Hidrogeologia

Conceitos, métodos e aplicações para o saneamento ambiental

Curso de Saneamento Ambiental

Equipe de Hidrogeologia

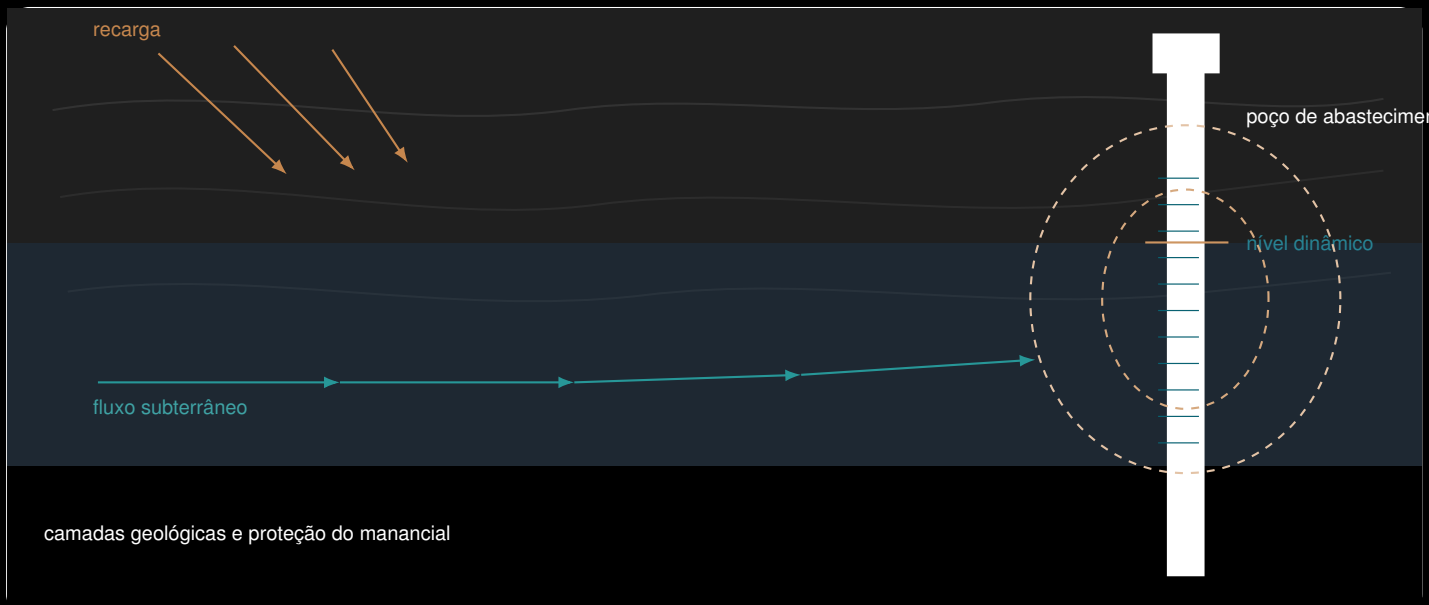

Sumário

1 Fundamentos da água subterrânea **1**
1.1 Introdução 1
1.2 Objetivos de aprendizagem 1
1.3 Meio geológico e água subterrânea 2
1.4 Porosidade 2
1.4.1 Definição e expressão matemática 2
1.4.2 Porosidade total e porosidade efetiva 2
1.4.3 Índice de vazios 3
1.4.4 Rendimento específico e retenção específica 3
1.4.5 Porosidade primária e secundária 3
1.4.6 Fatores que controlam a porosidade 4
1.4.7 Valores típicos de porosidade 4
1.5 Permeabilidade e condutividade hidráulica 4
1.5.1 Conceitos fundamentais 4
1.5.2 Conectividade, tortuosidade e anisotropia 5
1.5.3 Valores típicos de condutividade hidráulica 6
1.6 Tipos de aquíferos 6
1.6.1 Conceitos elementares 6
1.6.2 Aquífero livre 7
1.6.3 Aquífero confinado 7
1.6.4 Aquífero semiconfinado 7
1.6.5 Comparação entre os tipos de aquíferos 8
1.7 Lei de Darcy e escoamento em meios porosos 9
1.7.1 Carga hidráulica e gradiente hidráulico 9
1.7.2 Forma matemática da Lei de Darcy 9
1.7.3 Velocidade de Darcy e velocidade real 10
1.7.4 Transmissividade 10
1.7.5 Hipóteses e limites de validade 10
1.8 Aplicações para o saneamento ambiental 11
1.9 Exemplo resolvido 11
1.10 Resumo do capítulo 13

1.11 Exercícios 13
1.12 Gabarito comentado 15
1.13 Conexão com o próximo capítulo 17

2 Recarga de aquíferos, zonas de proteção e legislação 18
2.1 Introdução 18
2.2 Objetivos de aprendizagem 18
2.3 Conceitos fundamentais 19
2.3.1 Zona não saturada e zona saturada 19
2.4 Tipos de recarga 19
2.4.1 Recarga difusa 20
2.4.2 Recarga concentrada 20
2.4.3 Recarga induzida 20
2.4.4 Recarga artificial 20
2.5 Balanço hídrico e recarga 20
2.5.1 Fatores que controlam a recarga 21
2.5.2 Métodos básicos de estimativa 21
2.6 Exemplo resolvido 23
2.7 Zonas de proteção hidrogeológica 23
2.7.1 Faixas conceituais de proteção 23
2.7.2 Esquema conceitual 24
2.7.3 Aplicação prática 24
2.8 Proteção de mananciais subterrâneos: legislação 25
2.8.1 Princípios gerais 25
2.8.2 Instrumentos legais mais relevantes 25
2.8.3 Outorga e controle de uso 25
2.8.4 Proteção sanitária e ambiental 25
2.8.5 Relação entre legislação e hidrogeologia 26
2.9 Recarga, proteção e saneamento ambiental 27
2.10 Exemplo resolvido 27
2.11 Resumo do capítulo 28
2.12 Exercícios 28
2.13 Gabarito comentado 30
2.14 Conexão com o próximo capítulo 33

3 Poços de abastecimento e ensaios de bombeamento 34
3.1 Introdução 34
3.2 Objetivos de aprendizagem 34
3.3 Poços de abastecimento no saneamento ambiental 35
3.4 Tipos de poços 35

3.4.1 Poços escavados . . . 35
3.4.2 Poços tubulares . . . 36
3.4.3 Captações especiais . . . 36
3.5 Etapas do projeto de um poço . . . 36
3.5.1 Critérios de locação . . . 37
3.6 Elementos construtivos de um poço tubular . . . 37
3.6.1 Esquema construtivo . . . 38
3.7 Nível estático, nível dinâmico e rebaixamento . . . 38
3.7.1 Capacidade específica . . . 39
3.8 Dimensionamento hidráulico . . . 39
3.8.1 Vazão de projeto . . . 39
3.8.2 Altura manométrica total . . . 39
3.9 Ensaios de bombeamento . . . 40
3.9.1 Finalidades principais . . . 40
3.9.2 Tipos de ensaio . . . 41
3.9.3 Ensaio escalonado . . . 41
3.9.4 Ensaio de vazão constante . . . 42
3.9.5 Método de Theis . . . 42
3.9.6 Aproximação de Cooper-Jacob . . . 42
3.9.7 Ensaio de recuperação . . . 43
3.10 Interpretação hidráulica . . . 43
3.10.1 Parâmetros derivados . . . 44
3.11 Exemplo resolvido . . . 44
3.12 Proteção sanitária e operação . . . 45
3.12.1 Medidas fundamentais . . . 45
3.12.2 Problemas operacionais comuns . . . 46
3.13 Resumo do capítulo . . . 46
3.14 Exercícios . . . 47
3.15 Gabarito comentado . . . 48
3.16 Conexão com o próximo capítulo . . . 51

4 Vulnerabilidade e contaminação de aquíferos 52
4.1 Introdução . . . 52
4.2 Objetivos de aprendizagem . . . 52
4.3 Conceitos fundamentais . . . 53
4.3.1 Vulnerabilidade intrínseca e específica . . . 53
4.4 Fontes de contaminação . . . 54
4.5 Mecanismos de transporte de contaminantes . . . 54
4.5.1 Advecção . . . 55

4.5.2 Dispersão 55
4.5.3 Difusão 55
4.5.4 Soração e retardação 55
4.5.5 Degradação e atenuação natural 56
4.6 Plumas de contaminação 56
4.7 Vulnerabilidade natural dos aquíferos 57
4.8 Métodos de avaliação da vulnerabilidade 58
4.8.1 Abordagem conceitual 58
4.8.2 Índices de vulnerabilidade 58
4.8.3 Vulnerabilidade e risco 59
4.9 Monitoramento hidroquímico e sanitário 59
4.9.1 Objetivos do monitoramento 59
4.9.2 Parâmetros frequentemente acompanhados 59
4.9.3 Rede de monitoramento 60
4.10 Prevenção e remediação 60
4.10.1 Prevenção 60
4.10.2 Remediação 61
4.11 Exemplo resolvido 61
4.12 Resumo do capítulo 62
4.13 Exercícios 63
4.14 Gabarito comentado 64
4.15 Conexão com o próximo capítulo 68

5 Sistemas aquíferos do Brasil 69
5.1 Introdução 69
5.2 Objetivos de aprendizagem 69
5.3 Panorama hidrogeológico do Brasil 70
5.3.1 Principais províncias hidrogeológicas 70
5.4 Sistema Aquífero Guarani 71
5.4.1 Contexto geológico 71
5.4.2 Extensão e caráter transfronteiriço 71
5.4.3 Recarga e circulação 72
5.4.4 Uso para abastecimento 72
5.4.5 Desafios de gestão 72
5.5 Outros sistemas aquíferos relevantes do Brasil 73
5.5.1 Aquífero Alter do Chão 74
5.5.2 Aquífero Urucuia 74
5.5.3 Sistema Bauru–Caiuá 74
5.5.4 Sistema Barreiras 74

5.5.5 Aquíferos cársticos carbonáticos . . . 75
5.5.6 Aquíferos fissurais do embasamento cristalino . . . 75
5.5.7 Aquíferos associados a basaltos da Serra Geral . . . 75
5.6 Comparação entre sistemas aquíferos . . . 76
5.7 Sistemas aquíferos e abastecimento público . . . 76
5.8 Desafios de gestão no Brasil . . . 77
5.9 Exemplo resolvido . . . 77
5.10 Resumo do capítulo . . . 78
5.11 Exercícios . . . 79
5.12 Gabarito comentado . . . 81
5.13 Conexão com os apêndices . . . 84

A Unidades, símbolos e conversões fundamentais 85
A.1 Finalidade deste apêndice . . . 85
A.2 Símbolos e grandezas mais usados . . . 85
A.3 Conversões práticas de uso frequente . . . 85
A.4 Conversões de temperatura e viscosidade . . . 85

B Fórmulas fundamentais da hidrogeologia 88
B.1 Finalidade deste apêndice . . . 88
B.2 Geometria do meio poroso . . . 88
B.2.1 Porosidade . . . 88
B.2.2 Índice de vazios . . . 88
B.2.3 Rendimento específico e retenção específica . . . 88
B.3 Carga hidráulica e fluxo subterrâneo . . . 89
B.3.1 Carga hidráulica . . . 89
B.3.2 Gradiente hidráulico . . . 89
B.3.3 Lei de Darcy . . . 89
B.3.4 Descarga específica . . . 89
B.3.5 Velocidade intersticial média . . . 89
B.3.6 Transmissividade . . . 89
B.3.7 Relação entre condutividade hidráulica e permeabilidade intrínseca . 90
B.4 Aquíferos e armazenamento . . . 90
B.4.1 Armazenabilidade . . . 90
B.4.2 Armazenamento específico . . . 90
B.5 Recarga e balanço hídrico . . . 90
B.5.1 Balanço hídrico simplificado . . . 90
B.5.2 Coeficiente de recarga . . . 91
B.5.3 Recarga por flutuação do nível freático . . . 91
B.6 Poços e dimensionamento . . . 91

B.6.1 Rebaixamento 91
B.6.2 Capacidade específica 91
B.6.3 Altura manométrica total 91
B.6.4 Potência hidráulica 91
B.6.5 Potência no eixo 91
B.7 Ensaios de bombeamento 92
B.7.1 Solução de Theis 92
B.7.2 Aproximação de Cooper-Jacob 92
B.7.3 Estimativa de armazenabilidade por intercepto 92
B.7.4 Ensaio escalonado 92
B.7.5 Eficiência de poço 92
B.8 Contaminação e transporte 92
B.8.1 Velocidade do contaminante conservativo 93
B.8.2 Fator de retardação 93
B.8.3 Velocidade do contaminante sorvido 93
B.9 Observações de uso 93

C Valores típicos de parâmetros hidrogeológicos 94
C.1 Finalidade deste apêndice 94
C.2 Materiais geológicos e propriedades típicas 94
C.3 Valores típicos de parâmetros de aquíferos 94
C.4 Valores orientativos de transmissividade 94
C.5 Indicadores de qualidade da água subterrânea 94
C.6 Leitura prática dos valores 94

D Glossário técnico 98
D.1 Finalidade deste apêndice 98
D.2 Observação final 101

E Checklist de campo, projeto e operação 102
E.1 Finalidade deste apêndice 102
E.2 Checklist para seleção de área 102
E.2.1 Antes da perfuração 102
E.3 Checklist para projeto do poço 102
E.3.1 Concepção e dimensionamento 102
E.4 Checklist para construção 103
E.4.1 Durante a perfuração 103
E.5 Checklist para desenvolvimento e limpeza 103
E.5.1 Após a perfuração 103
E.6 Checklist para ensaio de bombeamento 103

E.6.1 Campo e medição 104
E.7 Checklist para operação 104
E.7.1 Rotina de abastecimento 104
E.8 Checklist de proteção sanitária 104
E.9 Checklist resumido para revisão final 105

Referências **106**
E.10 Básica 106
E.11 Complementar 106
E.12 Observação final 106

Lista de Figuras

1.1 Esquema comparativo dos principais tipos de aquíferos. 8

2.1 Esquema conceitual de recarga e zonas de proteção em torno de um poço. 24

3.1 Esquema simplificado de um poço tubular de abastecimento. 38

3.2 Esquema conceitual de curva de rebaixamento em um ensaio de vazão constante. 43

4.1 Esquema conceitual de migração de uma pluma de contaminação em direção a um poço. 57

5.1 Visão conceitual das principais categorias de sistemas aquíferos no Brasil. . 71

Lista de Tabelas

1.1 Valores típicos de porosidade em materiais geológicos 5
1.2 Valores típicos de condutividade hidráulica em materiais geológicos 6
1.3 Comparação entre aquíferos livres, confinados e semiconfinados 8

2.1 Fatores que controlam a recarga de aquíferos 21
2.2 Instrumentos legais e administrativos relacionados à proteção de mananciais subterrâneos 26

3.1 Elementos construtivos básicos de um poço tubular e suas funções 37
3.2 Tipos principais de ensaios de bombeamento e suas finalidades 41

4.1 Fontes comuns de contaminação e contaminantes associados 54
4.2 Exemplos de índices de vulnerabilidade e suas variáveis principais 58

5.1 Principais sistemas aquíferos do Brasil e suas características gerais 73
5.2 Comparação conceitual entre sistemas aquíferos brasileiros 76

A.1 Símbolos e grandezas hidrogeológicas mais frequentes 86
A.2 Conversões úteis em hidrogeologia 87

C.1 Valores típicos de porosidade e condutividade hidráulica em materiais geológicos 95
C.2 Parâmetros típicos de aquíferos segundo o tipo de confinamento 95
C.3 Ordens de grandeza de transmissividade para leitura preliminar 96
C.4 Indicadores comuns em monitoramento hidroquímico 96

1

Fundamentos da água subterrânea

1.1 Introdução

A água subterrânea é parte essencial do ciclo hidrológico e um recurso estratégico para o saneamento ambiental. Sua ocorrência, sua mobilidade e sua disponibilidade dependem da estrutura do meio geológico, da conectividade dos vazios e do regime hidráulico instalado no subsolo. Em escala prática, é isso que determina se uma formação rochosa pode armazenar água, transmiti-la com facilidade ou apenas retê-la de forma lenta e limitada.

Neste capítulo, são integrados os fundamentos físicos que sustentam a hidrogeologia: porosidade, permeabilidade, tipos de aquíferos e Lei de Darcy. Esses temas formam a base conceitual para todo o restante do livro, pois explicam como a água se distribui nos solos e nas rochas, como os sistemas aquíferos se organizam e como o fluxo subterrâneo pode ser descrito matematicamente.

1.2 Objetivos de aprendizagem

Ao final deste capítulo, o estudante deverá ser capaz de:

- definir porosidade total, porosidade efetiva, permeabilidade e condutividade hidráulica;
- distinguir armazenamento de água e transmissão de água no subsolo;
- reconhecer os principais tipos de porosidade em solos e rochas;
- classificar aquíferos livres, confinados e semiconfinados;
- interpretar carga hidráulica, gradiente hidráulico e vazão subterrânea;
- aplicar a Lei de Darcy em situações simples de fluxo em meios porosos;
- relacionar esses conceitos com a captação, a proteção e a gestão da água subterrânea.

1.3 Meio geológico e água subterrânea

A água subterrânea ocupa os vazios existentes em solos e rochas. Esses vazios podem estar entre os grãos minerais, ao longo de fraturas, em cavidades de dissolução ou em estruturas internas mais complexas. A quantidade de água armazenada depende do volume de vazios; a facilidade com que essa água circula depende da conexão entre eles.

Meio poroso

Chama-se *meio poroso* o conjunto de sólidos e vazios no qual a água pode ficar armazenada e, eventualmente, escoar. Em hidrogeologia, esse meio pode ser um solo, um sedimento inconsolidado, uma rocha fraturada ou uma formação carbonática com cavidades de dissolução.

Ideia central

Porosidade mede quanto espaço vazio existe. Permeabilidade mede quão bem esses espaços se conectam. Por isso, alta porosidade não significa, necessariamente, alta permeabilidade.

1.4 Porosidade

1.4.1 Definição e expressão matemática

A porosidade é a razão entre o volume de vazios e o volume total do material:

$$n = \frac{V_v}{V_t}$$

em que:

- n é a porosidade;
- V_v é o volume de vazios;
- V_t é o volume total da amostra.

Quando expressa em percentual, a porosidade é dada por:

$$n(\%) = \frac{V_v}{V_t} \times 100$$

1.4.2 Porosidade total e porosidade efetiva

A **porosidade total** considera todo o volume vazio do material, independentemente de sua conectividade. Já a **porosidade efetiva** corresponde apenas aos vazios interligados, capazes de participar do escoamento da água.

Porosidade efetiva

A porosidade efetiva é a fração do volume total formada por poros conectados entre si e aptos a conduzir água sob ação de um gradiente hidráulico.

Essa diferença é decisiva. Um material pode ter muitos vazios, mas se eles estiverem isolados ou pouco conectados, o fluxo será reduzido.

1.4.3 Índice de vazios

Outra grandeza útil é o índice de vazios e, definido por:

$$e = \frac{V_v}{V_s}$$

em que V_s é o volume dos sólidos. A relação entre porosidade e índice de vazios é:

$$n = \frac{e}{1+e} \qquad \text{e} \qquad e = \frac{n}{1-n}$$

1.4.4 Rendimento específico e retenção específica

Em aquíferos livres, nem toda a água armazenada é liberada por gravidade. Parte permanece retida por forças capilares e de adsorção. Por isso, distinguem-se:

$$S_y = \frac{\text{volume de água liberado por gravidade}}{\text{volume total}}$$

$$S_r = \frac{\text{volume de água retido}}{\text{volume total}}$$

Em primeira aproximação, em um meio saturado:

$$n \approx S_y + S_r$$

Leitura hidrogeológica

Solos arenosos tendem a apresentar maior rendimento específico que argilas. As argilas podem ter porosidade total elevada, mas retêm grande parte da água e liberam pouco volume útil ao fluxo.

1.4.5 Porosidade primária e secundária

A porosidade pode ser classificada segundo sua origem.

- **Porosidade primária**: adquirida durante a formação do material, como nos sedimentos deposicionais.

- **Porosidade secundária**: formada após a litificação, por fraturamento, dissolução, alteração química ou deformação tectônica.

Exemplos:

- areias e cascalhos aluviais;
- arenitos pouco cimentados;
- rochas cristalinas fraturadas;
- calcários carstificados com condutos de dissolução.

1.4.6 Fatores que controlam a porosidade

A porosidade depende de vários fatores:

- **granulometria**: grãos maiores tendem a gerar vazios maiores;
- **seleção granulométrica**: sedimentos bem selecionados costumam apresentar porosidade mais uniforme;
- **empacotamento**: arranjos compactos reduzem o espaço vazio;
- **forma dos grãos**: grãos angulosos podem criar vazios menores e mais irregulares;
- **compactação**: o peso das camadas superiores reduz os vazios ao longo do tempo;
- **cimentação**: a precipitação de minerais nos poros diminui a porosidade;
- **fraturamento e dissolução**: processos que criam porosidade secundária.

1.4.7 Valores típicos de porosidade

Mensagem-chave

A porosidade indica a capacidade de armazenar água. Ela não informa, por si só, a capacidade de transmitir água.

1.5 Permeabilidade e condutividade hidráulica

1.5.1 Conceitos fundamentais

A permeabilidade expressa a facilidade com que um fluido atravessa um meio poroso. Em hidrogeologia, é comum distinguir:

- **permeabilidade intrínseca**: depende apenas da geometria e da conectividade dos vazios;

Tabela 1.1: Valores típicos de porosidade em materiais geológicos

Material	Porosidade total típica	Observação
Argila	40 % a 70 %	alta porosidade total, porém vazios muito finos e pouco conectados
Silte	35 % a 50 %	porosidade intermediária, com conectividade variável
Areia fina	25 % a 40 %	boa combinação entre armazenamento e conectividade
Areia grossa e cascalho	20 % a 35 %	porosidade moderada, mas alta eficiência de fluxo
Rocha fraturada	muito variável	depende da abertura e da continuidade das fraturas
Calcário carstificado	muito variável	controlado por condutos de dissolução e cavidades

- **condutividade hidráulica**: depende do meio e das propriedades do fluido.

Condutividade hidráulica

A condutividade hidráulica é a propriedade do meio saturado que expressa a facilidade de passagem da água sob um gradiente hidráulico.

A relação entre condutividade hidráulica K e permeabilidade intrínseca k é:

$$K = \frac{k\rho g}{\mu}$$

ou, de forma equivalente,

$$k = \frac{K\mu}{\rho g}$$

em que:

- K é a condutividade hidráulica;
- k é a permeabilidade intrínseca;
- ρ é a densidade da água;
- g é a aceleração da gravidade;
- μ é a viscosidade dinâmica.

1.5.2 Conectividade, tortuosidade e anisotropia

A permeabilidade é influenciada por:

- **conectividade**: vazios bem conectados favorecem o fluxo;
- **tortuosidade**: trajetórias mais sinuosas aumentam a resistência;
- **anisotropia**: o meio pode conduzir melhor em uma direção do que em outra.

Em sedimentos estratificados, o fluxo horizontal costuma ser mais fácil que o vertical. Em rochas fraturadas, a direção das fraturas pode dominar o escoamento.

1.5.3 Valores típicos de condutividade hidráulica

Tabela 1.2: Valores típicos de condutividade hidráulica em materiais geológicos

Material	Condutividade hidráulica saturada típica	Comportamento hidráulico
Argila	de 10^{-12} a 10^{-9} m/s	muito baixa transmissividade
Silte	de 10^{-10} a 10^{-6} m/s	baixa a moderada transmissividade
Areia fina	de 10^{-6} a 10^{-4} m/s	boa transmissão de água
Areia grossa e cascalho	de 10^{-4} a 10^{-1} m/s	alta transmissividade
Rocha fraturada	muito variável	depende da abertura e da conexão das fraturas
Calcário carstificado	muito variável	pode ser muito elevada em condutos dissolvidos

Distinção essencial

Permeabilidade intrínseca descreve o meio. Condutividade hidráulica descreve o sistema meio–fluido.

1.6 Tipos de aquíferos

1.6.1 Conceitos elementares

Aquífero

Aquífero é uma formação geológica capaz de armazenar e transmitir água em quantidades significativas.

Aquitardo

Aquitardo é uma unidade de baixa permeabilidade que armazena água, mas a transmite lentamente.

Nota terminológica

O termo *aquiclude* é tradicionalmente usado para indicar uma unidade praticamente impermeável, mas poucos materiais são absolutamente impermeáveis. Na prática moderna, prefere-se o uso de aquitardo para materiais de baixa permeabilidade.

1.6.2 Aquífero livre

No aquífero livre, o limite superior da zona saturada é a superfície freática. A água pode infiltrar-se diretamente a partir da superfície, atravessando a zona não saturada até atingir a zona saturada.

Características principais:

- recarga direta e relativamente rápida;
- maior variação sazonal do nível d'água;
- armazenamento relacionado ao rendimento específico;
- maior vulnerabilidade à contaminação superficial.

1.6.3 Aquífero confinado

O aquífero confinado é limitado acima e abaixo por camadas de baixa permeabilidade. A água fica sob pressão superior à atmosférica e sobe no interior do poço até a superfície potenciométrica.

Características principais:

- pressão hidráulica elevada;
- armazenamento baixo, associado à compressibilidade;
- resposta mais amortecida às chuvas superficiais;
- proteção natural maior, embora não absoluta.

1.6.4 Aquífero semiconfinado

O aquífero semiconfinado possui uma camada de baixa permeabilidade que não é totalmente impermeável. Há vazamento vertical através dessa camada, o que torna o sistema intermediário entre o livre e o confinado.

Características principais:

- comportamento hidráulico intermediário;
- vazamento vertical através do aquitardo;
- amortecimento parcial do rebaixamento;

- possibilidade de conexão com camadas superiores ou inferiores.

Artesianismo

Um aquífero confinado ou semiconfinado pode apresentar condição artesiana quando a superfície potenciométrica sobe acima do teto do aquífero. Se ultrapassar a superfície do terreno, o poço pode ser jorrante.

1.6.5 Comparação entre os tipos de aquíferos

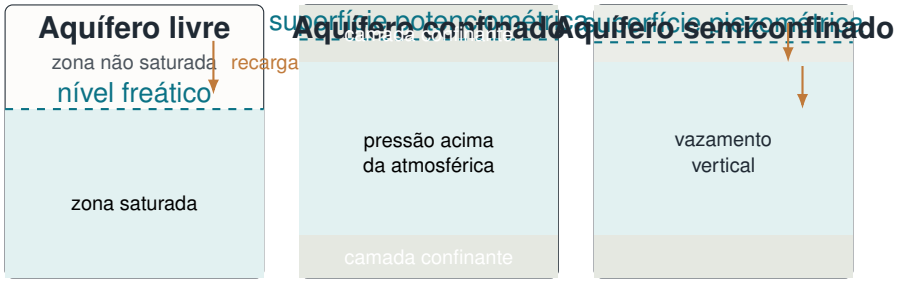

Figura 1.1: Esquema comparativo dos principais tipos de aquíferos.

A Tabela 1.3 resume as diferenças essenciais.

Tabela 1.3: Comparação entre aquíferos livres, confinados e semiconfinados

Critério	Aquífero livre	Aquífero confinado	Aquífero semiconfinado
Limite superior	superfície freática	camada confinante	camada semipermeável
Pressão da água	atmosférica na superfície freática	maior que a atmosférica	maior que a atmosférica, com vazamento
Armazenamento dominante	drenagem gravitacional	compressibilidade da água e da matriz	combinação de compressibilidade e vazamento
Resposta às chuvas	rápida a moderada	indireta e mais lenta	intermediária
Vulnerabilidade superficial	geralmente alta	geralmente menor	intermediária
Resposta ao bombeamento	rebaixamento com participação da zona não saturada	rebaixamento por compressão do sistema	rebaixamento amortecido por vazamento

Mensagem-chave

O tipo de aquífero controla a pressão da água, o armazenamento disponível, a resposta ao bombeamento e o grau de vulnerabilidade. Em outras palavras, ele define a dinâmica do sistema subterrâneo.

1.7 Lei de Darcy e escoamento em meios porosos

1.7.1 Carga hidráulica e gradiente hidráulico

A água subterrânea escoa das regiões de maior carga hidráulica para regiões de menor carga hidráulica. A carga hidráulica h pode ser expressa por:

$$h = z + \frac{p}{\gamma_w}$$

em que:

- z é a carga de elevação;
- p é a pressão da água;
- γ_w é o peso específico da água.

O gradiente hidráulico é a razão entre a diferença de carga e o comprimento do trajeto de fluxo:

$$i = \frac{\Delta h}{L} = \frac{h_1 - h_2}{L}$$

Quanto maior o gradiente, maior a tendência de escoamento.

1.7.2 Forma matemática da Lei de Darcy

Para escoamento unidimensional em meio poroso saturado, a Lei de Darcy é:

$$Q = -KA\frac{dh}{dl}$$

em que:

- Q é a vazão $(\mathrm{m}^3/\mathrm{s})$;
- K é a condutividade hidráulica (m/s);
- A é a área da seção transversal ao fluxo (m^2);
- $\frac{dh}{dl}$ é o gradiente hidráulico.

Em módulo, frequentemente usa-se:

$$Q = KAi$$

A descarga específica, ou vazão por unidade de área, é:

$$q = \frac{Q}{A} = Ki$$

Descarga específica

A descarga específica é a vazão dividida pela área total da seção transversal do meio poroso. Ela representa o fluxo médio aparente no meio.

1.7.3 Velocidade de Darcy e velocidade real

A descarga específica não é a velocidade real da água nos poros. A velocidade intersticial média é maior, pois a água circula apenas pelos vazios conectados. Se n_e for a porosidade efetiva, então:

$$v = \frac{q}{n_e} = \frac{Ki}{n_e}$$

Velocidade intersticial

A velocidade intersticial é a velocidade média da água ao longo dos caminhos efetivamente disponíveis dentro dos poros conectados.

1.7.4 Transmissividade

Quando a espessura saturada b é relevante, utiliza-se a transmissividade:

$$T = Kb$$

Ela expressa a capacidade integrada de uma unidade aquífera transmitir água ao longo de toda a sua espessura saturada.

1.7.5 Hipóteses e limites de validade

A Lei de Darcy é mais adequada quando:

- o meio é saturado;
- o fluxo é laminar;
- o meio pode ser tratado como contínuo em escala representativa;
- a condutividade hidráulica é aproximadamente constante no trecho analisado.

A lei perde aderência quando há:

- fluxo turbulento em fraturas muito abertas ou condutos cársticos;
- forte não saturação;
- heterogeneidade extrema em pequena escala;
- variações hidráulicas não lineares.

Aplicação prática

A Lei de Darcy é um alicerce da hidrogeologia, mas não descreve todos os regimes de fluxo. Em sistemas cársticos e em grandes fraturas abertas, o comportamento pode se afastar bastante da hipótese de meio poroso contínuo.

1.8 Aplicações para o saneamento ambiental

Os conceitos apresentados neste capítulo têm consequências diretas sobre a gestão da água subterrânea:

- **localização de poços**: materiais mais permeáveis tendem a oferecer maiores vazões;
- **proteção sanitária**: meios muito permeáveis podem facilitar a migração de contaminantes;
- **recarga**: áreas com alta infiltração podem alimentar os aquíferos de modo significativo;
- **vulnerabilidade**: aquíferos livres geralmente são mais expostos à contaminação superficial;
- **operação**: o tipo de aquífero influencia rebaixamento, eficiência e custo energético;
- **controle territorial**: o uso do solo precisa considerar a geometria e a dinâmica do sistema subterrâneo.

Síntese técnica

Em saneamento ambiental, porosidade, permeabilidade, tipo de aquífero e Lei de Darcy não são conceitos isolados. Eles formam um único quadro explicativo da água subterrânea.

1.9 Exemplo resolvido

Do volume de vazios à vazão subterrânea

Considere uma amostra de solo com volume total $V_t = 250\,\text{cm}^3$ e volume de sólidos $V_s = 180\,\text{cm}^3$. Em seguida, considere um trecho de aquífero com condutividade hidráulica $K = 1{,}5 \times 10^{-4}\,\text{m/s}$, área de fluxo $A = 24\,\text{m}^2$, gradiente hidráulico $i = 0{,}03$ e porosidade efetiva $n_e = 0{,}25$. Calcule a porosidade e a vazão; depois estime a velocidade intersticial média.

1. Porosidade

Primeiro, calcula-se o volume de vazios:

$$V_v = V_t - V_s = 250 - 180 = 70\,\text{cm}^3$$

Logo, a porosidade é:

$$n = \frac{V_v}{V_t} = \frac{70}{250} = 0{,}28$$

Portanto, a porosidade é de 28 %.

2. Vazão pela Lei de Darcy

$$Q = KAi$$

Substituindo os valores:

$$Q = 1{,}5 \times 10^{-4} \times 24 \times 0{,}03$$

$$Q = 1{,}08 \times 10^{-4}\ \mathrm{m^3/s}$$

ou aproximadamente 0,108 L/s.

3. Descarga específica e velocidade intersticial

A descarga específica é:

$$q = Ki = 1{,}5 \times 10^{-4} \times 0{,}03 = 4{,}5 \times 10^{-6}\ \mathrm{m/s}$$

A velocidade intersticial média é:

$$v = \frac{q}{n_e} = \frac{4{,}5 \times 10^{-6}}{0{,}25} = 1{,}8 \times 10^{-5}\ \mathrm{m/s}$$

ou cerca de 1,56 m/d.

4. Transmissividade

Se a espessura saturada do aquífero for $b = 12$ m, então:

$$T = Kb = 1{,}5 \times 10^{-4} \times 12 = 1{,}8 \times 10^{-3}\ \mathrm{m^2/s}$$

Interpretação

O exemplo mostra que a porosidade informa a capacidade de armazenamento, enquanto a Lei de Darcy quantifica o fluxo. O meio pode armazenar água e, ao mesmo tempo, transmiti-la em intensidades muito diferentes, a depender da conectividade dos vazios e do gradiente hidráulico.

1.10 Resumo do capítulo

Resumo do capítulo

- A água subterrânea ocupa vazios presentes em solos e rochas.
- Porosidade mede o volume de vazios; porosidade efetiva mede a fração realmente conectada.
- Permeabilidade expressa a facilidade de transmissão de água pelo meio.
- Condutividade hidráulica depende do meio e do fluido; permeabilidade intrínseca depende apenas do meio.
- Aquíferos livres têm superfície freática e maior vulnerabilidade superficial.
- Aquíferos confinados estão sob pressão e tendem a ter melhor proteção natural.
- Aquíferos semiconfinados permitem vazamento vertical através de camadas semipermeáveis.
- A Lei de Darcy relaciona vazão, condutividade hidráulica, área e gradiente.
- A descarga específica não é a velocidade real da água; a velocidade intersticial é maior.
- A transmissividade integra condutividade hidráulica e espessura saturada.
- Esses conceitos sustentam o estudo de poços, recarga, proteção e contaminação.

1.11 Exercícios

Nível F — Fáceis

F1

Defina porosidade total e porosidade efetiva com suas próprias palavras.

F2

Explique por que uma argila pode ter porosidade elevada e, ainda assim, apresentar baixa permeabilidade.

F3

Diferencie aquífero livre, aquífero confinado e aquífero semiconfinado.

F4

Explique, em termos simples, o que a Lei de Darcy descreve.

Nível M — Médios

M1

Uma amostra de solo possui volume total de 150 cm^3 e volume de sólidos de 120 cm^3. Calcule a porosidade total.

M2

Em um trecho de 40 m, a carga hidráulica cai de 18 m para 16 m. Calcule o gradiente hidráulico.

M3

Um aquífero possui condutividade hidráulica $K = 2 \times 10^{-4}$ m/s, área de fluxo $A = 30\,m^2$ e gradiente hidráulico $i = 0{,}02$. Calcule a vazão Q.

M4

Um poço perfura uma camada arenosa entre duas camadas argilosas. A água sobe no interior do tubo acima do teto do aquífero, mas não alcança a superfície do terreno. Classifique o aquífero.

Nível D — Difíceis

D1

Compare dois materiais com porosidade semelhante: uma argila e uma areia fina. Explique por que o comportamento hidráulico é tão diferente entre eles e indique qual tende a ser mais favorável à explotação de água subterrânea.

D2

Explique por que a Lei de Darcy pode produzir resultados inadequados em um sistema cárstico ou em uma fratura muito aberta.

D3

Em um projeto de abastecimento público, um aquífero livre muito produtivo está situado em área urbanizada e pouco protegida. Discuta os riscos e explique por que a escolha do aquífero não pode ser baseada apenas na vazão potencial.

1.12 Gabarito comentado

Resposta ao exercício F1

A porosidade total considera todos os vazios presentes no material, conectados ou não. A porosidade efetiva considera apenas os vazios interligados, capazes de participar do fluxo de água.
Assim, a porosidade total mede armazenamento potencial, enquanto a porosidade efetiva mede a fração realmente útil para o escoamento.

Resposta ao exercício F2

A argila pode apresentar muitos vazios finos, o que eleva a porosidade total. Porém, esses vazios costumam ser muito pequenos, tortuosos e pouco conectados. Além disso, forças capilares e adsorção retêm a água.
Por isso, a transmissão de água é lenta, e a permeabilidade é baixa, mesmo quando a porosidade é alta.

Resposta ao exercício F3

O aquífero livre possui superfície freática e recarga direta a partir da superfície. O aquífero confinado está limitado por camadas de baixa permeabilidade e a água se encontra sob pressão. O aquífero semiconfinado também possui restrição vertical, mas com vazamento através da camada semipermeável.
Em resumo: livre é aberto à atmosfera; confinado é pressurizado; semiconfinado é intermediário.

Resposta ao exercício F4

A Lei de Darcy descreve o fluxo de água em meios porosos saturados como proporcional ao gradiente hidráulico e à condutividade do meio. Ela mostra que a água se move de regiões de maior carga hidráulica para regiões de menor carga hidráulica.
Em termos práticos, a lei permite estimar vazões subterrâneas e compreender o comportamento hidráulico do aquífero.

Resposta ao exercício M1

Primeiro, calcula-se o volume de vazios:

$$V_v = V_t - V_s = 150 - 120 = 30\,\text{cm}^3$$

Depois, a porosidade:

$$n = \frac{V_v}{V_t} = \frac{30}{150} = 0{,}20$$

Logo, a porosidade total é de 20 %.

Resposta ao exercício M2

O gradiente hidráulico é:

$$i = \frac{\Delta h}{L} = \frac{18 - 16}{40} = \frac{2}{40} = 0{,}05$$

Logo, o gradiente hidráulico é $0{,}05$, ou 5 %. Isso indica a inclinação energética responsável pelo escoamento.

Resposta ao exercício M3

Pela Lei de Darcy:

$$Q = KAi$$

Substituindo os valores:

$$Q = 2 \times 10^{-4} \times 30 \times 0{,}02$$

$$Q = 1{,}2 \times 10^{-4}\ \mathrm{m^3/s}$$

Portanto, a vazão é de $1{,}2 \times 10^{-4}$ m^3/s, ou aproximadamente 0,12 L/s. O valor é coerente com um meio relativamente permeável sob gradiente moderado.

Resposta ao exercício M4

Trata-se de um aquífero confinado com condição artesiana não jorrante. A água sobe acima do teto do aquífero porque o sistema está sob pressão, mas não alcança a superfície do terreno.

Se a água ultrapassasse o terreno, o poço seria jorrante.

Resposta ao exercício D1

A diferença central está na conectividade dos vazios. A argila pode ter alta porosidade total, mas seus poros são muito finos, tortuosos e pouco conectados, o que reduz drasticamente a permeabilidade. Já a areia fina, mesmo com porosidade semelhante ou até menor, costuma possuir poros mais interligados e caminhos mais eficientes para o fluxo.

Do ponto de vista da explotação, a areia fina tende a ser mais favorável, porque combina armazenamento razoável com transmissão mais eficiente da água. A argila retém água, mas a libera muito lentamente.

Resposta ao exercício D2

A Lei de Darcy foi formulada para fluxo laminar em meio poroso saturado e contínuo. Em sistemas cársticos ou em fraturas muito abertas, o fluxo pode ocorrer por condutos preferenciais, com velocidade elevada, distribuição heterogênea e até turbulência. Nesses casos, a relação linear entre vazão e gradiente pode deixar de representar adequadamente o sistema.

Por isso, a aplicação direta da lei pode subestimar ou superestimar o comportamento real. Modelos de conduto, fratura ou abordagens híbridas costumam ser mais adequados.

Resposta ao exercício D3

Um aquífero livre muito produtivo em área urbanizada pode ser tecnicamente atraente, mas também muito vulnerável. A recarga ocorre diretamente pela superfície, o que facilita a entrada de contaminantes provenientes de esgoto, combustíveis, resíduos e atividades urbanas. Além disso, a impermeabilização pode alterar a recarga natural e concentrar fluxos em pontos críticos.

A escolha do aquífero não pode se basear apenas na vazão potencial. É necessário avaliar qualidade da água, vulnerabilidade, uso e ocupação do solo, proteção sanitária e sustentabilidade no longo prazo. Um aquífero menos produtivo, mas mais protegido, pode ser uma opção mais segura para abastecimento público.

1.13 Conexão com o próximo capítulo

Do fundamento físico à proteção do aquífero

Neste capítulo, foram estabelecidas as bases físicas da água subterrânea: porosidade, permeabilidade, tipos de aquíferos e Lei de Darcy. No próximo capítulo, esses fundamentos serão usados para compreender como os aquíferos se recarregam, como podem ser protegidos e por que a delimitação de zonas de proteção e a legislação ambiental são indispensáveis ao saneamento ambiental.

2

Recarga de aquíferos, zonas de proteção e legislação

2.1 Introdução

A água subterrânea é renovada continuamente, embora de forma mais lenta e menos visível do que a água superficial. Essa renovação ocorre por meio da recarga dos aquíferos, isto é, pela parcela da água que atravessa o solo e a zona não saturada até alcançar a zona saturada. Sem recarga, o aquífero deixa de se comportar como um sistema dinâmico e passa a ser apenas uma reserva em esgotamento.

Em saneamento ambiental, o estudo da recarga é decisivo para a gestão sustentável da água subterrânea, para a proteção de poços e para o controle de contaminações. A área que alimenta um aquífero precisa ser compreendida e protegida, pois o que acontece na superfície repercute no subsolo. Ao mesmo tempo, a legislação brasileira estabelece instrumentos para organizar o uso, a proteção e a fiscalização dessas águas.

Este capítulo integra quatro dimensões complementares: a dinâmica da recarga, a definição de zonas de proteção, os critérios de proteção hidrogeológica e o arcabouço legal aplicável aos mananciais subterrâneos.

2.2 Objetivos de aprendizagem

Ao final deste capítulo, o estudante deverá ser capaz de:

- definir recarga de aquífero e distingui-la de infiltração e percolação;
- classificar a recarga em difusa, concentrada, induzida e artificial;
- reconhecer os principais fatores que controlam a recarga subterrânea;
- aplicar métodos básicos de estimativa de recarga em situações simples;
- compreender o conceito de zona de proteção e área de contribuição;
- relacionar recarga, vulnerabilidade e uso do solo;

- identificar os principais instrumentos legais associados à proteção de mananciais subterrâneos.

2.3 Conceitos fundamentais

Recarga de aquífero

Recarga é a fração da água que, após infiltrar-se na superfície ou chegar ao subsolo por outros caminhos, atravessa a zona não saturada e alcança a zona saturada, contribuindo para a reposição das reservas subterrâneas.

Infiltração

Infiltração é a entrada da água na superfície do solo.

Percolação

Percolação é o movimento descendente da água através dos poros e fraturas do solo e das rochas.

Sequência conceitual

A infiltração é o ingresso da água no solo; a percolação é o deslocamento em profundidade; a recarga é a chegada efetiva à zona saturada.

Nem toda água infiltrada se transforma em recarga. Parte é perdida por evapotranspiração, parte pode ser desviada lateralmente e parte pode permanecer temporariamente armazenada no solo. A recarga é, portanto, um resultado final e não apenas uma etapa intermediária do processo hidrológico.

2.3.1 Zona não saturada e zona saturada

A zona não saturada, também chamada de zona vadosa, localiza-se entre a superfície do terreno e o nível freático. Nela, os poros contêm água, ar e filmes capilares. A zona saturada, por sua vez, é a região em que todos os vazios estão preenchidos com água.

A recarga depende da capacidade da água atravessar a zona não saturada com perdas moderadas. Solos arenosos, fraturas abertas e superfícies pouco impermeabilizadas favorecem esse processo. Solos argilosos, camadas compactadas e pavimentos urbanos tendem a dificultá-lo.

2.4 Tipos de recarga

2.4.1 Recarga difusa

A recarga difusa ocorre de forma distribuída sobre grandes áreas, geralmente pela infiltração da chuva em superfícies permeáveis. É típica de áreas planas ou suavemente onduladas, com cobertura de solo favorável e baixa impermeabilização.

2.4.2 Recarga concentrada

A recarga concentrada ocorre em pontos ou faixas onde a água penetra com maior intensidade, como vales, depressões, dolinas, leitos de rios intermitentes, fraturas, falhas e áreas de dissolução em terrenos cársticos.

2.4.3 Recarga induzida

A recarga induzida ocorre quando o bombeamento reduz a carga hidráulica no aquífero e passa a atrair água de rios, lagos ou unidades vizinhas. Trata-se de uma forma de alimentação provocada pela exploração.

2.4.4 Recarga artificial

A recarga artificial é aquela produzida intencionalmente por obras de engenharia, como bacias de infiltração, poços de recarga, trincheiras, valas e sistemas de recarga gerenciada.

Uso do solo

Impermeabilização urbana, compactação do solo, desmatamento e manejo agrícola inadequado podem reduzir a recarga natural. Por outro lado, práticas conservacionistas podem preservá-la ou até ampliá-la.

2.5 Balanço hídrico e recarga

A recarga pode ser estimada de forma simples por meio de um balanço hídrico.

$$P = ET + Q_s + R + \Delta S$$

em que:

- P é a precipitação;
- ET é a evapotranspiração;
- Q_s é o escoamento superficial;
- R é a recarga subterrânea;
- ΔS é a variação de armazenamento.

Reorganizando:

$$R = P - ET - Q_s - \Delta S$$

Em períodos longos, quando ΔS é pequeno, pode-se adotar aproximadamente:

$$R \approx P - ET - Q_s$$

Coeficiente de recarga

O coeficiente de recarga é a fração da precipitação que se transforma em recarga:

$$C_R = \frac{R}{P}$$

2.5.1 Fatores que controlam a recarga

Tabela 2.1: Fatores que controlam a recarga de aquíferos

Fator	Efeito sobre a recarga	Observação
Precipitação	Aumenta o potencial de recarga	A distribuição temporal é tão importante quanto o total anual
Evapotranspiração	Reduz a água disponível para infiltração profunda	É maior em climas quentes e com vegetação densa
Tipo de solo	Solos arenosos favorecem a infiltração; argilosos a restringem	A textura controla a velocidade de percolação
Topografia	Encostas íngremes favorecem escoamento; áreas planas favorecem infiltração	O relevo altera o tempo de permanência da água na superfície
Geologia	Fraturas, falhas e rochas porosas podem aumentar a recarga	A estrutura do meio cria caminhos preferenciais
Uso do solo	A impermeabilização urbana reduz a recarga	É um dos fatores mais sensíveis à ação humana
Cobertura vegetal	Pode reduzir o escoamento superficial e favorecer infiltração gradual	O efeito depende do sistema solo–vegetação

2.5.2 Métodos básicos de estimativa

A recarga pode ser estimada por diferentes métodos. A escolha depende da escala do estudo, da disponibilidade de dados e do tipo de aquífero.

Método do balanço hídrico

É um dos procedimentos mais usados em estudos regionais. A recarga é obtida a partir das entradas e saídas de água em uma área.

Método da flutuação do nível freático

Em aquíferos livres, a elevação do nível freático após um evento de recarga pode ser convertida em recarga equivalente. Uma forma simplificada é:

$$r = S_y \Delta h$$

em que:

- r é a recarga equivalente em altura de água;
- S_y é o rendimento específico;
- Δh é a elevação do nível freático.

O volume recarregado em uma área A é dado por:

$$V_R = rA = S_y \Delta h A$$

Método do cloreto

O cloreto pode ser usado como traçador conservativo em alguns contextos. Em formulação simplificada:

$$R = P \frac{C_P}{C_G}$$

em que:

- C_P é a concentração de cloreto na precipitação;
- C_G é a concentração de cloreto na água subterrânea.

Esse método exige cautela, pois fontes antrópicas de cloreto podem distorcer a estimativa.

Escolha metodológica

Não existe um único método universalmente superior. O ideal é integrar observações de campo, dados hidrológicos, piezometria e, quando possível, técnicas geoquímicas e modelagem.

2.6 Exemplo resolvido

Estimativa de recarga por balanço hídrico

Considere uma área de recarga de 12 km^2. Em um ano hidrológico, a precipitação total foi de 1 500 mm, a evapotranspiração foi de 980 mm e o escoamento superficial foi de 260 mm. Admita variação de armazenamento desprezível.

1. Cálculo da recarga em altura

$$R = P - ET - Q_s$$

$$R = 1500 - 980 - 260 = 260\,\text{mm}$$

Logo, a recarga anual equivalente é de 260 mm, ou 0,26 m.

2. Cálculo do volume

$$V_R = R \cdot A = 0{,}26 \times 12 \times 10^6$$

$$V_R = 3{,}12 \times 10^6\ \text{m}^3$$

Portanto, o volume anual recarregado é de aproximadamente 3,12 × 10^6 m^3.

Interpretação

O resultado mostra que, mesmo em uma área relativamente pequena, a recarga pode representar volume significativo de água subterrânea. Esse tipo de estimativa é útil para planejamento de uso e proteção do aquífero.

2.7 Zonas de proteção hidrogeológica

A recarga e a proteção de aquíferos estão intimamente ligadas. A mesma área que alimenta o aquífero pode também ser uma via de entrada para contaminantes. Por isso, a delimitação de zonas de proteção é uma medida essencial de gestão.

Zona de proteção

Zona de proteção é a área na qual se impõem restrições de uso e ocupação do solo com o objetivo de resguardar a qualidade e a disponibilidade da água subterrânea captada ou em recarga.

2.7.1 Faixas conceituais de proteção

Em termos conceituais, podem ser distinguidas três faixas principais:

- **zona imediata**: entorno direto do poço, com controle sanitário rigoroso;
- **zona intermediária**: área de influência de médio prazo, com restrições relevantes ao uso do solo;
- **zona de contribuição**: área mais ampla que alimenta hidraulicamente o poço ou o sistema de captação.

Critério técnico

A delimitação real dessas zonas depende da direção do fluxo, da velocidade da água, da vazão bombeada, da permeabilidade do meio e do tempo de trânsito dos contaminantes.

2.7.2 Esquema conceitual

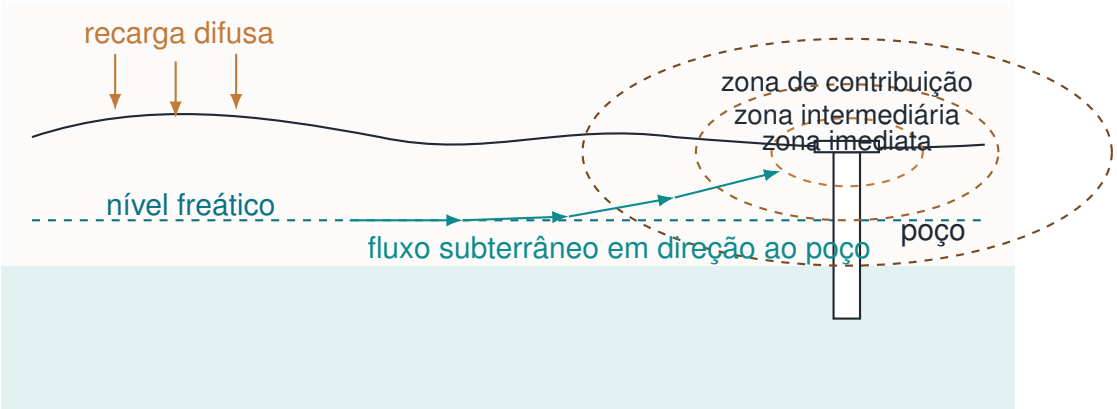

Figura 2.1: Esquema conceitual de recarga e zonas de proteção em torno de um poço.

2.7.3 Aplicação prática

A proteção de uma captação não deve ser definida apenas por um raio fixo e arbitrário. O ideal é considerar:

- direção do fluxo subterrâneo;
- velocidade de avanço de contaminantes;
- taxa de bombeamento;
- vulnerabilidade natural do aquífero;
- tempo de trânsito até o poço;
- presença de fraturas, falhas e heterogeneidades;
- uso e ocupação do solo na área de contribuição.

Proteção e gestão territorial

Proteger um aquífero é também intervir no uso do território. A água subterrânea responde às atividades da superfície, mesmo quando essa resposta não é imediata.

2.8 Proteção de mananciais subterrâneos: legislação

No Brasil, a proteção das águas subterrâneas está inserida em um sistema jurídico que combina princípios constitucionais, legislação federal, normas estaduais, regulamentações de órgãos gestores e exigências de licenciamento ambiental e sanitário.

2.8.1 Princípios gerais

A gestão das águas no Brasil é descentralizada e integrada por bacia hidrográfica. A água subterrânea não está fora desse sistema: ela é parte do ciclo hidrológico e deve ser tratada como recurso público sujeito a planejamento, controle e fiscalização.

- o uso da água depende de regras administrativas e técnicas;
- a proteção do manancial não se limita ao poço, mas inclui sua área de contribuição;
- a qualidade da água deve ser monitorada em função do uso pretendido;
- atividades potencialmente poluidoras podem ser limitadas por critérios sanitários e ambientais.

2.8.2 Instrumentos legais mais relevantes

2.8.3 Outorga e controle de uso

A outorga é o ato administrativo que autoriza o uso do recurso hídrico em condições definidas pelo órgão competente. Para águas subterrâneas, isso inclui a perfuração, a captação e, em certos casos, a interferência sobre outros usos.

Importância da outorga

A outorga não é mera formalidade. Ela é o instrumento que permite compatibilizar demanda, disponibilidade, proteção do aquífero e conflitos entre usuários.

2.8.4 Proteção sanitária e ambiental

A legislação e os regulamentos técnicos normalmente exigem:

- vedação adequada do poço;
- laje sanitária ou dispositivo equivalente;

Tabela 2.2: Instrumentos legais e administrativos relacionados à proteção de mananciais subterrâneos

Instrumento	Função principal	Relevância para aquíferos
Lei n. 9.433/1997	Institui a Política Nacional de Recursos Hídricos	estabelece outorga, cobrança, enquadramento e gestão integrada
Normas estaduais de recursos hídricos	Regulam o uso da água em cada unidade da federação	disciplinam perfuração, explotação, monitoramento e restrições locais
Licenciamento ambiental	Avalia impactos de atividades e empreendimentos	pode impor condicionantes para proteção de poços e áreas de recarga
Normas sanitárias de potabilidade	Definem os padrões de qualidade da água para consumo humano	orientam monitoramento, tratamento e controle operacional
Normas de proteção sanitária de poços	Regulam construção, vedação e perímetros de proteção	reduzem risco de entrada de contaminantes
Legislação ambiental sobre poluição e crimes ambientais	Responsabiliza por contaminação e degradação	fundamenta prevenção, reparação e sanções

- afastamento de fontes de contaminação;
- controle da ocupação nas áreas de recarga;
- monitoramento da qualidade da água;
- manutenção e inspeção periódica da captação.

Proteção de manancial

A proteção do manancial subterrâneo não se resume à boca do poço. Ela inclui o entorno imediato, a área de recarga e o uso do solo em toda a área que contribui para a captação.

2.8.5 Relação entre legislação e hidrogeologia

A legislação é mais eficaz quando está apoiada em diagnóstico hidrogeológico consistente. Sem conhecer a direção do fluxo, a vulnerabilidade e a recarga, a delimitação de áreas protegidas pode ser inadequada.

- Um aquífero livre em área urbana exige controles mais rígidos.
- Um aquífero confinado pode demandar proteção da integridade dos poços e das zonas de recarga.
- Um aquífero semiconfinado requer atenção especial ao vazamento vertical e às conexões entre camadas.

Mensagem central

A legislação fornece instrumentos de gestão; a hidrogeologia fornece o diagnóstico físico que torna esses instrumentos tecnicamente aplicáveis.

2.9 Recarga, proteção e saneamento ambiental

Em áreas urbanas, a impermeabilização do solo reduz a recarga difusa e pode concentrar fluxos em pontos vulneráveis. Em áreas rurais, a recarga pode ser maior, mas o risco de contaminação difusa por fertilizantes, agrotóxicos e dejetos animais exige vigilância.

- Em áreas urbanas: priorizam-se controle de vazamentos, proteção de poços e drenagem sustentável.
- Em áreas rurais: priorizam-se manejo do solo, proteção contra contaminantes difusos e controle de fontes pontuais.

Integração com o saneamento

A proteção dos aquíferos é parte do saneamento ambiental porque influencia diretamente a segurança hídrica, a qualidade da água e a saúde coletiva.

2.10 Exemplo resolvido

Recarga e delimitação simplificada de proteção

Considere uma área urbana de 8 km^2 sobre um aquífero livre. Em um ano, a precipitação foi de 1 450 mm, a evapotranspiração de 920 mm e o escoamento superficial de 280 mm. Um poço de abastecimento capta água dessa unidade e apresenta rendimento específico $S_y = 0{,}14$. Após um evento chuvoso, o nível freático elevou-se 0,40 m.

1. Estimativa da recarga anual

$$R = P - ET - Q_s$$

$$R = 1450 - 920 - 280 = 250\,\text{mm}$$

A recarga anual equivalente é de 250 mm, ou 0,25 m.

O volume recarregado é:

$$V_R = 0{,}25 \times 8 \times 10^6 = 2{,}0 \times 10^6\,\text{m}^3$$

2. Estimativa pela flutuação do nível freático

$$r = S_y \Delta h$$

$$r = 0{,}14 \times 0{,}40 = 0{,}056\ \text{m}$$

Logo, a recarga associada ao evento é de 56 mm.

3. Interpretação

Os valores não precisam coincidir exatamente, pois os métodos representam escalas e hipóteses distintas. O balanço hídrico estima a recarga anual média, enquanto a flutuação do nível freático reflete um evento pontual e local. Em ambos os casos, a área deve ser tratada como zona sensível de proteção, especialmente se houver poços, ocupação urbana e risco de contaminação superficial.

2.11 Resumo do capítulo

Resumo do capítulo

- Recarga é a água que efetivamente alcança a zona saturada e alimenta o aquífero.
- Infiltração, percolação e recarga são processos relacionados, mas não equivalentes.
- A recarga pode ser difusa, concentrada, induzida ou artificial.
- O balanço hídrico e a flutuação do nível freático são métodos úteis de estimativa.
- O coeficiente de recarga expressa a fração da precipitação que entra no aquífero.
- Zonas de proteção organizam restrições de uso em torno de poços e áreas de contribuição.
- A delimitação dessas zonas depende da direção do fluxo, da vazão, da vulnerabilidade e do tempo de trânsito.
- A legislação brasileira fornece instrumentos como outorga, licenciamento, normas sanitárias e controle ambiental.
- A proteção de mananciais subterrâneos exige integração entre marco legal e diagnóstico hidrogeológico.

2.12 Exercícios

Nível F — Fáceis

F1

Defina recarga de aquífero e explique por que ela não é sinônimo de precipitação.

F2

Diferencie infiltração, percolação e recarga.

F3

Explique a diferença entre recarga difusa e recarga concentrada.

F4

Por que a delimitação de zonas de proteção é importante para poços de abastecimento?

Nível M — Médios

M1

Em uma área de 10 km^2, a precipitação anual é de 1 400 mm, a evapotranspiração é de 900 mm e o escoamento superficial é de 250 mm. Admitindo variação de armazenamento desprezível, estime a recarga anual em milímetros e em volume.

M2

Em um aquífero livre, o rendimento específico é $S_y = 0{,}18$ e o nível freático subiu 0,50 m após um período chuvoso. Estime a recarga equivalente em altura de água.

M3

Cite três fatores naturais e dois fatores antrópicos que influenciam a recarga de aquíferos.

M4

Explique a função da zona imediata, da zona intermediária e da zona de contribuição em torno de um poço.

Nível D — Difíceis

D1

Uma cidade expandiu sua área impermeabilizada sobre uma antiga zona de recarga. Após alguns anos, observou-se redução da recarga local e aumento da concentração de nitrato em poços rasos. Apresente uma explicação hidrogeológica para esse comportamento e proponha medidas de gestão.

D2

Um aquífero livre apresenta área de contribuição de 4 km^2, rendimento específico de $0{,}12$ e elevação do nível freático de 0,75 m em um evento de recarga. Determine o volume recarregado e comente os limites da estimativa.

D3

Explique por que a recarga induzida pode ser benéfica do ponto de vista da disponibilidade hídrica, mas representar risco sanitário se a qualidade da água superficial for ruim.

2.13 Gabarito comentado

Resposta ao exercício F1

Recarga de aquífero é a fração da água que alcança a zona saturada e passa a integrar o armazenamento subterrâneo. Ela não é sinônimo de precipitação porque parte da chuva é perdida por evapotranspiração, parte escoa superficialmente e parte fica retida temporariamente no solo.
Assim, a recarga é apenas o componente da água que efetivamente alimenta o aquífero.

Resposta ao exercício F2

Infiltração é a entrada da água no solo pela superfície. Percolação é o movimento da água para camadas mais profundas, através dos poros e fraturas. Recarga é o resultado final quando a água chega à zona saturada e abastece o aquífero.
Logo, infiltração e percolação são etapas do processo; recarga é o efeito hidrogeológico final.

Resposta ao exercício F3

Recarga difusa ocorre de forma espalhada sobre grandes áreas, geralmente pela infiltração da chuva. Recarga concentrada ocorre em pontos ou faixas específicas, como leitos de rios, fraturas, dolinas ou depressões, onde a água penetra com maior intensidade.
A difusa é mais distribuída; a concentrada é mais localizada e intensa.

Resposta ao exercício F4

As zonas de proteção são importantes porque restringem atividades capazes de contaminar o poço ou sua área de contribuição. Elas ajudam a evitar que efluentes, combustíveis, resíduos, fossas e outros agentes poluentes alcancem a água subterrânea.
Além disso, a definição dessas zonas orienta o uso do solo e reduz riscos sanitários para a população abastecida.

Resposta ao exercício M1

Pela equação simplificada:

$$R = P - ET - Q_s$$

$$R = 1400 - 900 - 250 = 250\,\text{mm}$$

A recarga anual é de 250 mm, ou 0,25 m.
O volume recarregado é:

$$V_R = 0{,}25 \times 10 \times 10^6 = 2{,}5 \times 10^6\,\text{m}^3$$

Logo, o volume anual de recarga é aproximadamente $2{,}5 \times 10^6\,\text{m}^3$. O resultado é coerente com uma área de recarga moderada.

Resposta ao exercício M2

A recarga equivalente é:

$$r = S_y \Delta h$$

Substituindo:

$$r = 0{,}18 \times 0{,}50 = 0{,}09\,\text{m}$$

Logo, a recarga equivalente é de 90 mm. Esse valor representa a água adicionada ao aquífero por unidade de área.

Resposta ao exercício M3

Exemplos de fatores naturais:

- precipitação;
- tipo de solo;
- topografia;
- geologia e fraturamento;
- cobertura vegetal.

Exemplos de fatores antrópicos:

- impermeabilização urbana;
- desmatamento ou manejo inadequado do solo;
- compactação por maquinário;

- práticas agrícolas intensivas.

O estudante poderia citar quaisquer três naturais e dois antrópicos, desde que justificasse sua influência sobre a infiltração e a percolação.

Resposta ao exercício M4

A zona imediata protege o poço e sua estrutura física contra contaminação direta e danos operacionais. A zona intermediária restringe atividades que possam introduzir contaminantes com tempo de trânsito curto ou médio. A zona de contribuição corresponde à área mais ampla que alimenta hidraulicamente o poço.
Em conjunto, essas zonas organizam o controle territorial e reduzem o risco de contaminação do sistema de captação.

Resposta ao exercício D1

A impermeabilização urbana reduz a infiltração direta da chuva, diminui a recarga e aumenta o escoamento superficial. Ao mesmo tempo, a urbanização pode concentrar fontes de nitrato, como vazamentos de esgoto, fossas e manejo inadequado de resíduos. Em áreas rasas e vulneráveis, o nitrato pode migrar com facilidade para a zona saturada.
Medidas de gestão:

- controle da impermeabilização e adoção de drenagem sustentável;
- proteção de áreas de recarga remanescentes;
- saneamento básico e controle de vazamentos;
- monitoramento da qualidade da água subterrânea;
- restrição de usos de alto risco em áreas vulneráveis.

O caso mostra que reduzir a recarga não significa reduzir o risco: a qualidade da água pode piorar se a área for mal gerida.

Resposta ao exercício D2

O volume recarregado é dado por:

$$V_R = S_y \Delta h A$$

Substituindo:

$$V_R = 0{,}12 \times 0{,}75 \times 4 \times 10^6$$

$$V_R = 3{,}6 \times 10^5 \text{ m}^3$$

Portanto, o volume recarregado é de $3{,}6 \times 10^5$ m^3.
Limites da estimativa:

- o método assume que a elevação do nível freático se deve apenas à recarga;
- ignora perdas laterais e drenagem simultânea;
- depende de um valor representativo de rendimento específico;
- pode ser afetado por heterogeneidade espacial do aquífero.

Logo, o cálculo é útil, mas deve ser interpretado como aproximação.

Resposta ao exercício D3

A recarga induzida ocorre quando o bombeamento reduz a carga hidráulica do aquífero e passa a atrair água de um rio, lago ou unidade adjacente. Isso pode ser benéfico porque aumenta a disponibilidade hídrica e pode sustentar maiores vazões de exploração. Entretanto, se a água superficial tiver qualidade ruim, a indução pode trazer contaminantes para o aquífero. Nesse caso, o bombeamento transforma a fonte superficial em rota de entrada de poluentes. Por isso, a recarga induzida exige monitoramento rigoroso da qualidade da água e análise hidrogeológica da área de influência.

2.14 Conexão com o próximo capítulo

Da recarga à captação

Neste capítulo, a água subterrânea foi analisada como um sistema em renovação, sujeito à recarga, à proteção territorial e à regulação legal. No próximo capítulo, o foco passará para a obra de captação: os poços de abastecimento e os ensaios de bombeamento. A partir daí, será possível transformar o conhecimento hidrogeológico em projeto, dimensionamento e avaliação operacional de sistemas reais de abastecimento.

3

Poços de abastecimento e ensaios de bombeamento

3.1 Introdução

Os poços de abastecimento representam a interface prática entre o aquífero e o sistema de uso da água. Eles permitem transformar a disponibilidade subterrânea em vazão efetiva para consumo humano, irrigação, atividades industriais e serviços urbanos. No entanto, um poço bem-sucedido não é apenas uma perfuração produtiva: ele precisa ser tecnicamente locado, construtivamente estável, hidraulicamente eficiente e sanitariamente protegido.

Em saneamento ambiental, o projeto e a avaliação de poços exigem uma leitura integrada do meio geológico, da demanda de água, da resposta hidráulica do aquífero e das condições de qualidade da água. O desempenho da captação não pode ser estimado apenas pela profundidade ou pela vazão instantânea. É necessário conhecer o rebaixamento, a eficiência construtiva, a interferência com o aquífero e a evolução temporal do sistema.

Os ensaios de bombeamento complementam o projeto do poço, pois revelam a resposta real do aquífero e permitem estimar parâmetros como transmissividade, armazenabilidade e capacidade específica. Este capítulo reúne, de forma integrada, os fundamentos do projeto, da construção, da operação e da interpretação hidráulica dos poços de abastecimento.

3.2 Objetivos de aprendizagem

Ao final deste capítulo, o estudante deverá ser capaz de:

- reconhecer os principais tipos de poços de abastecimento;
- identificar os elementos construtivos de um poço tubular;
- compreender os critérios básicos de locação e dimensionamento;
- interpretar nível estático, nível dinâmico, rebaixamento e capacidade específica;
- distinguir ensaio escalonado, ensaio de vazão constante e ensaio de recuperação;

- estimar parâmetros hidráulicos a partir de testes de bombeamento;
- avaliar a eficiência de poço e as perdas associadas à obra;
- relacionar projeto, operação e proteção sanitária de poços com saneamento ambiental.

3.3 Poços de abastecimento no saneamento ambiental

Um poço de abastecimento é uma obra de captação destinada a interceptar água subterrânea e disponibilizá-la para uso. Seu papel é estratégico, especialmente em regiões onde o abastecimento superficial é insuficiente, sazonalmente instável ou demasiadamente vulnerável.

Poço de abastecimento

Poço de abastecimento é a estrutura de captação destinada à retirada de água subterrânea em vazão compatível com a demanda, respeitando a capacidade do aquífero, a estabilidade construtiva e os requisitos sanitários.

Os poços podem atender desde pequenas comunidades rurais até grandes sistemas urbanos. Em todos os casos, a qualidade da obra depende da compatibilidade entre o poço e o aquífero explorado. Um aquífero livre granular, por exemplo, comporta-se de modo diferente de um aquífero confinado, de uma rocha fraturada ou de um sistema semiconfinado.

Ideia central

O poço não cria água. Ele apenas acessa e controla a água já existente no sistema subterrâneo. Por isso, seu projeto deve respeitar os limites hidráulicos do aquífero.

3.4 Tipos de poços

3.4.1 Poços escavados

Os poços escavados são obras de pequena a média profundidade, geralmente com diâmetro maior e construção manual ou semimecanizada. São comuns em aquíferos rasos e livres, onde o nível freático se encontra próximo à superfície.

Características principais:

- maior diâmetro;
- menor profundidade;
- maior exposição à contaminação superficial;
- menor controle hidráulico e construtivo;
- maior suscetibilidade a desmoronamentos e entrada de sedimentos.

3.4.2 Poços tubulares

Os poços tubulares são perfurados mecanicamente e podem atingir maiores profundidades. São os mais usuais em sistemas públicos e em captações privadas de médio e grande porte.

Características principais:

- menor diâmetro que os poços escavados;
- maior profundidade;
- possibilidade de captação em aquíferos livres, confinados e semiconfinados;
- melhor controle técnico;
- maior dependência de projeto, construção e manutenção adequados.

3.4.3 Captações especiais

Além dos poços convencionais, existem captações como drenos radiais, galerias de infiltração, poços de rebaixamento e sistemas mistos. Neste livro, o foco principal está nos poços tubulares de abastecimento, por serem os mais relevantes para a hidrogeologia aplicada ao saneamento ambiental.

3.5 Etapas do projeto de um poço

O projeto de um poço deve ser tratado como um processo técnico completo.

1. estudo preliminar da área;
2. seleção do aquífero alvo;
3. definição de profundidade, diâmetro e revestimento;
4. perfuração;
5. registro litológico e perfilagem;
6. desenvolvimento e limpeza;
7. teste de produção;
8. seleção e instalação da bomba;
9. proteção sanitária e operação contínua.

Sequência técnica

Erros na fase de locação e concepção raramente são compensados por obras posteriores. Em poços, a qualidade do estudo preliminar é decisiva.

3.5.1 Critérios de locação

A escolha do local deve considerar:

- espessura saturada do aquífero;
- condutividade hidráulica e transmissividade;
- profundidade do nível d'água;
- direção do fluxo subterrâneo;
- distância de fontes de contaminação;
- acesso para instalação, manutenção e proteção;
- possibilidade de delimitar a zona de proteção.

Zona de influência do poço

Zona de influência do poço é a área do aquífero cujas águas convergem para a captação durante a operação. Sua extensão depende da vazão bombeada, do tipo de aquífero, da condutividade hidráulica e do tempo de bombeamento.

3.6 Elementos construtivos de um poço tubular

Tabela 3.1: Elementos construtivos básicos de um poço tubular e suas funções

Elemento	Função principal	Observação técnica
Cabeçote	Protege a abertura superior do poço	Deve impedir a entrada de água superficial e de contaminantes
Revestimento	Sustenta as paredes da perfuração	Isola intervalos indesejáveis e evita desmoronamentos
Filtro	Permite entrada de água do aquífero	A abertura deve ser compatível com a granulometria da formação
Pré-filtro	Faz a transição entre formação e filtro	Reduz a entrada de finos e melhora a estabilidade hidráulica
Laje sanitária	Protege a boca do poço	Deve ter caimento para afastar águas superficiais
Bomba submersa	Eleva a água à superfície	A seleção depende da vazão e da altura manométrica
Tubulação de recalque	Conduz a água até o uso	Deve ter perdas de carga compatíveis com o sistema

3.6.1 Esquema construtivo

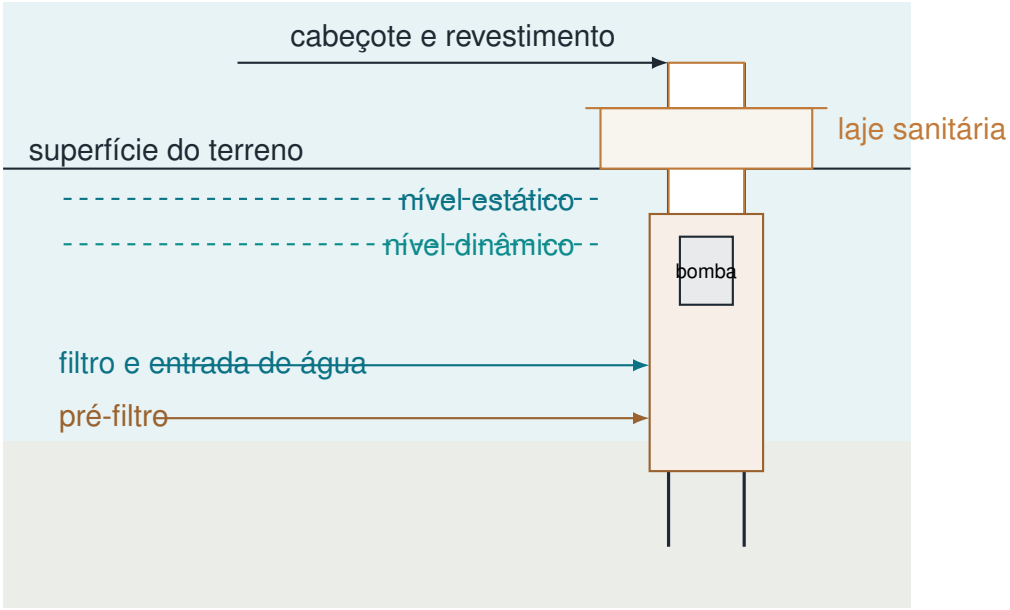

Figura 3.1: Esquema simplificado de um poço tubular de abastecimento.

3.7 Nível estático, nível dinâmico e rebaixamento

O comportamento operacional de um poço é descrito por três grandezas fundamentais.

Nível estático

É a posição da água no poço quando ele está em repouso, sem bombeamento.

Nível dinâmico

É a posição da água no poço durante o bombeamento, quando a vazão se estabiliza para determinada condição operacional.

Rebaixamento

É a diferença entre o nível dinâmico e o nível estático:

$$s = ND - NE$$

O rebaixamento indica quanto a água precisa descer para sustentar a vazão bombeada. Em geral, quanto maior o rebaixamento, maior a energia necessária para a captação.

Leitura operacional

Um poço pode apresentar boa vazão e, ainda assim, ser pouco eficiente se o rebaixamento for excessivo.

3.7.1 Capacidade específica

A capacidade específica expressa a relação entre vazão e rebaixamento:

$$C_e = \frac{Q}{s}$$

em que:

- C_e é a capacidade específica;
- Q é a vazão bombeada;
- s é o rebaixamento correspondente.

Essa grandeza é útil para comparar o desempenho de poços e para avaliar se a obra está operando de maneira eficiente.

3.8 Dimensionamento hidráulico

3.8.1 Vazão de projeto

A vazão de projeto deve ser compatível com a demanda e com a capacidade segura do poço e do aquífero. Não se deve adotar uma vazão apenas porque ela foi observada em um teste curto. É preciso considerar o comportamento de longo prazo.

Vazão de exploração

É a vazão adotada em operação regular, compatível com a sustentabilidade hidráulica do poço, a estabilidade do aquífero e as condições sanitárias da captação.

Uma forma simples de verificar a compatibilidade com a capacidade específica é:

$$Q_p \leq C_e \, s_{adm}$$

em que:

- Q_p é a vazão de projeto;
- s_{adm} é o rebaixamento admissível.

3.8.2 Altura manométrica total

Para selecionar a bomba, é necessário conhecer a altura manométrica total:

$$H_{MT} = H_g + s + h_f + h_p$$

em que:

- H_g é a altura geométrica;
- s é o rebaixamento operacional;
- h_f são as perdas de carga na tubulação;
- h_p é a pressão residual requerida no ponto de entrega.

A potência hidráulica necessária pode ser estimada por:

$$P = \frac{\rho g Q H_{MT}}{\eta}$$

em que:

- ρ é a densidade da água;
- g é a aceleração da gravidade;
- Q é a vazão;
- η é o rendimento global do sistema.

Seleção da bomba

A bomba deve ser escolhida para operar dentro de uma faixa de eficiência compatível com a vazão e com a altura manométrica total. A seleção inadequada pode gerar cavitação, desgaste prematuro e aumento do custo energético.

3.9 Ensaios de bombeamento

Os ensaios de bombeamento avaliam a resposta do poço e do aquífero à retirada de água. Eles são indispensáveis para estimar parâmetros hidráulicos e validar o desempenho da captação.

Ensaio de bombeamento

É o teste hidráulico em que um poço é submetido a uma vazão conhecida e monitorada, enquanto os níveis d'água são medidos em função do tempo, no próprio poço ou em poços de observação.

3.9.1 Finalidades principais

- estimar transmissividade e armazenabilidade;
- avaliar a eficiência do poço;
- definir a vazão segura de exploração;
- identificar fronteiras hidráulicas;

- detectar interferência de poços vizinhos;
- orientar a seleção de bomba e a operação.

3.9.2 Tipos de ensaio

Tabela 3.2: Tipos principais de ensaios de bombeamento e suas finalidades

Tipo de ensaio	Finalidade principal	Observação técnica
Ensaio escalonado	Avaliar perdas de carga no poço e eficiência construtiva	Usa vazões crescentes em etapas sucessivas
Ensaio de vazão constante	Estimar parâmetros do aquífero e sua resposta temporal	É o teste clássico de interpretação hidrogeológica
Ensaio de recuperação	Verificar a recomposição do nível após o bombeamento	Complementa a leitura do ensaio principal
Teste de curta duração	Obter estimativas preliminares de K e comportamento local	Útil como apoio, mas não substitui os demais

3.9.3 Ensaio escalonado

No ensaio escalonado, o poço é bombado em etapas de vazões crescentes. Em cada etapa, observa-se o rebaixamento produzido.

Uma forma clássica de representação é:

$$s = BQ + CQ^2$$

em que:

- BQ representa a perda de carga linear, associada ao aquífero;
- CQ^2 representa a perda de carga não linear, associada ao poço e à turbulência local.

A forma dividida por Q é:

$$\frac{s}{Q} = B + CQ$$

Eficiência de poço

A eficiência de poço pode ser expressa pela fração do rebaixamento atribuída às perdas lineares:

$$E = \frac{BQ}{s} \times 100$$

Se a eficiência diminui com o aumento da vazão, isso indica que o poço está introduzindo perdas importantes.

3.9.4 Ensaio de vazão constante

No ensaio de vazão constante, o poço é bombeado com vazão aproximadamente fixa por tempo suficiente para registrar a evolução do rebaixamento. Esse é o ensaio mais importante para estimar os parâmetros do aquífero.

Cone de rebaixamento

É a depressão da superfície freática ou piezométrica em torno de um poço bombeado, causada pela retirada de água.

3.9.5 Método de Theis

Para aquíferos confinados ideais, a solução de Theis relaciona rebaixamento, vazão e tempo por:

$$s(r,t) = \frac{Q}{4\pi T} W(u)$$

em que:

$$u = \frac{r^2 S}{4Tt}$$

e $W(u)$ é a função poço.

Parâmetros de Theis

- T: transmissividade;
- S: armazenabilidade;
- r: distância ao poço;
- t: tempo desde o início do bombeamento;
- Q: vazão constante.

3.9.6 Aproximação de Cooper-Jacob

Em tempos suficientemente longos, pode-se usar a aproximação:

$$s = \frac{2.3Q}{4\pi T} \log_{10}\left(\frac{2.25Tt}{r^2 S}\right)$$

Da inclinação da reta no gráfico semilogarítmico, obtém-se:

$$T = \frac{0.183Q}{\Delta s}$$

quando Q é expresso em m^3/d e Δs é o rebaixamento por ciclo logarítmico de tempo.

Vantagem prática

O método de Cooper-Jacob simplifica a interpretação e é muito útil quando o trecho de resposta do aquífero já apresenta comportamento aproximadamente linear em gráfico semilogarítmico.

3.9.7 Ensaio de recuperação

Após o desligamento da bomba, observa-se a recuperação do nível d'água. Essa etapa ajuda a confirmar a interpretação da fase de bombeamento.

Recuperação

É o retorno parcial ou total do nível d'água após o fim do bombeamento.

3.10 Interpretação hidráulica

A forma da curva de rebaixamento fornece informações essenciais sobre o comportamento do sistema.

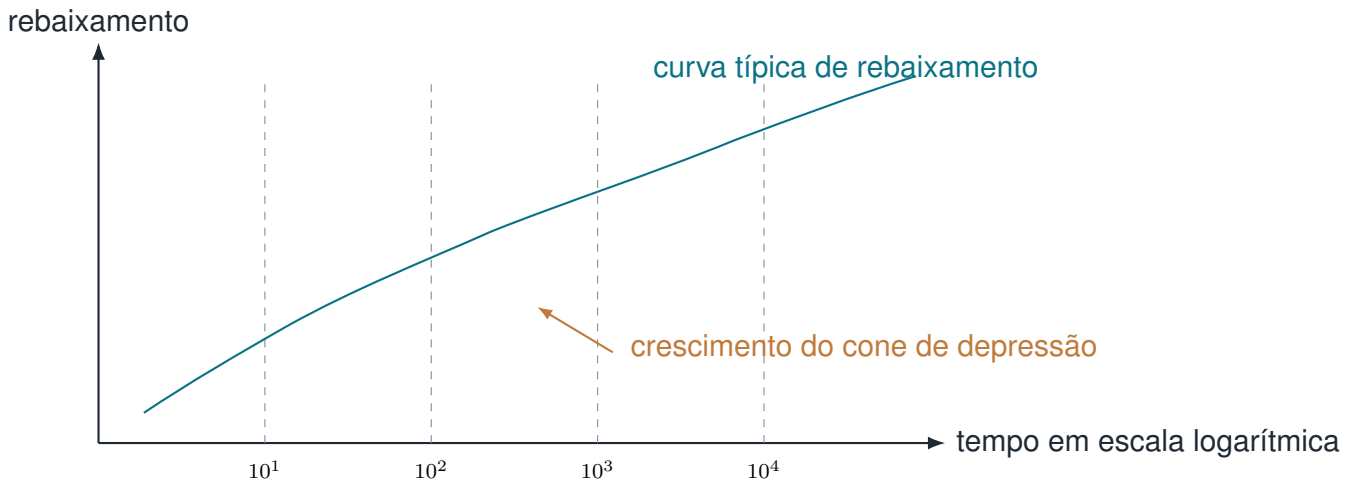

Figura 3.2: Esquema conceitual de curva de rebaixamento em um ensaio de vazão constante.

Em aquíferos confinados, a interpretação é geralmente mais direta. Em aquíferos livres, a resposta inicial pode ser influenciada pela drenagem gravitacional. Em aquíferos semiconfinados, o vazamento vertical pode amortecer o rebaixamento.

Leitura interpretativa

Mudanças na inclinação da curva podem indicar fronteira de recarga, barreira impermeável, interferência de outros poços ou vazamento através de camadas semipermeáveis.

3.10.1 Parâmetros derivados

Os testes permitem estimar:

- transmissividade T;
- armazenabilidade S;
- condutividade hidráulica K, se a espessura b for conhecida, por $K = T/b$;
- capacidade específica do poço;
- eficiência hidráulica da obra.

Integração conceitual

Os ensaios de bombeamento traduzem em números o comportamento que já vinha sendo discutido desde a porosidade, a Lei de Darcy e os tipos de aquíferos.

3.11 Exemplo resolvido

Avaliação preliminar de um poço e seleção da bomba

Uma comunidade necessita de 15 m³/h de água. Um poço tubular apresentou capacidade específica de 2,5 m³/(h m). O nível estático está a 18 m de profundidade e admite-se rebaixamento operacional de 7 m. A altura geométrica adicional é de 5 m, as perdas de carga na tubulação são de 3 m e o rendimento global do sistema é de 68%.

1. Verificação da vazão admissível

$$Q_p \leq C_e s_{adm}$$

$$Q_p \leq 2.5 \times 7 = 17{,}5\ \text{m}^3/\text{h}$$

A demanda de 15 m³/h é compatível com a capacidade estimada do poço.

2. Altura manométrica total

$$H_{MT} = H_g + s + h_f$$

Como não foi exigida pressão residual no ponto de entrega, adota-se $h_p = 0$:

$$H_{MT} = 18 + 7 + 5 + 3 = 33\ \text{m}$$

3. Potência no eixo

Primeiro, converte-se a vazão:

$$Q = \frac{15}{3600} = 4{,}17 \times 10^{-3}\ \mathrm{m^3/s}$$

Então:

$$P = \frac{\rho g Q H_{MT}}{\eta}$$

$$P = \frac{1000 \times 9.81 \times 4.17 \times 10^{-3} \times 33}{0.68}$$

$$P \approx 1{,}99\ \mathrm{kW}$$

Logo, uma motobomba da ordem de 2 kW seria uma referência inicial plausível, a ser confirmada pelas curvas do fabricante e pelas condições reais de operação.

Interpretação

O exemplo mostra que a escolha da bomba depende de vazão, rebaixamento, perdas de carga e eficiência do conjunto, e não apenas da necessidade volumétrica da comunidade.

3.12 Proteção sanitária e operação

A proteção sanitária é indispensável para preservar a qualidade da água e a vida útil da captação.

3.12.1 Medidas fundamentais

- laje sanitária ao redor da boca do poço;
- vedação do espaço anular;
- cabeçote elevado e protegido;
- cercamento da área imediata;
- drenagem superficial adequada;
- ausência de fontes poluidoras no entorno;
- inspeção periódica de tampa, juntas e tubulações;
- manutenção regular da bomba e dos dispositivos elétricos.

Proteção imediata

A medida mais simples e mais barata também é uma das mais importantes: impedir a entrada de água superficial pela boca do poço.

3.12.2 Problemas operacionais comuns

- entrada de areia fina;
- colmatação do filtro;
- corrosão de tubulações;
- redução gradual da eficiência;
- interferência entre poços;
- contaminação por falhas construtivas;
- cavitação e superaquecimento da bomba.

Mensagem prática

Um poço pode ser tecnicamente viável e, ainda assim, inadequado para abastecimento se não houver controle sanitário e manutenção contínua.

3.13 Resumo do capítulo

Resumo do capítulo

- Poços de abastecimento conectam aquíferos ao sistema de uso da água.
- Poços escavados são mais rasos e vulneráveis; poços tubulares oferecem maior controle técnico.
- O projeto do poço envolve locação, perfuração, desenvolvimento, teste, operação e proteção sanitária.
- Revestimento, filtro, pré-filtro, cabeçote e laje sanitária são componentes essenciais.
- Nível estático, nível dinâmico e rebaixamento descrevem o comportamento operacional.
- A capacidade específica relaciona vazão e rebaixamento.
- A vazão de exploração deve ser compatível com a capacidade segura do poço e do aquífero.
- A altura manométrica total é indispensável para selecionar a bomba.
- Ensaios de bombeamento permitem estimar transmissividade, armazenabilidade e eficiência.
- O ensaio escalonado avalia perdas no poço; o ensaio de vazão constante avalia o aquífero; o ensaio de recuperação complementa a interpretação.

- Proteção sanitária e manutenção contínua são indispensáveis para o abastecimento seguro.

3.14 Exercícios

Nível F — Fáceis

F1

Defina nível estático, nível dinâmico e rebaixamento de um poço.

F2

Explique a função do revestimento e do filtro em um poço tubular.

F3

Por que a laje sanitária é importante para a proteção de um poço?

F4

Cite duas diferenças entre poços escavados e poços tubulares.

Nível M — Médios

M1

Um poço apresenta nível estático a 24 m de profundidade e nível dinâmico a 31 m. Calcule o rebaixamento.

M2

Um poço bombeia 12 m^3/h com rebaixamento de 6 m. Calcule a capacidade específica.

M3

Uma captação requer 20 m^3/h. O poço testado apresenta capacidade específica de 3 $m^3/(h\,m)$ e rebaixamento admissível de 6 m. A vazão solicitada é compatível com o poço? Justifique.

M4

Explique por que a seleção da bomba deve considerar a altura manométrica total e não apenas a vazão desejada.

Nível D — Difíceis

D1

Uma cidade pretende implantar um poço tubular em área urbana parcialmente impermeabilizada. A região possui fontes potenciais de contaminação, mas também boa transmissividade aquífera. Proponha uma estratégia de localização, proteção e operação do poço.

D2

Um poço apresenta capacidade específica relativamente alta, mas a água produzida contém areia fina em suspensão. Interprete o problema do ponto de vista construtivo e hidrogeológico e indique possíveis correções.

D3

Explique por que um poço pode ser hidráulica e economicamente viável, mas inadequado para abastecimento público se não houver proteção sanitária e controle de uso do solo.

3.15 Gabarito comentado

Resposta ao exercício F1

O nível estático é a posição da água no poço quando ele está em repouso, sem bombeamento. O nível dinâmico é a posição da água durante o bombeamento. O rebaixamento é a diferença entre os dois:

$$s = ND - NE$$

Essas grandezas permitem avaliar o desempenho operacional do poço.

Resposta ao exercício F2

O revestimento sustenta as paredes da perfuração e isola intervalos indesejáveis. O filtro permite a entrada de água do aquífero e ajuda a reter partículas finas. Juntos, eles garantem estabilidade estrutural e melhor desempenho hidráulico.
Sem esses elementos, o poço pode desmoronar, colmatar ou produzir água com excesso de areia.

Resposta ao exercício F3

A laje sanitária impede que água de chuva ou água contaminada escoe diretamente para a boca do poço. Ela também ajuda a proteger a estrutura contra infiltração lateral e facilita o escoamento superficial para longe da captação.
É uma medida simples, mas essencial para evitar contaminação direta.

Resposta ao exercício F4

Poços escavados são normalmente rasos, de maior diâmetro e mais expostos à contaminação superficial. Poços tubulares são perfurados mecanicamente, atingem maiores profundidades e permitem melhor controle técnico da captação.
Além disso, poços tubulares podem explorar aquíferos confinados ou semiconfinados, enquanto poços escavados geralmente captam aquíferos livres rasos.

Resposta ao exercício M1

O rebaixamento é:

$$s = ND - NE = 31 - 24 = 7\,\text{m}$$

Logo, o rebaixamento é de 7 m. Esse valor representa quanto a água desceu durante o bombeamento em relação ao repouso.

Resposta ao exercício M2

A capacidade específica é:

$$C_e = \frac{Q}{s} = \frac{12}{6} = 2\,\text{m}^3/(\text{h m})$$

Portanto, a capacidade específica do poço é 2 m³/(h m). Quanto maior esse valor, melhor o desempenho operacional do poço.

Resposta ao exercício M3

A vazão admissível é:

$$Q_p \leq C_e s_{adm}$$

$$Q_p \leq 3 \times 6 = 18\,\text{m}^3/\text{h}$$

Como a demanda é de 20 m³/h, a vazão solicitada não é compatível com a capacidade segura estimada do poço. Seria necessário reduzir a demanda, ampliar o rebaixamento admissível com cautela, perfurar outro poço ou buscar um aquífero mais produtivo.
O cálculo mostra que a decisão de projeto deve respeitar o desempenho real do sistema.

Resposta ao exercício M4

A altura manométrica total reúne todos os componentes da carga que a bomba precisa vencer: desnível geométrico, rebaixamento operacional, perdas de carga e eventual pressão residual.
Se a bomba for escolhida apenas pela vazão, pode ficar subdimensionada em altura ou

consumir energia excessiva. Por isso, a análise deve considerar o sistema completo, e não apenas a vazão nominal.

Resposta ao exercício D1

A estratégia deve combinar viabilidade hidrogeológica com proteção sanitária. Em área urbana, o poço deve ser localizado o mais longe possível de fontes de contaminação, respeitando a direção do fluxo subterrâneo e a possibilidade de delimitar zonas de proteção. Deve-se priorizar a porção do aquífero com boa transmissividade, mas sem sacrificar a segurança da água.

Medidas recomendadas:

- levantamento hidrogeológico e sanitário detalhado;
- afastamento de fontes de contaminação;
- vedação e laje sanitária adequadas;
- monitoramento da qualidade da água;
- definição de zona imediata e zona de contribuição;
- operação com vazão compatível com a capacidade do aquífero.

Assim, o poço será produtivo e sanitariamente mais seguro.

Resposta ao exercício D2

A presença de areia fina indica que a seção filtrante, o pré-filtro ou o desenvolvimento do poço podem estar inadequados. Pode haver velocidade de entrada elevada, seleção incorreta da abertura do filtro, ausência de pré-filtro apropriado ou colmatação da zona próxima ao poço.

Possíveis correções:

- revisar a granulometria da formação e do pré-filtro;
- ajustar a abertura do filtro;
- realizar novo desenvolvimento;
- reduzir a vazão de bombeamento;
- verificar a integridade do revestimento e das juntas.

O problema é tanto construtivo quanto hidrogeológico, pois depende da interação entre o poço e o meio poroso.

Resposta ao exercício D3

Um poço pode ser hidráulica e economicamente viável, mas inadequado para abastecimento público se houver risco elevado de contaminação. Isso ocorre quando o entorno é mal protegido, a zona de recarga é vulnerável ou o uso do solo é incompatível com a preservação da água.

A água subterrânea captada pode ser boa no momento da perfuração, mas degradar-se ao longo do tempo se não houver controle sanitário. Portanto, viabilidade técnica sem proteção sanitária não é suficiente para garantir segurança no abastecimento.

3.16 Conexão com o próximo capítulo

Do projeto e operação à vulnerabilidade

Neste capítulo, o poço foi tratado como obra de captação, desde sua concepção até a interpretação dos ensaios de bombeamento. No próximo capítulo, o foco passará para a vulnerabilidade e a contaminação dos aquíferos. A partir daí, será possível analisar como os contaminantes se movimentam no subsolo, quais fatores aumentam o risco e quais medidas são necessárias para proteger a água subterrânea em contexto de saneamento ambiental.

4

Vulnerabilidade e contaminação de aquíferos

4.1 Introdução

A água subterrânea é frequentemente percebida como um recurso naturalmente protegido por sua posição no subsolo. Em parte isso é verdade, mas essa proteção não é absoluta. Dependendo da estrutura geológica, do tipo de aquífero, da profundidade do nível d'água e do uso do solo na superfície, contaminantes podem atingir a zona saturada com relativa facilidade.

Em saneamento ambiental, compreender a vulnerabilidade dos aquíferos é indispensável para prevenir riscos, proteger poços, monitorar a qualidade da água e definir estratégias de ocupação territorial. A contaminação subterrânea costuma ser difícil de detectar, lenta para se desenvolver e cara para remediar. Por isso, a prevenção é sempre preferível à correção.

Este capítulo aborda os conceitos de vulnerabilidade, as principais fontes de contaminação, os mecanismos de transporte no subsolo, a formação de plumas contaminantes, os métodos de avaliação da susceptibilidade natural e as medidas de prevenção e remediação aplicáveis à gestão de águas subterrâneas.

4.2 Objetivos de aprendizagem

Ao final deste capítulo, o estudante deverá ser capaz de:

- diferenciar contaminação, poluição, vulnerabilidade e risco hidrogeológico;
- identificar fontes pontuais, lineares e difusas de contaminação;
- reconhecer os principais mecanismos de transporte de contaminantes no subsolo;
- compreender o papel da advecção, dispersão, difusão, sorção e degradação;
- interpretar a evolução de plumas de contaminação em aquíferos livres e confinados;
- distinguir vulnerabilidade intrínseca e vulnerabilidade específica;

- reconhecer os limites dos mapas e índices de vulnerabilidade;
- propor medidas preventivas e corretivas para proteção de aquíferos.

4.3 Conceitos fundamentais

Contaminação

Contaminação é a alteração da qualidade natural da água subterrânea pela presença de substâncias, microrganismos ou energia em concentrações ou condições incompatíveis com o uso desejado.

Poluição

Poluição é uma forma de contaminação que já produz efeito indesejável, deterioração da qualidade ou risco concreto ao uso humano, ecológico ou produtivo da água.

Vulnerabilidade

Vulnerabilidade é a predisposição natural de um aquífero a ser afetado por contaminantes a partir da superfície ou de zonas adjacentes.

Risco hidrogeológico

Risco hidrogeológico é a combinação entre a presença de uma fonte de ameaça, a vulnerabilidade do meio e a exposição de receptores, como poços, nascentes ou usuários.

Distinção importante

Nem todo aquífero vulnerável está contaminado, e nem toda área contaminada apresenta a mesma vulnerabilidade. A vulnerabilidade é uma condição natural do sistema; a contaminação é um estado resultante da introdução de agentes externos.

4.3.1 Vulnerabilidade intrínseca e específica

A **vulnerabilidade intrínseca** depende apenas das características naturais do aquífero e do meio sobrejacente: profundidade do nível d'água, tipo de solo, litologia, recarga e grau de confinamento.

A **vulnerabilidade específica** considera, além disso, o contaminante em questão. Um composto muito móvel e persistente pode representar risco maior do que outro mais facilmente degradável ou adsorvido.

Leitura técnica

Em termos práticos, um aquífero pode ser intrinsecamente pouco vulnerável, mas tornar-se muito suscetível a um determinado poluente se esse contaminante for altamente persistente, solúvel e pouco retido pelo meio.

4.4 Fontes de contaminação

As fontes de contaminação podem ser classificadas segundo sua geometria e seu padrão de emissão.

- **Fontes pontuais**: ocupam área reduzida e introduzem contaminantes em um ponto específico, como fossas, poços mal vedados, tanques subterrâneos, aterros, postos de combustíveis e efluentes industriais.
- **Fontes lineares**: associadas a linhas de emissão, como redes de esgoto, canais, dutos, valas e infraestrutura de drenagem.
- **Fontes difusas**: espalham contaminantes por áreas extensas, como uso agrícola com fertilizantes e agrotóxicos, deposição atmosférica e infiltração urbana generalizada.

Tabela 4.1: Fontes comuns de contaminação e contaminantes associados

Fonte	Contaminantes típicos	Observação
Fossas e esgoto sanitário	coliformes, vírus, nitrato, amônio, matéria orgânica	risco elevado em aquíferos livres rasos
Aterros e lixões	chorume, amônio, metais, compostos orgânicos, sais dissolvidos	contaminação complexa e persistente
Postos e tanques de combustível	hidrocarbonetos, BTEX, solventes, fase livre de combustível	forte mobilidade em meios permeáveis
Atividades agrícolas	nitrato, fosfato, pesticidas, sais	fonte difusa e de grande extensão
Indústrias e oficinas	solventes, metais, óleos, compostos orgânicos	depende do tipo de processo e descarte
Poços mal construídos	comunicação vertical entre camadas	podem conduzir contaminantes diretamente ao aquífero

Boa prática

Poços mal vedados podem transformar-se em caminhos rápidos de contaminação vertical, conectando a superfície a unidades profundas que, de outro modo, estariam protegidas.

4.5 Mecanismos de transporte de contaminantes

Os contaminantes se movem no subsolo por processos físicos, químicos e biológicos. O entendimento desses mecanismos é fundamental para prever a migração de plumas e o

tempo de chegada a poços ou receptores sensíveis.

4.5.1 Advecção

A advecção é o transporte de contaminantes acompanhando o fluxo da água subterrânea. Em meios porosos saturados, a velocidade média da água nos poros pode ser estimada por:

$$v = \frac{Ki}{n_e}$$

em que:

- v é a velocidade intersticial média;
- K é a condutividade hidráulica;
- i é o gradiente hidráulico;
- n_e é a porosidade efetiva.

Se o contaminante não sofre retardação relevante, sua velocidade tende a ser próxima à da água.

4.5.2 Dispersão

A dispersão é o espalhamento do contaminante no meio poroso devido à heterogeneidade dos caminhos de fluxo, diferenças locais de velocidade e mistura entre trajetórias. Ela aumenta a largura da pluma e reduz, em parte, a concentração máxima ao longo do trajeto.

4.5.3 Difusão

A difusão é o movimento das moléculas de regiões de maior concentração para regiões de menor concentração, mesmo na ausência de fluxo significativo. Em aquíferos de baixa velocidade, a difusão pode ser importante, especialmente em escalas de tempo longas.

4.5.4 Soração e retardação

Muitos contaminantes interagem com a matriz do solo ou da rocha por adsorção, troca iônica ou partição. Isso reduz sua velocidade aparente e aumenta o tempo de migração.

Uma forma simplificada de representar esse efeito é pelo fator de retardação:

$$R_f = 1 + \frac{\rho_b K_d}{n_e}$$

em que:

- R_f é o fator de retardação;
- ρ_b é a densidade aparente do meio;

- K_d é o coeficiente de distribuição sólido–água;
- n_e é a porosidade efetiva.

A velocidade efetiva do contaminante pode ser aproximada por:

$$v_c = \frac{v}{R_f}$$

Interpretação

Quanto maior a sorção, maior o retardamento. Contaminantes fortemente adsorvidos tendem a migrar mais lentamente, mas podem permanecer no sistema por muito tempo e atuar como fonte secundária de poluição.

4.5.5 Degradação e atenuação natural

Alguns contaminantes sofrem degradação química ou biológica ao longo do percurso. Outros podem precipitar, volatilizar ou ser diluídos. Esses processos compõem a atenuação natural, que pode reduzir parcialmente a concentração ao longo do tempo.

- **Biodegradação**: transformação por microrganismos.
- **Oxidação e redução**: reações controladas por condições redox.
- **Precipitação**: formação de fases sólidas pouco solúveis.
- **Diluição**: mistura com água menos contaminada.
- **Volatilização**: perda de compostos voláteis para a fase gasosa.

Limite da atenuação natural

A atenuação natural não substitui o controle da fonte. Ela pode ajudar, mas não deve ser tratada como solução única para contaminação de aquíferos.

4.6 Plumas de contaminação

Quando um contaminante entra no aquífero, ele tende a formar uma pluma, isto é, uma região alongada de água alterada quimicamente em direção ao fluxo subterrâneo. A geometria da pluma depende da velocidade da água, do grau de dispersão, da heterogeneidade do meio e da presença de reações químicas.

Em uma pluma típica, podem ser reconhecidas zonas com diferentes características:

- **núcleo**: região de concentração mais elevada;
- **franja**: área de transição com mistura e atenuação;
- **cauda**: extensão distal da pluma, com baixas concentrações;

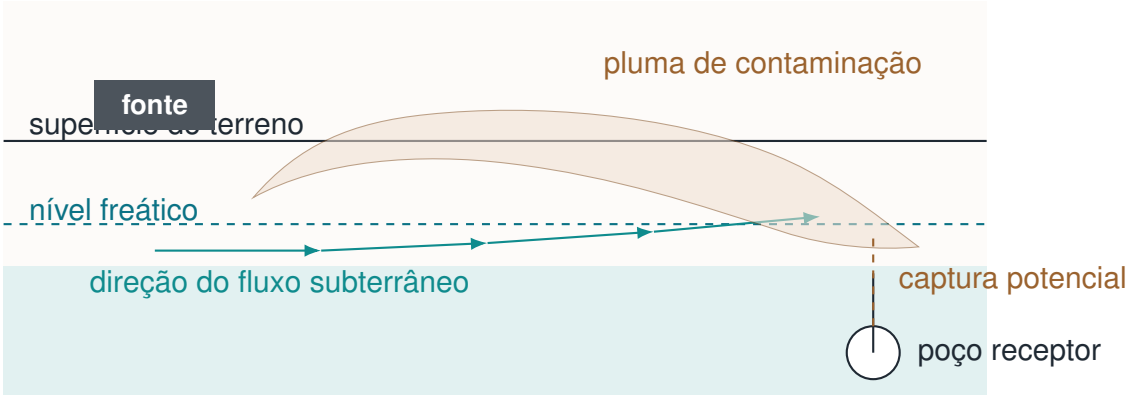

Figura 4.1: Esquema conceitual de migração de uma pluma de contaminação em direção a um poço.

- **zona fonte**: local onde o contaminante ainda está sendo liberado.

Importância do gradiente

Em áreas com gradiente hidráulico elevado, a pluma tende a avançar mais rapidamente. Em meios heterogêneos, a migração pode concentrar-se em caminhos preferenciais, tornando a previsão mais complexa.

4.7 Vulnerabilidade natural dos aquíferos

A vulnerabilidade de um aquífero não é uniforme. Ela depende de uma série de fatores físicos e geométricos.

- **Profundidade do nível d'água**: quanto mais raso, maior a vulnerabilidade.
- **Grau de confinamento**: aquíferos livres tendem a ser mais vulneráveis.
- **Tipo de solo**: solos arenosos geralmente oferecem menor proteção que solos argilosos.
- **Recarga**: maior recarga pode aumentar a entrada de contaminantes.
- **Fraturamento**: fraturas e falhas podem funcionar como vias rápidas de migração.
- **Crescimento urbano**: impermeabilização, poços mal construídos e vazamentos aumentam o risco.

Mensagem central

Aquíferos mais produtivos não são, necessariamente, os mais seguros. Em saneamento, produtividade e proteção precisam ser avaliadas em conjunto.

4.8 Métodos de avaliação da vulnerabilidade

A vulnerabilidade pode ser avaliada por abordagens qualitativas, semiquantitativas e quantitativas.

4.8.1 Abordagem conceitual

A forma mais simples de avaliação consiste em interpretar:

- profundidade do nível d'água;
- tipo de cobertura do solo;
- litologia da zona não saturada;
- presença de recarga concentrada;
- existência de fraturas e condutos.

Essa abordagem é útil em diagnósticos preliminares, mas não substitui estudos mais detalhados.

4.8.2 Índices de vulnerabilidade

Os índices ajudam a sintetizar várias variáveis em um valor comparativo. Entre os mais conhecidos estão:

- **GOD**: considera grau de confinamento, características do substrato e profundidade da água;
- **DRASTIC**: combina profundidade, recarga, meio aquífero, solo, topografia, impacto da zona vadosa e condutividade hidráulica;
- **SINTACS**: estrutura semelhante ao DRASTIC, com adaptação a diferentes contextos.

Tabela 4.2: Exemplos de índices de vulnerabilidade e suas variáveis principais

Índice	Variáveis centrais	Comentário
GOD	grau de confinamento, litologia do aquífero, profundidade da água	simples e rápido, útil em estudos preliminares
DRASTIC	profundidade, recarga, meio aquífero, solo, topografia, zona vadosa, condutividade	mais detalhado, amplamente empregado
SINTACS	parâmetros semelhantes ao DRASTIC, com ajustes de ponderação	flexível para diferentes cenários

Limitação dos índices

Mapas de vulnerabilidade não devem ser interpretados como verdade absoluta. Eles são ferramentas de apoio e dependem de boa base de dados, calibração local e validação em campo.

4.8.3 Vulnerabilidade e risco

A vulnerabilidade natural precisa ser combinada com a presença de fontes de ameaça. Uma área pode ser altamente vulnerável, mas apresentar baixo risco se não houver atividade poluidora relevante. Da mesma forma, uma área menos vulnerável pode tornar-se crítica se houver fontes intensas e persistentes de contaminação.

Risco e gestão

O risco real emerge quando fonte, caminho e receptor se encontram. Por isso, a gestão de aquíferos exige tanto controle de fontes quanto conhecimento da vulnerabilidade natural.

4.9 Monitoramento hidroquímico e sanitário

O monitoramento é essencial para detectar alterações de qualidade antes que a contaminação se torne irreversível ou muito cara de remediar.

4.9.1 Objetivos do monitoramento

- identificar tendências de contaminação;
- verificar se há migração de plumas;
- acompanhar a eficiência de medidas de controle;
- apoiar decisões de uso, restrição ou remediação;
- proteger poços de abastecimento e áreas de recarga.

4.9.2 Parâmetros frequentemente acompanhados

- pH;
- condutividade elétrica;
- temperatura;
- oxigênio dissolvido;
- potencial redox;
- nitrato;

- amônio;
- cloreto;
- ferro e manganês;
- coliformes;
- compostos orgânicos específicos, conforme a fonte.

Indicadores úteis

Nitrato, cloreto e coliformes costumam ser indicadores importantes de impacto sanitário. Em áreas com combustível ou solventes, outros parâmetros específicos devem ser incorporados.

4.9.3 Rede de monitoramento

Uma rede de monitoramento bem concebida deve incluir:

- poços a montante e a jusante hidráulica;
- pontos em diferentes profundidades, quando houver camadas distintas;
- frequência de amostragem compatível com a dinâmica do contaminante;
- registro de níveis d'água e condições operacionais dos poços;
- integração entre dados hidráulicos e dados hidroquímicos.

4.10 Prevenção e remediação

4.10.1 Prevenção

A prevenção é sempre a estratégia mais eficiente. As medidas mais importantes incluem:

- controle de fontes pontuais e difusas;
- proteção de poços e áreas de recarga;
- vedação adequada de captações;
- manutenção de redes de esgoto e drenagem;
- controle de tanques e armazenamentos subterrâneos;
- manejo agrícola conservacionista;
- educação ambiental e fiscalização.

Três barreiras de proteção

Uma boa estratégia de prevenção combina: controle da fonte, proteção do caminho e proteção do receptor.

4.10.2 Remediação

Quando a contaminação já ocorreu, algumas estratégias podem ser aplicadas, dependendo do tipo de contaminante e da escala do problema:

- **remoção da fonte**: cessar o aporte contaminante;
- **contenção hidráulica**: evitar a expansão da pluma;
- **bombeamento e tratamento**: capturar a água contaminada e tratá-la;
- **barreiras reativas**: promover reações de degradação ou imobilização;
- **atenuação natural monitorada**: acompanhar a redução gradual da pluma sob controle;
- **substituição ou isolamento do poço**: quando a captação está comprometida.

Cuidado técnico

Remediação subterrânea costuma ser demorada, cara e tecnicamente complexa. Em muitos casos, o foco realista deve ser conter a fonte e proteger os receptores mais importantes.

4.11 Exemplo resolvido

Estimativa de tempo de chegada de um contaminante não sorvido

Considere um aquífero livre com condutividade hidráulica $K = 1 \times 10^{-4}$ m/s, gradiente hidráulico $i = 0{,}015$ e porosidade efetiva $n_e = 0{,}20$. Um contaminante conservativo é lançado a 150 m de um poço de abastecimento, ao longo da direção principal do fluxo. Admitindo que o contaminante não sofra sorção nem degradação relevante, estime o tempo de viagem advectiva.

1. Velocidade intersticial

$$v = \frac{Ki}{n_e}$$

$$v = \frac{1 \times 10^{-4} \times 0{,}015}{0{,}20}$$

$$v = 7{,}5 \times 10^{-6}\ \mathrm{m/s}$$

Convertendo para metros por dia:

$$v = 7{,}5 \times 10^{-6} \times 86400 = 0{,}648\,\mathrm{m/d}$$

2. Tempo de viagem

$$t = \frac{L}{v}$$

$$t = \frac{150}{0{,}648} \approx 231{,}5\,\mathrm{d}$$

Logo, o contaminante poderia alcançar a captação em aproximadamente 232 d, isto é, cerca de 7 a 8 meses.

3. Efeito de retardação

Se o contaminante apresentar fator de retardação $R_f = 4$, o tempo de viagem estimado passa a ser:

$$t_c \approx 4 \times 231.5 = 926\,\mathrm{d}$$

ou cerca de 2,5 anos.

Interpretação

O exemplo mostra que o tempo de migração depende tanto da estrutura hidráulica quanto da interação do contaminante com o meio. Mesmo assim, o poço permanece vulnerável porque o avanço ainda pode ocorrer em escala humana relevante.

4.12 Resumo do capítulo

Resumo do capítulo

- Contaminação é a alteração da qualidade natural da água subterrânea.
- Poluição é a contaminação com efeito indesejável ou impeditivo ao uso.
- Vulnerabilidade é a predisposição natural do aquífero a ser afetado por contaminantes.
- Risco depende da combinação entre fonte, caminho e receptor.
- As fontes de contaminação podem ser pontuais, lineares ou difusas.
- Advecção, dispersão, difusão, sorção e degradação controlam o movimento dos contaminantes.
- Plumas de contaminação se propagam na direção do fluxo subterrâneo e podem atingir poços.

- Aquíferos livres e rasos tendem a ser mais vulneráveis do que aquíferos confinados.
- Índices como GOD, DRASTIC e SINTACS ajudam a mapear vulnerabilidade, mas não substituem campo.
- O monitoramento hidroquímico é essencial para prevenir e detectar problemas.
- A prevenção é sempre mais eficiente do que a remediação.

4.13 Exercícios

Nível F — Fáceis

F1

Defina contaminação, poluição e vulnerabilidade de aquífero.

F2

Explique por que aquíferos livres costumam ser mais vulneráveis à contaminação superficial.

F3

Diferencie fonte pontual, fonte linear e fonte difusa de contaminação.

F4

Por que o nitrato é frequentemente usado como indicador de impacto em águas subterrâneas?

Nível M — Médios

M1

Em um aquífero com $K = 8 \times 10^{-5}$ m/s, $i = 0{,}02$ e $n_e = 0{,}25$, calcule a velocidade intersticial média da água.

M2

Considere um contaminante com $\rho_b = 1{,}60\,\mathrm{g/cm^3}$, $K_d = 0{,}50\,\mathrm{L/kg}$ e $n_e = 0{,}20$. Calcule o fator de retardação.

M3

Um poço está situado a jusante de uma área de recarga urbana. Cite três parâmetros que devem ser monitorados para avaliar possível contaminação.

M4

Explique a diferença entre vulnerabilidade intrínseca e vulnerabilidade específica.

Nível D — Difíceis

D1

Uma área agrícola sobre aquífero livre apresentou aumento de nitrato na água subterrânea após vários anos de intensificação do uso de fertilizantes. Analise a situação do ponto de vista da fonte, do caminho e do receptor, e proponha medidas de gestão.

D2

Um poço de abastecimento começou a apresentar traços de solventes orgânicos após o aparecimento de uma pluma associada a um posto de combustíveis situado a montante hidráulico. Proponha uma estratégia técnica de resposta envolvendo monitoramento, contenção e proteção do abastecimento.

D3

Explique por que mapas de vulnerabilidade são úteis, mas não devem ser usados isoladamente para decidir sobre a instalação de poços ou sobre o fechamento de uma captação existente.

4.14 Gabarito comentado

Resposta ao exercício F1

Contaminação é a alteração da qualidade natural da água subterrânea pela presença de substâncias ou microrganismos. Poluição é uma forma de contaminação já associada a efeito indesejável ou impedimento de uso. Vulnerabilidade é a predisposição natural do aquífero a ser afetado por contaminantes.

Em resumo: contaminação é o estado alterado; poluição é a contaminação com impacto; vulnerabilidade é a susceptibilidade natural do sistema.

Resposta ao exercício F2

Aquíferos livres costumam ser mais vulneráveis porque a água de recarga entra diretamente pela superfície ou pela zona não saturada, com pouca barreira geológica entre a fonte de contaminação e a zona saturada.

Além disso, em aquíferos rasos, o tempo de trânsito até a água captada é menor, o que reduz a oportunidade de atenuação natural.

Resposta ao exercício F3

Fonte pontual é aquela concentrada em um ponto, como uma fossa ou um tanque subterrâneo. Fonte linear é distribuída ao longo de uma linha, como uma rede de esgoto ou um canal. Fonte difusa é espalhada por uma área extensa, como fertilização agrícola ou infiltração urbana generalizada.

A distinção é importante porque a estratégia de controle muda conforme a geometria da fonte.

Resposta ao exercício F4

O nitrato é muito útil como indicador porque é móvel, persistente em muitos ambientes e frequentemente associado a esgoto, fossas e fertilizantes. Quando aparece em concentração elevada em água subterrânea, sugere influência antrópica recente ou contínua. Além disso, ele se comporta como um traçador prático da recarga contaminada em muitos contextos.

Resposta ao exercício M1

A velocidade intersticial é:

$$v = \frac{Ki}{n_e}$$

$$v = \frac{8 \times 10^{-5} \times 0{,}02}{0{,}25}$$

$$v = 6{,}4 \times 10^{-6}\ \mathrm{m/s}$$

Em metros por dia:

$$v = 6{,}4 \times 10^{-6} \times 86400 = 0{,}552\,96\ \mathrm{m/d}$$

Logo, a velocidade intersticial média é aproximadamente 0,553 m/d.

Resposta ao exercício M2

Primeiro, converte-se a densidade aparente:

$$\rho_b = 1{,}60\ \mathrm{g/cm^3} = 1{,}60\ \mathrm{kg/L}$$

Em seguida, aplica-se:

$$R_f = 1 + \frac{\rho_b K_d}{n_e}$$

$$R_f = 1 + \frac{1.60 \times 0.50}{0.20}$$

$$R_f = 1 + 4 = 5$$

Logo, o fator de retardação é $R_f = 5$. Isso significa que o contaminante tende a se mover aproximadamente cinco vezes mais lentamente que a água.

Resposta ao exercício M3

Três parâmetros úteis são:

- nitrato;
- cloreto;
- coliformes termotolerantes.

Também podem ser monitorados pH, condutividade elétrica, amônio, oxigênio dissolvido e compostos específicos conforme a natureza da ameaça. O importante é relacionar o conjunto de parâmetros com a provável fonte de contaminação.

Resposta ao exercício M4

Vulnerabilidade intrínseca é a susceptibilidade natural do aquífero, independentemente do contaminante específico. Vulnerabilidade específica considera também o tipo de substância, sua mobilidade, persistência, sorção e degradabilidade.
Assim, a vulnerabilidade intrínseca responde à pergunta “o sistema é naturalmente exposto?”; a vulnerabilidade específica responde “exposto a quê?”.

Resposta ao exercício D1

A fonte é o uso intensivo de fertilizantes; o caminho é a infiltração e percolação através do solo e da zona não saturada; o receptor é o aquífero livre e os poços associados. O nitrato é altamente móvel e tende a acompanhar a água de recarga, especialmente em solos permeáveis e em áreas com pouca proteção natural.
Medidas de gestão:

- ajuste da dose e do calendário de fertilização;
- adoção de práticas conservacionistas do solo;
- monitoramento de nitrato em poços e piezômetros;
- proteção de áreas de recarga e zonas de captação;
- restrição de usos potencialmente poluidores em áreas críticas.

O caso mostra uma contaminação difusa, persistente e de difícil reversão, o que reforça a

importância da prevenção.

Resposta ao exercício D2

A resposta técnica deve combinar diagnóstico, contenção e proteção do abastecimento:

- delimitar a pluma por meio de poços de monitoramento;
- confirmar a direção do fluxo e a proximidade do poço em relação à fonte;
- reduzir ou interromper temporariamente a captação, se necessário;
- avaliar contenção hidráulica ou barreiras adequadas;
- remover ou neutralizar a fonte de combustível;
- monitorar a evolução química e hidráulica do sistema;
- considerar fontes alternativas de abastecimento enquanto durar a investigação.

Como solventes e hidrocarbonetos podem ser persistentes e mobilizáveis, a prioridade é proteger o receptor e evitar a expansão da pluma. Em muitos casos, a remediação completa é demorada, então a gestão do risco precisa ser imediata.

Resposta ao exercício D3

Mapas de vulnerabilidade são úteis porque sintetizam, de forma espacial, áreas mais ou menos susceptíveis à contaminação. Eles ajudam no planejamento territorial, na definição de zonas de proteção e na priorização de monitoramento.
No entanto, não devem ser usados isoladamente porque:

- são dependentes da qualidade dos dados;
- representam condições naturais médias, não situações pontuais;
- não incorporam automaticamente o tipo de contaminante;
- não substituem investigação de campo e amostragem hidroquímica;
- podem mascarar heterogeneidades locais, fraturas e poços mal construídos.

Portanto, mapas de vulnerabilidade são ferramentas de apoio, e não critérios únicos de decisão.

4.15 Conexão com o próximo capítulo

Da vulnerabilidade à realidade hidrogeológica do Brasil

Este capítulo mostrou como os aquíferos podem ser afetados por fontes de contaminação, pelos mecanismos de transporte e pela vulnerabilidade natural do sistema. No próximo capítulo, o foco passará para os principais sistemas aquíferos do Brasil, com destaque para o Sistema Aquífero Guarani e outras unidades relevantes. Essa transição permitirá aplicar os conceitos de vulnerabilidade e proteção a contextos regionais concretos do território brasileiro.

5

Sistemas aquíferos do Brasil

5.1 Introdução

O Brasil possui uma das maiores diversidades hidrogeológicas do mundo. Essa diversidade resulta da combinação entre grandes bacias sedimentares, extensas áreas de embasamento cristalino, coberturas vulcânicas, terrenos cársticos e unidades costeiras recentes. Como consequência, o país abriga sistemas aquíferos de naturezas muito distintas, com comportamentos hidráulicos, vulnerabilidades e potenciais de exploração também muito diferentes.

Para o saneamento ambiental, conhecer os principais sistemas aquíferos brasileiros é essencial porque a tomada de decisão sobre abastecimento não pode depender apenas da presença de água no subsolo. É preciso considerar produtividade, qualidade natural, recarga, vulnerabilidade, distribuição geográfica e possibilidades de gestão. Um sistema aquífero altamente produtivo pode ser transfronteiriço e exigir cooperação institucional; outro, mais modesto, pode ser localmente decisivo para milhares de pessoas, especialmente em regiões semiáridas.

Este capítulo apresenta uma visão sintética, porém aprofundada, dos principais sistemas aquíferos do Brasil, com destaque para o Sistema Aquífero Guarani e para outras unidades de grande relevância regional e nacional.

5.2 Objetivos de aprendizagem

Ao final deste capítulo, o estudante deverá ser capaz de:

- reconhecer a diversidade hidrogeológica brasileira;
- diferenciar aquíferos sedimentares, cársticos, fissurais e vulcânicos;
- descrever as principais características do Sistema Aquífero Guarani;
- identificar outros sistemas aquíferos relevantes no território brasileiro;
- relacionar tipo de aquífero, produtividade, vulnerabilidade e uso para abastecimento;

- compreender os desafios de gestão associados a sistemas regionais e transfronteiriços;
- interpretar a importância dos aquíferos brasileiros para o saneamento ambiental.

5.3 Panorama hidrogeológico do Brasil

A hidrogeologia brasileira reflete a história geológica do território. O país abriga:

- grandes bacias sedimentares continentais;
- coberturas arenosas extensas;
- derrames vulcânicos basálticos;
- terrenos carbonáticos carstificados;
- embasamentos cristalinos fraturados;
- depósitos sedimentares costeiros e aluviais recentes.

Essa variedade produz sistemas com comportamento muito distinto. Em termos gerais, pode-se agrupar os aquíferos brasileiros em quatro grandes contextos:

- **sedimentares**: formados por arenitos, siltitos e outras rochas porosas;
- **vulcânicos fraturados**: como os basaltos da Serra Geral;
- **cársticos**: em rochas carbonáticas dissolvidas;
- **fissurais ou cristalinos**: em rochas ígneas e metamórficas fraturadas.

Leitura regional

A produtividade de um aquífero não depende apenas da idade da rocha, mas de sua estrutura, fraturamento, porosidade, recarga e conectividade hidráulica.

5.3.1 Principais províncias hidrogeológicas

Em escala regional, o Brasil pode ser compreendido por meio de províncias hidrogeológicas associadas às grandes unidades geológicas. Entre elas, destacam-se:

- bacias sedimentares do interior;
- bacias sedimentares costeiras;
- cinturões carbonáticos e cársticos;
- escudos cristalinos;
- coberturas vulcânicas do sul e sudeste;
- depósitos aluviais e fluviais recentes.

A Figura 5.1 resume, de forma conceitual, essa diversidade.

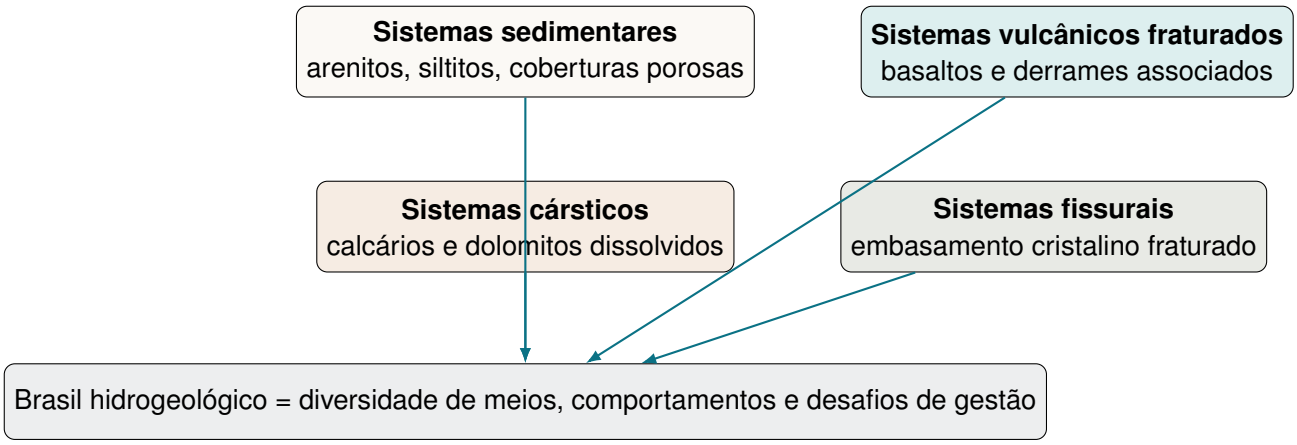

Figura 5.1: Visão conceitual das principais categorias de sistemas aquíferos no Brasil.

5.4 Sistema Aquífero Guarani

5.4.1 Contexto geológico

O Sistema Aquífero Guarani é um dos mais importantes reservatórios subterrâneos da América do Sul. Trata-se de um sistema sedimentar essencialmente associado a arenitos de boa porosidade e permeabilidade, recobertos em grande parte por derrames basálticos da Formação Serra Geral.

Em muitas áreas, o aquífero é confinado ou semiconfinado pelos basaltos; em outras, afloram as zonas de recarga, onde a água pode infiltrar-se diretamente. Essa combinação de unidades sedimentares e vulcânicas cria um sistema hidrogeológico complexo e muito relevante para abastecimento.

Importância regional

O Guarani não deve ser pensado como um único poço ou uma única camada, mas como um sistema amplo, com zonas de recarga, áreas confinadas, compartimentos locais e gradientes regionais.

5.4.2 Extensão e caráter transfronteiriço

O Sistema Aquífero Guarani possui extensão transfronteiriça, ocupando áreas do Brasil, Argentina, Paraguai e Uruguai. No território brasileiro, predomina em faixas extensas do Centro-Sul, com forte expressão em estados como São Paulo, Paraná, Mato Grosso do Sul, Goiás, Minas Gerais e Santa Catarina.

Sua importância ultrapassa o campo técnico, pois envolve segurança hídrica, planejamento territorial e cooperação entre países.

5.4.3 Recarga e circulação

As áreas de recarga do Guarani são especialmente sensíveis. Em geral, estão associadas a regiões de afloramento dos arenitos e a zonas de afloramento ou cobertura muito delgada. Nesses setores, a água da chuva pode infiltrar-se mais diretamente e alimentar o sistema.

Quando o sistema se encontra sob basaltos, a circulação pode ser mais lenta, com compartimentos hidráulicos e diferentes graus de confinamento. A água pode permanecer por longos períodos no subsolo, o que influencia sua composição química e seu tempo de residência.

Consequência hidroquímica

Águas subterrâneas mais antigas podem apresentar mineralização diferente da água de recarga recente. Isso é natural e deve ser considerado na interpretação de sua qualidade para abastecimento.

5.4.4 Uso para abastecimento

O Guarani é largamente utilizado para abastecimento público, industrial e, em alguns contextos, termal. Sua relevância decorre da boa produtividade de muitos setores e da possibilidade de exploração em larga escala.

No entanto, sua gestão exige cautela:

- áreas de recarga precisam ser protegidas;
- poços devem ser bem construídos e devidamente selados;
- o bombeamento precisa respeitar a capacidade do sistema;
- a qualidade da água deve ser monitorada de forma contínua;
- interferências entre poços devem ser avaliadas em escala regional.

5.4.5 Desafios de gestão

Por ser transfronteiriço e muito extenso, o Guarani exige uma visão de governança integrada. Os principais desafios incluem:

- uso intensivo em áreas urbanas e agrícolas;
- risco de contaminação em zonas de recarga;
- necessidade de compatibilizar exploração e conservação;
- monitoramento em diferentes jurisdições;
- harmonização entre informação científica e gestão pública.

Mensagem central

O Guarani é um patrimônio hidrogeológico de escala continental. Sua exploração deve ser técnica, coordenada e ambientalmente responsável.

5.5 Outros sistemas aquíferos relevantes do Brasil

Além do Guarani, o Brasil possui diversos sistemas de grande relevância regional e nacional. A Tabela 5.1 apresenta um panorama sintético.

Tabela 5.1: Principais sistemas aquíferos do Brasil e suas características gerais

Sistema aquífero	Contexto geológico	Tipo predominante	Observação geral
Guarani	arenitos sob cobertura basáltica e unidades sedimentares correlatas	sedimentar, confinado ou semi-confinado	grande importância regional e transfronteiriça
Alter do Chão	bacia sedimentar amazônica	sedimentar poroso	expressivo potencial na Amazônia, com forte relevância para abastecimento local e regional
Urucuia	grandes pacotes arenosos do interior do Brasil	sedimentar poroso	importante recarga e contribuição para vazões de base em várias bacias
Bauru–Caiuá	coberturas arenosas do interior do Sudeste e Centro-Oeste	sedimentar poroso	amplamente utilizado, porém sensível à ocupação do solo
Barreiras	depósitos sedimentares costeiros e subcosteiros	sedimentar poroso	frequente em áreas urbanas costeiras, com vulnerabilidade elevada
Bambuí e outros cársticos	rochas carbonáticas dissolvidas	cárstico	alta produtividade local, mas forte variabilidade e vulnerabilidade
Serra Geral	basaltos fraturados e vesiculares	vulcânico fraturado	produtividade dependente do fraturamento e da interseção de estruturas
Cristalino fraturado	granitos, gnaisses, migmatitos e afins	fissural	amplamente distribuído; importante em áreas semiáridas e interiores

5.5.1 Aquífero Alter do Chão

O sistema Alter do Chão ocorre na Amazônia e está associado a sedimentos arenosos de grande extensão. Em muitos locais, apresenta bom potencial de armazenamento e transmissão de água, sendo importante para abastecimento urbano e regional.

Sua relevância cresce porque a região amazônica combina grandes demandas localizadas, dificuldades logísticas e forte sensibilidade ambiental. Assim, a disponibilidade hídrica deve ser tratada com atenção à proteção da qualidade e à sustentabilidade da explotação.

5.5.2 Aquífero Urucuia

O Urucuia é um importante sistema sedimentar de arenitos, especialmente expressivo no Centro-Oeste e em áreas de transição para o semiárido. É conhecido por seu papel na manutenção de vazões de base em diversas bacias hidrográficas.

Função hidrológica

Além de fornecer água para poços, o Urucuia participa da sustentação de cursos d'água superficiais, o que o torna relevante tanto para abastecimento quanto para ecossistemas aquáticos.

5.5.3 Sistema Bauru–Caiuá

O conjunto Bauru–Caiuá é composto por sedimentos arenosos amplamente distribuídos no interior do país. Em áreas onde a cobertura é favorável e a recarga é significativa, pode fornecer vazões importantes.

Entretanto, por estar muitas vezes associado a áreas de intensa ocupação agrícola e urbana, sua vulnerabilidade pode ser elevada. A gestão desse sistema exige atenção ao uso do solo e à proteção das áreas de recarga.

5.5.4 Sistema Barreiras

Os aquíferos associados aos depósitos Barreiras são frequentes em faixas costeiras e subcosteiras, especialmente no Norte e Nordeste. Em muitos contextos, são aquíferos rasos, porosos e bastante sensíveis à ocupação urbana, à salinização e à contaminação superficial.

Atenção especial

Em áreas costeiras, a superexploração pode favorecer intrusão salina, um problema crítico para a potabilidade da água subterrânea.

5.5.5 Aquíferos cársticos carbonáticos

Os terrenos cársticos, como os associados a unidades carbonáticas do grupo Bambuí e de outras sequências, têm grande relevância para abastecimento em alguns estados. Sua produtividade pode ser muito alta, mas o comportamento hidráulico é irregular.

- podem apresentar grandes vazões localizadas;
- a água pode circular por condutos e cavidades;
- a vulnerabilidade à contaminação costuma ser elevada;
- o comportamento espacial é fortemente heterogêneo.

Paradoxo do carste

O mesmo sistema que pode produzir muita água também pode transmitir contaminantes com rapidez. Por isso, produtividade e vulnerabilidade andam juntas nesse contexto.

5.5.6 Aquíferos fissurais do embasamento cristalino

No semiárido e em outras áreas de embasamento cristalino, a água subterrânea costuma estar armazenada em fraturas, falhas, zonas de cisalhamento e manto de alteração. Esses sistemas são muito importantes para o abastecimento de pequenas e médias comunidades.

Características típicas:

- armazenamento reduzido na matriz;
- forte dependência da rede de fraturas;
- elevada variabilidade espacial de vazões;
- recarga fortemente controlada pelas chuvas e pelo relevo;
- necessidade de locação precisa dos poços.

Importância social

Em regiões semiáridas, mesmo aquíferos fissurais de produtividade modesta podem ser fundamentais para a segurança hídrica local.

5.5.7 Aquíferos associados a basaltos da Serra Geral

Os basaltos da Serra Geral podem funcionar como aquíferos importantes quando intensamente fraturados, vesiculados ou interconectados por estruturas tectônicas. Em certas áreas, sua produtividade é alta o suficiente para abastecimento público relevante.

Contudo, a exploração depende do grau de fraturamento e da presença de descontinuidades. Por isso, estudos locais são indispensáveis.

5.6 Comparação entre sistemas aquíferos

A Tabela 5.2 sintetiza diferenças importantes entre alguns sistemas brasileiros.

Tabela 5.2: Comparação conceitual entre sistemas aquíferos brasileiros

Sistema	Produtividade típica	Vulnerabilidade	Observação de gestão
Guarani	alta a muito alta em muitos setores	moderada a elevada nas áreas de recarga	requer proteção regional e controle transfronteiriço
Alter do Chão	alta em várias áreas	moderada a elevada conforme o uso do solo	importante para abastecimento amazônico
Urucuia	alta em setores arenosos	moderada	relevante para vazões de base e abastecimento
Bauru–Caiuá	moderada a alta	moderada a elevada	sensível à ocupação agrícola e urbana
Barreiras	moderada	elevada em muitos contextos costeiros	atenção à salinização e à urbanização
Bambuí cárstico	muito variável, por vezes alta	elevada	exige proteção rigorosa e mapeamento local
Cristalino fissural	baixa a moderada, muito variável	variável, geralmente moderada a elevada	depende fortemente de fraturas e locação de poços
Serra Geral	variável a alta localmente	moderada	produtividade condicionada por fraturamento

Mensagem-chave

Não existe o melhor aquífero em abstrato. Existe o aquífero mais adequado para um determinado contexto, desde que sua qualidade, vulnerabilidade e capacidade de renovação sejam compatíveis com o uso planejado.

5.7 Sistemas aquíferos e abastecimento público

A seleção de um sistema aquífero para abastecimento deve considerar:

- produtividade hidráulica;
- qualidade natural da água;
- vulnerabilidade à contaminação;

- custo de perfuração e operação;
- disponibilidade de recarga;
- interferência com outros usos;
- possibilidade de proteção da área de contribuição.

Em áreas urbanas, a proximidade de fontes poluidoras pode pesar mais do que a produtividade. Em áreas rurais, a disponibilidade e a simplicidade operacional podem ser decisivas. Em regiões semiáridas, a confiabilidade do sistema ao longo do ano é frequentemente mais importante que a vazão instantânea máxima.

Síntese para o saneamento

O abastecimento público sustentável depende de um triângulo equilibrado: quantidade, qualidade e proteção.

5.8 Desafios de gestão no Brasil

Alguns desafios se repetem em diferentes sistemas aquíferos brasileiros:

- crescimento urbano sobre áreas de recarga;
- poços mal construídos ou sem controle técnico;
- superexploração local e rebaixamento excessivo;
- contaminação difusa por agricultura e urbanização;
- ausência de monitoramento contínuo;
- fragmentação institucional entre estados e municípios;
- dificuldade de integração entre ciência e gestão.

Gestão integrada

A hidrogeologia brasileira exige planejamento em múltiplas escalas: local, municipal, regional e, em certos casos, transfronteiriça.

5.9 Exemplo resolvido

Escolha preliminar de sistema aquífero para abastecimento municipal

Uma cidade de porte médio no interior brasileiro precisa decidir entre três alternativas para ampliar seu abastecimento subterrâneo:

- **Alternativa A**: aquífero livre raso, de fácil perfuração, localizado sob área urbana densamente ocupada;

- **Alternativa B**: aquífero sedimentar profundo, com boa produtividade, localizado em área menos ocupada e com melhor proteção natural;
- **Alternativa C**: aquífero cristalino fraturado, com vazões moderadas e alta variabilidade espacial.

Análise técnica

A alternativa A pode oferecer baixo custo inicial, mas tende a apresentar maior vulnerabilidade, maior risco de contaminação e maior sensibilidade ao uso do solo urbano.

A alternativa B é, em geral, a mais equilibrada, pois combina produtividade, proteção natural e melhor possibilidade de gestão, desde que a recarga e a área de contribuição sejam bem monitoradas.

A alternativa C pode ser útil como complemento ou para comunidades menores, mas sua variabilidade hidráulica exige investigação geológica mais detalhada e pode não garantir a regularidade necessária para uma cidade média.

Conclusão

A opção mais promissora, em princípio, é a alternativa B. Contudo, a decisão final deve ser validada por estudos de campo, testes de bombeamento, análise de qualidade da água, modelagem da área de contribuição e verificação dos custos de operação e proteção.

5.10 Resumo do capítulo

Resumo do capítulo

- O Brasil possui grande diversidade hidrogeológica, com sistemas sedimentares, cársticos, vulcânicos e fissurais.
- O Sistema Aquífero Guarani é um dos mais importantes da América do Sul e exige gestão transfronteiriça.
- Alter do Chão, Urucuia, Bauru–Caiuá, Barreiras, Bambuí, Serra Geral e o embasamento cristalino são sistemas relevantes em diferentes regiões.
- Aquíferos sedimentares tendem a ser mais porosos; aquíferos fraturados dependem da rede de fraturas; aquíferos cársticos podem ser muito produtivos e muito vulneráveis.
- A produtividade não pode ser analisada sem considerar a vulnerabilidade e a proteção das áreas de recarga.
- Para abastecimento público, o melhor aquífero é aquele que equilibra quantidade, qualidade, custo e segurança.
- A gestão dos sistemas aquíferos brasileiros deve integrar ciência, proteção territorial e planejamento do saneamento ambiental.

5.11 Exercícios

Nível F — Fáceis

F1

Cite quatro grandes contextos hidrogeológicos presentes no Brasil e dê um exemplo de cada um.

F2

Defina, em linhas gerais, o que é o Sistema Aquífero Guarani.

F3

Explique por que aquíferos cársticos podem ser produtivos e, ao mesmo tempo, muito vulneráveis.

F4

Por que os aquíferos fissurais do embasamento cristalino são importantes em regiões semiáridas?

Nível M — Médios

M1

Compare os sistemas Guarani, Urucuia e Bauru–Caiuá quanto à natureza geológica, potencial de uso e vulnerabilidade.

M2

Explique por que o Sistema Aquífero Guarani exige gestão transfronteiriça e por que isso complica sua governança.

M3

Uma cidade costeira pretende ampliar sua captação subterrânea. O aquífero local é do tipo Barreiras, raso e poroso. Quais cuidados devem ser considerados antes da perfuração e da operação?

M4

Descreva três características típicas de aquíferos fissurais e explique como elas afetam o projeto de poços.

Nível D — Difíceis

D1

Compare um sistema sedimentar poroso, um sistema cárstico e um sistema cristalino fraturado do ponto de vista da produtividade, vulnerabilidade, previsibilidade espacial e estratégia de gestão.

D2

Uma região sobre o Sistema Aquífero Guarani apresenta forte expansão agrícola sobre áreas de recarga. Discuta os riscos hidrogeológicos e de saneamento ambiental e proponha medidas de proteção.

D3

Explique por que, em escala nacional, a segurança hídrica do Brasil não depende apenas de possuir grandes aquíferos, mas de saber geri-los de modo articulado com o uso do solo, a qualidade da água e a demanda social.

5.12 Gabarito comentado

Resposta ao exercício F1

Quatro contextos possíveis são:

- **sedimentar**: como o Guarani ou o Urucuia;
- **cárstico**: como sistemas carbonáticos do Bambuí;
- **fissural**: como o embasamento cristalino;
- **vulcânico fraturado**: como os basaltos da Serra Geral.

Cada um deles possui comportamento hidráulico próprio, com implicações distintas para abastecimento e proteção.

Resposta ao exercício F2

O Sistema Aquífero Guarani é um grande sistema hidrogeológico sedimentar da América do Sul, formado principalmente por arenitos e associado, em várias áreas, a cobertura basáltica. Ele se estende por Brasil, Argentina, Paraguai e Uruguai, sendo um dos principais reservatórios subterrâneos do continente.
Sua importância decorre da grande extensão, da produtividade em vários setores e do papel no abastecimento público e regional.

Resposta ao exercício F3

Aquíferos cársticos podem ser muito produtivos porque a dissolução cria condutos, cavernas e vias preferenciais de fluxo, permitindo grandes vazões. Ao mesmo tempo, essa mesma estrutura facilita a entrada rápida de contaminantes pela superfície e reduz a capacidade natural de filtração do meio.
Em resumo: a água se move muito bem no carste, mas a proteção natural é fraca.

Resposta ao exercício F4

Em regiões semiáridas, os aquíferos fissurais do embasamento cristalino são importantes porque muitas comunidades dependem deles como principal fonte subterrânea disponível. Embora o armazenamento na matriz seja pequeno, as fraturas podem concentrar água suficiente para captações locais.
Além disso, são frequentemente os aquíferos mais acessíveis em áreas onde as unidades sedimentares são escassas ou inexistentes.

Resposta ao exercício M1

O Guarani é um sistema sedimentar de grande extensão e elevada relevância regional, com produtividade alta em muitos setores e vulnerabilidade variável, especialmente maior

nas áreas de recarga.
O Urucuia também é sedimentar, com importante papel na manutenção de vazões de base e na recarga regional. O Bauru–Caiuá é igualmente sedimentar, mas costuma ser mais sensível ao uso do solo e à ocupação intensa em várias áreas.
Comparando de forma sintética:

- **Guarani**: grande escala e gestão complexa;
- **Urucuia**: forte função hidrológica regional;
- **Bauru–Caiuá**: útil e amplamente explorado, porém vulnerável em áreas ocupadas.

Resposta ao exercício M2

O Guarani é transfronteiriço porque se estende por mais de um país. Isso significa que a recarga, a explotação e a proteção não podem ser tratadas apenas por uma jurisdição nacional isolada.
A governança se complica porque:

- diferentes países têm legislações e prioridades distintas;
- os efeitos do bombeamento podem ultrapassar fronteiras;
- a proteção de áreas de recarga pode exigir coordenação internacional;
- o monitoramento precisa de padrões compatíveis.

Por isso, a gestão deve ser cooperativa e baseada em informações compartilhadas.

Resposta ao exercício M3

Antes da perfuração e da operação, devem ser considerados:

- risco de salinização e intrusão salina;
- vulnerabilidade à contaminação urbana;
- proximidade de fontes poluidoras;
- profundidade do nível d'água;
- possibilidade de proteção sanitária e de recarga;
- interferência com outras captações.

Além disso, a operação deve ser acompanhada por monitoramento de qualidade da água e do nível piezométrico, para evitar degradação do sistema.

Resposta ao exercício M4

Três características típicas são:

- baixa armazenabilidade na matriz rochosa;
- forte dependência da rede de fraturas;
- grande variabilidade espacial de vazões.

Isso afeta o projeto de poços porque a locação precisa buscar zonas fraturadas favoráveis, a profundidade deve ser escolhida com base em investigação geológica e a vazão prevista pode variar muito de um ponto para outro.

Resposta ao exercício D1

Um sistema sedimentar poroso tende a apresentar maior previsibilidade espacial e boa produtividade relativamente homogênea quando bem desenvolvido. Um sistema cárstico pode oferecer vazões muito altas, mas com extrema heterogeneidade e vulnerabilidade elevada. Um sistema cristalino fraturado costuma ter produtividade mais baixa e muito variável, dependente de estruturas geológicas locais.
Em termos de gestão:

- o sedimentar poroso exige proteção das áreas de recarga;
- o cárstico exige proteção rigorosa contra entradas rápidas de contaminantes;
- o cristalino fraturado exige boa locação de poços e expectativa realista de produtividade.

A estratégia de gestão precisa ser adaptada ao tipo de meio e não apenas ao volume de água disponível.

Resposta ao exercício D2

A expansão agrícola sobre áreas de recarga do Guarani aumenta o risco de contaminação difusa por fertilizantes, agrotóxicos e sedimentos, além de poder alterar a infiltração e a qualidade da água que alimenta o sistema. Como o Guarani é extenso e, em certas áreas, confinado, o problema se concentra especialmente nos setores de recarga e nas conexões hidráulicas com a superfície.
Medidas de proteção:

- delimitação e controle das áreas de recarga;
- boas práticas agrícolas e redução de insumos químicos;
- monitoramento de nitrato, pesticidas e condutividade;
- proteção de poços e fiscalização de captações;
- zoneamento territorial com base hidrogeológica;

- cooperação entre municípios, estados e, quando aplicável, países.

A expansão agrícola pode ser economicamente relevante, mas precisa ser compatível com a proteção do manancial subterrâneo.

Resposta ao exercício D3

Grandes aquíferos não garantem segurança hídrica por si sós. A segurança depende de como a água é captada, protegida, distribuída e monitorada. Um grande volume de água pode ser comprometido por contaminação, superexploração, salinização, poços mal construídos ou ocupação desordenada das áreas de recarga.
Portanto, a segurança hídrica exige:

- conhecimento hidrogeológico;
- gestão territorial;
- proteção sanitária;
- monitoramento de qualidade e quantidade;
- integração entre abastecimento, planejamento urbano e uso rural do solo.

Sem gestão, um grande aquífero pode deixar de ser uma garantia e se tornar um passivo.

5.13 Conexão com os apêndices

Fechamento do livro

Este capítulo encerra a parte principal do livro ao apresentar os sistemas aquíferos mais importantes do Brasil e sua relevância para o saneamento ambiental. Nos apêndices, o leitor encontrará materiais complementares de apoio, como fórmulas essenciais, unidades, conversões, valores típicos e um glossário técnico. Esses recursos foram preparados para facilitar a consulta, o estudo e a aplicação prática do conteúdo desenvolvido ao longo da obra.

A

Unidades, símbolos e conversões fundamentais

A.1 Finalidade deste apêndice

Este apêndice reúne as unidades e conversões mais úteis para o estudo e a aplicação da hidrogeologia. Ele foi preparado como uma referência rápida para exercícios, dimensionamentos preliminares, leitura de dados de campo e interpretação de resultados de testes.

Convenção geral

Sempre que possível, utilize o Sistema Internacional de Unidades. Em hidrogeologia, isso evita ambiguidades e facilita a comparação entre dados de diferentes fontes.

A.2 Símbolos e grandezas mais usados

A.3 Conversões práticas de uso frequente

A.4 Conversões de temperatura e viscosidade

Em águas subterrâneas, a temperatura influencia a viscosidade da água e, portanto, a condutividade hidráulica aparente.

- 20 °C é a temperatura de referência mais comum em muitos cálculos preliminares.
- O aumento de temperatura reduz a viscosidade e tende a aumentar a condutividade hidráulica observada.
- Em estudos comparativos, convém informar a temperatura da amostra ou da água do ensaio.

Tabela A.1: Símbolos e grandezas hidrogeológicas mais frequentes

Símbolo	Grandeza	Unidade SI usual	Observação
n	porosidade total	adimensional	fração de vazios no volume total
n_e	porosidade efetiva	adimensional	fração de poros conectados
e	índice de vazios	adimensional	relação entre volume de vazios e sólidos
K	condutividade hidráulica	m/s	depende do meio e do fluido
k	permeabilidade intrínseca	m^2	depende apenas do meio
T	transmissividade	m^2/s	$T = Kb$
S	armazenabilidade	adimensional	aquíferos confinados e semiconfinados
S_y	rendimento específico	adimensional	aquíferos livres
S_r	retenção específica	adimensional	água retida por capilaridade e adsorção
Q	vazão	m^3/s	volume por unidade de tempo
q	descarga específica	m/s	vazão por área total
v	velocidade intersticial	m/s	velocidade média no espaço poroso
h	carga hidráulica	m	energia por unidade de peso
i	gradiente hidráulico	adimensional	$\Delta h/L$
s	rebaixamento	m	diferença entre níveis d'água
C_e	capacidade específica	$m^3/(s\,m)$	ou vazão por rebaixamento
R	recarga	m ou m^3	conforme o contexto
V_R	volume recarregado	m^3	recarga integrada em uma área
R_f	fator de retardação	adimensional	para contaminantes sorvidos

Tabela A.2: Conversões úteis em hidrogeologia

Conversão	Equivalência	Comentário
1 L/s	3,6 m^3/h	vazão de bombas e poços
1 L/s	86,4 m^3/d	muito usada em testes de bombeamento
1 m^3/h	0,277 8 L/s	conversão inversa
1 m^3/s	86 400 m^3/d	vazões regionais
1 ha	10 000 m^2	áreas agrícolas e de recarga
1 km^2	1 000 000 m^2	áreas regionais
1 mm sobre 1 ha	10 m^3	recarga volumétrica rápida
1 mm sobre 1 km^2	1 000 m^3	útil em balanço hídrico
1 cm	0,01 m	leitura de campo e laboratório
1 d	86 400 s	conversão temporal
1 D	$9{,}869 \times 10^{-13}$ m^2	unidade clássica de permeabilidade

Boa prática

Quando houver dados de laboratório ou de campo com temperaturas muito diferentes, a comparação direta deve ser feita com cautela.

B

Fórmulas fundamentais da hidrogeologia

B.1 Finalidade deste apêndice

Este apêndice reúne as equações mais úteis do livro em um único lugar, organizadas por tema. Ele serve como referência de consulta rápida para exercícios, interpretação de campo e revisão conceitual.

B.2 Geometria do meio poroso

B.2.1 Porosidade

$$n = \frac{V_v}{V_t}$$

$$n(\%) = \frac{V_v}{V_t} \times 100$$

B.2.2 Índice de vazios

$$e = \frac{V_v}{V_s}$$

$$n = \frac{e}{1+e} \quad \text{e} \quad e = \frac{n}{1-n}$$

B.2.3 Rendimento específico e retenção específica

$$S_y = \frac{\text{volume de água liberado por gravidade}}{\text{volume total}}$$

$$S_r = \frac{\text{volume de água retido}}{\text{volume total}}$$

Em primeira aproximação, para um meio saturado:

$$n \approx S_y + S_r$$

B.3 Carga hidráulica e fluxo subterrâneo

B.3.1 Carga hidráulica

$$h = z + \frac{p}{\gamma_w}$$

B.3.2 Gradiente hidráulico

$$i = \frac{\Delta h}{L} = \frac{h_1 - h_2}{L}$$

B.3.3 Lei de Darcy

$$Q = -KA\frac{dh}{dl}$$

Em módulo:

$$Q = KAi$$

B.3.4 Descarga específica

$$q = \frac{Q}{A} = Ki$$

B.3.5 Velocidade intersticial média

$$v = \frac{q}{n_e} = \frac{Ki}{n_e}$$

B.3.6 Transmissividade

$$T = Kb$$

B.3.7 Relação entre condutividade hidráulica e permeabilidade intrínseca

$$K = \frac{k\rho g}{\mu}$$

$$k = \frac{K\mu}{\rho g}$$

B.4 Aquíferos e armazenamento

B.4.1 Armazenabilidade

Para aquíferos confinados:

$$S = S_s b$$

em que S_s é o armazenamento específico.

B.4.2 Armazenamento específico

$$S_s = \frac{\text{água liberada ou armazenada}}{\text{volume total} \times \text{variação de carga}}$$

Essa expressão é conceitual e ajuda a interpretar a origem da água mobilizada no aquífero confinado.

B.5 Recarga e balanço hídrico

B.5.1 Balanço hídrico simplificado

$$P = ET + Q_s + R + \Delta S$$

$$R = P - ET - Q_s - \Delta S$$

Quando ΔS é pequeno:

$$R \approx P - ET - Q_s$$

B.5.2 Coeficiente de recarga

$$C_R = \frac{R}{P}$$

B.5.3 Recarga por flutuação do nível freático

$$r = S_y \Delta h$$

$$V_R = S_y \Delta h A$$

B.6 Poços e dimensionamento

B.6.1 Rebaixamento

$$s = ND - NE$$

B.6.2 Capacidade específica

$$C_e = \frac{Q}{s}$$

B.6.3 Altura manométrica total

$$H_{MT} = H_g + s + h_f + h_p$$

B.6.4 Potência hidráulica

$$P_h = \rho g Q H_{MT}$$

B.6.5 Potência no eixo

$$P = \frac{\rho g Q H_{MT}}{\eta}$$

B.7 Ensaios de bombeamento

B.7.1 Solução de Theis

$$s(r,t) = \frac{Q}{4\pi T} W(u)$$

com

$$u = \frac{r^2 S}{4Tt}$$

B.7.2 Aproximação de Cooper-Jacob

$$s = \frac{2.3Q}{4\pi T} \log_{10}\left(\frac{2.25Tt}{r^2 S}\right)$$

$$T = \frac{0.183Q}{\Delta s}$$

quando Q é expresso em m^3/d e Δs corresponde ao rebaixamento por ciclo logarítmico de tempo.

B.7.3 Estimativa de armazenabilidade por intercepto

$$S = \frac{2.25Tt_0}{r^2}$$

B.7.4 Ensaio escalonado

$$s = BQ + CQ^2$$

$$\frac{s}{Q} = B + CQ$$

B.7.5 Eficiência de poço

$$E = \frac{BQ}{s} \times 100$$

B.8 Contaminação e transporte

B.8.1 Velocidade do contaminante conservativo

$$v_c \approx v$$

B.8.2 Fator de retardação

$$R_f = 1 + \frac{\rho_b K_d}{n_e}$$

B.8.3 Velocidade do contaminante sorvido

$$v_c = \frac{v}{R_f}$$

B.9 Observações de uso

Antes de aplicar qualquer fórmula

Verifique sempre:

- se a unidade está correta;
- se o sistema é saturado ou não;
- se o meio pode ser tratado como contínuo;
- se os dados correspondem ao aquífero, ao poço ou ao ensaio;
- se as hipóteses do modelo são compatíveis com o problema real.

C

Valores típicos de parâmetros hidrogeológicos

C.1 Finalidade deste apêndice

Os valores listados aqui são ordens de grandeza úteis para interpretação preliminar. Eles não substituem medições locais, mas ajudam o leitor a identificar se um resultado está dentro do esperado para determinado material ou tipo de aquífero.

Cuidado com a generalização

A variabilidade natural é grande. Os valores abaixo devem ser lidos como faixas indicativas, não como constantes universais.

C.2 Materiais geológicos e propriedades típicas

C.3 Valores típicos de parâmetros de aquíferos

C.4 Valores orientativos de transmissividade

C.5 Indicadores de qualidade da água subterrânea

C.6 Leitura prática dos valores

- **Argila**: armazena água, mas libera muito pouco.
- **Areia grossa**: costuma ser excelente para captação.
- **Carste**: pode ser extremamente produtivo, porém vulnerável.
- **Cristalino fraturado**: depende fortemente de fraturas e da locação do poço.

Tabela C.1: Valores típicos de porosidade e condutividade hidráulica em materiais geológicos

Material	Porosidade total típica	Condutividade hidráulica saturada típica	Comentário
Argila	40 % a 70 %	de 10^{-12} a 10^{-9} m/s	alta retenção de água e baixa transmissão
Silte	35 % a 50 %	de 10^{-10} a 10^{-6} m/s	comportamento intermediário
Areia fina	25 % a 40 %	de 10^{-6} a 10^{-4} m/s	boa combinação entre armazenamento e fluxo
Areia grossa	20 % a 35 %	de 10^{-4} a 10^{-1} m/s	muito favorável à explotação
Cascalho	15 % a 30 %	de 10^{-3} a 10^{-1} m/s	alta transmissividade em depósitos soltos
Arenito pouco cimentado	10 % a 30 %	de 10^{-7} a 10^{-3} m/s	depende da cimentação e da seleção
Arenito bem cimentado	5 % a 15 %	de 10^{-10} a 10^{-6} m/s	porosidade reduzida e fluxo restrito
Calcário carstificado	muito variável	pode ser muito elevada em condutos	forte heterogeneidade espacial
Basalto fraturado	muito variável	de muito baixa a alta, conforme fraturas	depende da densidade de descontinuidades
Cristalino fraturado	muito variável	muito variável, geralmente baixa a moderada	controle estrutural dominante

Tabela C.2: Parâmetros típicos de aquíferos segundo o tipo de confinamento

Tipo de aquífero	Armazenabilidade típica	Rendimento específico típico	Observação
Livre	ordem de 10^{-1} a 10^{-2}	0,05 a 0,30	drenagem gravitacional domina a resposta
Confinado	ordem de 10^{-5} a 10^{-3}	muito baixo ou não aplicável	resposta depende da compressibilidade
Semiconfinado	entre os dois anteriores	intermediário	vazamento vertical altera o comportamento
Cárstico	muito variável	muito variável	condutos podem dominar a resposta
Fissural cristalino	muito variável	geralmente baixo a intermediário	controle da rede de fraturas

Tabela C.3: Ordens de grandeza de transmissividade para leitura preliminar

Faixa de T	Interpretação geral	Exemplo de meio
Menor que 10^{-5} m²/s	muito baixa transmissividade	argilas, siltes muito finos
10^{-5} a 10^{-3} m²/s	baixa a moderada transmissividade	siltes, arenitos mais fechados
10^{-3} a 10^{-1} m²/s	boa transmissividade	areias, cascalhos, alguns arenitos
Maior que 10^{-1} m²/s	muito alta transmissividade	sistemas muito produtivos ou condutos

Tabela C.4: Indicadores comuns em monitoramento hidroquímico

Indicador	O que pode sugerir	Observação
Nitrato	influência de esgoto, fertilizantes ou dejetos animais	marcador importante de recarga contaminada
Cloreto	aporte antrópico, salinização ou mistura de águas	útil como traçador conservativo
Coliformes	contaminação sanitária recente ou falhas de proteção	exige resposta rápida
Condutividade elétrica	mineralização, salinidade ou mistura de águas	varia com composição iônica
Ferro e manganês	condições redutoras ou dissolução geoquímica	comuns em certos aquíferos
BTEX e solventes	combustíveis ou atividades industriais	indicam fontes pontuais

Regra de ouro

Se um valor de campo parecer incompatível com a litologia conhecida, investigue a amostragem, a escala de observação e a possibilidade de heterogeneidade local.

D

Glossário técnico

D.1 Finalidade deste apêndice

Este glossário reúne termos essenciais empregados ao longo do livro. As definições foram redigidas em linguagem técnica, porém acessível, para apoiar a leitura, a revisão e a aplicação prática do conteúdo.

Advecção transporte de substâncias dissolvidas acompanhando o movimento da água subterrânea.

Aquífero formação geológica capaz de armazenar e transmitir água em quantidades significativas.

Aquífero confinado aquífero limitado por camadas de baixa permeabilidade, no qual a água está sob pressão.

Aquífero livre aquífero cujo limite superior é a superfície freática, com pressão atmosférica nessa interface.

Aquífero semiconfinado aquífero com camada de baixa permeabilidade que permite vazamento vertical, mas não isola totalmente o sistema.

Aquitardo unidade de baixa permeabilidade que transmite água lentamente.

Aquiclude termo tradicional para unidade praticamente impermeável; em uso moderno, emprega-se com cautela.

Armazenabilidade fração de água liberada ou armazenada por variação de carga hidráulica em um aquífero.

Capacidade específica relação entre vazão bombeada e rebaixamento correspondente.

Condutividade hidráulica
propriedade que expressa a facilidade de passagem da água por um meio saturado.

Contaminação alteração da qualidade natural da água por substâncias, microrganismos ou energia em condições incompatíveis com o uso.

Descarga específica
vazão por unidade de área total da seção transversal.

Difusão movimento molecular de regiões de maior concentração para regiões de menor concentração.

Dispersão espalhamento de contaminantes causado pela heterogeneidade dos caminhos de fluxo e pela variação de velocidades locais.

Eficiência de poço
medida da parcela do rebaixamento atribuída às perdas no aquífero em relação ao rebaixamento total.

Evapotranspiração
perda combinada de água por evaporação e transpiração vegetal.

Fator de retardação
fator que expressa o atraso no movimento de um contaminante em relação à água.

Fluxo laminar regime de escoamento em que as trajetórias são ordenadas e a relação entre vazão e gradiente tende a ser linear.

Gradiente hidráulico
diferença de carga hidráulica dividida pelo comprimento do trajeto de fluxo.

Infiltração entrada da água na superfície do solo.

Índice de vazios
razão entre volume de vazios e volume de sólidos.

Lei de Darcy relação que descreve o fluxo de água em meio poroso saturado em função da condutividade hidráulica e do gradiente hidráulico.

Nível dinâmico posição da água no poço durante o bombeamento.

Nível estático posição da água no poço em repouso, sem bombeamento.

Porosidade razão entre volume de vazios e volume total do material.

Porosidade efetiva
fração de vazios interligados que participam do escoamento.

Porosidade total
fração de vazios totais, conectados ou não.

Permeabilidade intrínseca
propriedade do meio relacionada à geometria e à conectividade dos vazios, independente do fluido.

Poluição contaminação com efeito concreto e indesejável sobre o uso humano, ambiental ou produtivo da água.

Potência hidráulica
energia por unidade de tempo necessária para elevar uma vazão a determinada altura manométrica.

Recarga fração da água que atravessa a zona não saturada e alcança a zona saturada.

Recarga artificial
recarga promovida intencionalmente por obras de engenharia.

Recarga difusa recarga distribuída de forma ampla sobre a superfície.

Recarga induzida
recarga causada pela redução de carga hidráulica decorrente de bombeamento.

Retenção específica
fração de água retida no meio por forças capilares e de adsorção.

Rebaixamento diferença entre o nível dinâmico e o nível estático.

Rendimento específico
fração do volume total liberada por gravidade em aquíferos livres.

Risco hidrogeológico
combinação de fonte de ameaça, vulnerabilidade e exposição de receptores.

Sorção interação de um soluto com a fase sólida do meio, incluindo adsorção e partição.

Superfície freática
limite superior da zona saturada em aquíferos livres.

Superfície potenciométrica
nível até o qual a água sobe em um piezômetro instalado em aquífero confinado ou semiconfinado.

Transmissividade
capacidade integrada de uma unidade aquífera de transmitir água ao longo de sua espessura saturada.

Vazão volume de água que atravessa uma seção por unidade de tempo.

Velocidade intersticial
velocidade média da água apenas nos poros conectados.

Vulnerabilidade predisposição natural do aquífero a ser afetado por contaminantes.

Vulnerabilidade intrínseca
vulnerabilidade determinada pelas características naturais do meio, independentemente do contaminante específico.

Vulnerabilidade específica
vulnerabilidade considerada em relação a um contaminante determinado.

Zona de contribuição
área do aquífero que alimenta hidraulicamente um poço ou sistema de captação.

Zona de proteção
área em que se impõem restrições de uso para preservar a qualidade e a disponibilidade da água subterrânea.

Zona não saturada
faixa do subsolo situada entre a superfície do terreno e o nível freático, onde coexistem água e ar.

Zona saturada região do subsolo em que os vazios estão preenchidos por água.

D.2 Observação final

Como usar o glossário

Quando surgir um termo novo durante a leitura dos capítulos, retorne a este apêndice e compare a definição com o contexto em que ele foi empregado. Em hidrogeologia, muitos termos parecem semelhantes, mas possuem implicações muito diferentes na prática.

E

Checklist de campo, projeto e operação

E.1 Finalidade deste apêndice

Este apêndice foi pensado como ferramenta prática para estudos de campo, elaboração de projetos e rotinas de operação de poços. O objetivo é transformar conceitos hidrogeológicos em verificação objetiva.

E.2 Checklist para seleção de área

E.2.1 Antes da perfuração

- O aquífero alvo foi identificado com base em dados geológicos e hidrogeológicos?
- A profundidade do nível d'água foi estimada?
- A direção do fluxo subterrâneo foi considerada?
- Foram mapeadas fontes potenciais de contaminação?
- A área de recarga ou de contribuição foi avaliada?
- Há possibilidade de delimitar zona de proteção?
- A acessibilidade para perfuração, manutenção e operação está assegurada?

Se algum item for negativo

Rever o estudo preliminar antes de perfurar. Um bom diagnóstico inicial evita erros caros e difíceis de corrigir.

E.3 Checklist para projeto do poço

E.3.1 Concepção e dimensionamento

- O tipo de poço é compatível com o aquífero?

- O diâmetro previsto permite instalação, operação e manutenção?
- A profundidade alcança o intervalo mais produtivo?
- O revestimento é compatível com a estabilidade da perfuração?
- O filtro tem abertura adequada à granulometria da formação?
- Existe pré-filtro ou pacote filtrante compatível?
- A laje sanitária está prevista no projeto?
- O cabeçote será protegido contra entrada de água superficial?

E.4 Checklist para construção

E.4.1 Durante a perfuração

- O registro litológico está sendo documentado?
- Há controle de perdas, desmoronamentos ou mudanças bruscas de material?
- Os intervalos produtivos foram identificados?
- O revestimento foi instalado corretamente?
- O filtro foi posicionado no intervalo mais favorável?
- O espaço anular recebeu o tratamento adequado?

E.5 Checklist para desenvolvimento e limpeza

E.5.1 Após a perfuração

- O poço foi desenvolvido adequadamente?
- Foram removidos finos e materiais indesejáveis?
- A produção de areia está dentro de limites aceitáveis?
- A água foi limpa ou estabilizada antes do teste final?
- Houve desinfecção quando necessária?

E.6 Checklist para ensaio de bombeamento

E.6.1 Campo e medição

- O nível estático foi medido antes do bombeamento?
- A vazão foi monitorada com instrumento confiável?
- O tempo de início foi registrado com precisão?
- Os níveis foram medidos em intervalos adequados?
- Houve poços de observação, quando possível?
- Foram anotadas interferências externas, como chuva ou falha elétrica?
- A recuperação foi acompanhada após o desligamento?

E.7 Checklist para operação

E.7.1 Rotina de abastecimento

- O nível dinâmico permanece acima da submersão mínima da bomba?
- A vazão está dentro da faixa de exploração segura?
- A qualidade da água está sendo monitorada periodicamente?
- Há sinais de areia, incrustação ou corrosão?
- O entorno do poço está limpo e protegido?
- A vedação da boca e do espaço anular estão preservadas?
- Há controle de acesso à área imediata?

Regra operacional

Se a qualidade da água piorar ou o rebaixamento aumentar progressivamente, o poço deve ser reavaliado antes que ocorram danos estruturais ou sanitários.

E.8 Checklist de proteção sanitária

- Existe laje sanitária com caimento adequado?
- A boca do poço está elevada e bem vedada?
- O cercamento impede acesso indevido?
- Há afastamento seguro de fossas, efluentes, combustíveis e resíduos?
- A drenagem superficial evita acúmulo de água ao redor da captação?

- A área de contribuição possui controle mínimo de uso do solo?

E.9 Checklist resumido para revisão final

Antes de considerar um poço apto para produção regular, confirme:

- viabilidade hidrogeológica;
- integridade construtiva;
- desempenho hidráulico;
- proteção sanitária;
- monitoramento de qualidade;
- compatibilidade entre vazão e demanda;
- sustentabilidade do aquífero;
- adequação ao saneamento ambiental.

Síntese final

Este checklist não substitui o projeto técnico, mas ajuda a reduzir omissões e a organizar a tomada de decisão em campo.

Referências

E.10 Básica

- FEITOSA, F. A. C. et al. (org.). *Hidrogeologia: Conceitos e Aplicações*. 3. ed. Rio de Janeiro: CPRM/LABHID, 2008.
- FREEZE, R. A.; CHERRY, J. A. *Groundwater*. New Jersey: Prentice Hall, 1979.
- REBOUÇAS, A. C.; BRAGA, B.; TUNDISI, J. G. *Águas Doces no Brasil*. 3. ed. São Paulo: Escrituras, 2006.

E.11 Complementar

- HEATH, R. C. *Basic Ground-Water Hydrology*. USGS Water Supply Paper 2220, 1983.
- BRASIL. Lei n. 9.433, de 8 de janeiro de 1997. Institui a Política Nacional de Recursos Hídricos, cria o Sistema Nacional de Gerenciamento de Recursos Hídricos, regulamenta o inciso XIX do art. 21 da Constituição Federal e altera o art. 1º da Lei n. 8.001, de 13 de março de 1990, que modificou a Lei n. 7.990, de 28 de dezembro de 1989. *Diário Oficial da União*, Brasília, DF, 9 jan. 1997.

E.12 Observação final

Uso das referências

Esta lista reúne as obras-base para o estudo da hidrogeologia no contexto do saneamento ambiental. Elas sustentam os conceitos desenvolvidos ao longo do livro e devem ser consultadas para aprofundamento teórico e aplicação prática.