Curso de Saneamento Ambiental

Projeto, Construção e Operação de Açudes

Dimensionamento, construção e operação de barragens de terra e açudes no contexto semiárido

Equipe técnica de Saneamento Ambiental

Sumário

I Fundamentos e decisão de implantação **1**

1 Açudes, barragens e o semiárido **2**

1.1 O semiárido e a lógica do armazenamento 2

1.1.1 A sazonalidade como dado de projeto 3

1.1.2 Usos múltiplos e conflitos 3

1.2 Conceitos básicos 4

1.3 Tipos principais de barragens 4

1.3.1 Barragens de terra 4

1.3.2 Barragens de enrocamento 5

1.3.3 Barragens de concreto 5

1.4 Componentes essenciais de um açude 7

1.5 Princípios de boa concepção 7

1.6 Resumo do capítulo 9

1.7 Exercícios 9

1.8 Gabarito comentado 10

2 Estudo de viabilidade e seleção do local **12**

2.1 O que é um estudo de viabilidade 12

2.2 Etapas do reconhecimento inicial 13

2.2.1 Levantamento documental e cartográfico 13

2.2.2 Visita de campo 14

2.3 Critérios técnicos de seleção do local 14

2.3.1 Critério hidrológico 14

2.3.2 Critério topográfico 15

2.3.3 Critério geológico e geotécnico 15

2.3.4 Critério de disponibilidade de materiais 16

2.3.5 Critério ambiental 16

2.3.6 Critério social 16

2.3.7 Critério construtivo e logístico 17

2.4 Seleção do eixo da barragem 17

2.4.1 Boas práticas na definição do eixo 17
2.5 Análise preliminar de alternativas 18
2.6 Pré-viabilidade técnico-econômica 19
2.7 Fluxo lógico da tomada de decisão 19
2.8 Resumo do capítulo 19
2.9 Exercícios 20
2.10 Gabarito comentado 21

II Projeto hidrológico e hidráulico 23

3 Hidrologia aplicada a açudes e reservatórios 24
3.1 A bacia hidrográfica como unidade de resposta 25
3.1.1 Fatores que controlam a resposta hidrológica 25
3.1.2 Perdas hidrológicas 25
3.2 Vazão de projeto, cheia de projeto e período de retorno 26
3.2.1 Métodos preliminares de estimativa de vazão 26
3.3 Curvas cota-área, cota-volume e cota-volume-área 27
3.3.1 Conceitos básicos 27
3.3.2 Por que essas curvas são essenciais 28
3.3.3 Como construir a curva 28
3.4 Exemplo didático de construção da curva 29
3.5 Indicadores derivados da curva 30
3.6 Interpretação hidrológica no contexto semiárido 30
3.6.1 Armazenar mais não é sempre armazenar melhor 31
3.6.2 Hidrologia e tomada de decisão 31
3.7 Resumo do capítulo 32
3.8 Exercícios 32
3.9 Gabarito comentado 33

4 Vertedores e dissipação de energia 35
4.1 Função hidráulica do vertedor 36
4.1.1 Níveis hidráulicos associados ao vertedor 36
4.2 Tipos de vertedores 36
4.2.1 Vertedor de soleira livre 37
4.2.2 Vertedor lateral 37
4.2.3 Vertedor em canal revestido 37
4.2.4 Vertedor em queda livre ou salto 37
4.3 Noções preliminares de dimensionamento 37
4.3.1 Implicações práticas 38
4.4 Erosão, galgamento e falhas associadas 39
4.4.1 Galgamento 39

4.4.2 Erosão regressiva 39
4.5 Dissipação de energia 39
4.5.1 Objetivos da dissipação 40
4.5.2 Formas usuais de dissipação 40
4.5.3 Relação entre vertedor e dissipador 40
4.6 Critérios básicos de verificação 41
4.7 Vertedores no contexto semiárido 41
4.8 Resumo do capítulo 42
4.9 Exercícios 42
4.10 Gabarito comentado 43

III Construção, instrumentação e segurança 45

5 Construção de barragens de terra 46
5.1 Da concepção ao canteiro 46
5.1.1 Planejamento da obra 47
5.1.2 A obra como sistema de etapas 47
5.2 Materiais de empréstimo e zonamento do maciço 48
5.2.1 Materiais usuais 48
5.2.2 Critérios de seleção do material 48
5.2.3 Zonamento 49
5.3 Preparação da fundação 49
5.3.1 Limpeza e decapagem 49
5.3.2 Tratamento da base 49
5.3.3 Encontros com ombreiras 50
5.4 Compactação e controle da umidade 50
5.4.1 Conceito de compactação 50
5.4.2 Umidade ótima e massa específica seca máxima 51
5.4.3 Espessura de camada e equipamento 51
5.4.4 Sequência prática de compactação 51
5.5 Proteções internas e superficiais 52
5.5.1 Filtros 52
5.5.2 Drenos 52
5.5.3 Proteção dos taludes 53
5.6 Controle tecnológico da obra 53
5.6.1 Principais controles em campo 53
5.6.2 O que o controle busca evitar 53
5.7 Sequência executiva recomendada 54
5.8 Patologias construtivas mais comuns 54
5.9 Construção no contexto semiárido 55

5.10 Resumo do capítulo 57
5.11 Exercícios 57
5.12 Gabarito comentado 58

6 Instrumentação, inspeção e segurança de barragens 60
6.1 Por que monitorar a barragem 60
6.2 Instrumentação básica em açudes e pequenas barragens 61
6.2.1 Piezômetros 61
6.2.2 Marcos superficiais 62
6.2.3 Medição de vazão de percolação 62
6.2.4 Régua linimétrica ou escala de nível 62
6.3 Inspeção visual: o primeiro sensor da barragem 63
6.3.1 O que observar 63
6.3.2 Inspeção de rotina e inspeção especial 64
6.4 Sinais de anomalia e interpretação preliminar 64
6.4.1 Anomalias comuns 66
6.4.2 O que mais preocupa 66
6.5 Segurança de barragens e enquadramento legal 66
6.5.1 Elementos centrais da gestão de segurança 66
6.5.2 Categoria de risco e dano potencial associado 67
6.6 Plano de segurança, rotina de inspeção e resposta a emergências . . 67
6.6.1 Conteúdo essencial de um plano de segurança 67
6.6.2 Resposta a anomalias 67
6.7 Integração entre instrumentação e operação 68
6.7.1 Exemplos de integração 68
6.8 Resumo do capítulo 69
6.9 Exercícios 69
6.10 Gabarito comentado 70

IV Operação e convivência 72

7 Operação e manutenção de açudes 73
7.1 Operar um açude é tomar decisões continuamente 74
7.1.1 Funções centrais da operação 74
7.2 Controle de níveis e regras operacionais 74
7.2.1 Faixas de operação 74
7.2.2 A lógica da descida e da recomposição 75
7.3 Balanço hídrico simplificado do reservatório 75
7.3.1 Evaporação 76
7.3.2 Infiltração e percolação 76
7.4 Usos múltiplos e prioridade de atendimento 76

7.4.1 Principais usos 76
7.4.2 Critérios de prioridade 77
7.5 Manutenção: preservar a função ao longo do tempo 77
7.5.1 Manutenção preventiva típica 78
7.5.2 Manutenção corretiva típica 78
7.5.3 Manutenção emergencial 78
7.6 Sedimentação e assoreamento 79
7.6.1 Como o assoreamento afeta o açude 79
7.6.2 Medidas de controle do assoreamento 79
7.7 Qualidade da água e operação 79
7.7.1 Fatores que afetam a qualidade 80
7.7.2 Boas práticas operacionais 80
7.8 Operação em estiagem e em eventos de cheia 80
7.8.1 Durante a estiagem 80
7.8.2 Durante chuvas e enchentes 81
7.9 Rotina de manutenção recomendada 81
7.10 Resumo do capítulo 82
7.11 Exercícios 82
7.12 Gabarito comentado 83

8 Convivência com o semiárido: cisternas e barragens subterrâneas 85
8.1 A lógica da convivência com o semiárido 86
8.2 Cisternas: armazenamento próximo do consumo 86
8.2.1 Princípio de funcionamento 87
8.2.2 Tipos mais comuns 87
8.2.3 Componentes básicos 87
8.2.4 Aspectos de qualidade da água 88
8.3 Barragens subterrâneas: água guardada no subsolo raso 89
8.3.1 Como funcionam 89
8.3.2 Condições favoráveis 89
8.3.3 Componentes usuais 89
8.3.4 Vantagens e limitações 90
8.4 Complementaridade com os açudes 90
8.4.1 Como as soluções se combinam 91
8.4.2 Aplicação por contexto 92
8.5 Gestão comunitária e manutenção 92
8.5.1 Pontos críticos de gestão 92
8.5.2 Educação e apropriação social 92
8.6 Qualidade da água e riscos sanitários 93
8.6.1 Riscos mais comuns 93

8.6.2 Boas práticas sanitárias . . . 93
8.7 Resumo do capítulo . . . 94
8.8 Exercícios . . . 94
8.9 Gabarito comentado . . . 95

V Integração aplicada 97

9 Estudo de caso integrador 98
9.1 Estudo de caso didático . . . 98
9.1.1 Contexto territorial . . . 98
9.1.2 Dados iniciais do problema . . . 99
9.2 Leitura integrada da situação . . . 99
9.3 Estimativa hidrológica preliminar . . . 101
9.3.1 Cheia de projeto preliminar . . . 101
9.4 Solução de projeto proposta . . . 101
9.4.1 Tipologia principal . . . 101
9.4.2 Vertedor e dissipação . . . 102
9.4.3 Níveis operacionais . . . 102
9.4.4 Instrumentação mínima . . . 103
9.5 Construção e controle tecnológico . . . 103
9.6 Operação e manutenção do caso . . . 104
9.7 Complementação com cisternas e barragens subterrâneas . . . 104
9.8 Síntese final da solução . . . 105
9.9 Resumo do capítulo . . . 105
9.10 Exercícios . . . 106
9.11 Gabarito comentado . . . 107

A Checklist de projeto e seleção do local 109
A.1 Finalidade do checklist . . . 109
A.2 Roteiro de reconhecimento inicial . . . 109
A.3 Critérios que exigem atenção especial . . . 109
A.4 Sequência mínima de decisão . . . 109

B Checklist de construção, inspeção e manutenção 111
B.1 Finalidade do checklist . . . 111
B.2 Antes do início da obra . . . 111
B.3 Durante a execução . . . 111
B.4 Após a conclusão da obra . . . 112
B.5 Inspeção de rotina . . . 112
B.6 Periodicidade sugerida . . . 113
B.7 Conexão entre manutenção e segurança . . . 113

C Fórmulas e relações úteis 114
C.1 Objetivo 114
C.2 Símbolos mais usuais 114
C.3 Relações hidrológicas e hidráulicas 114
C.3.1 Método racional 114
C.3.2 Vertedor de soleira livre 115
C.3.3 Curva cota-volume-área 115
C.3.4 Volume entre cotas sucessivas 115
C.3.5 Grau de compactação 115
C.3.6 Balanço hídrico simplificado 115
C.4 Leitura prática das fórmulas 116
C.5 Resumo final do apêndice 116

Referências 117

Lista de Figuras

1.1 Visão sistêmica simplificada de um açude como infraestrutura de armazenamento sazonal. 2
1.2 Esquema conceitual de uma barragem de terra com reservatório e vertedor independente. 7

2.1 Sequência lógica da decisão de implantação de um açude. 12
2.2 Fluxo simplificado da tomada de decisão na seleção do local. 20

3.1 Cadeia hidrológica simplificada que liga a chuva ao armazenamento e à operação do açude. 24
3.2 Curva cota-volume acumulado para o exemplo simplificado da Tabela 3.2. . 30

4.1 Esquema conceitual de vertedor e bacia de dissipação em uma barragem de terra. 35

5.1 Esquema conceitual de uma barragem de terra zonada, com núcleo impermeável, filtros e drenagem de pé. 47
5.2 Sequência simplificada de execução de uma barragem de terra. 55

6.1 Instrumentos e pontos de observação típicos em uma barragem de terra. . 61

7.1 Ciclo simplificado de operação e manutenção de um açude ao longo da vida útil. 73

8.1 Visão integrada: cisternas, barragens subterrâneas e açudes como partes complementares da convivência com o semiárido. 86
8.2 Esquema simplificado de uma cisterna de captação de água de chuva com descarte da primeira água. 88
8.3 Esquema simplificado de barragem subterrânea em vale aluvial. 90

9.1 Fluxo lógico de um projeto integrador de açude no semiárido. 99

Lista de Tabelas

1.1 Comparação sintética entre as principais tipologias de barragens 6

2.1 Critérios usuais para comparação preliminar de alternativas de implantação 18

3.1 Métodos usuais de estimativa preliminar de vazões em bacias contribuintes 27
3.2 Exemplo simplificado de levantamento cota-área-volume 29

4.1 Comparação sintética entre tipos de vertedor 38
4.2 Soluções usuais de dissipação de energia 40

5.1 Equipamentos usuais de compactação e aplicações típicas 52
5.2 Controles tecnológicos usuais na construção de barragens de terra 54
5.3 Patologias construtivas, causas prováveis e prevenção 56

6.1 Principais instrumentos e sua função em barragens de terra 63
6.2 Exemplo de rotina de inspeção por tipo de evento 65
6.3 Sinais de anomalia, possíveis causas e implicações 65

7.1 Exemplo de rotina de manutenção em açudes 81

8.1 Comparação entre cisternas, barragens subterrâneas e açudes 91

9.1 Dados preliminares do caso didático 100
9.2 Síntese do estudo de caso e da solução adotada 105

A.1 Checklist preliminar para seleção do local 110

B.1 Checklist simplificado de inspeção periódica 112
B.2 Rotina sugerida de manutenção e observação 113

C.1 Símbolos e unidades de referência 114

Parte I

Fundamentos e decisão de implantação

Capítulo 1

Açudes, barragens e o semiárido

Objetivos de aprendizagem

Ao final deste capítulo, espera-se que o leitor seja capaz de:

- distinguir com precisão os conceitos de barragem, reservatório e açude;
- compreender por que o armazenamento de água é estratégico no semiárido;
- reconhecer as principais tipologias de barragens: terra, enrocamento e concreto;
- identificar os componentes essenciais de um sistema de açude;
- relacionar a escolha da tipologia às condições locais, ao uso pretendido e à segurança da obra.

A construção de açudes, no contexto do semiárido, não é apenas uma resposta à escassez hídrica. Ela representa uma forma de organizar o tempo da água: captar em poucos eventos de chuva e disponibilizar durante longos períodos secos. Por isso, o açude deve ser compreendido como uma infraestrutura de adaptação territorial, e não apenas como uma obra de retenção.

Em saneamento ambiental, essa visão é essencial. O reservatório precisa atender usos múltiplos, operar com segurança, resistir ao clima e permanecer funcional ao longo do tempo. Antes de discutir seleção de local, hidrologia ou dimensionamento, é indispensável consolidar a base conceitual: o que é um açude, como ele se relaciona com a barragem que o forma e quais tipologias de barragem são mais usadas em diferentes situações.

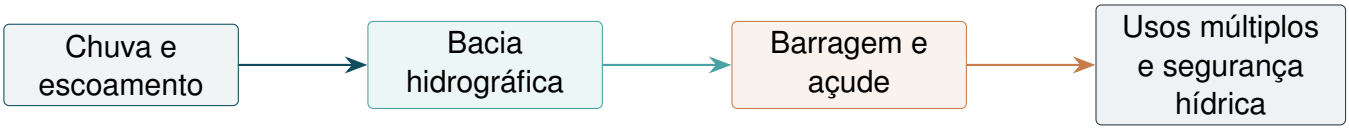

Figura 1.1 – Visão sistêmica simplificada de um açude como infraestrutura de armazenamento sazonal.

1.1 O semiárido e a lógica do armazenamento

O semiárido brasileiro é marcado por chuva irregular, forte concentração das precipitações em poucos meses, elevada demanda evaporativa e cursos d'água muitas vezes intermitentes. Em termos práticos, isso significa que a água chega em pulsos curtos, mas a necessidade

de uso é contínua ao longo do ano. O açude nasce exatamente dessa assimetria: ele transforma um regime natural instável em disponibilidade hídrica mais previsível.

1.1.1 A sazonalidade como dado de projeto

Em regiões semiáridas, não basta contabilizar a chuva anual. É preciso entender sua distribuição no tempo, a resposta da bacia hidrográfica, a capacidade de armazenamento e as perdas por evaporação e infiltração. Um reservatório eficiente não é aquele que apenas acumula muita água em períodos chuvosos; é aquele que consegue manter função útil durante a estiagem, com segurança e com uso racional.

A lógica do armazenamento sazonal é simples e, ao mesmo tempo, decisiva: captar excedentes em um curto intervalo e redistribuí-los ao longo de meses de escassez. Isso vale tanto para abastecimento humano quanto para dessedentação animal, irrigação complementar, usos comunitários e eventual regularização de vazões locais.

1.1.2 Usos múltiplos e conflitos

No semiárido, o açude raramente atende apenas um usuário. Em geral, ele está associado a diferentes demandas:

- consumo humano, direto ou tratado;
- dessedentação animal;
- irrigação complementar em pequena escala;
- piscicultura ou usos produtivos compatíveis;
- reserva estratégica para períodos críticos;
- apoio à convivência comunitária com a seca.

Quanto maior a diversidade de usos, maior a necessidade de regras operacionais, monitoramento e gestão. Um açude não é apenas uma reserva volumétrica; ele é também um ponto de decisão sobre prioridade de uso, conservação da qualidade da água e distribuição do recurso ao longo do tempo.

Água armazenada não é água disponível em qualquer condição

A presença de volume armazenado não garante, por si só, disponibilidade segura para qualquer finalidade. A qualidade da água, o nível operacional, as perdas por evaporação e a necessidade de manter margem de segurança hidráulica devem ser considerados desde a concepção do empreendimento.

1.2 Conceitos básicos

Terminologia essencial

- **Barragem**: estrutura transversal construída para reter, elevar ou controlar o escoamento de um curso d'água.
- **Reservatório**: volume de água acumulado a montante da barragem.
- **Açude**: denominação corrente, especialmente no Nordeste do Brasil, para o reservatório formado por uma barragem destinada ao armazenamento de água.
- **Vertedor**: estrutura de segurança destinada a conduzir vazões excedentes sem comprometer a barragem.
- **Descarga de fundo**: dispositivo hidráulico localizado em cota inferior, usado para esvaziamento controlado, operação e manejo de sedimentos.

Açude não é sinônimo de barragem

Na linguagem técnica, a **barragem** é a obra física que intercepta o curso d'água; o **açude** é o reservatório resultante do represamento. Embora no uso corrente os termos apareçam misturados, essa distinção é importante porque o projeto precisa tratar, ao mesmo tempo, a estrutura e o volume de água que ela cria.

Leitura prática da distinção

Dizer que um município possui um grande açude não significa apenas que existe uma barragem elevada. Significa que existe uma obra hidráulica capaz de armazenar água, um reservatório com determinada capacidade e um conjunto de dispositivos e regras para operação, segurança e manutenção.

1.3 Tipos principais de barragens

A escolha da tipologia não deve ser feita por tradição local nem por aparência. Ela depende da fundação, da geometria do vale, da disponibilidade de materiais, da altura da obra, do regime de cheias e do uso previsto para o reservatório. Em açudes de pequeno e médio porte, a barragem de terra é frequentemente a solução mais econômica e adaptável, mas isso não a torna universal. Barragens de enrocamento e de concreto podem ser mais adequadas em condições específicas.

1.3.1 Barragens de terra

Barragens de terra são construídas com solos compactados em camadas, formando um maciço estável e impermeável ou semipermeável, conforme o projeto. Podem ser homogêneas ou zonadas, com núcleo impermeável, filtros, drenos e proteção de taludes.

Sua principal vantagem é a possibilidade de aproveitar materiais de empréstimo relativamente próximos à obra, o que reduz custo e simplifica a logística. Além disso, elas se adaptam bem a vales mais largos e a fundações onde o maciço de terra pode ser apoiado com correção geotécnica adequada.

Por outro lado, são obras mais sensíveis à erosão superficial e ao galgamento. Isso exige vertedor independente, compactação rigorosa e controle de qualidade contínuo durante a construção. Em outras palavras, barragem de terra barata na concepção pode tornar-se cara e perigosa se mal executada.

1.3.2 Barragens de enrocamento

Barragens de enrocamento utilizam blocos de rocha e material granular como elemento principal de resistência. Geralmente necessitam de um elemento de impermeabilização complementar, como núcleo argiloso, face impermeável ou sistema de vedação associado.

Essas barragens são indicadas quando há disponibilidade de rocha em quantidade suficiente, quando a fundação apresenta alguma deformabilidade ou quando se deseja maior tolerância a recalques e movimentações. Em comparação com as barragens de terra, costumam demandar maior especialização executiva, embora possam ser tecnicamente vantajosas em determinadas condições.

No semiárido, sua aplicação depende fortemente da geologia local e da logística de transporte da rocha. Se a jazida estiver distante, o custo pode tornar a solução pouco competitiva para pequenos açudes.

1.3.3 Barragens de concreto

Barragens de concreto são mais rígidas e menos dependentes de grandes volumes de material terroso ou rochoso. Em pequenos açudes, aparecem com mais frequência em vales estreitos, com fundação rochosa competente e necessidade de uma solução estrutural mais compacta.

Sua principal vantagem está na robustez estrutural e na ocupação reduzida da seção do vale. Por outro lado, o custo de execução e a exigência de fundação de boa qualidade tornam a tipologia menos frequente em empreendimentos de menor orçamento ou em locais com fundação pouco favorável.

Em termos práticos, barragens de concreto devem ser avaliadas com muito cuidado. Elas não substituem a necessidade de estudo geológico, hidrológico e hidráulico; apenas oferecem uma alternativa quando as condições naturais justificam a solução.

Seleção tipológica em linguagem de projeto

Em um vale largo, com solos argilosos disponíveis nas proximidades, acesso viável para obra e necessidade de reservatório para usos múltiplos, a barragem de terra costuma ser a primeira alternativa a ser examinada. Se o vale for estreito, a fundação for rochosa

Tabela 1.1 – Comparação sintética entre as principais tipologias de barragens

Critério	Barragem de terra	Barragem de enrocamento	Barragem de concreto
Material predominante	Solo compactado em camadas	Blocos de rocha e material granular	Concreto estrutural
Uso mais comum em açudes	Muito frequente em pequenos e médios reservatórios	Aplicações específicas, sobretudo quando há rocha disponível	Situações pontuais, vales estreitos e fundação rochosa
Vantagem principal	Aproveita materiais locais e costuma ter menor custo	Boa acomodação a recalques e maior tolerância estrutural	Alta rigidez e pequena ocupação transversal
Limitação principal	Sensível a erosão e galgamento	Exige impermeabilização complementar e bom controle de filtros	Maior custo e exigência de fundação e execução
Aplicação típica no semiárido	Solução preferencial quando o solo é adequado e o vale é largo	Alternativa quando a pedreira é próxima e a geologia favorece	Casos especiais, geralmente com maior complexidade técnica

e houver exigência de maior rigidez estrutural, a solução em concreto ou enrocamento pode ganhar competitividade.

Regra prática de seleção

De forma simplificada:

- **vale largo + solo local disponível** → barragem de terra tende a ser a solução mais racional;
- **vale estreito + fundação rochosa competente** → barragem de concreto ou de enrocamento pode ser tecnicamente atraente;
- **jazida de rocha próxima + necessidade de tolerância a deformações** → enrocamento pode ser vantajoso;
- **fundação incerta ou regime de cheias significativo** → a escolha deve ser subordinada a estudo geotécnico e hidráulico mais detalhado.

1.4 Componentes essenciais de um açude

Embora o termo açude seja muitas vezes associado apenas ao espelho d'água, o sistema completo é composto por diferentes elementos, cada um com função específica. Entender esses elementos desde o início ajuda a evitar a falsa impressão de que a obra é apenas um muro atravessando o rio.

Os componentes mais importantes são:

- **barragem principal**: estrutura que fecha o vale e cria o reservatório;
- **fundação e ombreiras**: apoio lateral e de base da estrutura, que precisam ser compatíveis com as cargas e com a infiltração esperada;
- **coroamento**: parte superior da barragem, que deve permitir inspeção e estabilidade;
- **vertedor**: estrutura de segurança para passagem das cheias;
- **descarga de fundo ou tomada d'água**: dispositivo de controle operacional;
- **proteção de taludes**: medidas contra erosão por chuva, ondas e escoamento superficial;
- **área de jusante**: setor que pode ser afetado por descargas, percolação ou falhas de operação.

Segurança essencial

Em barragens de terra, o vertedor deve ser uma estrutura **independente** e protegida. O maciço de terra não deve ser usado como caminho de extravasamento normal da água. Quando a água passa sobre um aterro não protegido, a erosão pode evoluir rapidamente para ruptura.

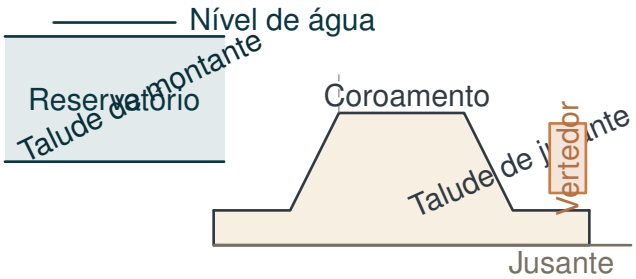

Figura 1.2 – Esquema conceitual de uma barragem de terra com reservatório e vertedor independente.

1.5 Princípios de boa concepção

Um bom açude não nasce apenas de uma boa seção transversal. Ele resulta da combinação entre hidrologia, geotecnia, hidráulica, operação e uso social da água. Mesmo neste capítulo introdutório, vale registrar alguns princípios que orientarão todo o livro.

Princípio de ouro do projeto

Nenhuma tipologia deve ser escolhida apenas pelo custo inicial. A decisão correta considera simultaneamente:

- geologia e fundação;
- geometria do vale;
- disponibilidade de materiais;
- volume a armazenar;
- facilidade de operação e manutenção;
- risco hidráulico;
- uso pretendido da água;
- impactos a montante e a jusante.

Além disso, uma concepção madura precisa observar cinco compromissos básicos:

1. **Segurança**: a obra deve resistir às condições normais e às situações excepcionais previsíveis.
2. **Simplicidade operacional**: quanto mais simples a operação, maior a chance de o sistema permanecer funcional.
3. **Manutenibilidade**: dispositivos devem ser acessíveis, inspecionáveis e reparáveis.
4. **Compatibilidade territorial**: o açude deve fazer sentido para a bacia, para a comunidade e para a logística local.
5. **Resiliência**: a obra precisa suportar variações climáticas sem perda imediata de desempenho.

O erro de concepção mais comum

Um erro frequente é tratar a barragem como se fosse o único elemento importante do empreendimento. Na prática, um açude mal dotado de vertedor, sem dispositivo de descarga, com acesso precário para inspeção e sem critério de operação tende a apresentar problemas mesmo que a barragem, isoladamente, tenha sido executada com bom material.

1.6 Resumo do capítulo

Resumo do capítulo

- Barragem é a estrutura; açude é o reservatório formado por ela.
- No semiárido, o armazenamento é estratégico porque a chuva é concentrada e o período seco é longo.
- Barragens de terra são as mais comuns em pequenos e médios açudes, mas exigem controle rigoroso de compactação e proteção contra erosão.
- Barragens de enrocamento e de concreto são alternativas tecnicamente válidas em condições específicas de fundação, geometria e disponibilidade de materiais.
- O sistema de açude inclui barragem, vertedor, dispositivos de descarga, fundação, ombreiras e proteção dos taludes.
- A escolha da tipologia deve considerar segurança, custo, operação, manutenção e uso múltiplo da água.

1.7 Exercícios

Exercícios de fixação — nível F

F1. Explique a diferença entre barragem e açude.

F2. Por que o armazenamento de água é particularmente importante no semiárido?

F3. Cite uma vantagem e uma limitação da barragem de terra.

F4. Em que situação a barragem de concreto pode se tornar uma opção tecnicamente interessante?

F5. Qual é a função do vertedor em um sistema de açude?

Exercícios de aplicação — nível M

M1. Em uma região com vale largo, solos de boa disponibilidade local e demanda de água para usos múltiplos, qual tipologia tende a ser mais racional? Justifique.

M2. Liste quatro componentes essenciais de um açude e explique, em uma frase, a função de cada um.

M3. Compare, de forma objetiva, barragens de terra e de enrocamento quanto à disponibilidade de materiais e tolerância a deformações.

M4. Explique por que o vertedor deve ser independente do maciço de terra.

Exercícios de integração — nível D

D1. Uma comunidade rural no semiárido necessita de um açude para abastecimento complementar, dessedentação animal e eventual apoio à produção agrícola de pequena escala. O vale é amplo, com solos argilosos disponíveis e fundação não totalmente rochosa. Proponha a tipologia mais provável e apresente três argumentos técnicos para essa escolha.

D2. Imagine que um projetista escolheu uma barragem de terra em um local onde havia expectativa de cheias expressivas, mas o vertedor foi previsto de forma inadequada. Quais riscos principais podem surgir?

D3. Com base no que foi estudado neste capítulo, escreva um conjunto de cinco critérios mínimos que devem orientar a concepção inicial de um açude.

1.8 Gabarito comentado

Gabarito comentado — nível F

F1. **Barragem** é a obra física construída para interceptar o escoamento. **Açude** é o reservatório resultante do represamento. A distinção é fundamental porque o projeto deve tratar tanto da estrutura quanto do volume armazenado.

F2. Porque a precipitação é irregular, concentrada em poucos meses, e os cursos d'água costumam ter escoamento intermitente. O armazenamento permite transferir água do período úmido para o período seco.

F3. Vantagem: costuma aproveitar materiais locais e apresentar menor custo relativo. Limitação: é sensível à erosão e ao galgamento, exigindo compactação rigorosa e vertedor independente.

F4. Em vales estreitos, com fundação rochosa competente e necessidade de estrutura mais rígida. Nesses casos, o concreto pode oferecer solução compacta e estruturalmente eficiente.

F5. O vertedor conduz as vazões excedentes com segurança. Ele protege a barragem contra o extravasamento descontrolado, que pode causar erosão e ruptura.

Gabarito comentado — nível M

M1. A barragem de terra tende a ser a primeira opção. O motivo é a combinação de vale largo, disponibilidade de solo local e possibilidade de solução economicamente mais simples. A escolha, porém, sempre depende de estudo de fundação e de cheias.

M2. Resposta possível: barragem principal, vertedor, descarga de fundo, fundação, taludes protegidos. A barragem forma o reservatório; o vertedor conduz cheias; a descarga de fundo permite esvaziamento e manejo; a fundação suporta a obra; os taludes protegidos reduzem erosão.

M3. A barragem de terra depende mais de solos adequados e compactação cuidadosa; a de enrocamento exige rocha e sistema complementar de impermeabilização. Em contrapartida, a de enrocamento costuma tolerar melhor deformações e recalques.

M4. Porque o vertedor é a estrutura de segurança do sistema. Se a água excedente passar sobre o aterro de terra, o fluxo tende a erodir o maciço rapidamente, podendo provocar ruptura da barragem.

Gabarito comentado — nível D

D1. A solução mais provável é a **barragem de terra**. Três argumentos técnicos fortes são: (i) vale amplo, o que favorece uma seção em aterro; (ii) solos argilosos disponíveis, o que reduz custo de material; (iii) uso múltiplo da água, que pede solução economicamente viável e de operação simples. A resposta deve sempre mencionar que a decisão final depende de estudos de viabilidade, fundação e hidrologia.

D2. Os riscos incluem galgamento, erosão do aterro, instabilidade progressiva do maciço e possibilidade de ruptura. Em barragens de terra, o subdimensionamento do vertedor é uma das falhas mais graves, porque converte uma checida previsível em mecanismo de falha estrutural.

D3. Critérios mínimos esperados: segurança hidráulica; compatibilidade com a fundação; disponibilidade de materiais; geometria favorável do vale; facilidade de operação e manutenção; adequação ao uso pretendido da água; e consideração dos impactos a jusante. Outras respostas tecnicamente coerentes podem ser aceitas, desde que bem justificadas.

Conexão com o próximo capítulo

Depois de compreender o que é um açude, qual é sua função no semiárido e quais tipologias podem ser adotadas, o próximo passo lógico é decidir **onde** a obra deve ser implantada. No capítulo seguinte, serão estudados os critérios de viabilidade e seleção do local, incluindo bacia hidrográfica, topografia, geologia, disponibilidade de materiais, impactos ambientais e condicionantes sociais.

Capítulo 2

Estudo de viabilidade e seleção do local

Objetivos de aprendizagem

Ao final deste capítulo, espera-se que o leitor seja capaz de:

- compreender a finalidade do estudo de viabilidade em empreendimentos de açudes;
- identificar os principais critérios para seleção do local de uma barragem;
- reconhecer condicionantes hidrológicos, topográficos, geológicos, geotécnicos, ambientais, sociais e construtivos;
- distinguir locais tecnicamente favoráveis de locais apenas aparentemente promissores;
- organizar uma análise preliminar que antecede o projeto hidráulico e estrutural.

A escolha do local é uma das decisões mais importantes de todo o empreendimento. Um açude pode ser bem dimensionado, bem construído e bem operado, mas ainda assim fracassar como solução se tiver sido implantado em área inadequada. Em saneamento ambiental, a etapa de viabilidade não é um formalismo anterior ao projeto; ela é parte essencial do projeto, porque define se o sistema faz sentido do ponto de vista técnico, econômico, territorial e social.

Em regiões semiáridas, essa etapa ganha ainda mais peso. A escassez de água induz soluções apressadas, mas justamente nessas regiões o erro de localização costuma ser mais caro e mais difícil de corrigir. Um bom local reduz perdas, facilita o enchimento do reservatório, melhora a estabilidade da barragem, simplifica a operação e aumenta a vida útil do açude.

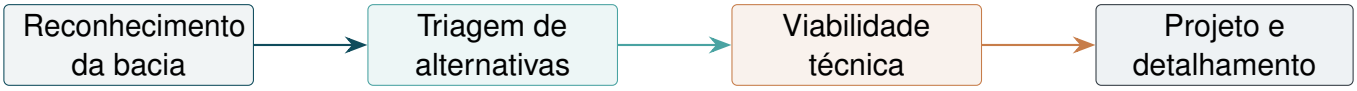

Figura 2.1 – Sequência lógica da decisão de implantação de um açude.

2.1 O que é um estudo de viabilidade

O estudo de viabilidade é a análise preliminar que responde a uma pergunta central: **o empreendimento pode ser implantado aqui, com segurança, utilidade e razoabilidade?**

Essa pergunta envolve muito mais do que a simples existência de um vale ou de um curso d'água. Ela exige a avaliação integrada de restrições e potencialidades.

Viabilidade de implantação

Viabilidade é a compatibilidade entre uma proposta de barragem e as condições reais do local, considerando:

- disponibilidade hídrica da bacia;
- condições geométricas do vale;
- aptidão geológica e geotécnica da fundação;
- acesso à obra e logística construtiva;
- impactos ambientais e sociais;
- finalidade e escala do reservatório;
- custos de implantação, operação e manutenção.

Um erro comum é confundir viabilidade com intenção. Há locais onde a necessidade social é evidente, mas as condições naturais são desfavoráveis; há outros em que a obra é tecnicamente possível, mas socialmente ou ambientalmente mal situada. O estudo correto precisa equilibrar esses elementos.

Viabilidade não é sinônimo de autorização

Um empreendimento pode ser viável do ponto de vista preliminar e, ainda assim, não ser imediatamente executável. A viabilidade é uma etapa de análise; a implantação definitiva depende de estudos mais detalhados, licenciamento, projetos executivos e decisões institucionais.

2.2 Etapas do reconhecimento inicial

Antes de qualquer detalhe de engenharia, a equipe precisa entender a bacia e o território. O reconhecimento inicial costuma seguir uma sequência lógica.

2.2.1 Levantamento documental e cartográfico

Essa etapa reúne:

- cartas topográficas e modelos digitais de terreno;
- imagens de satélite e fotografias aéreas;
- registros pluviométricos e hidrológicos;
- dados geológicos e pedológicos;

- informações sobre uso e ocupação do solo;
- dados de propriedades, acessos e infraestrutura existente.

O objetivo é reduzir incertezas antes da visita de campo. Em regiões semiáridas, onde a variabilidade espacial pode ser elevada, o uso combinado de imagens, mapas e observação local é especialmente importante.

2.2.2 Visita de campo

A vistoria de campo permite verificar:

- a geometria real do vale;
- a presença de afloramentos rochosos, solos expostos e zonas de erosão;
- sinais de infiltração, nascentes ou umidade persistente;
- facilidade de acesso de veículos e equipamentos;
- ocupação humana, benfeitorias e usos a montante e a jusante;
- áreas de empréstimo para materiais de construção;
- pontos favoráveis para eixo da barragem e vertedor.

Importância da vistoria

Em mapas, dois locais podem parecer semelhantes. No campo, porém, um deles pode revelar solo colapsável, taludes instáveis, afloramentos inadequados ou ocupação social conflitiva. A vistoria de campo é o momento em que a engenharia confronta a abstração cartográfica com a realidade física.

2.3 Critérios técnicos de seleção do local

A escolha do local deve ser baseada em um conjunto de critérios que se reforçam mutuamente. Nenhum critério isolado define a solução, mas a ausência de um critério essencial pode inviabilizar toda a proposta.

2.3.1 Critério hidrológico

O local precisa estar em uma bacia capaz de fornecer vazões compatíveis com o objetivo do açude. Não basta haver água em período chuvoso; é preciso haver volume suficiente para justificar o investimento e a operação.

Aspectos fundamentais:

- área de contribuição;
- regime de chuvas;
- coeficiente de escoamento;

- intermitência do curso d'água;
- frequência e magnitude das cheias;
- perdas por evaporação e infiltração na bacia e no reservatório.

Um açude pequeno em uma bacia com aporte muito irregular pode encher raramente. Por outro lado, um açude muito grande em bacia pouco produtiva pode representar custo alto e baixa efetividade. O equilíbrio entre oferta e demanda é essencial.

2.3.2 Critério topográfico

A forma do vale influencia diretamente o volume armazenado, o comprimento da barragem, o custo e a estabilidade da obra. Em termos gerais:

- vales muito largos exigem barragens mais extensas;
- vales muito estreitos podem reduzir o comprimento, mas aumentar exigências estruturais;
- áreas naturalmente deprimidas podem favorecer o armazenamento;
- declividades excessivas podem dificultar a fundação e a construção.

A topografia ideal é aquela que permite boa relação entre volume armazenado e volume de aterro ou concreto necessário. Em outras palavras, deseja-se máximo aproveitamento do relevo com mínimo custo estrutural.

2.3.3 Critério geológico e geotécnico

A fundação é o suporte da barragem. Se ela for inadequada, a estrutura pode apresentar deformações excessivas, percolação indesejada, recalques ou instabilidade. O reconhecimento geológico preliminar deve observar:

- presença de rocha competente ou solo firme;
- continuidade e espessura dos estratos;
- fraturas, falhas, zonas de cisalhamento e intemperismo;
- permeabilidade natural da fundação;
- risco de carreamento interno ou piping;
- possibilidade de tratamento de fundação com custo aceitável.

No semiárido, é comum encontrar fundações com grande heterogeneidade local. Isso exige atenção redobrada, porque uma barragem de terra bem compactada sobre fundação ruim continua sendo uma solução insegura.

2.3.4 Critério de disponibilidade de materiais

Barragens de terra e de enrocamento dependem fortemente da existência de materiais de construção próximos e adequados. O estudo preliminar deve verificar:

- jazidas de solo apropriado;
- material argiloso para núcleo ou impermeabilização;
- brita, rocha ou enrocamento, quando necessário;
- distância média de transporte;
- acessibilidade de caminhões e equipamentos;
- sazonalidade de extração e transporte.

Quanto mais distante estiver a jazida, maior o custo e maior o impacto logístico. Em muitos casos, a disponibilidade de material local é um fator decisivo para a viabilidade do açude.

2.3.5 Critério ambiental

A obra deve ser compatível com o ambiente em que se insere. Isso inclui:

- vegetação ciliar e áreas protegidas;
- habitats sensíveis;
- alteração de fluxo a jusante;
- potencial de assoreamento;
- qualidade da água;
- interferência em usos tradicionais do território.

Um bom estudo de viabilidade procura reduzir impactos desde o início, e não apenas mitigar depois. Em regiões semiáridas, a vegetação e o solo podem ser mais vulneráveis à degradação, exigindo abordagem conservacionista.

2.3.6 Critério social

A água armazenada precisa servir a pessoas concretas, em contextos concretos. O local escolhido não pode ignorar:

- comunidades a montante e a jusante;
- áreas de moradia, produção e circulação;
- conflitos fundiários;
- apropriação desigual da água;

- aceitação social do empreendimento;
- percepção comunitária sobre benefícios e riscos.

Em saneamento ambiental, o valor social da infraestrutura é tão relevante quanto sua eficiência técnica. Um açude mal aceito pela comunidade ou que gere conflito de uso pode tornar-se um passivo em vez de solução.

2.3.7 Critério construtivo e logístico

Além de ser tecnicamente viável, a obra precisa ser construível. Isso inclui:

- acesso para máquinas;
- espaço para canteiro de obras;
- disponibilidade de energia, água de obra e apoio operacional;
- possibilidade de desvio provisório do fluxo;
- condições climáticas durante a execução;
- segurança do tráfego e do pessoal.

Um local excelente em planta pode ser inviável na prática se o acesso for impossível ou se a logística de obra for excessivamente onerosa. A construtibilidade é parte da viabilidade.

A obra precisa caber no território

A implantação de um açude não depende apenas de o vale ser adequado. A solução também precisa caber no território do ponto de vista de acessos, servidões, circulação de equipamentos, segurança de canteiro e compatibilidade com o entorno humano e ambiental.

2.4 Seleção do eixo da barragem

Uma vez identificado o local potencial, o passo seguinte é posicionar o eixo da barragem. O eixo é a linha imaginária sobre a qual a estrutura será implantada, e sua escolha influencia diretamente o comprimento da obra, o volume de aterro, a qualidade da fundação e a segurança hidráulica.

2.4.1 Boas práticas na definição do eixo

Em geral, busca-se:

- a seção mais favorável do vale;
- menor comprimento de barragem compatível com segurança;
- fundação mais competente;

- ombreiras estáveis;
- alinhamento favorável ao escoamento e ao vertedor;
- menor interferência com áreas sensíveis.

Nem sempre o eixo mais curto é o melhor. Um eixo ligeiramente maior, mas apoiado em fundação superior e com melhor implantação do vertedor, pode oferecer desempenho global mais seguro.

Erro de alinhamento

Um eixo muito próximo de uma encosta instável pode reduzir o comprimento da barragem, mas introduzir risco geotécnico relevante. Da mesma forma, um eixo aparentemente econômico, porém posicionado em área de solo de baixa capacidade de suporte, pode elevar o custo de fundação e comprometer a obra.

2.5 Análise preliminar de alternativas

Em projetos bem conduzidos, não se escolhe apenas um local: compara-se uma pequena lista de alternativas. Essa comparação pode ser feita por critérios qualitativos ou por matrizes simples de decisão. O objetivo não é produzir falsa precisão, mas organizar o raciocínio.

Tabela 2.1 – Critérios usuais para comparação preliminar de alternativas de implantação

Critério	O que observar
Hidrologia	Área contribuinte, vazões afluentes, regularidade de aporte, perdas e cheias
Topografia	Forma do vale, comprimento da barragem, potencial de armazenamento e declividade
Geologia e geotecnia	Competência da fundação, permeabilidade, fraturas, recalques e estabilidade
Materiais	Distância, quantidade e qualidade de solos, rochas e agregados
Ambiental	Vegetação, assoreamento, qualidade da água e sensibilidade ecológica
Social	Conflitos de uso, ocupação do território, aceitação comunitária e impactos locais
Construtibilidade	Acesso, canteiro, logística, desvio provisório e segurança de execução

Uma boa prática é atribuir uma avaliação qualitativa a cada critério, por exemplo: favorável, intermediário ou desfavorável. Em seguida, a equipe identifica se algum critério crítico é eliminatório. Caso haja fator eliminatório, a alternativa deve ser descartada ou reavaliada.

2.6 Pré-viabilidade técnico-econômica

A análise técnica precisa dialogar com o custo. Não se trata de escolher sempre a alternativa mais barata, mas a solução mais racional dentro das restrições reais. A pré-viabilidade técnico-econômica considera:

- custo de terraplenagem ou concreto;
- transporte de materiais;
- complexidade de fundação;
- necessidade de tratamentos adicionais;
- facilidade de operação futura;
- custo de manutenção;
- benefício esperado do reservatório.

O equilíbrio entre investimento e benefício é especialmente importante em pequenos açudes destinados a comunidades rurais, onde o orçamento costuma ser limitado e a obra precisa ter vida útil longa.

Economia mal calculada

Reduzir custo inicial sacrificando fundação, vertedor, drenagem ou proteção de taludes não representa economia; representa transferência do custo para o futuro, com juros técnicos e sociais muito mais altos.

2.7 Fluxo lógico da tomada de decisão

A seleção do local pode ser visualizada como um processo de filtragem progressiva. A cada etapa, alternativas menos adequadas são excluídas, até restarem as opções mais promissoras para o projeto.

2.8 Resumo do capítulo

Resumo do capítulo

- O estudo de viabilidade responde se a obra pode ser implantada aqui, com segurança e utilidade.
- O reconhecimento inicial inclui levantamento documental, leitura cartográfica e vistoria de campo.
- Os critérios centrais de seleção são hidrologia, topografia, geologia, materiais, ambiente, sociedade e construtibilidade.

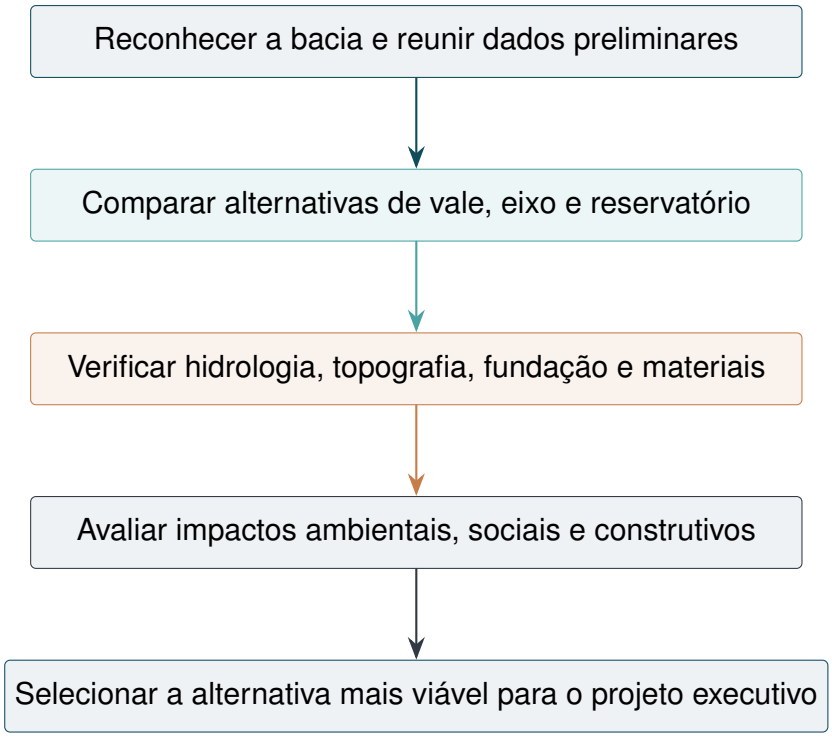

Figura 2.2 – Fluxo simplificado da tomada de decisão na seleção do local.

- O eixo da barragem deve buscar bom equilíbrio entre comprimento, fundação, estabilidade e implantação do vertedor.
- A pré-viabilidade técnico-econômica evita soluções tecnicamente frágeis e financeiramente insustentáveis.
- Decidir o local corretamente é tão importante quanto dimensionar a obra.

2.9 Exercícios

Exercícios de fixação — nível F

F1. O que se entende por estudo de viabilidade em um projeto de açude?

F2. Cite quatro critérios que devem ser analisados na seleção do local.

F3. Qual é a importância da vistoria de campo?

F4. Por que a disponibilidade de materiais é um critério relevante?

F5. Qual a diferença entre viabilidade técnica e autorização para implantação?

Exercícios de aplicação — nível M

M1. Em uma alternativa de implantação, o vale é favorável, mas a fundação apresenta forte heterogeneidade geológica. Como esse dado deve influenciar a decisão?

M2. Explique por que um eixo mais curto nem sempre é o melhor eixo para a barragem.

M3. Elabore uma lista com cinco informações mínimas que devem ser obtidas em um reconhecimento preliminar da bacia.

M4. Em que sentido a construtibilidade faz parte da viabilidade?

Exercícios de integração — nível D

D1. Uma comunidade solicita um açude em um vale aparentemente promissor. A análise preliminar indica bom potencial de armazenamento, mas também revela acesso difícil, fundação pouco conhecida e presença de áreas ambientalmente sensíveis a jusante. Como você organizaria a decisão? Quais seriam os critérios eliminatórios, se houver?

D2. Compare duas alternativas: a primeira tem menor comprimento de barragem, mas fundação ruim; a segunda tem maior comprimento, mas fundação mais competente e melhor acesso de obra. Qual tende a ser preferível e por quê?

D3. Redija, em linguagem técnica, um parágrafo justificando por que o estudo de viabilidade deve anteceder o dimensionamento hidráulico detalhado.

2.10 Gabarito comentado

Gabarito comentado — nível F

F1. É a análise preliminar que verifica se o empreendimento pode ser implantado em determinado local com segurança, utilidade e razoabilidade.

F2. Resposta esperada: hidrologia, topografia, geologia/geotecnia, materiais, ambiente, sociedade e construtibilidade. Bastam quatro, desde que sejam relevantes e bem explicados.

F3. A vistoria de campo confirma a realidade física do local, verifica a geometria do vale, o estado dos solos e rochas, a acessibilidade e os sinais de restrições não visíveis em mapas.

F4. Porque barragens de terra e de enrocamento dependem fortemente de materiais locais. A distância e a qualidade desses materiais afetam custo, prazo e desempenho.

F5. Viabilidade técnica indica possibilidade física e engenharia aceitável; autorização depende de licenciamento, projetos, aprovações e decisões institucionais.

Gabarito comentado — nível M

M1. A heterogeneidade da fundação é um fator crítico e pode comprometer a solução. Deve haver investigação adicional; se a heterogeneidade implicar riscos altos ou tratamento excessivamente oneroso, a alternativa pode ser descartada.

M2. Porque o menor comprimento não garante menor custo global nem maior segurança. Um eixo curto sobre fundação ruim, com ombreiras instáveis ou com vertedor mal localizado, pode ser pior do que um eixo um pouco maior e mais seguro.

M3. Exemplo de resposta: mapas e imagens; regime de chuvas; área de contribuição; topografia; geologia; uso do solo; acessos; ocupação humana; jazidas de material; presença de áreas de risco.

M4. A construtibilidade verifica se a obra pode ser executada com segurança, acesso, canteiro, logística e recursos compatíveis. Uma obra pode ser tecnicamente bela no papel e inviável no terreno.

Gabarito comentado — nível D

D1. A decisão deve ser feita por etapas. Primeiro, confirmar se há algum fator eliminatório, como fundação inadequada sem possibilidade de tratamento, restrição ambiental insuperável ou impossibilidade logística severa. Em seguida, ponderar os fatores favoráveis e desfavoráveis. Se o risco geotécnico e ambiental for alto demais, a alternativa deve ser descartada, ainda que o potencial de armazenamento seja bom.

D2. A segunda alternativa tende a ser preferível se a melhora de fundação e acessibilidade compensar o aumento de comprimento. Em barragens, segurança e construtibilidade pesam muito. Menor comprimento sem base adequada não é vantagem real.

D3. Resposta possível: o estudo de viabilidade deve anteceder o dimensionamento detalhado porque define se o empreendimento é tecnicamente compatível com o local. Sem essa etapa, corre-se o risco de dimensionar uma obra em área geologicamente inadequada, hidrologicamente insuficiente ou socialmente conflitante, o que compromete toda a cadeia de projeto e execução.

Conexão com o próximo capítulo

Com o local escolhido e a viabilidade preliminar confirmada, o próximo passo é compreender a base hidrológica do projeto. No capítulo seguinte, serão estudados a bacia hidrográfica, o escoamento, as vazões de projeto e a relação entre chuva, armazenamento e disponibilidade hídrica, incluindo a curva cota-volume-área do reservatório.

Parte II

Projeto hidrológico e hidráulico

Capítulo 3

Hidrologia aplicada a açudes e reservatórios

Objetivos de aprendizagem

Ao final deste capítulo, espera-se que o leitor seja capaz de:

- compreender por que a hidrologia é a base do projeto de açudes;
- reconhecer como a bacia hidrográfica controla o aporte de água ao reservatório;
- distinguir vazão de projeto, cheia de projeto e período de retorno;
- interpretar a curva cota-volume-área como instrumento central do dimensionamento;
- construir e ler, em nível preliminar, uma tabela de cota-área-volume;
- relacionar o comportamento hidrológico do semiárido às decisões de projeto e operação.

A hidrologia é a espinha dorsal do projeto de um açude. Antes de discutir o formato do vertedor, a seção da barragem ou a proteção de taludes, é indispensável entender como a chuva se transforma em escoamento, como esse escoamento chega ao reservatório e como o volume armazenado varia com a elevação do nível d'água. Em outras palavras, a obra precisa ser coerente com a dinâmica da bacia hidrográfica que a alimenta.

No semiárido, essa coerência é ainda mais importante. A água não chega de forma contínua e regular; ela aparece em eventos concentrados, com grande variabilidade temporal e espacial. O açude precisa capturar esse excedente, armazená-lo com perdas aceitáveis e liberar sua utilidade ao longo do período seco. Sem hidrologia bem estabelecida, qualquer dimensionamento posterior fica fragilizado.

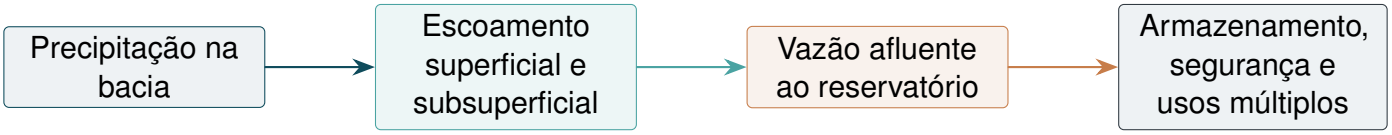

Figura 3.1 – Cadeia hidrológica simplificada que liga a chuva ao armazenamento e à operação do açude.

3.1 A bacia hidrográfica como unidade de resposta

A bacia hidrográfica é a unidade natural que organiza o caminho da água até o reservatório. Ela reúne a superfície que contribui para um mesmo ponto de saída, normalmente o local onde a barragem intercepta o curso d'água. Em termos de projeto, isso significa que a resposta do açude depende não apenas da chuva que cai, mas da forma como a bacia transforma essa chuva em vazão.

3.1.1 Fatores que controlam a resposta hidrológica

A mesma chuva pode gerar respostas muito distintas conforme:

- a área da bacia;
- a declividade do terreno;
- o tipo e a cobertura do solo;
- a densidade da drenagem;
- o estado de umidade antecedente;
- o uso e ocupação do solo;
- a presença de feições rochosas, áreas compactadas ou solos muito permeáveis.

Uma bacia com solos rasos e declividades acentuadas tende a produzir escoamento mais rápido. Já uma bacia com maior infiltração, cobertura vegetal razoável e relevo suave tende a reter parte da água e produzir picos de vazão menos abruptos. Para o açude, isso altera o enchimento, a segurança hidráulica e a dinâmica de operação.

No semiárido, o volume anual não conta a história completa

Do ponto de vista prático, a média anual de chuva pode ser enganosa. Em regiões semiáridas, interessa tanto a quantidade quanto a distribuição temporal das chuvas, a intensidade dos eventos e a capacidade da bacia de concentrar o escoamento em poucas ocasiões favoráveis ao armazenamento.

3.1.2 Perdas hidrológicas

Nem toda chuva se transforma em vazão útil para o reservatório. Parte da precipitação é perdida por:

- interceptação pela vegetação;
- infiltração no solo;
- evapotranspiração;
- armazenamento superficial temporário;

- consumo pela própria dinâmica da bacia.

Essas perdas são especialmente relevantes no semiárido, onde a evaporação pode ser elevada e o solo pode apresentar grande heterogeneidade espacial. Assim, o projeto não deve assumir que toda chuva disponível será convertida em água armazenável.

3.2 Vazão de projeto, cheia de projeto e período de retorno

A análise hidrológica de um açude precisa distinguir dois conceitos complementares:

- **vazão de projeto**: vazão usada como base para dimensionar um componente da obra;
- **cheia de projeto**: evento hidrológico de referência adotado para verificar a segurança do sistema.

Esses conceitos não são idênticos em qualquer obra, mas ambos expressam a mesma ideia central: escolher uma condição de cálculo compatível com o grau de risco aceito.

Cheia de projeto, vazão de projeto e período de retorno

- **Cheia de projeto**: evento de cheia adotado no dimensionamento ou na verificação de segurança do reservatório e de seus dispositivos hidráulicos.
- **Vazão de projeto**: vazão associada ao evento adotado para cálculo.
- **Período de retorno**: intervalo estatístico médio esperado entre eventos iguais ou superiores a uma determinada magnitude.

No planejamento de açudes, a escolha da cheia de projeto depende do porte da obra, do risco aceitável, da importância da infraestrutura e das consequências de eventual falha. Em obras pequenas, essa escolha ainda assim deve ser cuidadosa, porque uma solução aparentemente simples pode ter grandes efeitos a jusante.

3.2.1 Métodos preliminares de estimativa de vazão

Quando o projeto ainda está em fase preliminar, alguns métodos são usados para estimar a resposta da bacia. A escolha depende do porte da bacia, da disponibilidade de dados e do nível de detalhamento desejado.

Uso criterioso do método racional

O método racional é frequentemente apresentado pela expressão

$$Q_p = 0{,}278\, C\, i\, A$$

na qual Q_p é a vazão de pico em m^3/s, C é o coeficiente de escoamento, i é a intensidade da chuva em mm/h e A é a área da bacia em km^2. Trata-se de uma ferramenta simples

Tabela 3.1 – Métodos usuais de estimativa preliminar de vazões em bacias contribuintes

Método	Aplicação típica	Dados necessários	Observação técnica
Método racional	Pequenas bacias com resposta rápida	Intensidade de chuva, coeficiente de escoamento e área	Simples e útil em triagem, mas não deve ser usado fora de seu domínio de validade
Hidrograma unitário e métodos afins	Bacias médias e estudos mais detalhados	Chuva de projeto, características da bacia e parâmetros de transformação chuva-vazão	Permite melhor representação temporal do escoamento
Regionalização hidrológica	Situações com escassez de dados fluviométricos	Estudos regionais, séries históricas e parâmetros de referência	Muito útil no semiárido, desde que a região de origem dos parâmetros seja compatível

e útil para estimativas preliminares em bacias pequenas e relativamente homogêneas, mas não substitui estudos hidrológicos mais robustos quando o risco é relevante.

Leitura técnica da vazão de projeto

Se uma pequena bacia possui alta impermeabilização local, declividade acentuada e tempo de concentração reduzido, a vazão de pico tende a ocorrer rapidamente após a chuva intensa. Esse comportamento exige atenção especial ao vertedor, porque o reservatório pode receber um volume significativo em pouco tempo.

3.3 Curvas cota-área, cota-volume e cota-volume-área

A geometria do reservatório é representada por curvas que relacionam a elevação da lâmina d'água com a área inundada e o volume armazenado. Essas curvas são fundamentais porque conectam a topografia ao comportamento hidráulico do açude.

3.3.1 Conceitos básicos

A curva cota-área informa a área do espelho d'água para cada nível do reservatório. A curva cota-volume informa o volume acumulado armazenado até determinada cota. A combinação das duas é chamada de curva cota-volume-área.

Em termos matemáticos, a relação entre volume e cota pode ser expressa por

$$A(h) = \frac{dV}{dh}$$

onde $A(h)$ é a área inundada na cota h e $V(h)$ é o volume acumulado até essa mesma cota.

Outra forma útil de escrever a acumulação é

$$V(h) = \int_{h_0}^{h} A(\eta)\, d\eta$$

na qual h_0 representa a cota de referência adotada no levantamento.

Atenção ao datum topográfico

Todas as cotas utilizadas na curva devem estar referidas ao mesmo datum topográfico. Misturar referências altimétricas diferentes é um erro grave, porque distorce completamente a interpretação do reservatório, da descarga de fundo, da tomada d'água e do vertedor.

3.3.2 Por que essas curvas são essenciais

Essas curvas permitem:

- estimar o volume útil do reservatório;
- identificar o volume morto;
- avaliar a área exposta e as perdas por evaporação;
- relacionar cota de operação com disponibilidade hídrica;
- apoiar decisões de segurança, operação e manutenção;
- comparar alternativas de projeto com base geométrica real.

No semiárido, a área do espelho d'água é tão importante quanto o volume armazenado. Um reservatório muito raso e muito aberto pode perder grande parte da água por evaporação, mesmo quando o volume total parece elevado. Portanto, a curva cota-volume-área não é apenas um instrumento geométrico; ela é um instrumento de eficiência hídrica.

3.3.3 Como construir a curva

O procedimento preliminar costuma seguir as etapas abaixo:

1. definir um datum altimétrico único para todo o levantamento;
2. levantar as cotas do terreno e desenhar as curvas de nível do vale;
3. calcular a área inundada para cada cota escolhida;

4. determinar os volumes incrementais entre cotas sucessivas;
5. acumular os volumes até o nível desejado;
6. plotar as curvas e revisar a coerência dos resultados.

Para intervalos verticais regulares, o volume entre duas cotas consecutivas pode ser estimado pela regra dos trapézios:

$$V_i = V_{i-1} + \frac{A_{i-1} + A_i}{2}\,\Delta h$$

em que Δh é a diferença de cotas entre dois níveis consecutivos.

3.4 Exemplo didático de construção da curva

Considere um reservatório hipotético com cotas espaçadas de 1 m. As áreas inundadas medidas em cada cota estão resumidas na tabela a seguir. A partir desses valores, é possível construir a curva cota-volume-área por acumulação sucessiva.

Tabela 3.2 – Exemplo simplificado de levantamento cota-área-volume

Cota (m)	Área espelho (ha)	Volume incremental (m^3)	Volume acumulado (m^3)
100	0,0	–	0
101	0,8	4 000	4 000
102	1,6	12 000	16 000
103	2,7	21 500	37 500
104	4,1	34 000	71 500
105	5,8	49 500	121 000

O primeiro incremento, entre as cotas 100 e 101, pode ser entendido assim:

$$V_1 = \frac{0{,}0 + 0{,}8}{2} \times 10\,000 \times 1 = 4\,000\ \mathrm{m}^3$$

Como 1 ha equivale a 10 000 m^2, a área média de 0,4 ha resulta em 4 000 m^3 para um desnível de 1 m. O mesmo raciocínio é repetido para os demais trechos.

O que a curva revela

Observe que, à medida que a cota aumenta, o reservatório passa a ganhar volume com incrementos cada vez maiores. Isso normalmente significa maior área inundada, maior exposição à evaporação e maior sensibilidade à gestão operacional. Em muitos açudes do semiárido, os metros finais de enchimento aumentam muito a área molhada e, por consequência, as perdas potenciais.

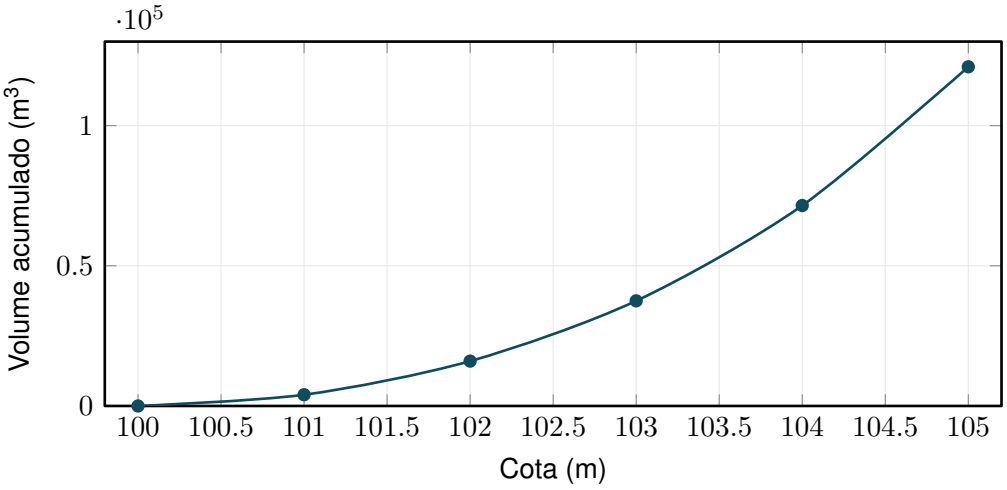

Figura 3.2 – Curva cota-volume acumulado para o exemplo simplificado da Tabela 3.2.

3.5 Indicadores derivados da curva

A curva cota-volume-área não serve apenas para representar a geometria do reservatório. Ela também ajuda a definir níveis operacionais importantes.

Níveis e volumes operacionais

- **Volume morto**: parcela armazenada abaixo do nível mínimo operacional ou abaixo da tomada d'água.
- **Volume útil**: parcela efetivamente disponível para uso regular.
- **Volume de espera**: reserva disponível para amortecer eventos de cheia, quando adotada na estratégia operacional.
- **Cota normal de operação**: nível de funcionamento cotidiano do reservatório.
- **Cota máxima normal**: nível superior admitido em operação regular, sem ultrapassar a segurança hidráulica.

Esses conceitos variam conforme o tipo de reservatório e o critério do projeto, mas a lógica permanece a mesma: parte do volume é reservada para operação, parte para segurança e parte para compensar a variabilidade natural do sistema.

3.6 Interpretação hidrológica no contexto semiárido

No semiárido, a curva cota-volume-área deve ser lida em conjunto com a frequência das chuvas, a evaporação potencial e a demanda do reservatório. Um açude pode ter volume total expressivo, mas pouca eficiência prática se o espelho d'água for muito grande em relação à profundidade útil.

3.6.1 Armazenar mais não é sempre armazenar melhor

A cada metro adicional de enchimento, o reservatório pode:

- ganhar volume;
- aumentar a área exposta;
- perder mais água por evaporação;
- alterar a qualidade da água;
- demandar maior cuidado operacional.

Assim, o desempenho hidrológico do açude precisa ser avaliado não apenas pela capacidade máxima, mas pela relação entre ganho de volume e custo hídrico associado à área inundada. Esse raciocínio é central no semiárido, onde a água armazenada é valiosa e as perdas superficiais são relevantes.

3.6.2 Hidrologia e tomada de decisão

A partir do comportamento hidrológico da bacia e da geometria do reservatório, o projetista consegue responder perguntas decisivas:

- O reservatório enche com frequência suficiente?
- A área inundada é compatível com a disponibilidade hídrica?
- O volume útil atende à demanda prevista?
- A cheia de projeto exige um vertedor maior ou menor?
- Há margem para operação segura durante anos secos e chuvosos?

Essas perguntas mostram que a hidrologia não é um estudo isolado: ela guia diretamente o dimensionamento hidráulico e a estratégia operacional do açude.

Leitura integrada para o semiárido

Se duas alternativas apresentam o mesmo volume máximo, mas uma delas possui área do espelho d'água muito maior, a alternativa de menor área tende a ser mais eficiente em regiões de alta evaporação, desde que a segurança hidráulica e a viabilidade construtiva sejam preservadas.

3.7 Resumo do capítulo

Resumo do capítulo

- A hidrologia estabelece a ligação entre chuva, escoamento e armazenamento no açude.
- A bacia hidrográfica é a unidade que controla a resposta do reservatório.
- Vazão de projeto, cheia de projeto e período de retorno são conceitos básicos para a segurança hidráulica.
- A curva cota-volume-área traduz a geometria do reservatório e é essencial para o dimensionamento e a operação.
- O volume acumulado pode ser estimado por integração ou por regra dos trapézios a partir de áreas sucessivas.
- No semiárido, a área do espelho d'água é crítica porque influencia diretamente as perdas por evaporação.
- A qualidade do levantamento topográfico e a consistência do datum são indispensáveis para a confiabilidade das curvas.

3.8 Exercícios

Exercícios de fixação — nível F

F1. Explique por que a bacia hidrográfica é a unidade fundamental da análise hidrológica de um açude.

F2. Qual é a diferença entre vazão de projeto e cheia de projeto?

F3. O que representa a curva cota-volume-área em um reservatório?

F4. Por que a área do espelho d'água merece atenção especial no semiárido?

F5. Qual é a importância de utilizar o mesmo datum topográfico em todo o levantamento?

Exercícios de aplicação — nível M

M1. Cite três fatores da bacia que influenciam a geração de escoamento superficial.

M2. Explique, em termos técnicos, por que o método racional deve ser usado com cautela.

M3. Dada uma sequência de áreas crescentes ao longo das cotas, descreva o procedimento para calcular o volume acumulado entre dois níveis sucessivos.

M4. Em um reservatório semiárido, dois projetos têm o mesmo volume total, mas áreas inundadas muito diferentes. Qual critério adicional deve ser observado para comparar as alternativas?

Exercícios de integração — nível D

D1. Uma bacia de pequena extensão, com declividade elevada e baixa infiltração, recebe uma chuva intensa de curta duração. Explique por que o pico de vazão pode ocorrer rapidamente e quais implicações isso traz para a concepção do açude.

D2. Suponha que um reservatório tenha uma curva cota-volume com grande aumento de área nos últimos metros de enchimento. Discuta as consequências dessa característica para a evaporação, para a operação e para a eficiência hídrica no semiárido.

D3. Em um levantamento topográfico, duas equipes produziram curvas cota-volume distintas para o mesmo local, porque adotaram referências altimétricas diferentes. Analise as consequências técnicas desse erro e proponha uma forma de evitá-lo.

3.9 Gabarito comentado

Gabarito comentado — nível F

F1. Porque a bacia define a área que contribui para a formação do escoamento que alimenta o reservatório. Sem essa unidade de análise, não é possível relacionar adequadamente chuva, vazão e armazenamento.

F2. Vazão de projeto é a vazão usada como base de cálculo; cheia de projeto é o evento hidrológico de referência adotado na verificação de segurança. Em muitos casos, a cheia de projeto gera a vazão de projeto, mas os conceitos não são sinônimos absolutos.

F3. É a relação entre a elevação da água, a área inundada e o volume acumulado do reservatório. Ela traduz a geometria do vale em capacidade de armazenamento.

F4. Porque a evaporação é elevada e a água superficial é mais vulnerável a perdas. Um grande espelho d'água pode reduzir a eficiência do armazenamento.

F5. Porque misturar referências altimétricas altera completamente a interpretação das cotas, volumes e níveis operacionais. O erro compromete o projeto inteiro.

Gabarito comentado — nível M

M1. Exemplo de resposta: declividade do terreno, tipo de solo, cobertura vegetal, uso e ocupação do solo, densidade de drenagem e umidade antecedente. Qualquer três bem justificadas são aceitáveis.

M2. Porque o método racional é uma simplificação que só se aplica adequadamente a certas bacias pequenas, homogêneas e com hipóteses restritivas. Fora desse contexto, ele pode subestimar ou superestimar a vazão de pico.

M3. Primeiro, deve-se calcular a área média entre duas cotas sucessivas. Depois, multiplica-se essa área média pela diferença de cota. O volume acumulado é obtido somando os incrementos sucessivos, de forma compatível com a regra dos trapézios.

M4. Deve-se observar a eficiência hídrica do reservatório, e não apenas o volume total. Em regiões semiáridas, um reservatório com menor área inundada costuma apresentar perdas por evaporação mais controláveis.

Gabarito comentado — nível D

D1. O pico de vazão ocorre rapidamente porque a bacia responde de forma quase instantânea à chuva intensa, sobretudo quando há pouca infiltração e forte declividade. Isso implica necessidade de vertedor capaz de atender vazões elevadas em curto tempo, além de cuidado com o posicionamento da barragem e com a segurança contra galgamento.

D2. Um forte aumento de área nos últimos metros significa maior exposição da lâmina d'água à evaporação, maior sensibilidade à operação e possível redução da eficiência do armazenamento. No semiárido, essa característica pode tornar o reservatório menos competitivo do ponto de vista hídrico, mesmo com volume nominal alto.

D3. As consequências são graves: volumes incorretos, cotas operacionais equivocadas, dimensionamento inconsistente de vertedor e descarga de fundo e, em última instância, risco para a segurança e a operação. A forma de evitar é padronizar o datum antes de qualquer processamento e verificar a compatibilidade de todas as cotas com a mesma referência altimétrica.

Conexão com o próximo capítulo

Com a base hidrológica definida, o próximo passo é transformar essa informação em segurança hidráulica concreta. No capítulo seguinte, serão estudados o vertedor e a bacia de dissipação, isto é, os elementos responsáveis por conduzir cheias com segurança e proteger a barragem e o terreno a jusante contra erosão e falhas de extravasamento.

Capítulo 4

Vertedores e dissipação de energia

Objetivos de aprendizagem

Ao final deste capítulo, espera-se que o leitor seja capaz de:

- compreender a função hidráulica do vertedor em açudes e reservatórios;
- reconhecer os principais tipos de vertedores usados em pequenas barragens;
- interpretar, em nível preliminar, a relação entre vazão, carga hidráulica e largura útil de extravasamento;
- distinguir os objetivos do vertedor e da bacia de dissipação;
- avaliar os riscos de erosão, galgamento e falha por extravasamento inadequado;
- aplicar critérios básicos de segurança hidráulica no contexto do semiárido.

O vertedor é o elemento que traduz, em segurança, a resposta da barragem às cheias. Enquanto a barragem cria o reservatório, o vertedor evita que a água excedente se transforme em ameaça estrutural. Em açudes de terra, essa função é absolutamente decisiva: a água não pode passar livremente sobre o aterro, e o sistema deve conduzir as vazões de excesso por uma estrutura própria, estável e protegida.

A dissipação de energia, por sua vez, complementa o vertedor. Não basta descarregar a água com segurança imediata; é preciso reduzir a velocidade do escoamento a jusante para evitar erosão, escavação e instabilidade do terreno. Em síntese, o vertedor protege a barragem durante a cheia, e a dissipação protege o vale após a passagem da água.

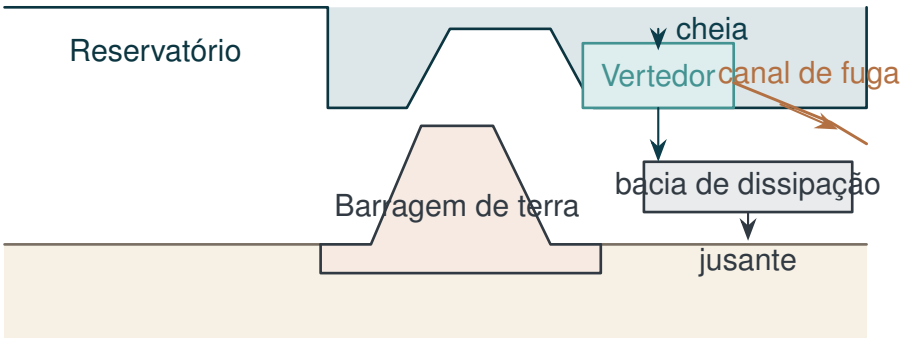

Figura 4.1 – Esquema conceitual de vertedor e bacia de dissipação em uma barragem de terra.

4.1 Função hidráulica do vertedor

O vertedor é a estrutura destinada a conduzir, de forma controlada, as vazões excedentes que ultrapassam a capacidade normal de armazenamento do açude. Sua presença é obrigatória do ponto de vista de segurança funcional: quando o reservatório atinge o nível máximo admissível, o excesso precisa ser descarregado sem comprometer a barragem.

Vertedor

Vertedor é o dispositivo hidráulico que permite a passagem de vazões excedentes de um reservatório para jusante, preservando a integridade da barragem e conduzindo a cheia de forma segura.

Em barragens de terra, o vertedor normalmente deve ser independente do maciço. Em outras palavras, não se admite que o aterro funcione como canal de extravasamento. Essa independência reduz o risco de erosão regressiva, galgamento e ruptura.

Por que o vertedor é elemento de segurança

O vertedor não é um acessório do projeto; ele é uma das principais linhas de defesa contra falha hidráulica. A maior parte das rupturas graves em barragens de terra está associada ao galgamento ou a falhas no extravasamento. Portanto, dimensionar o vertedor corretamente é tão importante quanto construir bem o aterro.

4.1.1 Níveis hidráulicos associados ao vertedor

No estudo preliminar, é útil distinguir:

- **nível normal de operação**: cota usual do reservatório em regime ordinário;
- **cota máxima normal**: nível superior admissível na operação regular;
- **nível máximo extraordinário**: condição de evento excepcional;
- **cota da crista da barragem**: topo da estrutura, que precisa ficar acima dos níveis máximos esperados com margem de segurança.

A diferença entre essas cotas forma a chamada folga livre, ou *freeboard*, necessária para acomodar ondas, incertezas hidrológicas e variações operacionais. No contexto do semiárido, essa margem continua sendo essencial, mesmo quando o reservatório parece pouco sujeito a enchentes frequentes.

4.2 Tipos de vertedores

A escolha do tipo de vertedor depende da geometria do vale, do porte da obra, da fundação, da vazão de projeto e da facilidade construtiva. Em açudes de pequeno e médio porte, algumas tipologias são recorrentes.

4.2.1 Vertedor de soleira livre

É a solução mais simples: a água passa sobre uma crista, sem comporta. Funciona bem em estruturas de pequeno porte, com controle hidráulico relativamente direto. É muito usado em obras em que a simplicidade operacional é prioridade.

Sua principal vantagem é a robustez e a baixa complexidade de operação. A limitação está na necessidade de boa compatibilidade entre a geometria da soleira, a vazão a extravasar e a energia do escoamento a jusante.

4.2.2 Vertedor lateral

Nesse tipo, a água transborda lateralmente para um canal coletor. Ele pode ser útil quando o eixo da barragem não permite solução frontal ou quando a topografia favorece a condução do excesso para uma ombreira.

É uma alternativa tecnicamente válida, mas exige estudo cuidadoso do canal de aproximação, da transição de entrada e do trajeto até a dissipação final.

4.2.3 Vertedor em canal revestido

É frequente em pequenos açudes de terra. A água passa por um canal em concreto, alvenaria ou outro revestimento resistente à erosão. O canal deve possuir declividade, largura e proteção adequadas para conduzir a vazão até a dissipação.

A vantagem é a relativa simplicidade de execução em relação a estruturas mais complexas. A limitação está na necessidade de evitar deterioração do revestimento e erosão nas bordas.

4.2.4 Vertedor em queda livre ou salto

Em determinados arranjos, a descarga ocorre com queda significativa de nível, exigindo estrutura de proteção ao longo da trajetória ou logo no impacto. Essa solução demanda maior atenção à energia específica e ao tipo de dissipação.

4.3 Noções preliminares de dimensionamento

O dimensionamento do vertedor relaciona vazão, geometria e carga hidráulica. Em nível introdutório, é suficiente compreender que a capacidade de descarga cresce com a largura útil e com a lâmina de água sobre a soleira.

Uma forma clássica de representação é dada por

$$Q = C\,L\,H^{3/2}$$

em que Q é a vazão, C é um coeficiente que depende da forma e do regime de escoamento, L é a largura efetiva do vertedor e H é a carga hidráulica sobre a soleira.

Tabela 4.1 – Comparação sintética entre tipos de vertedor

Tipo de vertedor	Vantagem principal	Limitação principal	Uso típico
Soleira livre	Simplicidade e robustez	Pode exigir bom controle de energia a jusante	Pequenas barragens e açudes rurais
Lateral	Flexibilidade de implantação	Exige canal de aproximação e transição bem resolvidos	Locais com restrição de eixo ou topografia favorável
Canal revestido	Boa condução da vazão e fácil leitura visual	Depende da integridade do revestimento	Açudes de terra com extravasamento controlado
Queda livre / salto	Pode acomodar desníveis relevantes	Necessita dissipação muito cuidadosa	Obras com desnível acentuado e projeto mais detalhado

Interpretação da fórmula

A expressão não deve ser lida como receita universal sem contexto. O coeficiente depende da geometria do vertedor, das condições de aproximação e de outras variáveis hidráulicas. Em projeto real, o cálculo requer maior detalhamento. Aqui, a fórmula serve para mostrar que a capacidade de descarga cresce com a largura e com a carga sobre a crista.

4.3.1 Implicações práticas

Duas consequências são particularmente importantes:

- aumentar a largura útil do vertedor tende a aumentar a capacidade de passagem;
- elevar demais a carga sobre o vertedor pode comprometer a segurança se a obra não estiver preparada para isso.

Assim, o dimensionamento busca compatibilizar a vazão de cheia com uma estrutura capaz de descarregá-la sem gerar erosão, instabilidade ou operação perigosa.

Leitura conceitual

Se o reservatório recebe uma cheia mais intensa do que a inicialmente estimada, a carga sobre o vertedor aumenta. Se a estrutura não tiver largura ou cota adequadas, o nível do reservatório pode subir além do esperado, reduzindo a folga livre e aumentando o risco de galgamento.

4.4 Erosão, galgamento e falhas associadas

A falha hidráulica costuma iniciar de forma simples e evoluir rapidamente. Em barragens de terra, os mecanismos mais críticos são:

- galgamento;
- erosão superficial;
- ruptura de revestimentos;
- instabilidade de taludes próximos ao vertedor;
- carreamento de solo ao longo do canal de descarga.

4.4.1 Galgamento

Galgamento ocorre quando a água ultrapassa a crista da barragem ou transborda por região não prevista para extravasamento. Em aterros, isso é extremamente perigoso, porque o fluxo remove material progressivamente e pode abrir uma brecha de ruptura.

4.4.2 Erosão regressiva

A erosão regressiva ocorre quando o fluxo inicia no ponto de descarga e avança para montante, escavando o terreno e ampliando a seção erodida. Esse fenômeno é especialmente crítico em solos pouco coesos e em canais sem proteção adequada.

Sinal de alerta

Se a descarga apresenta indícios de solo exposto, sulcos crescentes, rebaixamento do fundo ou deterioração de bordas, a situação deve ser tratada como sinal de risco hidráulico. Em reservatórios pequenos, a evolução pode ser rápida após uma única cheia relevante.

4.5 Dissipação de energia

A água que sai do vertedor normalmente conserva velocidade elevada. Se ela atingir diretamente um solo não protegido, pode escavar o terreno e comprometer o canal ou a jusante da barragem. A bacia de dissipação existe para reduzir essa energia antes que o escoamento se espalhe pelo terreno natural.

Bacia de dissipação

Bacia de dissipação é a estrutura, localizada a jusante do vertedor, destinada a reduzir a energia do escoamento descarregado, protegendo o terreno contra erosão e instabilidade.

4.5.1 Objetivos da dissipação

A dissipação busca:

- reduzir a velocidade do fluxo;
- induzir turbulência controlada em área protegida;
- evitar escavação no leito natural;
- estabilizar o trecho a jusante;
- proteger estruturas complementares, como escadas, canais e saídas.

4.5.2 Formas usuais de dissipação

As soluções mais comuns incluem:

- bacia com soleira e bloco de queda;
- bacia com ressalto hidráulico;
- enrocamento de proteção;
- revestimento do canal de fuga;
- degraus ou estruturas auxiliares de dissipação.

Tabela 4.2 – Soluções usuais de dissipação de energia

Solução	Vantagem principal	Limitação principal	Aplicação típica
Bacia com ressalto hidráulico	Dissipação eficiente em espaço relativamente curto	Exige condições de escoamento adequadas	Descargas com velocidade elevada e canal controlado
Enrocamento de proteção	Execução relativamente simples	Menor controle hidráulico fino	Proteção complementar de leitos e taludes
Canal revestido	Condução estável do fluxo	Requer boa integridade estrutural	Saídas prolongadas até área segura
Estruturas em degraus	Boa dissipação por etapas	Projeto mais detalhado	Terrenos com desnível mais acentuado

4.5.3 Relação entre vertedor e dissipador

Vertedor e dissipador devem ser concebidos como um sistema único. Se o vertedor descarrega corretamente, mas o dissipador falha, o problema apenas muda de lugar: a

água sai da barragem, porém destrói o terreno a jusante. Por isso, a análise do projeto precisa observar todo o caminho do fluxo, da crista à dissipação final.

Erro frequente de concepção

É comum encontrar projetos que se concentram apenas na largura do vertedor e negligenciam o trecho imediatamente após a descarga. O resultado é um vertedor funcional no papel, mas com jatos de água lançados sobre solo natural não protegido. Nesse caso, a obra fica vulnerável à erosão mesmo sem falha da soleira.

4.6 Critérios básicos de verificação

Em nível preliminar, o projetista deve verificar, no mínimo:

1. se a vazão de projeto pode ser conduzida sem elevação excessiva do nível d'água;
2. se a cota de crista preserva folga livre suficiente;
3. se a água descarregada não atinge o maciço de terra;
4. se o canal de aproximação e a saída possuem proteção contra erosão;
5. se a dissipação é compatível com a energia do escoamento;
6. se há segurança para inspeção e manutenção.

Pergunta essencial

Toda verificação hidráulica deve responder a uma pergunta simples: a água, ao passar pelo sistema, permanece sob controle em todas as etapas? Se a resposta for não, o projeto precisa ser revisto.

4.7 Vertedores no contexto semiárido

No semiárido, a relação entre cheias concentradas e longos períodos secos torna a segurança hidráulica ainda mais relevante. A obra pode passar muito tempo com nível baixo, mas quando a cheia chega, ela pode ser intensa e rápida. Isso exige:

- vertedor bem implantado;
- canal de aproximação livre de obstruções;
- manutenção periódica;
- inspeção após eventos extremos;
- proteção contra assoreamento e vegetação invasora.

Cheias raras não significam cheias irrelevantes

Em regiões semiáridas, o fato de grandes vazões serem menos frequentes não reduz sua importância de projeto. Ao contrário, a raridade pode induzir subestimação do risco. O vertedor precisa estar preparado para o evento de maior consequência, e não apenas para a condição ordinária.

4.8 Resumo do capítulo

Resumo do capítulo

- O vertedor é o principal dispositivo de segurança hidráulica para descarregar vazões excedentes.
- Em barragens de terra, o extravasamento não deve ocorrer sobre o aterro.
- A folga livre protege a barragem contra ondas, incertezas hidrológicas e variações operacionais.
- Vertedores podem ser de soleira livre, laterais, em canal revestido ou com queda, entre outras configurações.
- Em nível preliminar, a capacidade de descarga cresce com a largura do vertedor e com a carga hidráulica.
- A bacia de dissipação reduz a energia do escoamento e protege o terreno a jusante.
- Vertedor e dissipação devem ser tratados como um sistema único de segurança hidráulica.
- No semiárido, cheias concentradas exigem atenção redobrada ao extravasamento e à manutenção.

4.9 Exercícios

Exercícios de fixação — nível F

F1. Qual é a função principal do vertedor em um açude?

F2. Por que a água não deve passar livremente sobre uma barragem de terra?

F3. O que é bacia de dissipação?

F4. Cite dois riscos associados ao extravasamento mal conduzido.

F5. Por que a folga livre é importante?

Exercícios de aplicação — nível M

M1. Explique, em linguagem técnica, por que o vertedor deve ser independente do maciço de terra.

M2. Interprete qualitativamente a expressão $Q = CLH^{3/2}$: o que acontece com a capacidade de descarga quando L aumenta?

M3. Compare, em poucas linhas, uma bacia de dissipação e um canal apenas revestido.

M4. Cite três verificações básicas que devem ser feitas em um sistema vertedor-dissipador.

Exercícios de integração — nível D

D1. Uma barragem de terra foi projetada com vertedor estreito e dissipação insuficiente. Após uma cheia intensa, surgiram sulcos profundos a jusante e erosão próxima ao canal de fuga. Analise o problema e indique, em termos conceituais, quais mecanismos de falha podem estar em desenvolvimento.

D2. Considere duas alternativas de vertedor para um pequeno açude: a primeira é mais simples, mas conduz a água muito próxima da ombreira; a segunda é mais longa, porém descarrega em terreno melhor protegido. Qual tende a ser mais segura do ponto de vista hidráulico e por quê?

D3. Em que sentido o projeto do vertedor precisa dialogar com a curva cota-volume-área estudada no capítulo anterior?

4.10 Gabarito comentado

Gabarito comentado — nível F

F1. Conduzir as vazões excedentes de forma segura, preservando a integridade da barragem e do reservatório.

F2. Porque o fluxo sobre aterro de terra tende a erodir rapidamente o material, podendo gerar ruptura por galgamento e escavação progressiva.

F3. É a estrutura localizada a jusante do vertedor destinada a reduzir a energia do fluxo e proteger o terreno contra erosão.

F4. Resposta possível: erosão do canal, galgamento, instabilidade do talude, escavação a jusante e ruptura do aterro.

F5. Porque ela fornece margem entre o nível máximo da água e a crista da barragem, ajudando a acomodar ondas e incertezas.

Gabarito comentado — nível M

M1. O vertedor deve ser independente para que o extravasamento não atinja o maciço de terra. Caso a água transborde sobre o aterro, a erosão pode comprometer a estabilidade da barragem rapidamente.

M2. A capacidade de descarga aumenta. Em termos qualitativos, quanto maior a largura útil do vertedor, maior a vazão possível para uma mesma carga hidráulica.

M3. O canal revestido tem função principal de condução estável do fluxo; a bacia de dissipação tem função de reduzir energia e proteger a jusante. O primeiro não substitui o segundo.

M4. Verificações esperadas: capacidade para a cheia de projeto; folga livre adequada; proteção contra erosão no canal e na saída; e controle da energia do escoamento a jusante.

Gabarito comentado — nível D

D1. Há indícios de falha hidráulica progressiva. O vertedor estreito pode ter imposto sobrecarga de nível, enquanto a dissipação insuficiente permitiu que a energia remanescente do fluxo causasse erosão regressiva, escavação do solo e possível instabilidade local. Se o problema avançar, pode ocorrer deterioração do canal, colapso da proteção e comprometimento da segurança da barragem.

D2. A segunda alternativa tende a ser mais segura, desde que seja bem executada. Em hidráulica de barragens, não basta descarregar a água; é preciso controlar a trajetória do fluxo e sua energia. Descarregar em terreno melhor protegido reduz o risco de erosão e de danos a jusante.

D3. O projeto do vertedor precisa ser compatível com a geometria do reservatório. A curva cota-volume-área define o comportamento do nível d'água durante o enchimento e a cheia. Se o reservatório enche rapidamente ou apresenta grande variação de área, isso influencia a cota máxima admissível, a folga livre e a demanda de descarga do vertedor.

Conexão com o próximo capítulo

Depois de compreender como o açude descarrega suas cheias com segurança, o leitor está pronto para avançar para a execução da própria barragem de terra. No próximo capítulo, serão abordados os processos construtivos, a compactação, o controle tecnológico e os cuidados necessários para transformar o projeto em uma estrutura estável e durável.

Parte III

Construção, instrumentação e segurança

Capítulo 5

Construção de barragens de terra

Objetivos de aprendizagem

Ao final deste capítulo, espera-se que o leitor seja capaz de:

- compreender a lógica construtiva de uma barragem de terra;
- reconhecer a importância da fundação, do tratamento de base e das ombreiras;
- distinguir os papéis do núcleo, dos filtros, dos drenos e das proteções superficiais;
- interpretar o papel da compactação na estabilidade e na impermeabilidade do maciço;
- identificar métodos usuais de controle tecnológico em obra;
- reconhecer patologias construtivas e suas causas mais prováveis;
- relacionar a construção em campo às condições específicas do semiárido.

A barragem de terra é, em muitos açudes, a solução tecnicamente mais racional e economicamente mais viável. Entretanto, sua aparente simplicidade é enganosa. Uma barragem de terra não é um monte de solo depositado sobre o vale; ela é uma estrutura geotécnica cuidadosamente planejada, executada em camadas, controlada em teor de umidade e compactação, apoiada sobre fundação preparada e protegida contra infiltração, erosão e instabilidade.

No semiárido, essa exigência é ainda maior. A obra costuma ser executada em ambiente com janela climática limitada, logística desafiadora e necessidade de máxima confiabilidade. Pequenos desvios de execução podem se transformar, no futuro, em caminhos preferenciais de percolação, erosão interna, recalques diferenciais ou falhas localizadas. Por isso, construir bem é tão importante quanto projetar bem.

5.1 Da concepção ao canteiro

A construção começa muito antes da primeira escavação. O projeto executivo deve ter definido a seção transversal, as cotas de fundação, o traçado do eixo, a posição do vertedor, os acessos e a logística básica. A obra em si é a etapa em que decisões de papel passam a interagir com material real, clima, equipamentos e pessoas.

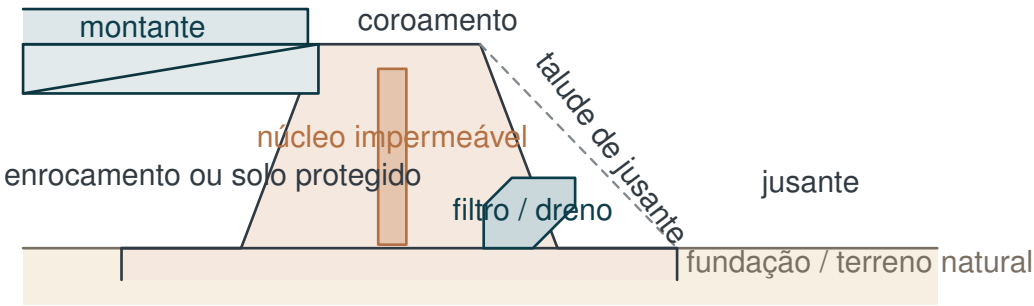

Figura 5.1 – Esquema conceitual de uma barragem de terra zonada, com núcleo impermeável, filtros e drenagem de pé.

5.1.1 Planejamento da obra

Em regiões semiáridas, o planejamento da construção deve considerar:

- a janela seca mais favorável para terraplenagem;
- a disponibilidade de água para umedecimento do material;
- o transporte de solos e agregados;
- a proteção do canteiro contra chuvas inesperadas;
- a sequência de execução do vertedor, da fundação e do maciço;
- a compatibilização entre obra civil e controle ambiental.

Construir na estação errada costuma custar caro

Em barragens de terra, a execução em período chuvoso eleva o risco de contaminação do material, interrupções frequentes, perda de umidade controlada e compactação deficiente. Quando possível, a terraplenagem principal deve ser concentrada em períodos mais secos e previsíveis.

5.1.2 A obra como sistema de etapas

Uma barragem de terra bem construída depende da integração entre:

- limpeza e preparação da fundação;
- execução de dispositivos de impermeabilização;
- deposição e compactação do maciço;
- construção de filtros, drenos e proteções;
- tratamento dos encontros com as ombreiras;
- acabamento do coroamento e dos taludes;
- controle tecnológico contínuo.

5.2 Materiais de empréstimo e zonamento do maciço

A construção de barragens de terra depende da escolha correta dos materiais. Nem todo solo serve para qualquer parte da seção. Em muitos casos, a solução é **zonada**, isto é, composta por regiões com funções distintas.

5.2.1 Materiais usuais

Em geral, podem ser utilizados:

- solos argilosos ou argilo-siltosos para núcleo impermeável;
- solos mais arenosos ou areno-argilosos para zonas de transição, desde que compatíveis com o filtro e o projeto;
- materiais mais granulares para drenagem e proteção interna;
- enrocamento ou rip-rap para proteção superficial;
- solos compactáveis de boa trabalhabilidade para o corpo principal.

Material de empréstimo

Material de empréstimo é o solo ou agregado retirado de área externa à seção da barragem, com características apropriadas para compor o maciço, os filtros, os drenos ou as proteções da obra.

5.2.2 Critérios de seleção do material

O material adequado deve apresentar:

- granulometria compatível com a função prevista;
- plasticidade e coesão suficientes quando se busca baixa permeabilidade;
- baixa presença de matéria orgânica;
- comportamento estável sob compactação;
- trabalhabilidade dentro da faixa de umidade de obra;
- disponibilidade em quantidade suficiente.

Solo bom para barragem não é necessariamente solo bom para todo o maciço

O núcleo pede um material mais impermeável; o corpo da barragem pode aceitar solos menos plásticos; os filtros exigem granulometria controlada; os drenos precisam de permeabilidade. Por isso, a barragem de terra não deve ser tratada como uma massa homogênea de solo indiferenciado.

5.2.3 Zonamento

Em uma barragem zonada, cada região possui uma função:

- **núcleo**: reduzir a percolação;
- **transições**: compatibilizar o núcleo com zonas mais granulares;
- **corpo principal**: conferir massa, estabilidade e forma geométrica;
- **filtros**: impedir carreamento de finos;
- **drenos**: coletar e conduzir a água que eventualmente percola;
- **proteções superficiais**: evitar erosão por chuva, ondas e escoamento.

Essa organização interna é uma das chaves da segurança de uma barragem de terra.

5.3 Preparação da fundação

A fundação é a interface entre a estrutura e o terreno natural. Sua preparação inadequada é causa frequente de problemas futuros, especialmente em regiões onde o subsolo apresenta heterogeneidade local.

5.3.1 Limpeza e decapagem

A primeira medida é a retirada de:

- vegetação;
- solo orgânico;
- material solto e instável;
- blocos desagregados;
- detritos e raízes.

Essa etapa garante que o aterro seja apoiado sobre superfície estável e com comportamento minimamente previsível.

5.3.2 Tratamento da base

Dependendo das condições do terreno, podem ser necessários:

- escavação de vala de vedação;
- regularização e scarificação da superfície;
- umedecimento ou secagem controlada;
- compactação do subleito;

- tratamento de fissuras, fraturas e pontos de infiltração;
- execução de colchões filtrantes ou camadas de transição.

Vala de vedação

Vala de vedação é a escavação realizada na fundação, geralmente ao longo do eixo da barragem, para interceptar caminhos preferenciais de percolação e melhorar a conexão entre o maciço e o terreno natural.

A fundação também é parte da barragem

Não existe barragem de terra segura se a fundação for tratada como detalhe secundário. O maciço pode estar bem compactado, mas se a fundação permitir percolação excessiva ou recalques desiguais, o desempenho global será comprometido.

5.3.3 Encontros com ombreiras

As ombreiras são os apoios laterais da barragem nas encostas do vale. Nelas, o contato entre aterro e terreno natural precisa ser cuidadosamente tratado para evitar caminhos preferenciais de infiltração. O encontro entre obra e encosta deve ter:

- limpeza rigorosa;
- regularização de superfície;
- compactação adequada nas proximidades;
- tratamento de fissuras e descontinuidades;
- transições bem desenhadas entre materiais diferentes.

5.4 Compactação e controle da umidade

A compactação é o coração da construção de barragens de terra. Ela reduz vazios, aumenta a resistência ao cisalhamento, diminui a compressibilidade e controla a permeabilidade do aterro. A ideia central é simples: material colocado sem compactação adequada não se comporta como maciço de barragem.

5.4.1 Conceito de compactação

Compactar é aplicar energia ao solo para reorganizar suas partículas e alcançar maior densidade seca. Essa densificação melhora:

- a estabilidade do talude;
- a resistência à deformação;
- o desempenho hidráulico;

- a homogeneidade do maciço;
- a durabilidade da estrutura.

Solo muito seco ou muito úmido é problema

Se o solo estiver muito seco, a compactação tende a ser ineficiente e o volume de vazios permanece elevado. Se estiver muito úmido, a energia aplicada pode ser dissipada na movimentação excessiva da água nos poros, gerando bombeamento, deformações e perda de suporte. O ideal é trabalhar próximo da umidade ótima definida em projeto.

5.4.2 Umidade ótima e massa específica seca máxima

O ensaio de compactação em laboratório, como o Proctor, fornece a relação entre umidade e massa específica seca do solo. A partir dessa curva, obtém-se a **umidade ótima** e a **massa específica seca máxima**, que servem de referência para o controle em obra.

Em forma simplificada, o grau de compactação pode ser expresso por

$$GC = \frac{\gamma_{d,\text{campo}}}{\gamma_{d,\text{máx}}} \times 100$$

em que $\gamma_{d,\text{campo}}$ é a massa específica seca obtida em campo e $\gamma_{d,\text{máx}}$ é a massa específica seca máxima de laboratório.

O número não substitui o julgamento técnico

O grau de compactação é um indicador importante, mas não deve ser lido isoladamente. Um solo pode apresentar bom valor de densidade e, ainda assim, ter umidade inadequada, segregação de material, baixa homogeneidade ou execução deficiente nas zonas críticas.

5.4.3 Espessura de camada e equipamento

A compactação deve ser feita em camadas delgadas e uniformes, compatíveis com o equipamento empregado. Em muitos casos, espessuras de camada compactada da ordem de 15 cm a 25 cm são adotadas, sempre conforme o projeto executivo, o tipo de solo e a energia de compactação disponível.

5.4.4 Sequência prática de compactação

A execução deve observar:

1. espalhamento do material em camada uniforme;
2. correção de umidade, se necessário;
3. compactação com número adequado de passadas;
4. verificação da espessura e da regularidade da camada;

Tabela 5.1 – Equipamentos usuais de compactação e aplicações típicas

Equipamento	Aplicação mais comum	Vantagem principal	Limitação típica
Pé-de-carneiro	Solos coesivos e mistos	Boa ação de amassamento e desagregação de torrões	Menor eficiência em materiais muito granulares
Rolo liso vibratório	Materiais granulares e mistos	Elevada produtividade e boa densificação	Menor ação em solos muito argilosos e plásticos
Rolo pneumático	Amplas faixas de materiais	Boa uniformidade e adaptação ao maciço	Requer controle operacional mais cuidadoso

5. limpeza da superfície antes da camada seguinte;
6. continuidade sem longas interrupções que gerem planos fracos.

Falha por camada mal executada

Uma camada muito espessa, compactada com equipamento inadequado, pode parecer satisfatória na superfície, mas conter material frouxo no interior. Esse defeito é particularmente perigoso porque cria zonas preferenciais para percolação e deformação futura.

5.5 Proteções internas e superficiais

Além do corpo compactado, a barragem de terra precisa de dispositivos que limitem a infiltração, conduzam a água interna e protejam o maciço contra erosão externa.

5.5.1 Filtros

Os filtros têm a função de impedir o carreamento de finos, permitindo a passagem de água sem perda do material do núcleo ou do terreno adjacente. Em termos práticos, um filtro bem projetado deve ser suficientemente permeável para conduzir a água, mas suficientemente seletivo para reter partículas finas.

5.5.2 Drenos

Os drenos coletam a água que eventualmente percola pelo maciço ou pela fundação e a conduzem para local seguro. Eles ajudam a:

- aliviar pressões neutras;

- reduzir risco de saturação interna;
- sinalizar eventual aumento de percolação;
- proteger contra piping e surgimento de nascentes a jusante.

5.5.3 Proteção dos taludes

Os taludes devem ser protegidos contra:

- erosão por chuva;
- ação de ondas;
- escoamento superficial;
- intemperismo;
- vegetação inadequada e ravinamento.

As proteções podem incluir solo vegetal estabilizado, enrocamento, revestimentos e soluções combinadas, sempre considerando as condições locais e o uso do reservatório.

Proteção superficial não é enfeite

Talude exposto é talude vulnerável. A proteção superficial não serve apenas para estética ou acabamento: ela é parte da segurança da barragem, sobretudo em obras onde chuvas intensas podem concentrar enxurradas sobre superfícies desprotegidas.

5.6 Controle tecnológico da obra

O controle tecnológico é o conjunto de verificações que assegura a conformidade entre o que foi projetado e o que está sendo executado. Em barragens de terra, ele é decisivo.

5.6.1 Principais controles em campo

5.6.2 O que o controle busca evitar

Os controles servem para evitar:

- compactação insuficiente;
- excesso de umidade;
- segregação de materiais;
- mistura de materiais incompatíveis;
- execução de camadas fora de espessura;
- descontinuidade entre trechos construídos em dias diferentes;
- perda de geometria do projeto.

Tabela 5.2 – Controles tecnológicos usuais na construção de barragens de terra

Controle	Finalidade	**Método usual**
Umidade do material	Verificar a condição de compactação	**Métodos expedidos de campo ou laboratório**
Massa específica seca	Avaliar o grau de densificação	**Areia, balão de borracha ou método nuclear**
Granulometria	Confirmar a aptidão do material	**Ensaio de peneiramento e sedimentação**
Limites de Atterberg	Verificar plasticidade e comportamento do solo fino	**Ensaios de consistência**
Espessura de camada	Garantir uniformidade do aterro	**Medição geométrica em campo**
Geometria final	Conferir cotas, taludes e coroamento	**Levantamento topográfico**

Registro é parte da qualidade

O controle não deve depender apenas da inspeção visual. Resultados de ensaios, medições de campo, registros fotográficos e rastreabilidade do material são fundamentais para a confiabilidade da obra e para a futura interpretação do comportamento da barragem.

5.7 Sequência executiva recomendada

A construção de uma barragem de terra pode ser organizada em uma sequência lógica, da base para o coroamento.

Essa sequência não é apenas organizacional; ela também reduz riscos. Quando a base é tratada corretamente e o núcleo é protegido desde o início, a barragem tende a apresentar melhor comportamento ao longo do tempo.

5.8 Patologias construtivas mais comuns

Os defeitos mais frequentes em barragens de terra costumam nascer na execução. Entre os mais importantes estão:

- compactação deficiente;
- heterogeneidade excessiva do material;

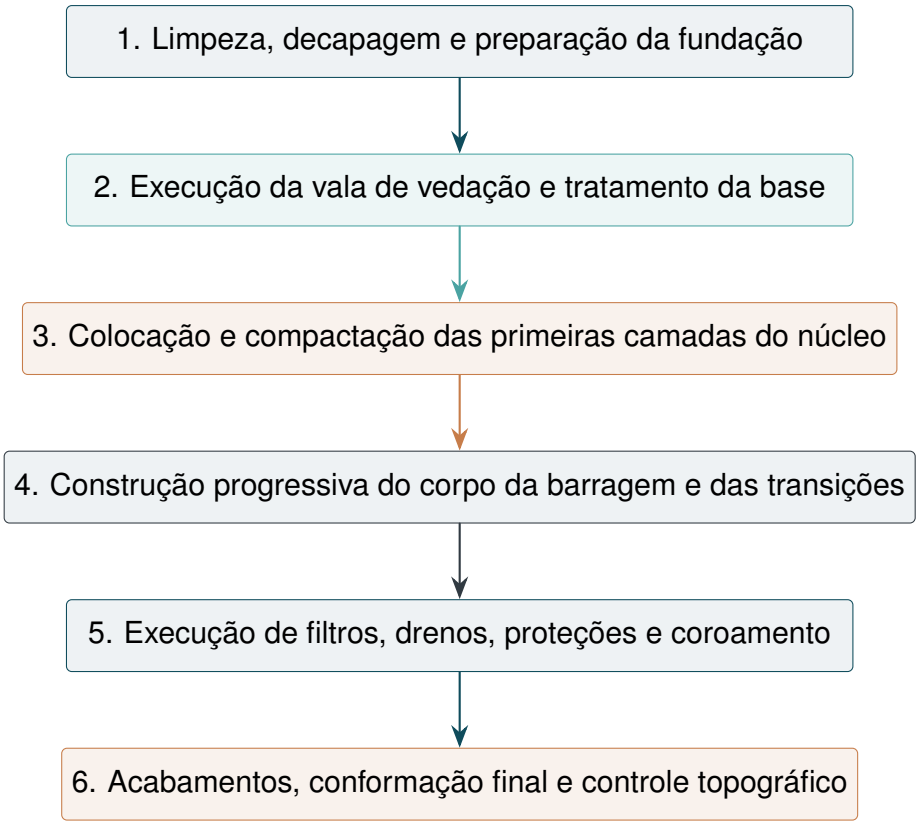

Figura 5.2 – Sequência simplificada de execução de uma barragem de terra.

- umidade fora da faixa de trabalho;
- interfaces mal tratadas entre camadas;
- ombreiras mal conectadas ao corpo da barragem;
- filtros e drenos mal dimensionados ou mal executados;
- proteção superficial insuficiente;
- coroamento irregular ou baixo demais;
- ausência de registros de controle.

Erro clássico

Um erro recorrente é considerar a barragem pronta quando o aterro atinge a cota de projeto. Na realidade, o acabamento, a proteção superficial, a adequação do coroamento e a verificação geométrica são parte essencial da obra e influenciam sua durabilidade.

5.9 Construção no contexto semiárido

No semiárido, a obra precisa conviver com condições específicas:

- longos períodos secos, que favorecem terraplenagem, mas aumentam o risco de poeira e perda de umidade;

Tabela 5.3 – Patologias construtivas, causas prováveis e prevenção

Patologia	Causa provável	**Prevenção básica**
Recalque excessivo	Compactação insuficiente ou material inadequado	**Controle de umidade, espessura e energia de compactação**
Percolação anômala	Núcleo defeituoso, junta mal tratada ou fundação permeável	**Tratamento de fundação e execução correta das transições**
Erosão superficial	Falta de proteção dos taludes ou drenagem ruim	**Proteção superficial e drenagem de águas pluviais**
Ravinas no talude	Enxurrada concentrada ou vegetação mal conduzida	**Controle de águas de chuva e manutenção periódica**
Trincas e fissuras	Recalque diferencial, secagem excessiva ou transição ruim	**Homogeneidade construtiva e boa gestão de umidade**

- chuvas intensas e concentradas, que podem interromper a execução e erodir material exposto;
- disponibilidade irregular de água para umedecimento e controle de compactação;
- logística por vezes distante de jazidas e centros de apoio;
- forte necessidade de proteção contra erosão e assoreamento.

Decisão operacional sábia

Muitas vezes, vale mais a pena aguardar um período mais estável do que tentar acelerar a obra durante uma sequência de chuvas. Em barragens de terra, o custo de corrigir camadas mal executadas ou de reconstruir taludes erodidos costuma ser muito maior do que o custo de uma programação mais cuidadosa.

5.10 Resumo do capítulo

Resumo do capítulo

- Barragens de terra exigem execução em camadas, compactação controlada e tratamento rigoroso da fundação.
- O material de empréstimo deve ser compatível com a função de cada zona do maciço.
- Núcleo, filtros, drenos e proteções superficiais têm funções diferentes e complementares.
- A umidade ótima e a massa específica seca máxima orientam o controle da compactação.
- O grau de compactação é um indicador importante, mas não substitui a avaliação global do maciço.
- O controle tecnológico envolve umidade, densidade, granulometria, limites de consistência, espessura de camada e geometria final.
- A sequência executiva deve priorizar fundação, núcleo, corpo principal, dispositivos internos e acabamento.
- No semiárido, a janela de obra, a proteção contra chuva e a logística de materiais são fatores decisivos.

5.11 Exercícios

Exercícios de fixação — nível F

F1. Por que uma barragem de terra não pode ser tratada como um simples aterro?

F2. Qual é a função do núcleo impermeável?

F3. Explique a diferença entre filtro e dreno.

F4. O que representa a compactação no desempenho de uma barragem de terra?

F5. Por que a preparação da fundação é tão importante?

Exercícios de aplicação — nível M

M1. Em uma barragem zonada, por que nem todo material pode ser usado em qualquer parte da seção?

M2. Descreva quatro etapas essenciais do processo de compactação em campo.

M3. Explique por que trabalhar com solo muito úmido pode ser prejudicial à barragem.

M4. Cite três controles tecnológicos usuais em obra e indique o que cada um verifica.

Exercícios de integração — nível D

D1. Uma barragem de terra foi executada com material heterogêneo, camada espessa, umidade excessiva e pouca fiscalização. Discuta os principais riscos que podem aparecer no curto e no longo prazo.

D2. Em uma obra semiárida, a compactação foi interrompida por chuvas intensas, e parte do aterro ficou exposta por vários dias. Analise os efeitos possíveis sobre homogeneidade, estabilidade e manutenção futura.

D3. Se você fosse responsável pelo controle de qualidade de uma barragem de terra, quais informações registraria em campo para garantir rastreabilidade e segurança da execução?

5.12 Gabarito comentado

Gabarito comentado — nível F

F1. Porque ela precisa cumprir requisitos geotécnicos e hidráulicos específicos, com compactação controlada, drenagem interna e proteção contra erosão.

F2. Reduzir a percolação através do maciço, funcionando como a principal barreira à passagem de água.

F3. O filtro evita o carreamento de finos; o dreno coleta e conduz a água percolada para local seguro.

F4. Ela aumenta a densidade, reduz vazios, melhora resistência e controla a permeabilidade do aterro.

F5. Porque a barragem depende do apoio adequado da base. Se a fundação estiver fraca, permeável ou mal tratada, todo o maciço pode ser comprometido.

Gabarito comentado — nível M

M1. Porque cada zona tem função distinta. O núcleo precisa ser mais impermeável; o corpo principal precisa garantir estabilidade; o filtro precisa ser seletivo; o dreno precisa ser permeável. Misturar funções sem critério reduz a segurança da obra.

M2. Resposta esperada: espalhar a camada de forma uniforme; corrigir a umidade; compactar com equipamento adequado; controlar espessura e número de passadas; limpar a superfície antes da próxima camada.

M3. Solo muito úmido pode perder suporte, sofrer bombeamento e gerar baixa eficiência de compactação. A água em excesso ocupa os vazios e reduz a capacidade de densificação.

M4. Exemplos: umidade do material, massa específica seca, granulometria, limites de Atterberg, espessura de camada e geometria final. O importante é explicar a finalidade de cada controle.

Gabarito comentado — nível D

D1. Os riscos incluem baixa densidade, recalques, permeabilidade excessiva, instabilidade de taludes, surgimento de caminhos de percolação e erosão interna. A curto prazo, podem aparecer deformações e trincas; a longo prazo, o comportamento hidráulico e a segurança da barragem ficam comprometidos.

D2. Pode haver perda de homogeneidade, reidratação ou secagem desigual, erosão superficial, contaminação do material e interrupção da sequência de compactação. Isso cria juntas fracas e reduz a confiabilidade do aterro.

D3. Devem ser registrados, por exemplo: origem do material, data e trecho executado, condições de umidade, número de passadas, espessura da camada, equipamentos utilizados, resultados de ensaios, cotas topográficas e observações de não conformidade. A rastreabilidade é essencial para qualidade e futura inspeção.

Conexão com o próximo capítulo

Com a barragem de terra construída, compactada e protegida, a obra entra em uma nova fase: a de observação do comportamento ao longo do tempo. No próximo capítulo, serão estudados a instrumentação, a inspeção e a segurança de barragens, incluindo piezômetros, marcos superficiais, sinais de anomalia e o enquadramento pela Lei nº 12.334/2010.

Capítulo 6

Instrumentação, inspeção e segurança de barragens

Objetivos de aprendizagem

Ao final deste capítulo, espera-se que o leitor seja capaz de:

- compreender a finalidade da instrumentação em barragens de terra e açudes;
- distinguir instrumentação de inspeção visual e interpretar sua complementaridade;
- reconhecer os principais instrumentos usados em pequenos e médios açudes;
- identificar sinais de anomalia relacionados a percolação, recalque, erosão e instabilidade;
- entender, em nível introdutório, o papel da Lei nº 12.334/2010 na segurança de barragens;
- relacionar monitoramento, operação e resposta a eventos anormais.

Uma barragem não é um objeto estático. Depois de construída, ela continua interagindo com a água, com o solo, com o clima e com o uso humano. Esse comportamento evolui ao longo do tempo por efeito de recalques, variações sazonais do nível do reservatório, percolação interna, erosão superficial, envelhecimento dos materiais e ações de manutenção. Por isso, o desempenho de uma barragem precisa ser observado e interpretado continuamente.

É nesse contexto que entram a instrumentação e a inspeção. A instrumentação fornece medidas; a inspeção fornece leitura crítica do estado físico da obra. Em conjunto, elas permitem detectar tendências anormais antes que se transformem em falhas graves. Em açudes do semiárido, onde eventos de cheia podem ser concentrados e a degradação por calor e secagem também é intensa, essa vigilância é ainda mais importante.

6.1 Por que monitorar a barragem

A finalidade da instrumentação é observar o comportamento interno e externo da barragem ao longo do tempo. Ela ajuda a responder perguntas essenciais:

- a água está percolando em quantidade compatível com o esperado?

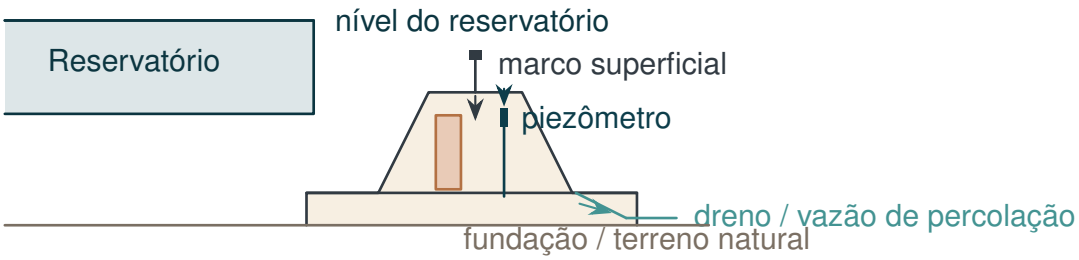

Figura 6.1 – Instrumentos e pontos de observação típicos em uma barragem de terra.

- o maciço está se deformando de modo aceitável?
- surgiram recalques, trincas ou deslocamentos anormais?
- o nível do reservatório está alterando as pressões internas como previsto?
- a descarga de percolação está limpa, turva ou crescente?

Auscultação

Auscultação é o conjunto de observações, leituras e análises destinado a acompanhar o comportamento de uma barragem ao longo do tempo, combinando instrumentação, inspeção visual e registro sistemático dos dados.

Auscultar uma barragem não significa apenas medir. Significa interpretar a obra como um sistema vivo, com tendência histórica. Leituras isoladas podem ser pouco informativas; já a evolução das leituras ao longo do tempo revela padrões, mudanças de regime e possíveis anomalias.

Sem monitoramento não há referência de normalidade

Uma barragem sem registros de comportamento não oferece base objetiva para distinguir variação normal de alteração preocupante. A rotina de monitoramento cria a linha de base que permite perceber quando algo sai do padrão.

6.2 Instrumentação básica em açudes e pequenas barragens

Em pequenos e médios açudes, a instrumentação pode ser relativamente simples, desde que bem escolhida e corretamente instalada. O princípio não é ter muitos aparelhos, mas os instrumentos certos nos pontos certos.

6.2.1 Piezômetros

Os piezômetros medem a pressão da água nos poros do solo ou, de forma equivalente, a posição da linha piezométrica em regiões de interesse. Em barragens de terra, são úteis para avaliar como a água está se distribuindo no interior do maciço e da fundação.

Podem ser instalados em diferentes profundidades e posições, por exemplo:

- no corpo da barragem;
- próximo ao núcleo impermeável;
- na fundação;
- nas zonas de transição.

O que o piezômetro ajuda a enxergar

Se o nível piezométrico cresce além do esperado ou apresenta resposta anormal em relação ao nível do reservatório, pode haver indício de percolação excessiva, drenagem insuficiente ou alteração interna no maciço.

6.2.2 Marcos superficiais

Os marcos superficiais ou marcos de recalque são pontos de referência instalados na crista, nos taludes ou em áreas adjacentes. Eles servem para acompanhar deslocamentos verticais e, em alguns casos, horizontais.

Seu uso é particularmente importante porque:

- barragens de terra sofrem assentamentos ao longo do tempo;
- parte do recalque é esperado e precisa ser quantificado;
- deslocamentos diferenciais podem indicar comportamento anômalo;
- o coroamento precisa manter a cota de segurança prevista.

6.2.3 Medição de vazão de percolação

A percolação é uma das variáveis mais importantes em barragens de terra. Quando a água atravessa a fundação, os drenos ou a zona de controle interna, ela deve ser coletada e medida de forma a indicar se o comportamento está dentro do previsto.

Os dispositivos mais comuns incluem:

- caixas de inspeção;
- calhas e canais de medição;
- vertedouros simples de laboratório de campo;
- estruturas de controle em drenagem de pé.

6.2.4 Régua linimétrica ou escala de nível

A leitura do nível do reservatório é simples, mas fundamental. A régua linimétrica permite relacionar o nível d'água com a curva cota-volume e com a operação do vertedor. Em

pequenos açudes, essa observação visual pode ser o primeiro sinal de que o reservatório está entrando em regime anormal.

Tabela 6.1 – Principais instrumentos e sua função em barragens de terra

Instrumento	Função principal	**O que observar**
Piezômetro	Medir pressão de água nos poros / nível piezométrico	**Variação com o nível do reservatório, resposta temporal e tendência**
Marco superficial	Medir recalques e deslocamentos do coroamento ou taludes	**Assentamento diferencial, subsidência e movimentações anormais**
Caixa de medição de percolação	Quantificar vazões de drenagem ou surgência controlada	**Aumento de vazão, turbidez e presença de finos**
Régua linimétrica	Acompanhar o nível do reservatório	**Cota de operação, resposta a cheias e faixa de segurança**
Pluviômetro local	Relacionar chuva com resposta do reservatório e da obra	**Intensidade de eventos e correlação com anomalias**

Instrumento simples pode ser muito valioso

Em muitas pequenas barragens, a combinação de uma régua de nível, alguns marcos de recalque e uma boa caixa de medição de percolação já fornece informação suficiente para detectar tendências importantes, desde que haja rotina de leitura e registro.

6.3 Inspeção visual: o primeiro sensor da barragem

A inspeção visual é a forma mais imediata de monitoramento. Ela deve ser sistemática, periódica e atenta aos detalhes. Mesmo com instrumentação, o olhar técnico continua indispensável.

6.3.1 O que observar

A inspeção deve verificar, no mínimo:

- trincas no coroamento e nos taludes;
- erosões superficiais;
- recalques e depressões;
- surgência de água a jusante;
- manchas úmidas persistentes;
- vegetação anômala indicando umidade excessiva;
- buracos de animais e escavações;
- deterioração de proteção superficial;
- obstrução do vertedor e dos dispositivos de descarga;
- depósito de sedimentos nas áreas críticas.

A água dá sinais antes da ruptura

Muitas falhas começam com pequenos sintomas: um ponto úmido, uma fissura, um filete de água turva, uma erosão discreta no pé do talude. O erro comum é normalizar o sintoma até que ele deixe de ser pequeno.

6.3.2 Inspeção de rotina e inspeção especial

A rotina pode ser dividida em:

- **inspeção de rotina**: realizada periodicamente, para acompanhar a condição ordinária da obra;
- **inspeção especial**: realizada após eventos incomuns, como chuvas intensas, enchimento rápido, registros anômalos ou obras de manutenção;
- **inspeção emergencial**: realizada quando há sinais de risco imediato ou progressivo.

6.4 Sinais de anomalia e interpretação preliminar

Uma anomalia não é necessariamente uma falha, mas é sempre um sinal de que o comportamento merece atenção. A interpretação correta depende da frequência, da localização, da evolução e da intensidade do sintoma.

Tabela 6.2 – Exemplo de rotina de inspeção por tipo de evento

Situação	Foco principal da inspeção
Operação normal	Estado geral da barragem, vegetação, nivelamento do coroamento, drenagem e limpeza do vertedor
Após chuva intensa	Galgamento, erosões, surgências, obstruções, recalques e resposta dos drenos
Após rápido enchimento	Piezometria, deformações e surgência de água a jusante
Após manutenção	Verificação da qualidade dos reparos e da continuidade do desempenho esperado

Tabela 6.3 – Sinais de anomalia, possíveis causas e implicações

Sinal observado	Possível causa	**Implicação potencial**
Trinca longitudinal no coroamento	Recalque diferencial, secagem ou movimentação interna	**Perda de homogeneidade e caminho preferencial de infiltração**
Ponto úmido persistente a jusante	Percolação concentrada, dreno insuficiente ou falha de vedação	**Erosão interna ou surgência anômala**
Água turva na drenagem	Carreamento de finos	**Início de piping ou degradação interna**
Erosão na face de montante ou jusante	Proteção superficial inadequada ou ação de chuva/ondas	**Redução da seção útil e fragilidade local**
Recalque em um trecho da crista	Compactação deficiente ou fundação compressível	**Redução da folga livre e alteração geométrica**
Vegetação muito vigorosa em área úmida isolada	Infiltração localizada ou vazamento	**Indício indireto de percolação anormal**

6.4.1 Anomalias comuns

Percolação não é sempre problema, mas precisa ser controlada

Toda barragem de terra admite algum grau de percolação. O problema não é a existência de fluxo interno em si; o problema é a existência de fluxo fora do padrão, concentrado, turvo, crescente ou associado a perda de material.

6.4.2 O que mais preocupa

Três situações merecem atenção especial:

- surgência de água com solo carregado de finos;
- aumento repentino de vazão de drenagem;
- deformações acompanhadas de trincas e abatimentos.

Esses sinais podem indicar erosão interna, instabilidade local ou alteração do regime hidráulico interno. Em qualquer caso, a reação deve ser imediata e tecnicamente orientada.

6.5 Segurança de barragens e enquadramento legal

A segurança de barragens não depende apenas da execução física da obra. Ela envolve gestão, documentação, inspeção, monitoramento e preparação para resposta a emergências. No Brasil, a Lei nº 12.334/2010 estabelece a Política Nacional de Segurança de Barragens.

Segurança de barragens

Segurança de barragens é o conjunto de ações e condições que visa garantir a integridade da obra, a preservação da vida, do meio ambiente e dos bens associados ao reservatório e à área a jusante.

A lógica da política de segurança é simples: uma barragem precisa ser conhecida, monitorada, classificada e acompanhada ao longo de sua vida útil. Mesmo quando a obra é pequena, a mentalidade de segurança deve ser incorporada desde o início.

6.5.1 Elementos centrais da gestão de segurança

Em termos gerais, a gestão de segurança envolve:

- cadastro e documentação da barragem;
- inspeções periódicas;
- análise de anomalias;
- registros de instrumentação;
- planos de ação para situações críticas;

- organização da responsabilidade técnica e operacional.

Lei e prática devem andar juntas

A existência de norma legal não substitui a disciplina operacional. A segurança real depende de rotina, registro, manutenção e capacidade de intervenção, e não apenas do enquadramento formal da obra.

6.5.2 Categoria de risco e dano potencial associado

Dois conceitos são úteis para entender a priorização da segurança:

- **categoria de risco**: relaciona-se com as condições da barragem, seu estado, sua complexidade e sua vulnerabilidade;
- **dano potencial associado**: refere-se às consequências que uma eventual falha pode causar a jusante.

Esses parâmetros ajudam a definir o nível de atenção e as medidas de gestão necessárias. Em açudes de uso comunitário ou próximos a áreas ocupadas, o potencial de dano pode ser relevante mesmo em obras relativamente pequenas.

6.6 Plano de segurança, rotina de inspeção e resposta a emergências

Uma barragem segura é uma barragem administrada. O conhecimento técnico precisa se converter em procedimentos.

6.6.1 Conteúdo essencial de um plano de segurança

Em abordagem didática, o plano deve contemplar:

- identificação da barragem e de seus componentes;
- registros de projeto e construção;
- histórico de inspeções e instrumentação;
- critérios de operação;
- lista de anomalias conhecidas;
- ações corretivas e preventivas;
- responsáveis pela inspeção e pela tomada de decisão;
- procedimentos de comunicação em caso de emergência.

6.6.2 Resposta a anomalias

Diante de um sinal anormal, o procedimento mais prudente é:

1. registrar o evento com data, hora, local e foto;
2. comparar com leituras anteriores e com o comportamento esperado;
3. classificar o grau de urgência;
4. acionar apoio técnico quando necessário;
5. adotar medidas operacionais compatíveis com o risco, inclusive redução controlada do nível, se indicada;
6. acompanhar a evolução até a estabilização ou correção definitiva.

A pior resposta é a inércia

Quando uma barragem apresenta sinais anormais, esperar para ver se "vai melhorar sozinha" é uma conduta perigosa. Em geral, anomalias hidráulicas e geotécnicas exigem resposta estruturada e tempestiva.

6.7 Integração entre instrumentação e operação

A informação obtida com os instrumentos precisa alimentar a operação cotidiana do açude. Não basta medir; é preciso decidir com base nas medições.

6.7.1 Exemplos de integração

- se o piezômetro indica aumento persistente de pressões, a operação deve revisar a condição de drenagem e a segurança do maciço;
- se os marcos superficiais mostram recalque acelerado, a cota de coroamento e a folga livre precisam ser reavaliadas;
- se a drenagem de pé se torna turva, a barragem deve ser inspecionada com prioridade;
- se o reservatório sobe rapidamente após chuva intensa, o vertedor e a limpeza do canal precisam ser revisados.

Leitura prática de tendência

Se, após a estação chuvosa, os piezômetros mostram comportamento estável, os marcos superficiais permanecem praticamente constantes e a drenagem se mantém limpa, há indícios de bom desempenho global. Se, porém, um desses elementos passa a divergir do padrão histórico, a obra pede investigação.

6.8 Resumo do capítulo

Resumo do capítulo

- A instrumentação mede o comportamento da barragem; a inspeção visual interpreta sinais físicos da obra.
- O monitoramento deve observar piezometria, recalques, vazões de percolação, nível do reservatório e sinais visuais de anomalia.
- Em barragens de terra, piezômetros, marcos superficiais, réguas de nível e medição de drenagem são instrumentos especialmente úteis.
- Trincas, surgências, água turva, recalques e erosões são sinais que exigem leitura técnica.
- A segurança de barragens envolve gestão contínua, registros, inspeções, planos e resposta a anomalias.
- A Lei nº 12.334/2010 organiza o princípio de segurança e reforça a necessidade de acompanhamento sistemático.
- Categoria de risco e dano potencial associado ajudam a priorizar a atenção e os recursos de gestão.
- Monitorar sem decidir é insuficiente; a informação precisa alimentar a operação e a manutenção.

6.9 Exercícios

Exercícios de fixação — nível F

F1. O que é auscultação de barragens?

F2. Qual é a função de um piezômetro?

F3. Para que servem os marcos superficiais?

F4. Cite três sinais visuais de anomalia em uma barragem de terra.

F5. Qual é a relação entre instrumentação e segurança de barragens?

Exercícios de aplicação — nível M

M1. Explique por que a vazão de percolação deve ser medida e não apenas observada.

M2. Diferencie inspeção de rotina, inspeção especial e inspeção emergencial.

M3. Em que sentido a água turva que sai pela drenagem pode indicar risco?

M4. Cite quatro elementos que devem constar, em termos gerais, em um plano de segurança de barragem.

Exercícios de integração — nível D

D1. Uma barragem de terra apresenta, após um período chuvoso, aumento da vazão de drenagem, surgência úmida a jusante e água levemente turva na saída. Como você interpretaria esse quadro e quais providências iniciais seriam justificáveis?

D2. Um açude possui bons registros de instrumentação, mas a equipe operacional ignora as medições e não realiza inspeções visuais. Explique por que essa prática compromete a segurança.

D3. Relacione o conceito de dano potencial associado à presença de comunidades a jusante e à necessidade de resposta rápida em caso de anomalia.

6.10 Gabarito comentado

Gabarito comentado — nível F

F1. É o acompanhamento sistemático do comportamento da barragem por meio de medições, leituras e interpretação técnica.

F2. Medir a pressão da água nos poros do solo ou o nível piezométrico em pontos internos da barragem ou da fundação.

F3. Monitorar deslocamentos verticais e, em alguns casos, horizontais, ajudando a identificar recalques e deformações.

F4. Exemplo de resposta: trincas, surgências úmidas, erosões, água turva na drenagem, recalques no coroamento e vegetação anormalmente vigorosa.

F5. A instrumentação fornece dados objetivos que ajudam a identificar tendências anormais e a apoiar decisões operacionais e de manutenção.

Gabarito comentado — nível M

M1. Porque a quantidade de água, sua evolução temporal e sua qualidade indicam se a percolação está normal ou se há carreamento de finos, que pode sinalizar risco de erosão interna.

M2. A inspeção de rotina é periódica e ordinária; a especial ocorre após eventos incomuns; a emergencial é motivada por risco imediato ou progressivo.

M3. Água turva pode indicar arraste de partículas finas, o que sugere possível erosão interna, piping ou degradação de filtros e drenagem.

M4. Resposta possível: identificação da barragem, registros de projeto, histórico de inspeções, critérios de operação, lista de anomalias, ações corretivas e procedimentos de emergência.

Gabarito comentado — nível D

D1. O conjunto é compatível com uma condição de atenção elevada. Vazão crescente, surgência e turbidez podem indicar percolação concentrada e possível carreamento de finos. As providências iniciais incluem registro imediato, inspeção técnica detalhada, comparação com leituras anteriores, avaliação da evolução do fenômeno e adoção de medidas operacionais compatíveis com o risco.

D2. Porque a informação só é útil quando interpretada e convertida em ação. Se a equipe não observa a instrumentação nem inspeciona a obra, sinais precoces de anomalia podem ser perdidos, reduzindo a chance de intervenção antes de uma falha grave.

D3. Quanto maior o dano potencial a jusante, maior a necessidade de monitoramento rigoroso e resposta rápida. A presença de comunidades, infraestrutura e usos sensíveis amplia a consequência de uma possível falha, tornando intolerável a demora na tomada de decisão diante de anomalias.

Conexão com o próximo capítulo

Depois de construir a barragem de terra e estabelecer os instrumentos de observação, o passo seguinte é operar o açude com disciplina técnica. No próximo capítulo, serão abordadas a operação e a manutenção, incluindo controle de níveis, rotina de inspeção, manejo de sedimentos, conservação das estruturas e decisões necessárias ao longo da vida útil do reservatório.

Parte IV

Operação e convivência

Capítulo 7

Operação e manutenção de açudes

Objetivos de aprendizagem

Ao final deste capítulo, espera-se que o leitor seja capaz de:

- compreender a diferença entre projetar, construir, operar e manter um açude;
- reconhecer a operação como processo contínuo de controle do nível, das descargas e dos usos da água;
- identificar rotinas de manutenção preventiva e corretiva aplicáveis a pequenos e médios açudes;
- relacionar assoreamento, evaporação, qualidade da água e vida útil do reservatório;
- interpretar a operação em situação de estiagem, cheia e uso múltiplo;
- valorizar a gestão do reservatório como parte integrante da segurança e da eficiência hídrica.

A construção de um açude não encerra o trabalho técnico; ela apenas inaugura uma nova fase, mais longa e, em muitos casos, mais decisiva para o sucesso do empreendimento. Um reservatório pode ter sido muito bem concebido e executado, mas se for operado sem critério e mantido sem rotina, sua capacidade de armazenamento, sua segurança e sua utilidade social podem se deteriorar rapidamente.

No semiárido, a operação e a manutenção têm peso ainda maior. As chuvas são concentradas, as secas são prolongadas, a evaporação é intensa e o reservatório costuma ser submetido a pressões de uso múltiplo. Assim, o açude deve ser compreendido como uma infraestrutura viva: ele precisa ser lido, acompanhado, limpo, protegido e ajustado ao longo do tempo.

Figura 7.1 – Ciclo simplificado de operação e manutenção de um açude ao longo da vida útil.

7.1 Operar um açude é tomar decisões continuamente

A operação consiste em controlar o reservatório de modo que ele cumpra sua função com segurança e eficiência. Isso inclui decisões sobre nível de armazenamento, descarga de água, resposta a eventos de chuva, prioridade de usos e proteção da estrutura.

Operação de açude

Operação é o conjunto de decisões e ações voltadas ao controle cotidiano ou sazonal do reservatório, visando compatibilizar armazenamento, segurança hidráulica, qualidade da água e atendimento aos usos previstos.

A operação não se resume a abrir ou fechar um dispositivo. Ela envolve leitura do nível d'água, avaliação da tendência do reservatório, acompanhamento da chuva, observação da demanda e verificação das condições da barragem e de seus componentes.

7.1.1 Funções centrais da operação

Em termos práticos, a operação busca:

- manter o nível do reservatório dentro da faixa segura;
- garantir o atendimento aos usos prioritários;
- preservar a integridade da barragem e do vertedor;
- reduzir perdas desnecessárias de água;
- evitar deterioração da qualidade da água;
- responder adequadamente a eventos extremos.

Reservatório cheio não é sempre reservatório bem operado

Um açude muito alto por longos períodos pode aumentar o risco hidráulico, a evaporação e a sobrecarga de usos. Por outro lado, um reservatório excessivamente baixo pode não cumprir sua função social. Operar bem é manter o equilíbrio entre segurança, reserva e aproveitamento.

7.2 Controle de níveis e regras operacionais

O nível do açude deve ser acompanhado por instrumentos simples e por observação técnica. A régua linimétrica, os marcos de cota e o registro das cheias permitem relacionar a condição atual do reservatório à curva cota-volume-área e aos limites de segurança do projeto.

7.2.1 Faixas de operação

É útil imaginar o reservatório em faixas:

- **faixa de volume morto ou mínimo operacional**: abaixo da qual o uso regular se torna difícil ou inviável;
- **faixa útil**: volume efetivamente disponível para os usos previstos;
- **faixa de atenção**: próximo aos níveis superiores, quando a operação precisa ser mais cautelosa;
- **faixa de segurança hidráulica**: limite superior compatível com a folga livre e com o vertedor.

O nível da água é uma informação de projeto e de rotina

A leitura do nível não serve apenas para saber se o açude está "cheio" ou "vazio". Ela orienta o uso da água, a resposta a eventos de chuva, a ativação de medidas de segurança e a previsão de disponibilidade futura.

7.2.2 A lógica da descida e da recomposição

Em regiões semiáridas, o reservatório tende a passar por ciclos:

1. enchimento após chuvas;
2. uso e perdas progressivas;
3. permanência em nível intermediário ou baixo;
4. nova recomposição em estação chuvosa.

A operação deve acompanhar esses ciclos com prudência. Se houver previsão de evento intenso, pode ser conveniente manter folga adicional. Se a estiagem se prolonga, a liberação de água deve ser priorizada conforme a necessidade social e a função estratégica do açude.

7.3 Balanço hídrico simplificado do reservatório

A operação depende de entender, mesmo que de forma simplificada, o que entra e o que sai do reservatório ao longo do tempo. O balanço hídrico ajuda a interpretar essa dinâmica.

$$\Delta S = V_{\text{entrada}} - V_{\text{saída}} - V_{\text{evap}} - V_{\text{infil}} - V_{\text{uso}}$$

em que:

- ΔS é a variação de armazenamento;
- V_{entrada} representa o volume afluente;
- $V_{\text{saída}}$ representa a descarga controlada ou vertida;
- V_{evap} representa as perdas por evaporação;

- V_{infil} representa as perdas por infiltração;
- V_{uso} representa a retirada para consumo ou outros usos.

A equação é simples, mas a leitura é estratégica

Mesmo em forma conceitual, o balanço hídrico mostra que o reservatório não depende apenas da chuva. Evaporação, infiltração e retirada de água podem consumir parcela importante do volume acumulado, especialmente no semiárido.

7.3.1 Evaporação

A evaporação é um dos principais fatores de perda em açudes do semiárido. Ela depende de:

- temperatura do ar;
- vento;
- umidade relativa;
- área exposta do espelho d'água;
- tempo de permanência da água na superfície.

Reservatórios muito rasos e muito abertos podem perder uma fração expressiva do volume armazenado. Por isso, a geometria do açude, a profundidade útil e a redução de área superficial são temas relevantes não só no projeto, mas também na operação.

7.3.2 Infiltração e percolação

Parte da água pode infiltrar-se para o subsolo ou percolar através da fundação e do maciço em quantidades compatíveis com o projeto. Se a perda se intensifica ou se torna turva, a operação deve passar a tratar o fenômeno como potencial anomalia.

Diferença entre perda esperada e problema

Toda barragem admite perdas controladas de água. O que não se admite é uma evolução sem explicação: aumento súbito de vazão, surgência turva, pontos úmidos novos ou alteração de comportamento após enchimento. Nesses casos, a operação deve acionar a inspeção e a manutenção.

7.4 Usos múltiplos e prioridade de atendimento

O açude, no contexto do saneamento ambiental, raramente existe para um único uso. A operação precisa conciliar interesses distintos e, muitas vezes, concorrentes.

7.4.1 Principais usos

Em geral, os usos podem incluir:

- abastecimento humano, direto ou tratado;
- dessedentação animal;
- irrigação complementar em pequena escala;
- lazer e uso comunitário compatível;
- reserva estratégica para estiagem prolongada;
- apoio a pequenos usos produtivos locais.

7.4.2 Critérios de prioridade

Quando a água é limitada, a operação precisa estabelecer prioridades. Em um contexto de escassez, é comum adotar a seguinte lógica geral:

1. atendimento humano;
2. dessedentação animal;
3. usos essenciais comunitários;
4. usos produtivos compatíveis com a disponibilidade restante.

Essa ordem pode variar conforme o contexto institucional e social, mas o princípio permanece: a operação deve ser transparente, justificável e compatível com a função social do reservatório.

Uso múltiplo exige governança

Quando vários usuários dependem do mesmo açude, a regra de operação não pode ser improvisada. Ela precisa ser compreensível, comunicada e seguida com consistência. Sem governança, o uso múltiplo tende a converter-se em conflito múltiplo.

7.5 Manutenção: preservar a função ao longo do tempo

A manutenção é o conjunto de ações destinadas a conservar ou recuperar a condição funcional da barragem, do reservatório e de seus dispositivos. Ela pode ser preventiva, corretiva ou emergencial.

Manutenção preventiva

Manutenção preventiva é a intervenção planejada antes que surja uma falha, com o objetivo de conservar o desempenho e reduzir a probabilidade de deterioração.

Manutenção corretiva

Manutenção corretiva é a intervenção realizada após o aparecimento de defeitos, visando restaurar a funcionalidade ou conter o avanço da degradação.

7.5.1 Manutenção preventiva típica

Entre as ações preventivas mais comuns estão:

- roçada e controle de vegetação;
- limpeza do vertedor, canais e obras de descarga;
- remoção de entulho e obstruções;
- reparo de erosões superficiais;
- verificação de trincas e recalques;
- inspeção de drenos e caixas de medição;
- controle de acesso de animais e pessoas em áreas sensíveis.

Vegetação não é sempre benéfica

Vegetação baixa e controlada pode ajudar na proteção superficial; vegetação excessiva, raízes profundas e árvores sobre o maciço podem dificultar inspeção, gerar caminhos de infiltração e aumentar a vulnerabilidade da barragem.

7.5.2 Manutenção corretiva típica

Quando o defeito já existe, as medidas podem incluir:

- recomposição de taludes erodidos;
- selagem de trincas e fissuras;
- limpeza de drenos e caixas;
- recuperação de proteção superficial;
- reparo de dispositivos de descarga;
- controle de ravinas e sulcos;
- regularização do coroamento.

7.5.3 Manutenção emergencial

A manutenção emergencial é acionada diante de risco iminente ou de evolução acelerada de anomalia. Nesses casos, a prioridade não é estética, mas segurança. Pode ser necessário:

- reduzir o nível do reservatório;
- isolar áreas de risco;
- impedir acesso de pessoas e animais;
- reforçar drenagem e proteção;

- acionar equipe técnica especializada.

7.6 Sedimentação e assoreamento

Com o tempo, os sedimentos transportados pela bacia tendem a se depositar no reservatório. Esse processo reduz o volume útil e altera a geometria de armazenamento.

7.6.1 Como o assoreamento afeta o açude

O assoreamento pode:

- reduzir a capacidade de armazenamento;
- elevar o fundo do reservatório;
- diminuir a profundidade útil;
- aumentar a área exposta à evaporação;
- comprometer a qualidade da água;
- afetar a tomada d'água e a operação do vertedor.

Vida útil depende da bacia

A vida útil de um açude não depende apenas da barragem. Ela depende também do manejo da bacia hidrográfica. Se o solo a montante estiver degradado, o reservatório pode perder capacidade muito antes do esperado.

7.6.2 Medidas de controle do assoreamento

A gestão do assoreamento envolve duas frentes:

- **na bacia**: conservação do solo, controle de erosão, recomposição vegetal e manejo adequado do uso do terreno;
- **no reservatório**: monitoramento do depósito de sedimentos, limpeza seletiva quando viável e adequação dos dispositivos de tomada d'água.

Estratégia de prevenção

Uma pequena barragem pode ter vida útil muito maior quando combinada com práticas conservacionistas na bacia, como terraceamento, manutenção de cobertura vegetal e controle de enxurradas. A obra hidráulica e o território a montante formam um sistema único.

7.7 Qualidade da água e operação

A qualidade da água é um tema central quando o açude atende usos múltiplos. A operação e a manutenção influenciam diretamente essa qualidade.

7.7.1 Fatores que afetam a qualidade

Entre os fatores mais comuns estão:

- entrada de sólidos em suspensão;
- decomposição de matéria orgânica;
- proliferação de algas em períodos de calor;
- estratificação térmica em reservatórios mais profundos;
- contaminação por uso inadequado da margem;
- presença de animais e resíduos.

7.7.2 Boas práticas operacionais

Para preservar a qualidade da água, convém:

- evitar lançamentos de resíduos na área do reservatório;
- proteger margens sensíveis;
- controlar acesso de animais a pontos críticos;
- remover vegetação e matéria orgânica acumuladas em áreas de uso;
- monitorar turbidez e odor em situações suspeitas;
- organizar regras de uso comunitário compatíveis com a finalidade do açude.

Qualidade da água também é conservação da obra

Água mal preservada agrava problemas operacionais e aumenta a necessidade de intervenções futuras. Em saneamento ambiental, operação e qualidade da água não são assuntos paralelos; são dimensões do mesmo sistema.

7.8 Operação em estiagem e em eventos de cheia

A operação do açude varia conforme o regime climático.

7.8.1 Durante a estiagem

Em estiagem prolongada, a operação deve:

- priorizar usos essenciais;
- evitar retiradas excessivas;
- monitorar a redução do nível;
- observar a qualidade da água;

- planejar alternativas complementares de abastecimento;
- preparar a comunidade para restrições eventuais.

7.8.2 Durante chuvas e enchentes

Em eventos de chuva, a atenção se concentra em:

- subida rápida do nível;
- comportamento do vertedor;
- limpeza de obstruções;
- estabilidade de taludes e do coroamento;
- ausência de erosão no canal de descarga;
- leitura de instrumentos e comparação com valores anteriores.

Chuva forte exige vigilância, não improviso

Quando ocorre uma cheia relevante, a operação precisa ser prudente e baseada em critérios previamente estabelecidos. A tentação de "fazer algo na hora" sem protocolo pode agravar o risco em vez de reduzi-lo.

7.9 Rotina de manutenção recomendada

A manutenção pode ser organizada por periodicidade.

Tabela 7.1 – Exemplo de rotina de manutenção em açudes

Periodicidade	Ação principal	Finalidade
Semanal ou quinzenal	Inspeção visual básica, limpeza de obstruções e verificação de nível	**Detectar problemas precoces**
Mensal	Roçada, verificação de drenagem, revisão de acessos e dispositivos	**Conservar funcionalidade e inspeção**
Após chuvas intensas	Inspeção especial de erosões, recalques, trincas e vertedor	**Verificar resposta a evento extremo**
Anual	Avaliação mais ampla da estrutura, sedimentos e operação	**Planejar correções e melhorias**

A periodicidade ideal depende do porte da obra, do uso do reservatório e do contexto local, mas a ideia central é clara: manutenção eventual não substitui rotina.

7.10 Resumo do capítulo

Resumo do capítulo

- Operar um açude é controlar níveis, descargas, usos da água e resposta a eventos climáticos.
- A operação deve apoiar-se na leitura do nível do reservatório, no balanço hídrico e na observação do comportamento da obra.
- Em reservatórios do semiárido, evaporação, infiltração, retirada de água e assoreamento influenciam fortemente a disponibilidade.
- O uso múltiplo exige regras de prioridade, transparência e governança.
- A manutenção preventiva conserva a estrutura; a corretiva recupera danos; a emergencial responde a riscos imediatos.
- Vegetação, erosão, obstruções, trincas e drenagem precária são pontos clássicos de atenção.
- O assoreamento reduz a vida útil do açude e depende do manejo da bacia a montante.
- Qualidade da água, operação e conservação estrutural fazem parte do mesmo sistema de gestão.

7.11 Exercícios

Exercícios de fixação — nível F

F1. O que significa operar um açude?

F2. Qual é a diferença entre manutenção preventiva e corretiva?

F3. Cite dois efeitos do assoreamento sobre o reservatório.

F4. Por que a qualidade da água é importante na operação de um açude?

F5. O que deve ser priorizado durante uma estiagem prolongada?

Exercícios de aplicação — nível M

M1. Explique por que um reservatório muito cheio nem sempre está em melhor condição operacional.

M2. Descreva quatro ações típicas de manutenção preventiva em um açude.

M3. Relacione o assoreamento com a redução da vida útil do reservatório.

M4. Em um contexto de uso múltiplo, por que a operação precisa estabelecer prioridades?

Exercícios de integração — nível D

D1. Um açude rural apresenta queda acelerada do nível, aumento de turbidez e vegetação muito vigorosa em um ponto específico da margem. Como você interpretaria esse conjunto de sinais e que tipo de ação seria compatível com a situação?

D2. Em uma comunidade semiárida, o reservatório vem sendo utilizado sem regras claras entre consumo humano, dessedentação animal e irrigação de pequena escala. Analise as consequências operacionais e sociais dessa falta de organização.

D3. Proponha um conjunto mínimo de medidas para ampliar a vida útil de um açude cujo principal problema é o aporte de sedimentos da bacia.

7.12 Gabarito comentado

Gabarito comentado — nível F

F1. É controlar o reservatório ao longo do tempo, regulando níveis, descargas, usos e resposta aos eventos climáticos.

F2. A preventiva é planejada antes da falha; a corretiva é executada após o surgimento de defeitos para restaurar a funcionalidade.

F3. Redução da capacidade de armazenamento e aumento da área exposta à evaporação são dois efeitos típicos. Também pode haver elevação do fundo e prejuízo à captação.

F4. Porque a operação afeta diretamente o uso humano, a segurança sanitária, a presença de algas, a turbidez e a aceitação do recurso pela comunidade.

F5. Devem ser priorizados os usos essenciais, especialmente abastecimento humano e dessedentação animal, de acordo com a gestão local.

Gabarito comentado — nível M

M1. Porque nível elevado por si só não garante boa operação. Pode haver risco hidráulico maior, evaporação intensa, sobrecarga de taludes e pouca margem para receber novas cheias.

M2. Resposta possível: roçada e controle de vegetação; limpeza do vertedor; remoção de entulho; inspeção de trincas e erosões; verificação de drenos; conservação de acessos.

M3. O assoreamento ocupa volume útil, reduz profundidade e torna o reservatório mais exposto à evaporação e à degradação da qualidade da água, encurtando sua vida útil.

M4. Porque a disponibilidade hídrica é limitada e os usos podem competir entre si. Sem prioridade, o açude pode deixar de atender a função principal em momentos críticos.

Gabarito comentado — nível D

D1. O quadro sugere possível perda anormal de água, com sinais compatíveis com percolação concentrada e carreamento de finos. A vegetação vigorosa em ponto localizado pode indicar umidade persistente. A ação compatível inclui inspeção técnica imediata, medição de vazão de drenagem, comparação com leituras anteriores e avaliação de necessidade de medidas emergenciais.

D2. A falta de regras pode gerar conflitos, uso desordenado e redução da disponibilidade para fins prioritários. Operacionalmente, o reservatório pode ser explorado além do limite seguro; socialmente, podem surgir disputas, injustiças e perda de confiança na gestão do açude.

D3. Medidas esperadas: conservação do solo na bacia, recomposição vegetal, controle de erosão, proteção de margens, monitoramento de sedimentos, adequação da tomada d'água e, quando viável, retenção de sedimentos a montante. O essencial é atacar a causa na bacia, não apenas o efeito no reservatório.

Conexão com o próximo capítulo

Depois de compreender a operação e a manutenção do açude, o leitor está pronto para ampliar a visão para soluções complementares de convivência com a escassez hídrica. No próximo capítulo, serão abordadas as cisternas e as barragens subterrâneas, tecnologias fundamentais no semiárido para descentralizar o armazenamento e aumentar a resiliência hídrica de famílias e comunidades.

Capítulo 8

Convivência com o semiárido: cisternas e barragens subterrâneas

Objetivos de aprendizagem

Ao final deste capítulo, espera-se que o leitor seja capaz de:

- compreender por que a convivência com o semiárido exige soluções descentralizadas de armazenamento de água;
- distinguir o papel das cisternas, das barragens subterrâneas e dos açudes na segurança hídrica;
- reconhecer os componentes básicos de uma cisterna de captação de água de chuva;
- compreender o princípio de funcionamento de uma barragem subterrânea;
- identificar condições favoráveis e limitações de cada tecnologia;
- propor arranjos complementares entre infraestrutura centralizada e tecnologias sociais;
- valorizar a gestão comunitária, a qualidade da água e a manutenção como partes da solução.

Ao longo do livro, o açude foi tratado como infraestrutura fundamental para armazenamento de água em escala comunitária e territorial. Porém, no semiárido, ele não deve ser visto como solução única. A convivência com a escassez hídrica depende de um conjunto de estratégias articuladas, em diferentes escalas, que reduzam a vulnerabilidade das famílias e das comunidades diante da irregularidade das chuvas.

É nesse contexto que entram as cisternas e as barragens subterrâneas. Ambas são tecnologias de armazenamento e aproveitamento hídrico com forte vocação social, baixa complexidade relativa e grande valor para a resiliência local. Elas não substituem o açude em todas as funções, mas complementam sua atuação ao aproximar a água do ponto de uso, reduzir perdas e diversificar fontes.

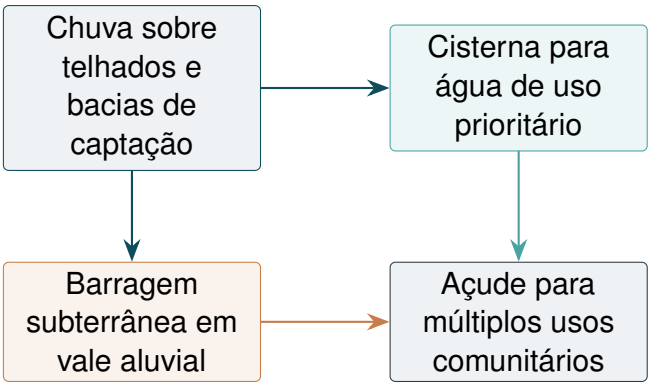

Figura 8.1 – Visão integrada: cisternas, barragens subterrâneas e açudes como partes complementares da convivência com o semiárido.

8.1 A lógica da convivência com o semiárido

Convivência com o semiárido não significa resignação diante da falta d'água. Significa organizar o território para trabalhar com a variabilidade climática, e não contra ela. Nessa perspectiva, o armazenamento de água precisa ser distribuído em várias escalas:

- escala da bacia e da comunidade, com os açudes;
- escala da família e da unidade produtiva, com as cisternas;
- escala do subsolo raso e dos vales aluviais, com as barragens subterrâneas.

Essa combinação reduz dependência de uma única fonte, melhora a segurança hídrica e amplia a capacidade de resposta durante secas prolongadas.

Tecnologias de convivência hídrica

Tecnologias de convivência hídrica são soluções técnicas, sociais e operacionais destinadas a captar, armazenar, proteger e utilizar água de forma compatível com a irregularidade climática e com as condições territoriais do semiárido.

Descentralizar é reduzir vulnerabilidade

Quando toda a disponibilidade hídrica depende de um único reservatório, a falha, a contaminação ou a escassez desse reservatório afeta toda a comunidade. Ao descentralizar o armazenamento, a resiliência aumenta e os riscos se distribuem.

8.2 Cisternas: armazenamento próximo do consumo

As cisternas são reservatórios destinados, em geral, à captação e ao armazenamento de água de chuva para uso doméstico, produtivo ou comunitário. Sua principal vantagem está em aproximar a água do local de uso, reduzindo perdas de transporte, simplificando o acesso e aumentando a autonomia das famílias.

8.2.1 Princípio de funcionamento

A água da chuva é coletada por uma área de captação, conduzida por calhas e tubulações e armazenada em um reservatório fechado ou semifechado. O sistema costuma incluir elementos de proteção da qualidade da água, como:

- tela ou grade de retenção de folhas e sólidos grossos;
- dispositivo de descarte da primeira água;
- tampa ou cobertura contra contaminação;
- retirada por torneira ou bomba simples;
- limpeza periódica das superfícies de captação.

8.2.2 Tipos mais comuns

Em contextos rurais semiáridos, podem aparecer diversas configurações:

- **cisterna de telhado**: recebe água de cobertura construída ou natural, com destinação prioritária para consumo humano;
- **cisterna de calçadão**: capta água de uma área pavimentada ou revestida, com maior potencial de coleta;
- **cisterna de enxurrada**: armazena água proveniente de escoamentos superficiais controlados;
- **cisterna para produção**: voltada a pequenos usos produtivos compatíveis com a disponibilidade local.

Uso e qualidade da água

A cisterna destinada ao consumo humano exige maior cuidado sanitário do que a cisterna voltada a usos produtivos. Misturar usos sem critério pode comprometer a qualidade da água e a confiança da comunidade no sistema.

8.2.3 Componentes básicos

Uma cisterna bem concebida costuma ter:

- área de captação;
- calhas e condutores;
- sistema de descarte da primeira água;
- reservatório principal;
- tampa ou cobertura;

- ponto de retirada da água;
- acesso para limpeza e manutenção.

Primeira água

Primeira água é o volume inicial de chuva coletado após um período seco, geralmente mais contaminado por poeira, fezes de animais, folhas e outras impurezas acumuladas na área de captação. Seu descarte melhora a qualidade da água armazenada.

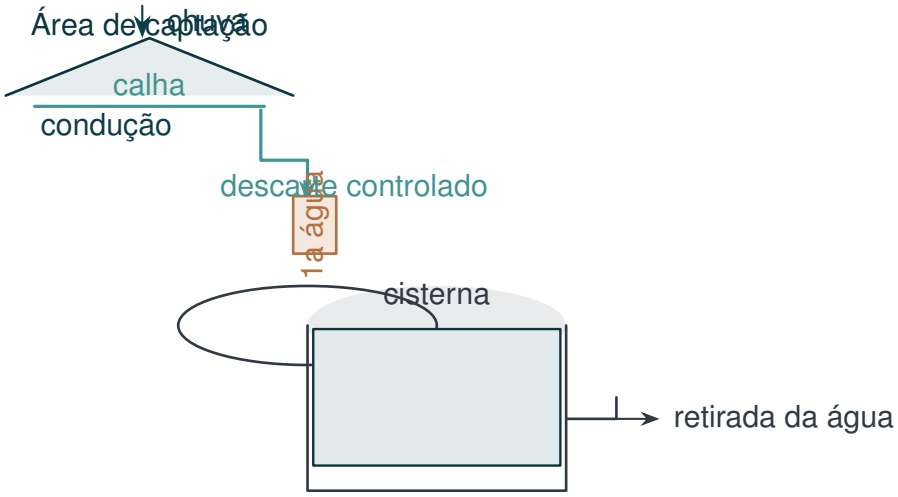

Figura 8.2 – Esquema simplificado de uma cisterna de captação de água de chuva com descarte da primeira água.

8.2.4 Aspectos de qualidade da água

A cisterna, principalmente quando associada ao consumo humano, exige disciplina sanitária. Os pontos críticos são:

- limpeza regular da cobertura e da calha;
- descarte da primeira água;
- vedação contra entrada de poeira, insetos e pequenos animais;
- retirada da água sem contato manual direto com o interior do reservatório;
- uso de água com tratamento compatível, quando aplicável.

Cisterna não é apenas recipiente

Uma cisterna adequada não depende apenas do volume do reservatório. O sistema de captação, a higiene da superfície, o descarte da primeira água e a forma de retirada influenciam decisivamente a qualidade final da água.

8.3 Barragens subterrâneas: água guardada no subsolo raso

As barragens subterrâneas são estruturas implantadas, em geral, em vales aluviais ou leitos de drenagem com material sedimentar permeável. Seu princípio é interromper ou reduzir o escoamento subsuperficial, permitindo que a água se acumule no solo e na zona de saturação a montante da parede impermeável.

8.3.1 Como funcionam

Em vez de formar um grande espelho d'água superficial, a barragem subterrânea cria uma retenção de umidade no subsolo. A água permanece armazenada nos poros do material aluvial, reduzindo perdas por evaporação direta e favorecendo o uso por poços rasos, cacimbas ou pequenos cultivos.

Barragem subterrânea

Barragem subterrânea é uma estrutura impermeável construída transversalmente a um vale aluvial ou leito permeável, com o objetivo de reter água no subsolo raso e elevar o nível freático a montante.

8.3.2 Condições favoráveis

Nem todo lugar é adequado para esse tipo de obra. Em geral, ela pede:

- vale aluvial com depósitos permeáveis;
- presença de fluxo subsuperficial sazonal;
- boa identificação da camada impermeável de fechamento;
- possibilidade de escavação e construção da parede;
- uso compatível com a disponibilidade armazenada;
- baixa salinização e controle da qualidade da água.

A geologia manda no desempenho

Se o vale não possui material aluvial adequado, se o terreno é excessivamente rochoso ou se não existe circulação subsuperficial significativa, a barragem subterrânea perde eficiência e pode se tornar uma solução mal adaptada.

8.3.3 Componentes usuais

Em um arranjo simplificado, a barragem subterrânea pode incluir:

- parede impermeável enterrada;
- área de recarga a montante;

- zona de armazenamento no subsolo;
- poço, cacimba ou estrutura de captação;
- dispositivos de controle e observação;
- proteção superficial para reduzir erosão e contaminação.

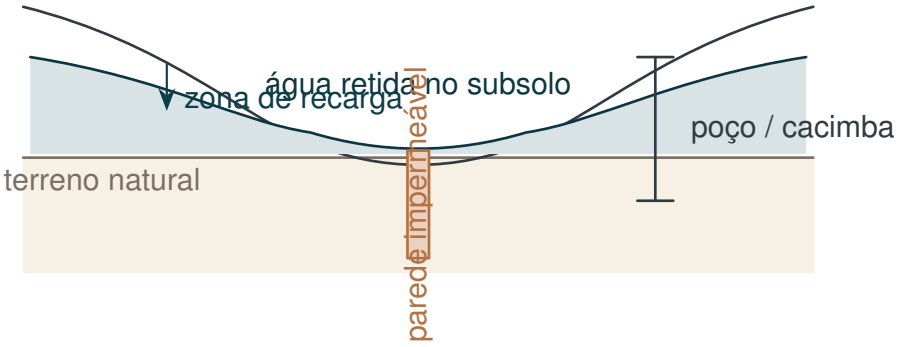

Figura 8.3 – Esquema simplificado de barragem subterrânea em vale aluvial.

8.3.4 Vantagens e limitações

As principais vantagens das barragens subterrâneas são:

- menor evaporação direta;
- aumento da umidade do subsolo raso;
- favorecimento de captação por poços rasos e usos próximos;
- menor exposição visual da água;
- adaptação a usos produtivos de pequena escala.

As limitações incluem:

- dependência forte da geologia local;
- dificuldade de visualização direta do volume armazenado;
- necessidade de controle da salinidade e da qualidade da água;
- risco de projeto inadequado se a leitura do vale for superficial;
- manutenção da parede impermeável e das estruturas de acesso.

8.4 Complementaridade com os açudes

As cisternas e as barragens subterrâneas não concorrem com os açudes; elas complementam o sistema hídrico. O açude continua sendo importante para armazenar maior volume, regular o uso múltiplo e atender demandas coletivas. As tecnologias descentralizadas,

Tabela 8.1 – Comparação entre cisternas, barragens subterrâneas e açudes

Critério	Cisternas	Barragens subterrâneas	Açudes
Escala de uso	Família / unidade produtiva / pequena comunidade	Pequena produção e uso local em vale aluvial	Comunidade, múltiplos usos e, em alguns casos, abastecimento regional
Fonte de água	Chuva captada em telhados ou áreas revestidas	Escoamento subsuperficial e umidade retida no alívio aluvial	Escoamento superficial de bacias hidrográficas
Perdas por evaporação	Muito baixas	Baixas	Moderadas a elevadas, dependendo da área do espelho d'água
Dependência da geologia	Baixa a moderada	Alta	Moderada a alta
Complexidade operacional	Baixa	Baixa a moderada	Moderada a alta
Uso típico da água	Consumo humano, higiene, pequenos usos produtivos	Pequenos cultivos, uso local e acesso por poços rasos	Usos múltiplos, reserva estratégica e gestão territorial

por sua vez, reduzem pressão sobre o reservatório principal e aproximam a água do uso cotidiano.

8.4.1 Como as soluções se combinam

Uma estratégia integrada pode funcionar assim:

- a cisterna atende a água de melhor qualidade, captada de telhados ou calçadões;
- a barragem subterrânea favorece pequenos usos produtivos e retenção de umidade em área local;
- o açude assegura maior volume para usos múltiplos, reserva de estiagem e gestão comunitária.

Essa combinação oferece maior robustez do que depender de uma única infraestrutura.

Diversificar fontes é uma estratégia de resiliência

Se uma fonte falha, as outras podem compensar parcialmente. A segurança hídrica no semiárido é mais forte quando a comunidade dispõe de uma carteira de soluções, e não de uma aposta única.

8.4.2 Aplicação por contexto

Em termos práticos:

- famílias isoladas tendem a se beneficiar fortemente de cisternas;
- pequenos vales aluviais podem ser vocacionados para barragens subterrâneas;
- comunidades maiores e usos múltiplos exigem açudes e gestão coletiva;
- territórios mais vulneráveis ganham ao combinar as três soluções.

8.5 Gestão comunitária e manutenção

Tecnologias de convivência hídrica exigem organização social. A qualidade da obra não depende apenas do desenho técnico, mas também da forma como a comunidade a usa e a conserva.

8.5.1 Pontos críticos de gestão

A gestão precisa cuidar de:

- limpeza das superfícies de captação;
- vedação e proteção contra contaminação;
- inspeção de calhas, tubos e dispositivos de descarte;
- controle de acesso de animais e resíduos;
- monitoramento da qualidade da água;
- manutenção da parede da barragem subterrânea e das estruturas de retirada;
- definição clara de responsabilidades de uso.

Manutenção simples, mas contínua

Tecnologias sociais costumam falhar quando são tratadas como obra pronta. O desempenho depende de pequenas ações contínuas, que precisam ser compreendidas e aceitas pela comunidade.

8.5.2 Educação e apropriação social

Em saneamento ambiental, a apropriação social é parte do funcionamento. A comunidade precisa saber:

- por que a primeira água deve ser descartada;
- por que a cisterna deve permanecer coberta;
- por que a barragem subterrânea depende do controle do vale;
- por que o açude requer regras de uso e vigilância.

Sem compreensão do sistema, as estruturas tendem a perder eficiência com o tempo.

8.6 Qualidade da água e riscos sanitários

A segurança hídrica não se resume à quantidade armazenada. Água armazenada precisa ter qualidade compatível com o uso.

8.6.1 Riscos mais comuns

Entre os principais riscos sanitários estão:

- contaminação por poeira e fezes de animais;
- presença de folhas, insetos e matéria orgânica;
- proliferação de algas em recipientes expostos;
- salinização em determinados contextos subterrâneos;
- manipulação inadequada na retirada da água;
- armazenamento sem proteção física.

8.6.2 Boas práticas sanitárias

Algumas medidas simples aumentam muito a segurança:

- limpeza periódica das áreas de coleta;
- descarte da primeira água;
- tampa e vedação adequadas;
- retirada da água sem contato direto com o interior do reservatório;
- proteção contra animais;
- monitoramento básico da água em caso de odor, turbidez ou alteração de cor.

Solução técnica com cuidado social

Uma cisterna bem construída pode falhar se a família não compreender que a água da calha precisa de limpeza e que o reservatório deve permanecer fechado. A tecnologia só é eficaz quando arquitetura, operação e educação caminham juntas.

8.7 Resumo do capítulo

Resumo do capítulo

- A convivência com o semiárido exige armazenamento descentralizado e complementação entre soluções.
- As cisternas aproximam a água do usuário e são especialmente adequadas para consumo humano e pequenos usos.
- Barragens subterrâneas retêm água no subsolo raso, reduzindo evaporação e favorecendo usos locais.
- O açude continua essencial para múltiplos usos e reserva territorial, mas não deve ser a única estratégia.
- Qualidade da água, manutenção e gestão comunitária são determinantes para o desempenho das tecnologias.
- A escolha da tecnologia depende de clima, geologia, uso pretendido, escala de demanda e capacidade de gestão.
- Diversificar fontes aumenta a resiliência hídrica e reduz vulnerabilidade a falhas.

8.8 Exercícios

Exercícios de fixação — nível F

F1. O que caracteriza uma tecnologia de convivência hídrica no semiárido?

F2. Qual é a função principal de uma cisterna?

F3. Como funciona, em termos gerais, uma barragem subterrânea?

F4. Por que as cisternas podem reduzir a pressão sobre os açudes?

F5. O que é a primeira água e por que ela deve ser descartada?

Exercícios de aplicação — nível M

M1. Compare cisterna de telhado e cisterna de calçadão quanto à captação e ao uso da água.

M2. Cite duas condições geológicas favoráveis à implantação de uma barragem subterrânea.

M3. Explique por que uma barragem subterrânea não é adequada em qualquer vale.

M4. Liste três medidas de manutenção para uma cisterna de consumo humano.

Exercícios de integração — nível D

D1. Uma comunidade semiárida possui um açude com forte evaporação, famílias dispersas e um vale aluvial favorável a retenção subterrânea. Proponha uma estratégia integrada de abastecimento que combine pelo menos duas das tecnologias estudadas neste capítulo, justificando tecnicamente a escolha.

D2. Explique por que a descentralização do armazenamento hídrico aumenta a resiliência do sistema local.

D3. Analise os riscos de higiene e operação que podem surgir se uma cisterna for usada sem descarte da primeira água, sem tampa e com retirada manual direta.

8.9 Gabarito comentado

Gabarito comentado — nível F

F1. É uma solução técnica e social compatível com a escassez e a irregularidade climática, buscando captar, armazenar e usar água de forma distribuída.

F2. Armazenar água de chuva próxima ao local de consumo, especialmente para usos domésticos e pequenos usos produtivos.

F3. Ela intercepta o fluxo subsuperficial em um vale aluvial, elevando a umidade do subsolo e permitindo o uso da água armazenada nos poros do terreno.

F4. Porque cada cisterna pode suprir parte das necessidades locais, diminuindo a dependência do reservatório maior para todos os usos.

F5. A primeira água é o volume inicial da chuva, mais sujeito a poeira, folhas e contaminantes. O descarte melhora a qualidade da água armazenada.

Gabarito comentado — nível M

M1. A cisterna de telhado capta uma área menor e costuma ser mais adequada à água de melhor qualidade para consumo humano; a de calçadão capta área maior e pode armazenar volumes mais expressivos, muitas vezes com vocação produtiva.

M2. Exemplo de resposta: vale aluvial com depósitos permeáveis e fluxo subsuperficial sazonal; presença de camada de fechamento eficiente; possibilidade de escavação e construção da parede impermeável.

M3. Porque ela depende de condições específicas de solo, circulação subsuperficial e geologia. Se o vale não tem material aluvial adequado ou se a hidráulica subterrânea é desfavorável, a retenção será pequena.

M4. Resposta possível: limpeza das calhas e da área de captação; inspeção da tampa e vedação; verificação do dispositivo de primeira água; limpeza periódica do reservatório; e proteção contra animais e contaminantes.

Gabarito comentado — nível D

D1. Uma solução coerente pode combinar cisternas para consumo humano e uma barragem subterrânea para uso produtivo local, reduzindo pressão sobre o açude. O açude pode permanecer como reserva comunitária para múltiplos usos e segurança hídrica geral. A justificativa técnica é a diversificação de fontes, a redução de evaporação e a proximidade da água ao uso.

D2. A descentralização reduz a vulnerabilidade a falhas de um único reservatório, distribui riscos, melhora a autonomia local e amplia a capacidade de resposta à seca. Se uma fonte tiver desempenho abaixo do esperado, outras podem sustentar parte da demanda.

D3. O uso sem descarte da primeira água, sem tampa e com retirada manual direta expõe o sistema a poeira, fezes de animais, insetos, matéria orgânica e manipulação contaminante. Isso reduz a qualidade da água, aumenta risco sanitário e pode tornar a cisterna inadequada para consumo humano.

Conexão com o próximo capítulo

Com a visão das soluções complementares para a convivência com o semiárido, o livro está pronto para a etapa final de síntese. No próximo capítulo, será desenvolvido um estudo de caso integrador, reunindo seleção do local, hidrologia, vertedor, construção, instrumentação, operação e a articulação entre açude, cisterna e barragem subterrânea em um único raciocínio de projeto.

Parte V

Integração aplicada

Capítulo 9

Estudo de caso integrador

Objetivos de aprendizagem

Ao final deste capítulo, espera-se que o leitor seja capaz de:

- integrar conceitos de escolha do local, hidrologia, hidráulica, construção, instrumentação, operação e convivência com o semiárido;
- interpretar um problema de projeto de açude como um sistema completo, e não como soma de partes isoladas;
- justificar a seleção de uma tipologia de barragem com base em condicionantes técnicas e territoriais;
- organizar uma solução preliminar coerente para reservatório, vertedor, dissipação, monitoramento e manutenção;
- reconhecer como soluções descentralizadas, como cisternas e barragens subterrâneas, complementam o açude;
- exercitar o raciocínio de síntese, típico da prática profissional em saneamento ambiental.

Este capítulo encerra a sequência principal do livro com uma proposta de integração. Não se trata de introduzir um novo assunto, mas de demonstrar como os temas anteriores se articulam em um projeto único. Em obras de armazenamento de água no semiárido, a qualidade do resultado depende menos de decisões isoladas e mais da coerência entre as decisões.

A seguir, será apresentado um estudo de caso didático, construído para reunir os conceitos centrais de todo o livro: seleção de local, tipologia da barragem, hidrologia da bacia, curva cota-volume-área, vertedor, dissipação de energia, construção de barragem de terra, instrumentação, segurança, operação, manutenção e convivência com o semiárido.

9.1 Estudo de caso didático

9.1.1 Contexto territorial

Considere a comunidade fictícia de **Riacho da Serra**, localizada em área semiárida, com ocupação rural dispersa e dependência direta de um curso d'água intermitente. A comu-

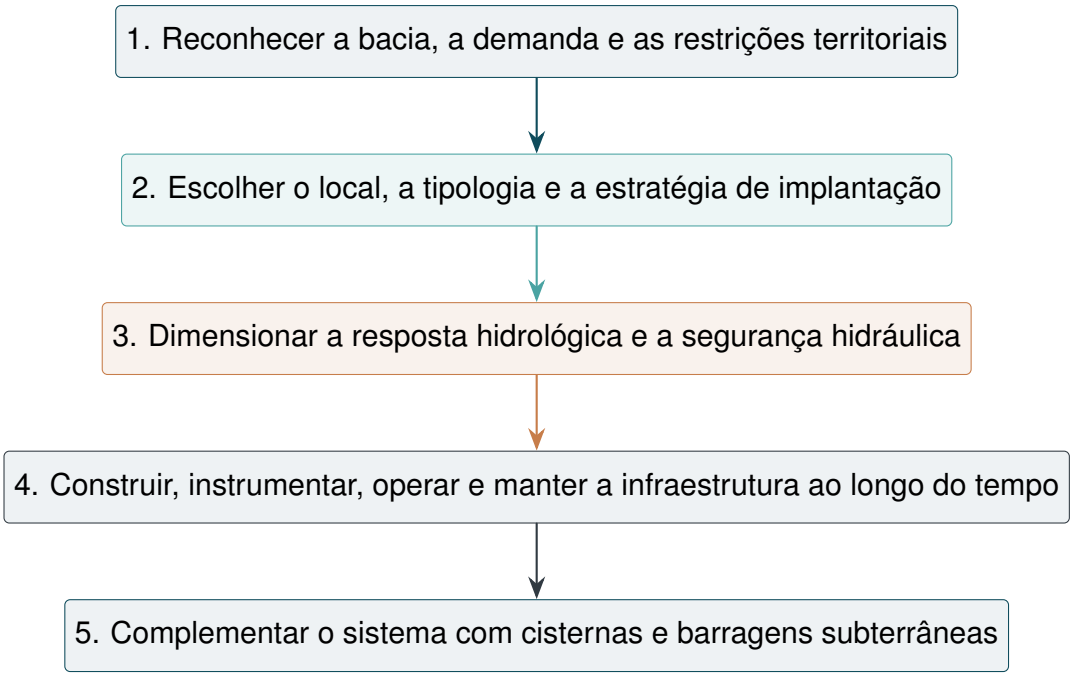

Figura 9.1 – Fluxo lógico de um projeto integrador de açude no semiárido.

nidade possui cerca de 1 200 habitantes, criação de animais de pequeno e médio porte e uma demanda sazonal de água para consumo humano, dessedentação animal e pequenas atividades produtivas compatíveis com a disponibilidade hídrica.

A população local solicita a implantação de um açude para aumentar a segurança hídrica e reduzir a vulnerabilidade durante os períodos secos. A equipe técnica, então, realiza uma análise preliminar do território.

9.1.2 Dados iniciais do problema

O caso é didático e simplificado

Os números apresentados neste capítulo servem para integrar os conceitos estudados no livro. Em um projeto real, seria necessário um levantamento hidrológico, topográfico, geotécnico e institucional mais detalhado.

9.2 Leitura integrada da situação

A análise preliminar aponta uma combinação de fatores favoráveis e restrições claras. O vale é suficientemente amplo para justificar uma barragem de terra, os solos argilosos estão próximos da obra e a demanda local pede uma solução economicamente viável e operacionalmente simples. Por outro lado, a fundação exige tratamento, a chuva é concentrada e a evaporação elevada impõe atenção ao desenho do reservatório.

Em termos de decisão, a leitura inicial sugere:

- barragem de terra zonada como solução principal;

Tabela 9.1 – Dados preliminares do caso didático

Item	Informação de partida
Área da bacia contribuinte	6 km^2
Precipitação média anual	620 mm
Coeficiente de escoamento preliminar	0,18
Intensidade de chuva para verificação preliminar	70 mm/h
Geometria do vale	Vale relativamente amplo, com garganta mais estreita a montante da seção escolhida
Fundação	Solo residual firme, com trecho aluvial e necessidade de tratamento local
Materiais disponíveis	Solo argiloso local em jazida próxima; rocha de melhor qualidade mais distante
Demanda principal	Consumo humano, dessedentação animal e reserva de estiagem
Condição climática	Alta evaporação, chuvas concentradas e longos intervalos secos

- vertedor independente, em canal revestido e posicionado fora do maciço;
- dissipação de energia a jusante com bacia protegida;
- instrumentação simples, porém eficaz;
- operação com prioridade para usos essenciais;
- complementação do sistema com cisternas e barragens subterrâneas.

O projeto precisa caber na bacia e na comunidade

O caso mostra que a melhor solução não é a que parece mais robusta isoladamente, mas a que se ajusta ao território, à economia local, à geologia, à hidrologia e à capacidade de manutenção da comunidade.

9.3 Estimativa hidrológica preliminar

Com base nos dados simplificados, pode-se estimar o volume anual potencial de escoamento superficial que chega à seção do açude. Usando a relação básica de balanço entre precipitação, coeficiente de escoamento e área da bacia, tem-se:

$$V_a = 0{,}62 \times 0{,}18 \times 6\,000\,000$$

Logo,

$$V_a \approx 669\,600\ \mathrm{m}^3$$

Esse valor representa um potencial anual teórico simplificado. Na prática, parte significativa desse volume será perdida por infiltração, evaporação, retenção na bacia e extravasamento em eventos de cheia. Ainda assim, o resultado indica que o reservatório pode ter relevância hídrica para a comunidade, desde que o projeto seja coerente com a escala local.

9.3.1 Cheia de projeto preliminar

Usando uma estimativa simplificada pelo método racional, com $C = 0{,}45$, $i = 70\ \mathrm{mm/h}$ e $A = 6\ \mathrm{km}^2$, obtém-se:

$$Q_p = 0{,}278 \times 0{,}45 \times 70 \times 6$$

Assim,

$$Q_p \approx 52{,}7\ \mathrm{m}^3/\mathrm{s}$$

Esse valor é apenas uma referência preliminar. Ele serve para mostrar a ordem de grandeza da vazão de verificação e para orientar a concepção do vertedor, da dissipação e da folga livre.

A cheia controla a segurança

Mesmo em obras pequenas, o comportamento da cheia define a confiabilidade do sistema. O vertedor deve ser pensado para conduzir a vazão de verificação sem colocar a barragem em risco de galgamento ou erosão.

9.4 Solução de projeto proposta

9.4.1 Tipologia principal

A solução mais coerente é uma **barragem de terra zonada**. A escolha se justifica por:

- disponibilidade de solo argiloso local;
- vale largo, mais favorável a aterro do que a estrutura rígida;
- custo e logística compatíveis com a realidade do semiárido;
- facilidade de manutenção e adaptação operacional;
- adequação ao porte comunitário do empreendimento.

A barragem deve incluir núcleo impermeável, zonas de transição, corpo principal compactado, filtros, dreno de pé e proteção dos taludes.

9.4.2 Vertedor e dissipação

Para o caso didático, adota-se um **vertedor lateral em canal revestido**, implantado em uma ombreira estável, de modo a evitar qualquer passagem sobre o aterro principal. A descarga a jusante deve conduzir a água até uma bacia de dissipação protegida por enrocamento ou estrutura equivalente.

Como referência preliminar, supondo um coeficiente de descarga simplificado C e uma carga hidráulica de 1,5 m, a largura útil estimada do vertedor pode ser calculada de forma conceitual por:

$$L \approx \frac{Q}{CH^{3/2}}$$

Tomando $Q \approx 52{,}7\,\mathrm{m^3/s}$, $C = 1{,}7$ e $H = 1{,}5\,\mathrm{m}$, obtém-se:

$$L \approx \frac{52{,}7}{1{,}7 \times 1{,}5^{3/2}} \approx 16{,}9\,\mathrm{m}$$

Em termos de projeto preliminar, isso sugere uma largura da ordem de 17 m, sempre sujeita à revisão por análise hidráulica mais detalhada.

Largura e carga não substituem projeto executivo

A conta acima é apenas uma aproximação didática. Em projeto real, a geometria do vertedor, as condições de aproximação, o tipo de soleira, as perdas locais e a dissipação precisam ser avaliados com maior rigor.

9.4.3 Níveis operacionais

Uma solução coerente para o caso prevê:

- **cota de operação normal**: nível de uso cotidiano;
- **cota máxima normal**: limite de funcionamento seguro;
- **folga livre**: margem entre a cota máxima normal e a crista da barragem;
- **coroamento**: com largura suficiente para inspeção e estabilidade.

Para o exemplo, pode-se admitir uma folga livre da ordem de 1,0 m, sempre com ajuste posterior em função do estudo hidráulico completo.

9.4.4 Instrumentação mínima

A proposta de instrumentação é enxuta, mas funcional:

- **dois piezômetros**: um próximo à região de montante e outro mais próximo da fundação ou zona de transição;
- **dois marcos superficiais**: para acompanhar recalques na crista;
- **uma régua linimétrica**: para leitura do nível do reservatório;
- **um ponto de medição de percolação**: na drenagem de pé ou caixa de inspeção;
- **registro fotográfico periódico**: para inspeção comparativa.

Instrumentar com inteligência

Em pequenas barragens, a eficiência não está no excesso de aparelhos, mas na escolha correta dos pontos de observação e na disciplina de leitura e registro.

9.5 Construção e controle tecnológico

A barragem de terra proposta deve ser executada preferencialmente em período seco, com a sequência correta de:

1. limpeza da fundação;
2. tratamento da base e das ombreiras;
3. execução da vala de vedação, se aplicável;
4. lançamento e compactação em camadas;
5. construção do núcleo impermeável e das transições;
6. implantação dos filtros e drenos;
7. proteção superficial dos taludes;
8. acabamento do coroamento;
9. ensaios e verificações de qualidade.

O controle tecnológico deve acompanhar umidade, massa específica seca, granulometria, espessura de camada e geometria final. Em um contexto semiárido, o maior risco é a perda de qualidade por interrupções climáticas e por variações na umidade dos materiais.

Obra e operação começam na mesma lógica

Uma obra bem executada facilita a operação futura. Uma obra mal executada transfere problemas para a fase de uso, quando a correção se torna mais cara, mais lenta e mais arriscada.

9.6 Operação e manutenção do caso

A operação do açude deve obedecer a uma lógica simples e transparente:

- prioridade para o abastecimento humano;
- segunda prioridade para dessedentação animal;
- uso produtivo somente quando compatível com a disponibilidade;
- inspeção reforçada após chuvas intensas;
- limpeza rotineira do vertedor e do canal de fuga;
- monitoramento do nível e da drenagem;
- controle do acesso de animais e resíduos.

A manutenção, por sua vez, deve ser organizada em rotina:

- semanal ou quinzenal: inspeção visual e limpeza básica;
- mensal: roçada, revisão do vertedor e verificação de drenagem;
- após chuvas intensas: inspeção especial de erosões, trincas e recalques;
- anual: revisão mais ampla da geometria, da sedimentação e dos registros.

A vida útil depende da bacia

Se a bacia for degradada, o açude perderá capacidade por assoreamento muito antes do esperado. A operação só é sustentável se houver cuidado também com o solo a montante.

9.7 Complementação com cisternas e barragens subterrâneas

A estratégia mais robusta para o caso é combinada. O açude atende à escala comunitária, mas a segurança hídrica melhora quando a comunidade também dispõe de cisternas domiciliares e de uma barragem subterrânea em vale favorável.

A proposta integrada pode ser resumida da seguinte forma:

- **açude principal**: armazenamento comunitário e usos múltiplos;
- **cisternas**: água de melhor qualidade para o nível domiciliar e para consumo prioritário;

- **barragem subterrânea**: umidade no subsolo e apoio a pequenos usos produtivos locais.

Não concentrar todo o risco em uma única obra

Uma única infraestrutura raramente resolve tudo. A resiliência aumenta quando o território possui soluções em camadas, com funções complementares e escalas diferentes.

9.8 Síntese final da solução

Tabela 9.2 – Síntese do estudo de caso e da solução adotada

Item	Decisão adotada
Local	Seção do vale com boa capacidade de armazenamento e fundação tratável
Tipologia da barragem	Barragem de terra zonada, com núcleo impermeável e filtros
Vertedor	Lateral, em canal revestido, independente do maciço principal
Dissipação	Bacia protegida a jusante com controle de energia e erosão
Instrumentação	Piezômetros, marcos superficiais, régua de nível e ponto de medição de percolação
Operação	Prioridade para usos essenciais, com regras claras e monitoramento contínuo
Manutenção	Rotina de inspeção, limpeza, roçada, revisão pós-cheias e controle do assoreamento
Complementação territorial	Cisternas e barragens subterrâneas para reduzir vulnerabilidade e ampliar a resiliência

9.9 Resumo do capítulo

Resumo do capítulo

- O estudo de caso integrador mostra que o projeto de um açude é um sistema, e não uma soma de partes desconectadas.
- A solução adotada para o caso foi uma barragem de terra zonada, compatível com o vale, os solos disponíveis e a escala da demanda.
- A hidrologia preliminar indicou potencial anual de escoamento suficiente para justificar o empreendimento, com cheia de verificação relevante para o vertedor.
- O vertedor lateral em canal revestido e a bacia de dissipação foram escolhidos para preservar a segurança do maciço de terra.

- A instrumentação mínima e a inspeção sistemática são essenciais para observar o comportamento da barragem ao longo do tempo.
- A operação deve priorizar usos essenciais, controlar níveis e responder a eventos de chuva e estiagem.
- A vida útil do açude depende também do manejo da bacia e do controle do assoreamento.
- Cisternas e barragens subterrâneas complementam o sistema e aumentam a resiliência hídrica do território.

9.10 Exercícios

Exercícios de fixação — nível F

F1. Qual é a principal função de um capítulo integrador em um livro técnico?

F2. Por que a barragem de terra zonada foi escolhida no caso didático?

F3. Qual o papel do vertedor lateral no estudo de caso?

F4. Por que a instrumentação simples, mas bem posicionada, pode ser suficiente em pequenas barragens?

F5. Como as cisternas e barragens subterrâneas complementam o açude?

Exercícios de aplicação — nível M

M1. A partir dos dados do caso, estime o volume anual potencial de escoamento superficial e interprete seu significado para a viabilidade do açude.

M2. Calcule, de forma preliminar, a vazão de pico pela expressão racional simplificada utilizada no capítulo e explique por que ela não deve ser tomada como valor final de projeto.

M3. Descreva, em cinco itens, a solução técnica integrada adotada no estudo de caso.

M4. Explique por que o controle do assoreamento não depende apenas da manutenção da barragem, mas também do manejo da bacia a montante.

Exercícios de integração — nível D

D1. Suponha que a comunidade do caso não disponha de cisternas domiciliares e dependa exclusivamente do açude principal. Discuta os riscos dessa dependência única e proponha uma alternativa mais resiliente.

D2. Se, durante a fase de operação, os piezômetros passarem a indicar aumento progressivo de pressão interna e a drenagem mostrar água levemente turva, como a gestão da barragem deveria reagir?

D3. Redija um parecer técnico curto, com linguagem profissional, justificando a escolha da barragem de terra zonada, do vertedor lateral revestido e da complementação por tecnologias descentralizadas para o caso apresentado.

9.11 Gabarito comentado

Gabarito comentado — nível F

F1. Integrar os conceitos estudados e mostrar como eles se articulam em um projeto real ou plausível.

F2. Porque há disponibilidade de solo local, o vale é amplo e a solução é compatível com a escala da demanda e com a realidade do semiárido.

F3. Conduzir a vazão excedente por um caminho seguro, sem permitir que a água passe sobre a barragem de terra.

F4. Porque, em pequenas barragens, poucos instrumentos bem posicionados já permitem observar tendências importantes, desde que as leituras sejam regulares.

F5. Elas distribuem o risco hídrico, aproximam a água do ponto de uso e reduzem a pressão sobre o açude principal.

Gabarito comentado — nível M

M1. O volume anual potencial estimado é de aproximadamente 669 600 m^3. Isso sugere que existe aporte hídrico relevante, suficiente para justificar um reservatório comunitário, desde que as perdas e a operação sejam adequadamente consideradas.

M2. A vazão de pico preliminar é de aproximadamente 52,7 m^3/s. O valor não é final porque depende de hipóteses simplificadas sobre chuva, coeficiente de escoamento e resposta da bacia, exigindo estudos mais detalhados antes do projeto executivo.

M3. Resposta esperada: barragem de terra zonada; vertedor lateral em canal revestido; bacia de dissipação protegida; instrumentação mínima com piezômetros, marcos e régua de nível; operação com prioridade para usos essenciais; complementação com cisternas e barragens subterrâneas.

M4. Porque o sedimento transportado para o reservatório depende das condições de erosão da bacia. Se o solo a montante estiver degradado, o açude perderá capacidade mesmo que a barragem esteja em bom estado.

Gabarito comentado — nível D

D1. A dependência exclusiva do açude aumenta a vulnerabilidade a falhas, secas prolongadas, perdas por evaporação e conflitos de uso. A alternativa mais resiliente é combinar o açude com cisternas domiciliares e, se o vale permitir, uma barragem subterrânea para usos locais.

D2. O quadro sugere necessidade de investigação imediata. A gestão deve registrar os dados, comparar com leituras anteriores, intensificar a inspeção visual, avaliar a percolação, verificar o dreno e, se necessário, adotar medidas operacionais e de segurança compatíveis com o risco.

D3. Espera-se um parecer que evidencie: adequação da barragem de terra ao vale e aos materiais locais; pertinência do vertedor lateral por segurança do maciço; necessidade de dissipação protegida; e vantagem da solução integrada com cisternas e barragens subterrâneas para reduzir vulnerabilidade e ampliar a resiliência hídrica.

Conexão com o próximo capítulo

Com este estudo de caso, encerra-se a parte principal do livro. A sequência lógica dos capítulos foi reunida em uma visão única de projeto, construção, operação e convivência com o semiárido. Nos apêndices, podem ser reunidos checklists, roteiros de inspeção e materiais de apoio para consulta rápida. Em seguida, serão apresentadas as referências finais organizadas manualmente.

Capítulo A

Checklist de projeto e seleção do local

A.1 Finalidade do checklist

Este apêndice reúne um roteiro prático para apoiar a fase de reconhecimento, triagem e seleção do local de um açude. A intenção é organizar a decisão antes do dimensionamento detalhado, reduzindo omissões e evitando que uma alternativa aparentemente boa seja levada adiante sem base técnica suficiente.

Checklist técnico

Checklist técnico é uma lista estruturada de verificação usada para confirmar, de modo sistemático, se os elementos essenciais de um estudo ou de uma obra foram observados antes da tomada de decisão.

A.2 Roteiro de reconhecimento inicial

A.3 Critérios que exigem atenção especial

- Fundação excessivamente permeável ou geologicamente heterogênea.
- Vale aparentemente favorável, mas com ombreiras instáveis.
- Distância elevada entre jazidas e obra, com transporte oneroso.
- Presença de ocupação humana ou usos sensíveis a jusante.
- Área de captação com forte tendência ao assoreamento.
- Alternativa com bom volume, mas espelho d'água muito grande para o contexto semiárido.

Critérios eliminatórios

Se um critério crítico for classificado como incompatível com o empreendimento e não houver tratamento tecnicamente razoável, a alternativa deve ser descartada ou profundamente reavaliada. Em obras hídricas, insistir em uma solução inadequada costuma gerar custos muito maiores no futuro.

A.4 Sequência mínima de decisão

1. Delimitar a bacia e entender a demanda.

Tabela A.1 – Checklist preliminar para seleção do local

Critério	Perguntas de verificação	**Situação**
Bacia hidrográfica	A área contribuinte é compatível com a demanda? O regime de chuvas justifica o empreendimento?	**Atende** / **Revisar** / **Não atende**
Topografia	O vale permite bom volume armazenado com comprimento razoável de barragem?	**Atende** / **Revisar** / **Não atende**
Geologia e geotecnia	A fundação é tratável? Há sinais de fraturas, solos muito permeáveis ou heterogeneidade crítica?	**Atende** / **Revisar** / **Não atende**
Materiais de construção	Há solo argiloso, rocha ou agregados em distância e quantidade compatíveis?	**Atende** / **Revisar** / **Não atende**
Ambiental	A intervenção é compatível com a vegetação, com o uso do solo e com as áreas a jusante?	**Atende** / **Revisar** / **Não atende**
Social	Existe aceitação comunitária? Há conflitos fundiários ou disputas de uso da água?	**Atende** / **Revisar** / **Não atende**
Construtibilidade	O acesso de máquinas, o canteiro e a logística são viáveis?	**Atende** / **Revisar** / **Não atende**

2. Comparar alternativas de implantação.
3. Verificar topografia, geologia, materiais e acessos.
4. Avaliar restrições ambientais e sociais.
5. Identificar possíveis pontos de conflito ou inviabilidade.
6. Escolher a alternativa mais coerente para o estudo detalhado.

Conexão com o próximo capítulo

O objetivo deste apêndice é apoiar a decisão inicial. Quando a seleção do local estiver consolidada, a próxima etapa é organizar a construção, o controle tecnológico e a rotina de inspeção da obra.

Capítulo B

Checklist de construção, inspeção e manutenção

B.1 Finalidade do checklist

Este apêndice reúne listas de verificação para a fase de obra e para a vida útil do açude. Em barragens de terra, a qualidade do resultado depende fortemente da execução. Por isso, a obra precisa ser acompanhada de maneira disciplinada, com registros objetivos e rotina de inspeção.

B.2 Antes do início da obra

- Confirmar eixo da barragem, cotas e locação topográfica.
- Verificar a limpeza e o preparo da fundação.
- Conferir a disponibilidade e a qualidade dos materiais de empréstimo.
- Definir a sequência de execução do núcleo, do corpo principal, dos filtros e dos drenos.
- Confirmar acesso de máquinas, canteiro e área de apoio.
- Estabelecer rotina de ensaios e controle tecnológico.
- Garantir que o vertedor e a dissipação estejam previstos em projeto antes da terraplenagem principal.

B.3 Durante a execução

- Controlar a umidade dos materiais antes da compactação.
- Respeitar a espessura de camada definida no projeto.
- Verificar o número de passadas dos equipamentos.
- Registrar a origem do material e o trecho executado.
- Evitar interrupções longas que gerem interfaces fracas entre camadas.
- Inspecionar o tratamento das ombreiras e da fundação.

- Manter proteção provisória contra chuva e erosão.
- Conferir cotas, taludes e geometria final do coroamento.

B.4 Após a conclusão da obra

- Registrar a geometria final do maciço.
- Testar a funcionalidade dos dispositivos de descarga e do vertedor.
- Verificar se há surgências, trincas ou recalques iniciais.
- Instalar e conferir a leitura dos instrumentos.
- Estabelecer rotina de inspeção e manutenção.
- Organizar a documentação técnica da barragem.

B.5 Inspeção de rotina

Tabela B.1 – Checklist simplificado de inspeção periódica

Item	O que verificar
Coroamento	Nível, regularidade, trincas, depressões e erosões
Taludes	Sulcos, ravinas, perda de proteção superficial e presença de umidade anormal
Ombreiras	Fissuras, pontos de infiltração, vegetação irregular e instabilidade local
Vertedor	Obstruções, erosão, integridade do revestimento e condições da chegada e saída da água
Drenagem de pé	Vazão, turbidez, presença de finos e comportamento ao longo do tempo
Reservatório	Nível d'água, assoreamento, qualidade da água e presença de resíduos
Acessos	Condições para inspeção, manutenção e resposta em emergências

Tabela B.2 – Rotina sugerida de manutenção e observação

Periodicidade	Ação recomendada	Finalidade
Semanal ou quinzenal	Inspeção visual básica e limpeza leve de obstruções	**Detectar anomalias precoces**
Mensal	Roçada controlada, verificação de drenagem e revisão do vertedor	**Conservar a funcionalidade**
Após chuvas intensas	Inspeção especial de erosões, trincas, recalques e surgências	**Avaliar resposta ao evento**
Anual	Revisão geral da barragem, do reservatório e dos registros	**Planejar correções e melhorias**

B.6 Periodicidade sugerida

Ação rápida diante de anomalia

Surgência turva, aumento repentino de vazão de drenagem, trinca progressiva ou erosão localizada devem ser tratados como sinais de atenção imediata. Em barragens, a demora na resposta costuma agravar o problema.

B.7 Conexão entre manutenção e segurança

A manutenção não é um complemento opcional. Ela é parte da segurança da barragem e da preservação da vida útil do reservatório. Em contexto semiárido, onde os eventos climáticos são intensos e espaçados, a capacidade de responder corretamente a cada período chuvoso é decisiva para a permanência da obra.

Conexão com o próximo capítulo

Após a construção e a manutenção, a última etapa de apoio ao estudo é reunir as relações matemáticas e os símbolos mais usados ao longo do livro, para consulta rápida e revisão.

Capítulo C

Fórmulas e relações úteis

C.1 Objetivo

Este apêndice reúne as principais expressões empregadas no livro, organizadas como apoio de revisão. As fórmulas foram apresentadas de forma didática ao longo dos capítulos e, aqui, aparecem em versão consolidada.

C.2 Símbolos mais usuais

Tabela C.1 – Símbolos e unidades de referência

Símbolo	Significado	**Unidade**
Q	Vazão	**m³/s**
A	Área	**m²**
V	Volume	**m³**
H	Carga hidráulica ou altura de água sobre a soleira	**m**
L	Largura útil de vertedor	**m**
i	Intensidade de chuva	**mm/h**
C	Coeficiente adimensional de escoamento ou descarga, conforme o contexto	**–**
γ_d	Massa específica seca do solo	**kN/m³**
GC	Grau de compactação	**%**

C.3 Relações hidrológicas e hidráulicas

C.3.1 Método racional

$$Q_p = 0{,}278\, C\, i\, A$$

Em que:

- Q_p é a vazão de pico em m³/s;
- C é o coeficiente de escoamento;

- i é a intensidade da chuva em mm/h;
- A é a área da bacia em km^2.

C.3.2 Vertedor de soleira livre

$$Q = C\,L\,H^{3/2}$$

A expressão mostra que, em nível conceitual, a capacidade de descarga cresce com a largura útil e com a carga hidráulica. O coeficiente depende da geometria e das condições de escoamento.

C.3.3 Curva cota-volume-área

$$A(h) = \frac{dV}{dh}$$

$$V(h) = \int_{h_0}^{h} A(\eta)\,d\eta$$

Essas relações ligam a topografia do reservatório ao volume armazenado.

C.3.4 Volume entre cotas sucessivas

$$V_i = V_{i-1} + \frac{A_{i-1} + A_i}{2}\,\Delta h$$

A expressão é útil para aproximações preliminares com cotas regularmente espaçadas.

C.3.5 Grau de compactação

$$GC = \frac{\gamma_{d,\text{campo}}}{\gamma_{d,\text{máx}}} \times 100$$

Esse indicador ajuda a verificar o desempenho da compactação em obra.

C.3.6 Balanço hídrico simplificado

$$\Delta S = V_{\text{entrada}} - V_{\text{saída}} - V_{\text{evap}} - V_{\text{infil}} - V_{\text{uso}}$$

A expressão resume a variação de armazenamento ao longo do tempo.

C.4 Leitura prática das fórmulas

Fórmula não substitui julgamento técnico

As expressões aqui reunidas são ferramentas de apoio. Elas orientam a análise, mas não substituem levantamento topográfico, estudo hidrológico, investigação geotécnica, verificação de campo e projeto executivo.

C.5 Resumo final do apêndice

- O método racional ajuda em estimativas preliminares de vazão.
- A relação $Q = C\,L\,H^{3/2}$ ajuda a interpretar a capacidade dos vertedores.
- A curva cota-volume-área é central para o entendimento do reservatório.
- A compactação precisa ser monitorada por indicadores objetivos.
- O balanço hídrico simplificado ajuda a compreender a dinâmica do armazenamento.

Conexão com o próximo capítulo

Com estes apêndices, o livro dispõe de apoio prático para seleção do local, construção, manutenção e revisão conceitual. A seguir, as referências foram organizadas manualmente, sem uso de arquivo `.bib`.

Referências Bibliográficas

[BRASIL, 2010] BRASIL. Lei n.º 12.334, de 20 de setembro de 2010. Estabelece a Política Nacional de Segurança de Barragens destinadas à acumulação de água para quaisquer usos, à disposição final ou temporária de rejeitos e à acumulação de resíduos industriais, e cria o Sistema Nacional de Informações sobre Segurança de Barragens. Brasília, 2010.

[CEARÁ, COGERH, 2009] CEARÁ. Companhia de Gestão dos Recursos Hídricos (COGERH). *Manual de Operação e Manutenção de Açudes*. Fortaleza: COGERH, 2009.

[CHAUDHRY, 2008] CHAUDHRY, M. H. *Open-Channel Hydraulics*. 2. ed. New York: Springer, 2008.

[DNOCS, 2011] DNOCS. Departamento Nacional de Obras Contra as Secas. *Manual de Pequenas Barragens*. Fortaleza: DNOCS, 2011.

[PONCE, 1994] PONCE, V. M. *Engineering Hydrology: Principles and Practices*. San Diego: San Diego State University, 1994.