MATERIAL DIDÁTICO

Curso de Saneamento Ambiental

HIDROLOGIA • PROJETO • GESTÃO

Planejamento, projeto e gestão de sistemas de drenagem pluvial urbana, controle de inundações e SBN

MATERIAL DIDÁTICO SANEAMENTO AMBIENTAL

Sistema de Drenagem Urbana

Planejamento, projeto e gestão de sistemas de drenagem pluvial urbana, controle de inundações e soluções baseadas na natureza (SBN)

HIDROLOGIA PROJETO GESTÃO SBN



Equipe do Curso de Saneamento Ambiental
Livro didático para graduação em Saneamento Ambiental

Projeto visual vetorial com foco em legibilidade, hierarquia e contraste

Sumário

1 Drenagem urbana: impermeabilização e ciclo hidrológico urbano 1
1.1 Objetivos de aprendizagem 1
1.2 Por que as cidades inundam? 2
1.3 O ciclo hidrológico em ambiente urbano 2
1.3.1 Componentes do ciclo e seus efeitos 3
1.3.2 Ambiente natural e ambiente urbano 4
1.4 Impermeabilização e resposta hidrológica da bacia 4
1.5 Alagamento, enxurrada e enchente: não são sinônimos 5
1.6 Exemplo comentado: aumento do escoamento com a urbanização 5
1.7 Resumo do capítulo 6
1.8 Exercícios 7
1.9 Gabarito comentado 8
1.10 Conexão com o próximo capítulo 9

2 Hidrologia de projeto e método racional 10
2.1 Objetivos de aprendizagem 10
2.2 Chuva de projeto, intensidade e período de retorno 11
2.2.1 Curvas intensidade-duração-frequência 11
2.3 Tempo de concentração 12
2.4 Coeficiente de escoamento 13
2.4.1 Valores indicativos 13
2.5 O método racional 13
2.5.1 Hipóteses do método racional 14
2.5.2 Comparação entre cenários 14
2.6 Exemplo completo de dimensionamento 15
2.6.1 Passo 1: coeficiente ponderado 15
2.6.2 Passo 2: escolha da chuva de projeto 16
2.6.3 Passo 3: cálculo da vazão de pico 16
2.6.4 Análise de sensibilidade 16
2.7 Erros frequentes em projetos 16
2.8 Resumo do capítulo 17
2.9 Exercícios 17

2.10 Gabarito comentado . . . 18
2.11 Conexão com o próximo capítulo . . . 20

3 Sarjetas, bocas-de-lobo e coletores de drenagem pluvial . . . 21
3.1 Objetivos de aprendizagem . . . 21
3.2 A microdrenagem como sistema . . . 22
3.3 Sarjetas: função, geometria e capacidade . . . 22
3.3.1 Parâmetros geométricos principais . . . 22
3.3.2 Critérios de projeto para sarjetas . . . 23
3.3.3 Estratégia prática de verificação . . . 23
3.4 Bocas-de-lobo: captação, tipologia e posicionamento . . . 24
3.4.1 Tipos mais usuais . . . 24
3.4.2 Critérios de localização . . . 25
3.4.3 Capacidade hidráulica da captação . . . 25
3.4.4 Confiabilidade e manutenção . . . 26
3.5 Coletores pluviais: transporte subterrâneo da vazão . . . 26
3.5.1 Elementos associados . . . 26
3.5.2 Critérios hidráulicos básicos . . . 27
3.5.3 Velocidade, sedimentação e autolimpeza . . . 27
3.5.4 O sentido de cálculo . . . 27
3.6 Procedimento prático de projeto . . . 28
3.7 Exemplo integrado de dimensionamento . . . 28
3.8 Erros frequentes em projetos . . . 30
3.9 Resumo do capítulo . . . 31
3.10 Exercícios . . . 31
3.11 Gabarito comentado . . . 32
3.12 Conexão com o próximo capítulo . . . 34

4 Bacias de detenção e retenção: dimensionamento . . . 35
4.1 Objetivos de aprendizagem . . . 35
4.2 Função das bacias no sistema de drenagem . . . 36
4.3 Detenção, retenção e infiltração: diferenças importantes . . . 36
4.4 Princípio de dimensionamento hidrológico . . . 36
4.4.1 Vazão admissível de saída . . . 37
4.5 Componentes físicos de uma bacia de controle . . . 38
4.5.1 Dispositivo de saída . . . 38
4.5.2 Segurança e operação . . . 39
4.5.3 Bacia de sedimentação preliminar . . . 40
4.6 Critérios de localização . . . 40
4.7 Procedimento de dimensionamento . . . 40

4.8 Exemplo completo de dimensionamento . . . 41
4.9 Erros frequentes em projetos . . . 43
4.10 Resumo do capítulo . . . 44
4.11 Exercícios . . . 44
4.12 Gabarito comentado . . . 45
4.13 Conexão com o próximo capítulo . . . 46

5 Técnicas de drenagem sustentável e Soluções Baseadas na Natureza (SBN) 47
5.1 Objetivos de aprendizagem . . . 47
5.2 Da lógica de transporte à lógica de controle na fonte . . . 48
5.3 Princípios de projeto das SBN . . . 48
5.4 Principais técnicas de drenagem sustentável . . . 49
5.4.1 Jardins de chuva . . . 50
5.4.2 Biovaletas . . . 50
5.4.3 Pavimentos permeáveis . . . 51
5.4.4 Telhados verdes . . . 51
5.4.5 Trincheiras de infiltração e canteiros pluviais . . . 51
5.4.6 Comparação entre técnicas . . . 52
5.5 Critérios de seleção do local . . . 52
5.6 Pré-dimensionamento hidrológico e hidráulico . . . 53
5.6.1 Jardim de chuva: área necessária . . . 54
5.6.2 Tempo de esvaziamento . . . 54
5.6.3 Biovaleta: verificação hidráulica . . . 54
5.6.4 Pavimento permeável: armazenamento em base granular . . . 55
5.6.5 Telhado verde: retenção simplificada . . . 55
5.7 Exemplo integrado de projeto em lote urbano . . . 56
5.8 Operação, manutenção e falhas comuns . . . 58
5.9 Erros frequentes em projetos . . . 58
5.10 Resumo do capítulo . . . 59
5.11 Exercícios . . . 59
5.12 Gabarito comentado . . . 60
5.13 Conexão com o próximo capítulo . . . 62

6 Plano Diretor de Drenagem Urbana, mapeamento de áreas de risco e alertas de inundação . . . 63
6.1 Objetivos de aprendizagem . . . 63
6.2 Por que a drenagem precisa de planejamento diretor . . . 64
6.3 Princípios orientadores de um PDDU . . . 64
6.4 Etapas de elaboração do PDDU . . . 65
6.4.1 1. Diagnóstico . . . 65

6.4.2 2. Prognóstico . . . 66
6.4.3 3. Alternativas . . . 66
6.4.4 4. Priorização . . . 67
6.4.5 5. Implementação . . . 67
6.4.6 6. Monitoramento e revisão . . . 67
6.5 Dados necessários para um bom plano . . . 67
6.5.1 Cadastro técnico e campo . . . 67
6.6 Mapeamento de áreas de risco . . . 69
6.6.1 Camadas cartográficas do risco . . . 69
6.6.2 Classificação simplificada de risco . . . 69
6.6.3 Exemplo de índice de triagem . . . 71
6.7 Sistema de alerta de inundação . . . 71
6.7.1 Componentes do sistema de alerta . . . 71
6.7.2 Níveis operacionais . . . 71
6.7.3 Comunicação de risco . . . 71
6.8 Medidas estruturais e não estruturais . . . 72
6.9 Hierarquização de intervenções . . . 73
6.10 Exemplo de estruturação de um PDDU simplificado . . . 73
6.11 Indicadores de desempenho e revisão . . . 74
6.12 Erros frequentes em planos de drenagem . . . 75
6.13 Resumo do capítulo . . . 75
6.14 Exercícios . . . 76
6.15 Gabarito comentado . . . 77
6.16 Conexão com o próximo capítulo . . . 79

7 Projeto integrador de uma microbacia urbana . . . 80
7.1 Objetivos de aprendizagem . . . 80
7.2 Caso-base da microbacia urbana . . . 81
7.3 Fluxo integrador do projeto . . . 81
7.4 Síntese técnica do diagnóstico . . . 81
7.5 Dimensionamento integrado . . . 82
7.5.1 Vazão de projeto da microbacia . . . 82
7.5.2 Trecho representativo da microdrenagem . . . 83
7.5.3 Reservação para amortecimento de pico . . . 83
7.5.4 Soluções Baseadas na Natureza . . . 84
7.6 Plano de implantação por fases . . . 84
7.7 Operação, manutenção e monitoramento . . . 84
7.8 Resultados técnicos consolidados . . . 86
7.9 Resumo do capítulo . . . 87

7.10 Exercícios . . . 87
7.11 Gabarito comentado . . . 88
7.12 Conexão com os apêndices . . . 89

A Fórmulas, unidades e relações de apoio . . . 91
A.1 Equações fundamentais . . . 91
A.1.1 Método racional . . . 91
A.1.2 Coeficiente médio ponderado . . . 91
A.1.3 Volume de escoamento superficial . . . 92
A.1.4 Equação da continuidade em reservação . . . 92
A.1.5 Manning . . . 92
A.1.6 Orifício . . . 93
A.1.7 Vertedor . . . 93
A.1.8 Tempo de esvaziamento em soluções de infiltração . . . 93
A.2 Conversões de unidade mais úteis . . . 94
A.3 Sequência de cálculo recomendada . . . 94
A.4 Faixas indicativas de coeficiente de escoamento . . . 94
A.5 Observações de uso . . . 94

B Checklist de inspeção e diagnóstico de campo . . . 96
B.1 Checklist geral da bacia . . . 96
B.2 Checklist da microdrenagem . . . 96
B.3 Checklist de reservação e controle de cheias . . . 97
B.4 Checklist de Soluções Baseadas na Natureza . . . 97
B.5 Checklist de risco e vulnerabilidade . . . 97
B.6 Modelo de ficha de vistoria . . . 98
B.7 Critérios de priorização em campo . . . 98
B.8 Uso do checklist . . . 98

C Modelo de memorial de cálculo e relatório técnico . . . 100
C.1 Estrutura mínima do documento . . . 100
C.2 Modelo de capa interna . . . 100
C.3 Roteiro de conteúdo técnico . . . 100
C.3.1 Caracterização da área . . . 100
C.3.2 Critérios hidrológicos . . . 101
C.3.3 Dimensionamento hidráulico . . . 101
C.3.4 Soluções complementares . . . 102
C.4 Modelo de conclusão . . . 102
C.5 Modelo de quadro-síntese . . . 102
C.6 Sugestão de organização visual . . . 102

D Glossário técnico essencial 104
D.1 Como usar este glossário 105
D.2 Encerramento dos apêndices 105

Referências Bibliográficas 107

Capítulo 1

Drenagem urbana: impermeabilização e ciclo hidrológico urbano

A drenagem urbana é um dos temas centrais do saneamento ambiental porque conecta ocupação do solo, hidrologia, infraestrutura e segurança da população. Quando a cidade cresce sem compatibilização entre uso do solo e capacidade de escoamento, o solo natural é substituído por telhados, pavimentos e superfícies compactadas. Essa transformação altera profundamente o caminho da água da chuva: reduz a infiltração, aumenta o escoamento superficial, encurta o tempo de resposta da bacia e eleva as vazões de pico. Em consequência, surgem alagamentos, enxurradas, assoreamento, erosão, danos materiais e riscos à saúde pública (Tucci, 2008; Botelho, 2011; Canholi, 2014).

Este capítulo estabelece a base conceitual do livro. Aqui o estudante vai compreender por que a drenagem urbana se torna crítica, como o ciclo hidrológico é modificado pelas cidades e quais são as diferenças entre alagamento, enxurrada e enchente. Essa base será indispensável para o dimensionamento de vazões no próximo capítulo e, depois, para o projeto de sarjetas, bocas-de-lobo, coletores, reservatórios e soluções baseadas na natureza.

Definição – Drenagem urbana

Conjunto de medidas estruturais e não estruturais destinadas a captar, transportar, retardar, armazenar, infiltrar e lançar de forma segura as águas pluviais em ambiente urbano, reduzindo danos humanos, ambientais e patrimoniais.

1.1 Objetivos de aprendizagem

Ao final deste capítulo, espera-se que o estudante seja capaz de:

- explicar como a urbanização altera o ciclo hidrológico natural;
- reconhecer os principais efeitos da impermeabilização sobre a geração de escoamento;
- diferenciar alagamento, enxurrada e enchente com base em sua causa e manifestação;
- interpretar os fatores que aumentam a vulnerabilidade a inundações urbanas;
- relacionar o diagnóstico hidrológico inicial com o dimensionamento que será desenvolvido no capítulo seguinte.

1.2 Por que as cidades inundam?

A inundação urbana não é um fenômeno simples nem resulta apenas de chuvas intensas. Em geral, ela aparece quando a capacidade de infiltração do solo, de armazenamento temporário da superfície e de condução da rede de drenagem é superada pela combinação entre precipitação, ocupação do terreno e deficiências de projeto, operação ou manutenção. Em outras palavras, o problema é sistêmico.

Os principais fatores que intensificam as inundações urbanas são:

- **Impermeabilização do solo:** telhados, calçadas, vias e estacionamentos reduzem drasticamente a infiltração;
- **Aumento da conectividade hidráulica:** a água escoa rapidamente de superfícies lisas para bocas-de-lobo, galerias e canais;
- **Ocupação de várzeas e fundos de vale:** áreas naturalmente destinadas à dissipação de cheias passam a receber usos vulneráveis;
- **Canalização e retificação de cursos d'água:** a redução da rugosidade e do tempo de percurso pode transferir o problema a jusante;
- **Obstrução de dispositivos:** lixo, sedimentos e manutenção insuficiente diminuem a capacidade real do sistema;
- **Falta de planejamento territorial:** o uso do solo cresce sem compatibilidade com a capacidade de drenagem existente.

Definição – Impermeabilização

Processo de substituição ou compactação da superfície natural do solo por materiais que reduzem a infiltração da água, como concreto, asfalto, pavimentos compactados, coberturas e superfícies seladas.

A literatura clássica mostra que, em drenagem urbana, o problema não está apenas no volume total de chuva, mas sobretudo na forma como a cidade transforma chuva em escoamento superficial rápido e concentrado (Tucci, 2008; Pompeo, 2000). Essa transformação eleva o pico de vazão, reduz o tempo de concentração da bacia e aumenta a frequência de ocorrência de transtornos mesmo em eventos que, em ambiente natural, seriam absorvidos sem grandes impactos.

1.3 O ciclo hidrológico em ambiente urbano

Em ambiente natural, parte da chuva infiltra-se no solo, parte evapora ou é interceptada pela vegetação e apenas uma fração se transforma em escoamento superficial. Em ambiente urbano, esse balanço é alterado de forma significativa. A drenagem urbana deve ser entendida, portanto, como a gestão do novo ciclo hidrológico imposto pela urbanização.

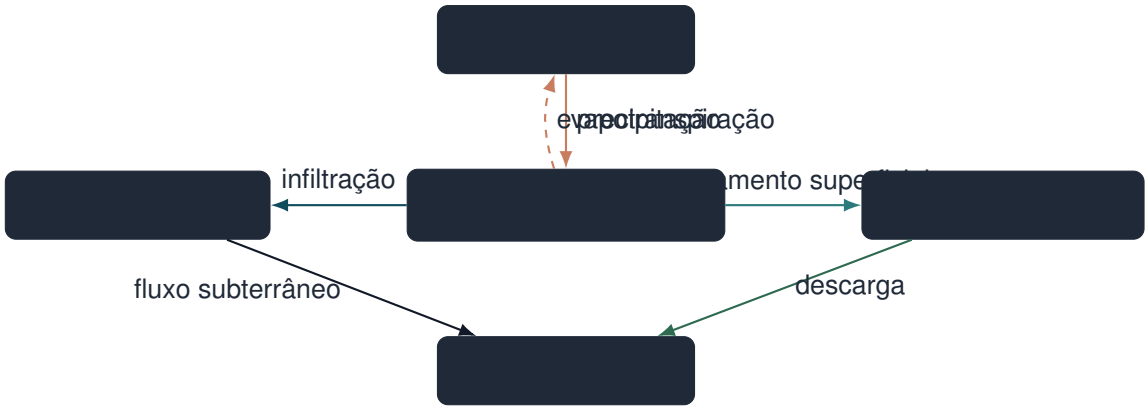

Figura 1.1: Esquema simplificado das principais rotas da água em ambiente urbano.

O balanço hídrico pode ser representado, de modo conceitual, por:

$$P = R + I + ET + \Delta S$$

em que P é a precipitação, R é o escoamento superficial, I é a infiltração, ET é a evapotranspiração e ΔS é a variação de armazenamento.

Em uma bacia urbanizada, parte importante da chuva que antes se infiltraria passa a compor o escoamento superficial. Isso altera não apenas a quantidade de água que chega aos canais e galerias, mas também a rapidez com que essa água chega. Por isso, uma cidade pode apresentar picos de cheia mais elevados mesmo sem aumento da chuva total anual.

1.3.1 Componentes do ciclo e seus efeitos

- **Precipitação:** é a entrada principal do sistema. Em drenagem urbana, interessam tanto a intensidade quanto a duração e a distribuição temporal da chuva;
- **Interceptação:** vegetação e superfícies interceptam parte da água, retardando sua chegada ao solo ou ao sistema de drenagem;
- **Infiltração:** é a entrada da água no solo. Em áreas impermeabilizadas, essa parcela diminui de forma expressiva;
- **Armazenamento superficial:** depressões, jardins, áreas verdes e solos naturais retêm temporariamente a água;
- **Escoamento superficial:** em áreas urbanas, torna-se mais rápido e concentrado, aumentando o risco de sobrecarga hidráulica;
- **Evapotranspiração:** em superfícies vegetadas, devolve parte da água à atmosfera; em áreas pavimentadas, esse processo é limitado.

1.3.2 Ambiente natural e ambiente urbano

A tabela a seguir resume as principais diferenças hidrológicas entre uma área natural e uma área urbanizada.

Tabela 1.1: Comparação entre o comportamento hidrológico em ambiente natural e urbano.

Componente	Ambiente natural	Ambiente urbano
Infiltração	Elevada, dependendo do tipo de solo e da cobertura vegetal	Reduzida pela impermeabilização e compactação
Escoamento superficial	Moderado e mais lento	Mais intenso e mais rápido
Armazenamento superficial	Maior, devido à vegetação e às depressões naturais	Menor, devido à pavimentação e à regularização do terreno
Tempo de resposta	Mais longo	Mais curto
Pico de vazão	Menor e mais distribuído no tempo	Maior e mais concentrado
Recarga subterrânea	Mais significativa	Reduzida

1.4 Impermeabilização e resposta hidrológica da bacia

A impermeabilização altera a resposta da bacia em quatro dimensões principais:

1. **Aumenta o volume de escoamento superficial.**

   Como a água encontra menos oportunidades para infiltrar e armazenar-se, maior fração da chuva segue diretamente para o sistema de drenagem.

2. **Eleva o pico de vazão.**

   O escoamento chega simultaneamente ao exutório, concentrando a descarga em pouco tempo.

3. **Reduz o tempo de concentração.**

   A água percorre caminhos mais curtos e mais rápidos sobre superfícies pavimentadas e redes artificiais.

4. **Diminui a recarga do aquífero e a sustentabilidade hídrica local.**

   Menor infiltração significa menor alimentação das águas subterrâneas e, em muitos casos, menor contribuição de base para córregos urbanos.

Outro efeito importante é a piora da qualidade da água pluvial. Em ambiente urbano, o escoamento arrasta sedimentos, óleos, lixo, metais, nutrientes e matéria orgânica acumulados nas superfícies. Assim, a drenagem não é apenas um problema de quantidade, mas também de qualidade da água e de proteção ambiental (Botelho, 2011; Canholi, 2014).

Definição – Coeficiente de impermeabilização

Razão entre a área impermeável e a área total de uma bacia. Uma forma simples de representá-lo é:

$$\phi = \frac{A_{\text{imp}}}{A_{\text{tot}}}$$

quanto maior o valor de ϕ, maior tende a ser a geração de escoamento superficial.

1.5 Alagamento, enxurrada e enchente: não são sinônimos

Na prática profissional, esses termos costumam ser usados como se fossem equivalentes, mas não são.

Tabela 1.2: Diferença conceitual entre alagamento, enxurrada e enchente.

Fenômeno	Causa principal	Característica essencial
Alagamento	Acúmulo de água por deficiência de drenagem local ou obstrução de dispositivos	A água permanece em vias, calçadas, pátios e baixadas sem necessariamente haver transbordamento de curso d'água
Enxurrada	Escoamento superficial concentrado e veloz após chuva intensa	A água se move com grande energia, podendo arrastar sedimentos e causar danos rápidos
Enchente	Elevação do nível de um rio, canal ou lago acima da condição normal	O curso d'água ocupa a planície adjacente; pode haver transbordamento

Essa distinção é essencial porque cada fenômeno exige uma resposta distinta. Alagamentos costumam demandar melhorias de microdrenagem, limpeza e reconfiguração de sarjetas, bocas-de-lobo e pontos baixos. Enxurradas exigem controle da velocidade do escoamento, redução da conectividade hidráulica e retenção na fonte. Enchentes, por sua vez, requerem ações de macrodrenagem, ordenamento territorial, recuperação de várzeas e gestão da bacia como um todo.

1.6 Exemplo comentado: aumento do escoamento com a urbanização

Considere uma microbacia de área total $A = 20\,\text{ha}$. Antes da urbanização, suponha uma superfície predominantemente permeável, com coeficiente médio de escoamento $C = 0{,}22$. Após a urbanização, a área passa a ter 12 ha de superfícies impermeáveis com coeficiente $C = 0{,}90$ e 8 ha de áreas permeáveis com coeficiente $C = 0{,}25$.

O coeficiente médio ponderado passa a ser:

$$C_{\text{m}} = \frac{12 \times 0.90 + 8 \times 0.25}{20} = 0{,}64$$

Agora considere uma chuva de 30 mm. Para estimar o volume escoado de forma simplificada, pode-se usar:

$$V = 10\,C\,P\,A$$

em que V é o volume em m^3, P é a altura de chuva em mm e A é a área em ha. O fator 10 resulta da conversão de unidades.

Situação antes da urbanização

$$V_1 = 10 \times 0.22 \times 30 \times 20 = 1320\,\text{m}^3$$

Situação após a urbanização

$$V_2 = 10 \times 0.64 \times 30 \times 20 = 3840\,\text{m}^3$$

A diferença é:

$$\Delta V = V_2 - V_1 = 2520\,\text{m}^3$$

Esse resultado mostra que a urbanização pode praticamente triplicar o volume de escoamento em um evento de mesma chuva. Na realidade, o problema costuma ser ainda mais grave, porque o aumento do volume vem acompanhado de maior velocidade de chegada da água, maior concentração do pico e menor oportunidade de amortecimento natural.

Este exemplo é propositalmente simples. No capítulo seguinte, a chuva de projeto, o tempo de concentração e o método racional permitirão transformar essa ideia qualitativa em dimensionamento hidráulico de engenharia.

1.7 Resumo do capítulo

Resumo do capítulo

A drenagem urbana deve ser tratada como um sistema integrado, e não como uma coleção isolada de galerias e sarjetas.

A urbanização altera o ciclo hidrológico ao reduzir infiltração, aumentar escoamento superficial, encurtar o tempo de resposta da bacia e elevar o pico de vazão.

Impermeabilização, ocupação de várzeas, canalização inadequada, manutenção deficiente e falta de planejamento territorial são causas frequentes de inundações urbanas.

Alagamento, enxurrada e enchente não são sinônimos; cada fenômeno tem causa e escala próprias.

O diagnóstico conceitual apresentado neste capítulo será a base para o dimensionamento hidrológico do próximo capítulo.

1.8 Exercícios

Exercício F1

Defina drenagem urbana e explique, em poucas linhas, qual é sua função principal em um bairro densamente urbanizado.

Exercício F2

Liste quatro alterações do ciclo hidrológico que ocorrem quando uma bacia natural é urbanizada.

Exercício F3

Explique a diferença entre alagamento, enxurrada e enchente.

Exercício M1

Em uma microbacia de 20 ha, 12 ha são impermeáveis com coeficiente de escoamento $C = 0{,}90$ e 8 ha são permeáveis com $C = 0{,}25$. Calcule o coeficiente médio ponderado da bacia.

Exercício M2

Usando a microbacia do exercício anterior e uma chuva uniforme de 30 mm, estime o volume de escoamento antes da urbanização, adotando $C = 0{,}22$, e após a urbanização, usando o coeficiente médio ponderado encontrado no exercício M1. Compare os resultados.

Exercício M3

Classifique os fenômenos a seguir como alagamento, enxurrada ou enchente, justificando a resposta:

- água acumulada em uma avenida após a obstrução de uma boca-de-lobo;
- fluxo rápido de água e lama descendo uma rua íngreme após chuva forte;
- transbordamento de um córrego que ocupa a via marginal e a planície adjacente.

Exercício D1

Uma região urbana passou por adensamento recente e a taxa de impermeabilização aumentou de 35 % para 70 %. Discuta pelo menos três consequências hidrológicas e proponha uma medida estrutural e uma medida não estrutural para mitigar os impactos.

Exercício D2

Elabore um diagnóstico preliminar de um bairro com alagamentos frequentes. Considere pelo menos os seguintes aspectos: uso do solo, pontos baixos, condição das bocas-de-lobo, presença de resíduos, ocupação de várzea e conectividade com o sistema de drenagem.

1.9 Gabarito comentado

Gabarito comentado

F1. Drenagem urbana é o conjunto de medidas para captar, transportar, retardar, armazenar e lançar com segurança a água da chuva em áreas urbanas. Sua função principal é reduzir danos causados por excesso de escoamento superficial, alagamentos e sobrecarga da infraestrutura.

F2. Entre as alterações mais importantes estão: redução da infiltração, aumento do escoamento superficial, diminuição do armazenamento superficial, encurtamento do tempo de resposta da bacia, redução da recarga subterrânea e aumento do pico de vazão. Quatro dessas respostas já caracterizam bem o processo.

F3. Alagamento é acúmulo de água por deficiência de drenagem local. Enxurrada é escoamento superficial rápido e concentrado, geralmente com grande energia. Enchente é a elevação do nível de um corpo d'água, com possível transbordamento para a planície adjacente. A causa e a escala espacial são diferentes em cada caso.

M1. O coeficiente médio ponderado é:

$$C_{\mathrm{m}} = \frac{12 \times 0.90 + 8 \times 0.25}{20} = 0{,}64$$

Logo, $C_{\mathrm{m}} = 0{,}64$ ou 64 %. O resultado mostra que a maior parte da chuva tende a converter-se em escoamento superficial.

M2. Antes da urbanização:

$$V_1 = 10 \times 0.22 \times 30 \times 20 = 1320\,\mathrm{m}^3$$

Após a urbanização:

$$V_2 = 10 \times 0.64 \times 30 \times 20 = 3840\,\mathrm{m}^3$$

A diferença é $\Delta V = 2520\,\mathrm{m}^3$. O volume escoado praticamente triplica, mesmo para a mesma chuva. Isso evidencia o efeito da impermeabilização sobre a geração de enxurradas e a sobrecarga da drenagem.

M3.

- água acumulada após obstrução de boca-de-lobo: **alagamento**;
- fluxo rápido de água e lama em rua íngreme: **enxurrada**;
- transbordamento de córrego e ocupação da planície adjacente: **enchente**.

A justificativa está na origem do fenômeno e na forma como a água se manifesta no espaço urbano.

D1. A impermeabilização maior tende a aumentar o volume de escoamento, elevar o pico de vazão, reduzir o tempo de concentração e diminuir a recarga subterrânea. Uma medida

estrutural pode ser a implantação de bacias de detenção ou dispositivos de retenção na fonte. Uma medida não estrutural pode ser o controle do uso do solo, a exigência de taxas máximas de impermeabilização e a manutenção periódica da microdrenagem.

D2. Um bom diagnóstico deve identificar onde a água se acumula, quais superfícies contribuem mais para o escoamento, se há obstruções por resíduos, se o bairro ocupa áreas naturalmente inundáveis e se a rede existente é compatível com a vazão gerada. Também é importante registrar a existência de ligações clandestinas, erosões, pontos de refluxo e falhas de manutenção. Esse levantamento orientará o dimensionamento e as prioridades de intervenção.

1.10 Conexão com o próximo capítulo

Conexão com o próximo capítulo

Este capítulo mostrou por que a urbanização altera o ciclo hidrológico e como a impermeabilização aumenta a geração de escoamento superficial. No próximo capítulo, esses conceitos serão transformados em cálculo de engenharia: chuva de projeto, intensidade, duração, período de retorno, tempo de concentração e vazão de pico. Essas ferramentas permitirão dimensionar, de forma objetiva, os elementos da drenagem urbana que conduzem e controlam a água pluvial.

Capítulo 2

Hidrologia de projeto e método racional

Se o capítulo anterior mostrou como a urbanização altera o ciclo hidrológico, este capítulo transforma o diagnóstico conceitual em ferramenta de engenharia. Aqui o objetivo é responder a uma pergunta central do projeto de drenagem: *qual vazão de pico deve ser considerada para dimensionar a infraestrutura pluvial?*

A resposta depende da chuva de projeto, do tempo de concentração, do grau de impermeabilização e do período de retorno adotado. Esses elementos são combinados, na prática, por meio do método racional, uma das abordagens mais utilizadas em drenagem urbana preliminar e em bacias pequenas, desde que suas hipóteses sejam respeitadas (Tucci, 2008; Botelho, 2011; Canholi, 2014).

Definição – Chuva de projeto

Evento pluviométrico representativo, escolhido para fins de dimensionamento, cuja intensidade, duração e frequência de ocorrência são compatíveis com o nível de risco admitido para uma obra ou sistema.

Definição – Período de retorno

Intervalo estatístico médio, em anos, associado à probabilidade anual de ocorrência ou superação de um evento de determinada magnitude.

Definição – Tempo de concentração

Tempo necessário para que a água precipitada no ponto hidráulico mais afastado da bacia alcance o exutório. Em projetos de drenagem, ele ajuda a definir a duração crítica da chuva.

2.1 Objetivos de aprendizagem

Ao final deste capítulo, o estudante deverá ser capaz de:

- interpretar o papel do período de retorno no dimensionamento de drenagem urbana;
- explicar a relação entre intensidade, duração e frequência da chuva;
- estimar o tempo de concentração de uma microbacia;
- aplicar corretamente o método racional e suas unidades;

- calcular o coeficiente de escoamento ponderado de uma bacia urbanizada;
- reconhecer as limitações do método racional e os erros mais comuns de aplicação.

2.2 Chuva de projeto, intensidade e período de retorno

A chuva que entra no projeto de drenagem não é a maior chuva já registrada nem a chuva mais intensa possível. Ela é uma chuva de referência, escolhida de modo compatível com a segurança esperada, o custo aceitável e as consequências da falha. Em drenagem urbana, essa escolha é expressa pelo período de retorno.

É importante enfatizar que o período de retorno não significa que o evento ocorrerá exatamente a cada T_r anos. Ele representa uma frequência média probabilística. Em um projeto com vida útil n, a probabilidade de ocorrer pelo menos uma vez um evento com período de retorno T_r é dada por:

$$P_n = 1 - \left(1 - \frac{1}{T_r}\right)^n$$

Por exemplo, para $T_r = 10$ anos e vida útil de $n = 30$ anos, obtém-se:

$$P_{30} = 1 - (0.9)^{30} \approx 0{,}9576$$

ou seja, uma probabilidade de aproximadamente 95,8 % de pelo menos uma ultrapassagem ao longo do período considerado. Isso mostra que escolher um período de retorno menor não elimina o risco; apenas o redistribui ao longo da vida do sistema.

2.2.1 Curvas intensidade-duração-frequência

A intensidade da chuva depende da duração do evento e do período de retorno adotado. Essa relação é obtida por meio das curvas intensidade-duração-frequência, conhecidas como curvas IDF. Sua forma é regional e deve ser obtida a partir de estudos locais ou de bases pluviográficas confiáveis.

Uma representação genérica da curva IDF é:

$$i = \frac{a\,T_r^m}{(t+b)^c}$$

em que:

- i é a intensidade da chuva, geralmente em mm/h;
- T_r é o período de retorno, em anos;
- t é a duração da chuva, em minutos ou horas, conforme a calibração da equação;
- a, b, c e m são parâmetros obtidos para a localidade.

Em drenagem urbana, a intensidade mais crítica é normalmente aquela associada a uma duração próxima ao tempo de concentração da bacia. Por isso, a determinação de t_c é etapa fundamental do projeto.

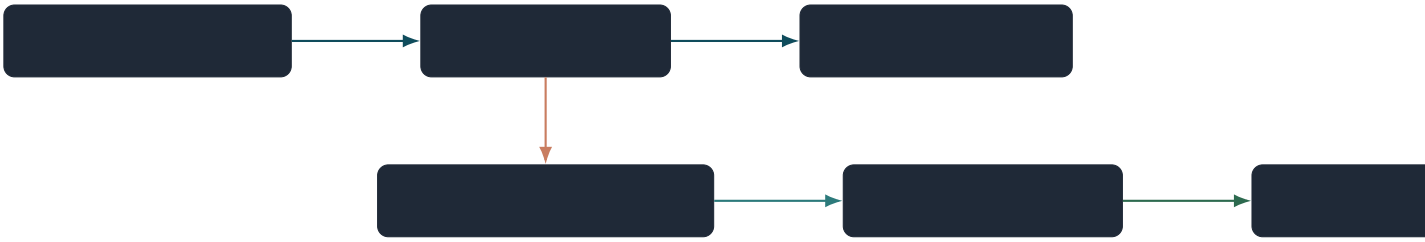

Figura 2.1: Fluxo básico do método racional em projetos preliminares de drenagem urbana.

2.3 Tempo de concentração

O tempo de concentração é influenciado por:

- comprimento do maior caminho de escoamento;
- declividade média do terreno;
- rugosidade da superfície;
- presença de calhas, sarjetas, galerias e canais;
- grau de impermeabilização;
- existência de depressões, travessias e obstáculos;
- conectividade hidráulica entre subáreas.

Em bacias urbanas, o tempo de concentração costuma diminuir à medida que a cidade se adensa, porque a água encontra trajetos mais curtos e mais lisos até a rede de drenagem. Isso faz com que o pico de vazão ocorra mais cedo e com maior intensidade.

Em projetos preliminares, o tempo de concentração pode ser estimado por:

- análise do percurso hidráulico mais longo;
- soma dos tempos de deslocamento em superfícies, sarjetas, galerias e canais;
- uso de fórmulas empíricas apropriadas para pequenas bacias;
- calibração com observações locais, quando disponíveis.

Na prática, o procedimento mais seguro é identificar o caminho hidráulico mais longo e verificar o tempo total de viagem da água até o exutório. Em áreas com grande heterogeneidade, o cálculo deve ser feito por subbacias.

2.4 Coeficiente de escoamento

Definição – Coeficiente de escoamento

Parâmetro adimensional que expressa a fração da chuva que se converte em escoamento superficial. Quanto maior o valor de C, maior tende a ser a vazão gerada.

Em áreas urbanas reais, o coeficiente de escoamento não deve ser escolhido de forma arbitrária. O procedimento correto é dividir a bacia em subáreas com comportamento hidrológico semelhante e calcular uma média ponderada:

$$C_m = \frac{\sum C_j A_j}{\sum A_j}$$

em que C_j é o coeficiente de cada subárea e A_j é a respectiva área.

2.4.1 Valores indicativos

A Tabela 2.1 apresenta valores indicativos de coeficiente de escoamento para apoio preliminar.

Tabela 2.1: Valores indicativos de coeficiente de escoamento para diferentes ocupações urbanas.

Tipo de superfície ou uso do solo	Coeficiente C	Observação
Telhados, lajes, concreto e asfalto contínuo	0.80 a 0.95	Alta impermeabilidade
Estacionamentos pavimentados e áreas muito compactadas	0.70 a 0.90	Dependem da inclinação e da condição da superfície
Residencial adensado com ruas e lotes mistos	0.45 a 0.70	Requer ponderação por subáreas
Residencial de baixa densidade	0.30 a 0.50	Varia com jardins, pavimentos e recuos
Áreas verdes urbanas e parques	0.05 a 0.25	Valores menores em solos bem conservados
Solo exposto ou compactado	0.20 a 0.40	Sensível à compactação e à umidade antecedente

Os valores da Tabela 2.1 são apenas indicativos. O projeto deve considerar a realidade local, o tipo de solo, a declividade, o estado de conservação das vias e a efetiva conectividade com a rede de drenagem.

2.5 O método racional

O método racional é uma forma simples e muito útil de estimar a vazão de pico em pequenas bacias urbanas. Sua expressão clássica é:

$$Q = 0.278\, C\, i\, A$$

em que:

- Q é a vazão de pico, em m³/s;
- C é o coeficiente de escoamento superficial, adimensional;
- i é a intensidade média da chuva, em mm/h;
- A é a área da bacia, em km².

Se a área estiver em hectares, a forma equivalente é:

$$Q = 0.00278\, C\, i\, A$$

com A em ha. O cuidado com as unidades é uma das principais fontes de erro em projetos. Um engano entre hectares e quilômetros quadrados pode alterar a vazão em uma ordem de grandeza.

2.5.1 Hipóteses do método racional

O método racional é muito útil, mas não é universal. Ele pressupõe que:

- a bacia é pequena o suficiente para que a chuva possa ser tratada como aproximadamente uniforme;
- a intensidade usada é a correspondente à duração crítica, usualmente próxima ao tempo de concentração;
- a vazão de pico é o principal interesse do projeto, e não todo o hidrograma;
- não há armazenamento significativo, propagação complexa ou controle hidráulico relevante no interior da bacia;
- o coeficiente de escoamento representa adequadamente a condição média da área contribuinte.

Quando a bacia é maior, quando há reservatórios, canais extensos, atrasos de propagação ou forte heterogeneidade espacial, o método racional deve ser substituído ou complementado por modelos hidrológicos mais robustos.

2.5.2 Comparação entre cenários

Considere a microbacia do capítulo anterior, com área de 20 ha e coeficiente médio ponderado $C_m = 0{,}64$. A Tabela 2.2 compara dois cenários de chuva de projeto para a mesma bacia.

No Cenário A:

Tabela 2.2: Comparação de cenários para a mesma microbacia usando o método racional.

Cenário	T_r	i	Q	**Observação**
A	10 anos	92 mm/h	3,27 m³/s	Referência preliminar
B	25 anos	108 mm/h	3,84 m³/s	Maior exigência de segurança

$$Q = 0.278 \times 0.64 \times 92 \times 0.20$$

$$Q \approx 3{,}27\ \mathrm{m^3/s}$$

No Cenário B:

$$Q = 0.278 \times 0.64 \times 108 \times 0.20$$

$$Q \approx 3{,}84\ \mathrm{m^3/s}$$

Esse comparativo mostra a sensibilidade do projeto à intensidade de chuva adotada. Em termos práticos, um aumento do período de retorno tende a elevar a vazão de dimensionamento e, consequentemente, o custo e a robustez do sistema.

2.6 Exemplo completo de dimensionamento

Considere uma microbacia urbana com área total de 18 ha, equivalente a 0,18 km². A ocupação do solo é a seguinte:

- 6 ha de telhados, pátios e superfícies impermeáveis, com $C = 0{,}85$;
- 8 ha de ruas, estacionamentos e áreas pavimentadas, com $C = 0{,}70$;
- 4 ha de áreas verdes urbanas, com $C = 0{,}20$.

2.6.1 Passo 1: coeficiente ponderado

$$C_m = \frac{6 \times 0.85 + 8 \times 0.70 + 4 \times 0.20}{18}$$

$$C_m = \frac{5.10 + 5.60 + 0.80}{18} = 0{,}6389$$

Logo, o coeficiente ponderado da bacia é aproximadamente $C_m = 0{,}64$.

2.6.2 Passo 2: escolha da chuva de projeto

Suponha que a análise da curva IDF local, para um período de retorno de 10 anos e duração igual ao tempo de concentração, forneça intensidade de:

$$i = 92\,\mathrm{mm/h}$$

2.6.3 Passo 3: cálculo da vazão de pico

Aplicando o método racional:

$$Q = 0.278 \times 0.6389 \times 92 \times 0.18$$

$$Q \approx 2{,}95\,\mathrm{m^3/s}$$

Portanto, a vazão de projeto da microbacia é de aproximadamente 2,95 $\mathrm{m^3/s}$. Esse valor será a base para o dimensionamento de sarjetas, bocas-de-lobo, coletores e demais elementos apresentados no próximo capítulo.

2.6.4 Análise de sensibilidade

Se a mesma área fosse ainda mais impermeabilizada, com $C = 0{,}75$ em vez de 0,64, a vazão subiria para:

$$Q = 0.278 \times 0.75 \times 92 \times 0.18$$

$$Q \approx 3{,}46\,\mathrm{m^3/s}$$

Isso mostra que pequenas mudanças no coeficiente de escoamento podem produzir aumentos expressivos na vazão. Em drenagem urbana, a impermeabilização não é apenas um dado de uso do solo; ela é um parâmetro hidráulico decisivo.

2.7 Erros frequentes em projetos

- usar intensidade de chuva sem compatibilidade com o tempo de concentração;
- aplicar o método racional em bacias grandes ou muito complexas;
- escolher um coeficiente C sem ponderação por subáreas;
- confundir hectares com quilômetros quadrados;
- adotar curva IDF de município vizinho sem justificativa técnica;
- ignorar armazenamento local, depressões e pequenos retardos hidráulicos;

- desconsiderar obstrução, manutenção e envelhecimento da rede;
- tratar a vazão calculada como se fosse infalível, sem margem de segurança.

A boa prática de projeto exige sempre verificação crítica dos resultados. A fórmula do método racional é simples, mas sua aplicação correta depende de julgamento técnico e leitura realista do território.

2.8 Resumo do capítulo

Resumo do capítulo

A chuva de projeto é uma representação estatística da precipitação usada para dimensionar sistemas de drenagem conforme o risco aceitável.
O período de retorno indica frequência média de ocorrência e não garante repetição exata do evento.
O tempo de concentração representa o tempo necessário para a água do ponto mais distante da bacia atingir o exutório e define a duração crítica do evento.
O método racional estima vazões de pico em pequenas bacias urbanas por meio de $Q = 0.278\, C\, i\, A$, com atenção rigorosa às unidades.
O coeficiente de escoamento deve ser ponderado por subáreas e ajustado às condições reais de ocupação, impermeabilização e conectividade hidráulica.
Este capítulo fornece a base quantitativa para o dimensionamento da microdrenagem no capítulo seguinte.

2.9 Exercícios

Exercício F1

Explique com suas palavras o que é chuva de projeto e por que ela não deve ser confundida com a maior chuva possível.

Exercício F2

Justifique por que, no método racional, a duração da chuva de projeto costuma ser escolhida próxima ao tempo de concentração da bacia.

Exercício F3

Mencione duas situações em que o método racional, isoladamente, pode ser inadequado.

Exercício M1

Calcule a probabilidade de ocorrer pelo menos uma ultrapassagem de um evento com período de retorno de 10 anos ao longo de uma vida útil de 30 anos.

Exercício M2

Para uma microbacia com 18 ha, estime o coeficiente ponderado de escoamento considerando:

- 6 ha com $C = 0{,}85$,
- 8 ha com $C = 0{,}70$,
- 4 ha com $C = 0{,}20$.

Exercício M3

Usando o coeficiente obtido no exercício M2, calcule a vazão de pico de uma bacia com área de 0,18 km^2 e intensidade de chuva de 92 mm/h.

Exercício M4

Mantendo a mesma área do exercício M3 e adotando $C = 0{,}75$ e $i = 108\,\mathrm{mm/h}$, calcule a nova vazão de pico e compare o resultado com o valor do exercício anterior.

Exercício D1

Uma prefeitura deseja escolher o período de retorno para dimensionar a drenagem de uma via arterial urbana. Discuta os critérios técnicos e sociais que devem orientar essa escolha, incluindo risco, custo, consequências da falha e manutenção futura.

Exercício D2

Elabore um roteiro técnico, em ordem lógica, para aplicar o método racional em uma microbacia urbana real. Indique quais dados precisam ser levantados em campo, quais podem ser obtidos por cartografia e quais exigem validação local.

2.10 Gabarito comentado

Gabarito comentado

F1. Chuva de projeto é um evento pluviométrico representativo usado no dimensionamento. Ela não é a maior chuva possível, mas uma chuva estatisticamente compatível com o risco aceitável, o custo da obra e a criticidade da área atendida.

F2. Porque a duração próxima ao tempo de concentração costuma produzir a condição crítica para a vazão de pico. Se a chuva durar muito menos, nem toda a bacia contribui; se durar muito mais, a intensidade média tende a cair. O valor de t_c ajuda a capturar o instante mais desfavorável.

F3. Exemplos: bacias grandes com forte heterogeneidade espacial; áreas com reservatórios, canais extensos ou forte armazenamento; sistemas em que a propagação da onda de cheia é relevante; estudos que exijam hidrograma completo e não apenas vazão de pico.

M1. A probabilidade de pelo menos uma ultrapassagem em 30 anos é:

$$P_{30} = 1 - \left(1 - \frac{1}{10}\right)^{30}$$

$$P_{30} = 1 - 0.9^{30} \approx 0.9576$$

Logo, a probabilidade é de aproximadamente 95,8 %. Isso mostra que um evento de 10 anos pode ocorrer várias vezes em uma vida útil longa.

M2. O coeficiente ponderado é:

$$C_m = \frac{6 \times 0.85 + 8 \times 0.70 + 4 \times 0.20}{18}$$

$$C_m = \frac{5.10 + 5.60 + 0.80}{18} = 0{,}6389$$

Portanto, $C_m \approx 0{,}64$. O resultado reflete uma bacia bastante urbanizada, embora ainda haja área verde.

M3. Aplicando o método racional:

$$Q = 0.278 \times 0.6389 \times 92 \times 0.18$$

$$Q \approx 2{,}95\,\mathrm{m^3/s}$$

Esse é o valor de vazão de pico a ser usado como base preliminar para o projeto.

M4. Para $C = 0{,}75$ e $i = 108\,\mathrm{mm/h}$:

$$Q = 0.278 \times 0.75 \times 108 \times 0.18$$

$$Q \approx 3{,}63\,\mathrm{m^3/s}$$

Comparando com 2,95 m³/s, o aumento é de cerca de 23 %. Isso confirma a forte sensibilidade da vazão à impermeabilização e à intensidade da chuva.

D1. A escolha do período de retorno deve considerar a classe da via, o custo de falha, a vulnerabilidade da população, a frequência aceitável de transtornos e a estratégia de manutenção. Vias com maior importância funcional e maior consequência de falha tendem a justificar períodos de retorno mais elevados. A decisão não deve ser apenas econômica; deve incluir segurança, continuidade operacional, responsabilidade pública e compatibilidade com o sistema a jusante.

D2. Um roteiro técnico consistente inclui: delimitação da bacia; mapeamento de usos do solo; medição ou estimativa do maior caminho de escoamento; cálculo do tempo de concentração; obtenção da curva IDF local; definição do período de retorno; ponderação do coeficiente C; cálculo de Q; verificação de coerência dimensional; análise de sensibilidade;

e validação em campo de pontos baixos, obstruções e pontos de contribuição concentrada. Dados de uso do solo e topografia podem vir de cartas, ortofotos e SIG; já as condições de drenagem, obstruções e conexões reais precisam de vistoria local.

2.11 Conexão com o próximo capítulo

Conexão com o próximo capítulo

Neste capítulo, a chuva de projeto, o tempo de concentração e o coeficiente de escoamento foram transformados em vazão de pico por meio do método racional. No próximo capítulo, essa vazão será aplicada diretamente ao dimensionamento dos elementos da microdrenagem urbana: sarjetas, bocas-de-lobo e coletores pluviais. Será o momento de converter a hidrologia de projeto em geometria hidráulica e critérios construtivos.

Capítulo 3

Sarjetas, bocas-de-lobo e coletores de drenagem pluvial

Depois de identificar como a urbanização altera o ciclo hidrológico e de calcular a vazão de projeto por meio do método racional, o próximo passo é transformar esse valor em infraestrutura real. Em drenagem urbana, a água da chuva não escoa de forma espontânea e segura apenas por existir uma superfície inclinada: ela precisa ser conduzida, captada e transportada por um sistema coerente. É exatamente essa a função da microdrenagem, formada principalmente por sarjetas, bocas-de-lobo, poços de visita e coletores pluviais (Botelho, 2011; Canholi, 2014).

Este capítulo apresenta os elementos básicos da microdrenagem urbana e os critérios iniciais de dimensionamento. A lógica é sempre a mesma: primeiro a água se organiza na sarjeta, depois é captada pela boca-de-lobo e, em seguida, conduzida pelo coletor até um ponto de descarga ou até a macrodrenagem. Quando qualquer uma dessas etapas falha, surgem alagamentos localizados, refluxos, transbordamentos e perda de desempenho do sistema.

Definição – Microdrenagem

Conjunto de dispositivos de drenagem voltados à captação e ao transporte das águas pluviais em escala de rua e quadra, normalmente composto por sarjetas, bocas-de-lobo, poços de visita e coletores.

3.1 Objetivos de aprendizagem

Ao final deste capítulo, o estudante deverá ser capaz de:

- explicar a função de sarjetas, bocas-de-lobo e coletores pluviais no sistema urbano;
- reconhecer critérios básicos de projeto para controle de espalhamento, captação e transporte;
- estimar, em nível preliminar, a capacidade hidráulica de uma sarjeta;
- comparar tipos de bocas-de-lobo e indicar sua aplicação mais adequada;
- dimensionar um coletor pluvial circular em regime de escoamento cheio, em nível preliminar;
- integrar os três elementos em um raciocínio único de projeto.

3.2 A microdrenagem como sistema

A microdrenagem não deve ser vista como um conjunto de peças independentes, mas como uma cadeia hidráulica. Cada elemento prepara o seguinte. A sarjeta recebe o escoamento da via; a boca-de-lobo capta a água antes que o alagamento se espalhe; o coletor pluvial conduz a vazão para jusante; e os poços de visita permitem inspeção, manutenção e mudanças de direção ou declividade.

Figura 3.1: Encadeamento funcional da microdrenagem urbana.

Esse encadeamento é importante porque uma solução local mal executada pode deslocar o problema para o trecho seguinte. Uma boca-de-lobo subdimensionada, por exemplo, não elimina a água: apenas aumenta o volume de bypass e a chance de alagamento a jusante. Um coletor mal dimensionado, por sua vez, pode receber a água captada e, ainda assim, falhar por sobrecarga, sedimentação ou perda de declividade funcional.

3.3 Sarjetas: função, geometria e capacidade

Definição – Sarjeta

Faixa longitudinal da via, junto ao meio-fio ou à borda da pista, destinada a conduzir o escoamento superficial até a boca-de-lobo ou outro dispositivo de captação.

A sarjeta é o primeiro elemento hidráulico da microdrenagem. Sua função é organizar o escoamento sobre a superfície viária e transportá-lo sem comprometer a segurança do tráfego, dos pedestres e dos acessos às edificações. Em termos práticos, a sarjeta deve:

- conduzir a água sem espalhamento excessivo sobre a pista;
- evitar lâmina d'água perigosa em faixas de circulação;
- manter velocidades compatíveis com o revestimento e com o conforto viário;
- direcionar a água para pontos de captação.

3.3.1 Parâmetros geométricos principais

Os dois parâmetros geométricos mais importantes são:

- **declividade longitudinal** S_0: inclinação da via no sentido do escoamento;
- **declividade transversal** S_x: inclinação da pista do eixo para a sarjeta.

Quanto maior a declividade longitudinal, maior tende a ser a velocidade da água. Quanto maior a declividade transversal, menor tende a ser o espalhamento da lâmina d'água sobre a pista. A geometria da rua, portanto, influencia diretamente o desempenho hidráulico.

Em uma aproximação preliminar, a sarjeta pode ser tratada como um canal triangular. Nesse caso:

$$T = \frac{y}{S_x}$$

em que T é a largura do espraiamento e y é a profundidade junto ao meio-fio. A área hidráulica aproximada é:

$$A \approx \frac{yT}{2}$$

e o perímetro molhado pode ser estimado por:

$$P \approx y + \sqrt{y^2 + T^2}$$

Logo, o raio hidráulico é:

$$R = \frac{A}{P}$$

A vazão na sarjeta pode então ser verificada pela equação de Manning:

$$Q = \frac{1}{n} A R^{2/3} S_0^{1/2}$$

em que n é o coeficiente de rugosidade.

3.3.2 Critérios de projeto para sarjetas

Em drenagem urbana, a verificação da sarjeta não depende apenas da capacidade hidráulica. O projetista deve observar também:

- **espraiamento admissível:** a água não deve ocupar largura excessiva da pista;
- **profundidade na borda:** lâminas muito altas prejudicam segurança e conforto;
- **velocidade do escoamento:** velocidades excessivas podem gerar riscos em declives fortes;
- **compatibilidade com a operação viária:** cruzamentos, acessos e travessias exigem controle mais rigoroso;
- **condições de manutenção:** sedimentos e resíduos podem reduzir a seção útil.

Os limites admissíveis de espraiamento e velocidade variam conforme manuais municipais, classe da via e condição do tráfego. Por isso, em projeto real, os parâmetros normativos locais devem prevalecer sobre valores genéricos de referência.

3.3.3 Estratégia prática de verificação

Uma sequência operacional adequada para a sarjeta é:

1. estimar a vazão que chega ao trecho;
2. definir a declividade da via e a rugosidade da superfície;
3. escolher uma espessura de lâmina compatível com a segurança viária;
4. calcular a vazão que a sarjeta consegue transportar;
5. comparar essa capacidade com a vazão de chegada;
6. determinar o excesso que deve ser captado pela boca-de-lobo.

Essa lógica mostra que a sarjeta não precisa transportar toda a vazão da bacia. Seu papel é organizar o fluxo até os pontos de captação, e não substituir a função da rede coletora.

3.4 Bocas-de-lobo: captação, tipologia e posicionamento

Definição – Boca-de-lobo

Dispositivo de captação de águas pluviais, normalmente instalado junto ao meio-fio ou na pista, destinado a receber a água acumulada na sarjeta e transferi-la para a rede de drenagem subterrânea.

A boca-de-lobo é o elo entre o escoamento superficial e o sistema subterrâneo. Quando bem posicionada e dimensionada, reduz a extensão do alagamento e protege a via. Quando mal localizada, deixa acumular água em ponto crítico, mesmo que a rede a jusante tenha capacidade suficiente.

3.4.1 Tipos mais usuais

Tabela 3.1: Principais tipos de bocas-de-lobo e suas características de uso.

Tipo	Vantagens	Limitações e uso típico
De meio-fio	Integra-se ao alinhamento da sarjeta; menor interferência na pista; boa estética urbana	Pode perder eficiência com folhas e sedimentos; depende de boa geometria da sarjeta; útil em ruas com meio-fio bem definido
Com grelha	Captura água superficial em depressões e áreas com grande contribuição lateral; pode receber fluxo de várias direções	Maior suscetibilidade a obstrução por lixo e detritos; requer manutenção frequente; útil em pontos baixos e áreas pavimentadas amplas
Combinada	Redundância hidráulica; associa captação por abertura lateral e por grelha; melhora a confiabilidade	Custo maior e maior complexidade construtiva; recomendável em locais críticos ou com alta vulnerabilidade

A escolha do tipo de boca-de-lobo depende de declividade, geometria da rua, volume esperado, risco de obstrução e facilidade de manutenção. Em áreas com muitas folhas, lixo ou sedimentos, a confiabilidade operacional pode ser mais importante do que a capacidade teórica de captação.

3.4.2 Critérios de localização

As bocas-de-lobo devem ser posicionadas, preferencialmente, em:

- pontos baixos e depressões da via;
- aproximações de interseções, onde o espraiamento pode aumentar;
- mudanças de declividade que concentrem o escoamento;
- trechos onde o espalhamento já se aproxima do limite admissível;
- áreas com grande contribuição lateral de calçadas, estacionamentos ou acessos.

A boa prática é considerar a rua como uma sequência de trechos de contribuição. Em cada trecho, a água deve ser captada antes que a lâmina se torne perigosa ou que o transbordamento alcance áreas sensíveis.

3.4.3 Capacidade hidráulica da captação

Em nível preliminar, a capacidade de uma boca-de-lobo pode ser analisada por dois regimes simplificados:

$$Q_w = C_w L h^{3/2}$$

para escoamento em regime de vertedor, e

$$Q_o = C_d A_o \sqrt{2gh}$$

para escoamento em regime de orifício.

Em que:

- Q_w é a vazão captada como vertedor;
- Q_o é a vazão captada como orifício;
- C_w é o coeficiente de vertedor;
- C_d é o coeficiente de descarga;
- L é o comprimento útil da abertura;
- A_o é a área útil da abertura;
- h é a lâmina de água junto à abertura;

- g é a aceleração da gravidade.

Em projeto real, a boca-de-lobo pode operar de forma mista, com parte do fluxo sendo captada e parte sendo desviada como bypass. Assim, a condição desejável é:

$$Q_{\text{cap}} \geq Q_{\text{cheg}}$$

ou, quando isso não for possível, que o excedente seja conduzido com segurança para a próxima unidade de captação.

3.4.4 Confiabilidade e manutenção

A eficiência de uma boca-de-lobo depende fortemente de manutenção. Entre os problemas mais comuns estão:

- obstrução por resíduos sólidos;
- deposição de sedimentos;
- deformações e assentamentos;
- grelhas danificadas ou inadequadas ao tráfego;
- conexão incorreta com o coletor.

Por isso, em drenagem urbana, projeto e operação devem ser tratados juntos. Uma boca-de-lobo teoricamente bem dimensionada pode falhar se não houver limpeza e inspeção periódicas.

3.5 Coletores pluviais: transporte subterrâneo da vazão

Definição – Coletor pluvial

Conduto, geralmente enterrado, destinado a transportar as águas pluviais captadas pela microdrenagem até pontos de lançamento, reservação, dissipação ou conexão com a macrodrenagem.

O coletor pluvial é a espinha dorsal subterrânea da drenagem urbana. Ele recebe a água das bocas-de-lobo e a conduz ao destino previsto em projeto. A função do coletor é transportar com segurança a vazão acumulada de vários trechos, sem provocar extravasamento, refluxo ou sedimentação excessiva.

3.5.1 Elementos associados

A rede de coletores é normalmente acompanhada por:

- **poços de visita:** pontos de inspeção, limpeza e mudança geométrica;
- **caixas de ligação:** estruturas de conexão entre dispositivos;
- **descidas ou degraus:** soluções para vencer desníveis acentuados;

- **dissipadores:** estruturas para reduzir energia na descarga.

Poços de visita devem ser previstos em mudanças de direção, de declividade, de diâmetro e em junções principais. A ausência desses elementos dificulta a manutenção e aumenta a probabilidade de obstrução e falhas operacionais.

3.5.2 Critérios hidráulicos básicos

O dimensionamento preliminar de coletores pluviais costuma ser feito pela equação de Manning:

$$Q = \frac{1}{n} A R^{2/3} S^{1/2}$$

em que S é a declividade hidráulica do trecho. Para um tubo circular escoando cheio:

$$A = \frac{\pi D^2}{4}$$

$$R = \frac{D}{4}$$

Substituindo na equação de Manning:

$$Q = \frac{1}{n} \frac{\pi D^2}{4} \left(\frac{D}{4}\right)^{2/3} S^{1/2}$$

e, resolvendo para o diâmetro:

$$D = \left[\frac{Q\, n\, 4^{5/3}}{\pi S^{1/2}}\right]^{3/8}$$

Essa expressão é útil em pré-dimensionamento de tubulações circulares. Em análises mais refinadas, podem ser considerados regime parcialmente cheio, perdas localizadas, cargas a montante, curva de remanso e condições de entrada e saída.

3.5.3 Velocidade, sedimentação e autolimpeza

Uma rede pluvial bem projetada deve evitar dois extremos:

- **velocidade baixa demais,** que favorece sedimentação e perda de seção útil;
- **velocidade alta demais,** que pode causar erosão, abrasão e problemas estruturais.

Por isso, o projetista deve buscar um equilíbrio entre declividade, diâmetro e material do tubo. Em situações de baixa declividade natural, a rede pode exigir ajustes geométricos, poços de queda ou intervenções complementares.

3.5.4 O sentido de cálculo

Em redes pluviais, é comum iniciar a análise pelos trechos de jusante, porque eles recebem a soma das contribuições a montante. A partir daí, as vazões são acumuladas trecho a trecho:

$$Q_j = Q_{j-1} + \sum Q_{\text{afluentes}} - Q_{\text{captado}}$$

Esse raciocínio evita subdimensionamentos e permite verificar se a tubulação de jusante suporta o fluxo acumulado de toda a sub-bacia tributária.

3.6 Procedimento prático de projeto

Uma boa prática de projeto para sarjetas, bocas-de-lobo e coletores segue os passos abaixo:

1. delimitar os trechos de contribuição superficial;
2. obter a vazão de projeto do capítulo anterior;
3. distribuir essa vazão ao longo da via, conforme a topografia;
4. verificar a capacidade da sarjeta e definir o espalhamento admissível;
5. localizar as bocas-de-lobo em pontos baixos e em trechos críticos;
6. estimar a capacidade de captação de cada dispositivo;
7. acumular as vazões nos coletores a jusante;
8. dimensionar os tubos por Manning e verificar a manutenção;
9. incluir poços de visita, conexões e descargas com segurança.

Essa sequência é importante porque o sistema deve funcionar como conjunto. Dimensionar somente o tubo sem verificar a captação na superfície é um erro comum. Da mesma forma, instalar muitas bocas-de-lobo sem checar a rede receptora também não resolve o problema.

3.7 Exemplo integrado de dimensionamento

Considere uma rua residencial com um ponto baixo onde se concentra o escoamento de uma sub-bacia urbana de 1,5 ha. Do capítulo anterior, tomaremos:

$$C = 0{,}65 \quad \text{e} \quad i = 92\,\text{mm/h}$$

A vazão de chegada ao ponto crítico é:

$$Q_{\text{cheg}} = 0.00278 \times 0.65 \times 92 \times 1.5$$

$$Q_{\text{cheg}} \approx 0{,}249\,\text{m}^3/\text{s}$$

1. Verificação preliminar da sarjeta

Admita uma via com declividade transversal $S_x = 0{,}02$, declividade longitudinal $S_0 = 0{,}008$ e lâmina admissível junto ao meio-fio de $y = 0{,}06$ m.

A largura do espraiamento será:

$$T = \frac{y}{S_x} = \frac{0.06}{0.02} = 3\,\text{m}$$

A área hidráulica aproximada é:

$$A \approx \frac{yT}{2} = \frac{0.06 \times 3}{2} = 0{,}09\,\text{m}^2$$

O perímetro molhado aproximado é:

$$P \approx y + \sqrt{y^2 + T^2} = 0.06 + \sqrt{0.06^2 + 3^2} \approx 3{,}0606\,\text{m}$$

Logo, o raio hidráulico é:

$$R = \frac{A}{P} \approx \frac{0.09}{3.0606} \approx 0{,}0294\,\text{m}$$

Adotando $n = 0{,}016$, a vazão conduzida pela sarjeta é:

$$Q_{\text{sarjeta}} = \frac{1}{0.016} \times 0.09 \times 0.0294^{2/3} \times 0.008^{1/2}$$

$$Q_{\text{sarjeta}} \approx 0{,}047\,\text{m}^3/\text{s}$$

Conclusão: a sarjeta, nessa condição geométrica, não transporta toda a vazão que chega. Ela apenas conduz uma fração até a boca-de-lobo. O restante precisa ser interceptado localmente.

2. Captação pela boca-de-lobo

Adote uma boca-de-lobo combinada com comprimento útil de 1,5 m, área útil de grelha de 0,12 m^2, altura de lâmina $h = 0{,}07$ m, $C_w = 1{,}8$ e $C_d = 0{,}65$.

A captação por vertedor é:

$$Q_w = C_w L h^{3/2} = 1.8 \times 1.5 \times 0.07^{3/2}$$

$$Q_w \approx 0{,}050\,\text{m}^3/\text{s}$$

A captação por orifício é:

$$Q_o = C_d A_o \sqrt{2gh} = 0.65 \times 0.12 \times \sqrt{2 \times 9.81 \times 0.07}$$

$$Q_o \approx 0{,}091\,\mathrm{m^3/s}$$

A capacidade preliminar total é:

$$Q_{\text{cap}} \approx Q_w + Q_o = 0{,}141\,\mathrm{m^3/s}$$

Como $Q_{\text{cap}} < Q_{\text{cheg}}$, a boca-de-lobo isolada não é suficiente. O excedente estimado é:

$$Q_{\text{bypass}} = Q_{\text{cheg}} - Q_{\text{cap}} \approx 0{,}108\,\mathrm{m^3/s}$$

Esse excedente deve ser conduzido de forma controlada até a próxima unidade de captação.

3. Dimensionamento do coletor

Suponha que o coletor a jusante deva transportar a vazão acumulada de 0,25 m³/s, com $n = 0{,}013$ e declividade $S = 0{,}005$.

O diâmetro preliminar será:

$$D = \left[\frac{0.25 \times 0.013 \times 4^{5/3}}{\pi \times 0.005^{1/2}}\right]^{3/8}$$

$$D \approx 0{,}49\,\mathrm{m}$$

Logo, a seleção preliminar adequada é um tubo de 500 mm. Em projeto executivo, ainda seriam verificados regime de escoamento, profundidade de assentamento, cobertura mínima, poços de visita e transições geométricas.

3.8 Erros frequentes em projetos

- dimensionar o tubo sem verificar a capacidade da sarjeta e da captação;
- instalar bocas-de-lobo em locais convenientes à obra, e não em locais hidráulicos críticos;
- ignorar o efeito de resíduos, folhas e sedimentos na captação;
- tratar todos os trechos da via como se tivessem a mesma contribuição;
- esquecer poços de visita em mudanças de direção e declividade;
- usar o diâmetro mínimo sem checar capacidade hidráulica real;
- desprezar o bypass quando a captação não é total;
- não considerar manutenção periódica como parte do projeto.

A microdrenagem funciona quando o projeto é coerente com a topografia, a hidrologia e a operação urbana. A melhor solução técnica é aquela que ainda permanece eficiente depois de instalada e mantida ao longo do tempo.

3.9 Resumo do capítulo

Resumo do capítulo

A microdrenagem urbana é o sistema que capta e transporta a água pluvial em escala de rua.

A sarjeta organiza o escoamento superficial e deve ser verificada por espalhamento, profundidade e capacidade hidráulica.

A boca-de-lobo é o dispositivo de captação que liga a superfície à rede subterrânea; sua eficiência depende do tipo, da posição e da manutenção.

O coletor pluvial conduz a vazão acumulada de vários trechos e é dimensionado, em nível preliminar, por Manning e pela continuidade.

Poços de visita, conexões e descargas são parte integrante do sistema e não acessórios opcionais.

O próximo capítulo mostrará como controlar o excedente hidráulico por meio de bacias de detenção e retenção.

3.10 Exercícios

Exercício F1

Explique a função de sarjeta, boca-de-lobo e coletor pluvial em uma rede de microdrenagem.

Exercício F2

Por que as bocas-de-lobo devem ser instaladas preferencialmente em pontos baixos e em trechos de maior contribuição superficial?

Exercício F3

Compare os três tipos mais usuais de bocas-de-lobo: de meio-fio, com grelha e combinada.

Exercício M1

Uma boca-de-lobo combinada possui comprimento útil de 1,5 m, área útil de grelha de 0,12 m^2, lâmina $h = 0{,}07$ m, coeficiente de vertedor $C_w = 1{,}8$ e coeficiente de descarga $C_d = 0{,}65$. Calcule, de forma preliminar, as vazões Q_w, Q_o e a capacidade total de captação.

Exercício M2

Para um coletor pluvial circular que deve conduzir 0,25 m^3/s, com rugosidade $n = 0{,}013$ e declividade $S = 0{,}005$, estime o diâmetro necessário pelo regime de escoamento cheio.

Exercício M3

Usando a estimativa de capacidade da sarjeta apresentada no exemplo integrado, verifique o quanto ela é capaz de transportar e compare com a vazão de chegada de 0,249 m^3/s. Determine o bypass aproximado.

Exercício D1

Elabore um plano conceitual para uma rua em declive com duas interseções e um ponto baixo central. Indique onde você posicionaria as bocas-de-lobo e explique o critério hidráulico usado em cada decisão.

Exercício D2

A partir da vazão de projeto obtida no capítulo anterior, proponha uma sequência completa de pré-dimensionamento para sarjeta, boca-de-lobo e coletor pluvial de um trecho urbano real. Explique quais dados precisam ser obtidos em campo e quais podem ser estimados por cartografia ou projeto geométrico.

3.11 Gabarito comentado

Gabarito comentado

F1. A sarjeta conduz o escoamento superficial ao longo da via; a boca-de-lobo capta a água e a transfere à rede subterrânea; o coletor pluvial transporta a vazão captada até o destino final, normalmente um ponto de descarga ou uma estrutura de macrodrenagem.

F2. Porque os pontos baixos concentram o escoamento e, se não houver captação adequada, acumulam água rapidamente. Trechos com maior contribuição superficial também exigem captação antecipada, evitando que a lâmina se espalhe e ocupe a pista, calçadas ou acessos.

F3. A boca-de-lobo de meio-fio integra-se à borda da via e tem boa inserção urbana; a com grelha capta água superficial em áreas pavimentadas ou depressões, mas pode obstruir com facilidade; a combinada reúne duas formas de captação e oferece maior redundância, sendo útil em pontos críticos.

M1. A captação por vertedor é:

$$Q_w = 1.8 \times 1.5 \times 0.07^{3/2}$$

Como $0.07^{3/2} \approx$ 0,018 52, resulta:

$$Q_w \approx 0{,}050\ \mathrm{m^3/s}$$

A captação por orifício é:

$$Q_o = 0.65 \times 0.12 \times \sqrt{2 \times 9.81 \times 0.07}$$

$$Q_o \approx 0{,}091\,\mathrm{m^3/s}$$

Logo, a capacidade total preliminar é:

$$Q_{\mathrm{cap}} \approx 0{,}141\,\mathrm{m^3/s}$$

A conclusão correta é que essa boca-de-lobo não capta toda a vazão de chegada se a contribuição for maior do que esse valor; portanto, o projeto deve prever bypass ou reforço de captação.

M2. Para um tubo circular cheio:

$$Q = \frac{1}{n}\frac{\pi D^2}{4}\left(\frac{D}{4}\right)^{2/3} S^{1/2}$$

Isolando D:

$$D = \left[\frac{Q\,n\,4^{5/3}}{\pi S^{1/2}}\right]^{3/8}$$

Substituindo $Q = 0{,}25\,\mathrm{m^3/s}$, $n = 0{,}013$ e $S = 0{,}005$:

$$D \approx 0{,}49\,\mathrm{m}$$

Assim, uma tubulação de 500 mm é a escolha preliminar adequada.

M3. A capacidade da sarjeta, no exemplo, foi estimada em aproximadamente 0,047 m³/s. Comparando com a vazão de chegada de 0,249 m³/s, observa-se que a sarjeta conduz apenas uma parcela do total. O bypass aproximado é:

$$Q_{\mathrm{bypass}} = 0.249 - 0.047 = 0{,}202\,\mathrm{m^3/s}$$

O resultado mostra que a sarjeta não deve ser tratada como elemento de armazenamento de toda a vazão, mas como conduto superficial até a boca-de-lobo.

D1. Um bom plano deve posicionar bocas-de-lobo nos pontos baixos e antes das interseções mais críticas, de modo a dividir a contribuição superficial em trechos menores. Em uma rua em declive, a captação deve evitar que a água ganhe velocidade excessiva ao longo do eixo viário. Se houver um ponto baixo central, ele deve receber captação reforçada ou combinada, enquanto os trechos de montante precisam ser interceptados antes de concentrarem volumes excessivos. O critério hidráulico central é manter o espraiamento dentro do limite admissível e impedir que a água ultrapasse áreas de circulação sensíveis.

D2. A sequência correta inclui: delimitação do trecho, leitura da topografia, definição do caminho principal de escoamento, verificação da vazão de projeto, análise da capacidade da sarjeta, escolha do tipo e posição da boca-de-lobo, acumulação das vazões no coletor, pré-dimensionamento do diâmetro e checagem de manutenção e acessibilidade. Em

campo, devem ser levantados pontos baixos, obstruções, condição das bocas existentes, interferências e declividades reais. Por cartografia e projeto geométrico, podem ser obtidos o traçado da via, cotas, declividades e áreas contribuintes.

3.12 Conexão com o próximo capítulo

Conexão com o próximo capítulo

Neste capítulo, a vazão de projeto foi convertida em elementos de microdrenagem: sarjetas, bocas-de-lobo e coletores pluviais. No próximo capítulo, a lógica será ampliada para estruturas de armazenamento, como bacias de detenção e retenção, que permitem amortecer picos de cheia e reduzir a sobrecarga da rede. Assim, a drenagem deixa de ser apenas transporte e passa a incorporar, de forma controlada, o princípio do retardamento hidráulico.

Capítulo 4

Bacias de detenção e retenção: dimensionamento

Quando a microdrenagem já foi dimensionada e, ainda assim, a vazão gerada pela bacia continua acima da capacidade do sistema a jusante, a solução deixa de ser apenas transportar mais água mais rapidamente. Nesse ponto, o projeto passa a incorporar um princípio essencial da drenagem urbana moderna: **retardar o escoamento**, armazenando temporariamente parte do volume gerado para reduzir o pico de descarga. É essa a função das bacias de detenção e retenção (Tucci, 2008; Botelho, 2011; Pompeo, 2000; Canholi, 2014).

Essas estruturas atuam como "pulmões hidráulicos" do sistema urbano. Em vez de transferirem instantaneamente todo o excesso de água para jusante, elas amortecem a resposta da bacia, diminuem o risco de sobrecarga de galerias e canais e permitem maior controle sobre a vazão de saída. Em áreas urbanas densas, esse tipo de controle é muitas vezes indispensável para compatibilizar ocupação do solo, infraestrutura existente e segurança hidrológica.

Definição – Bacia de detenção

Estrutura destinada ao armazenamento temporário de águas pluviais, com descarga controlada após o evento de chuva. Em geral, permanece seca ou com lâmina reduzida durante o tempo normal.

Definição – Bacia de retenção

Estrutura de armazenamento que mantém um volume permanente de água e regula a liberação das vazões excedentes. Além da função hidráulica, pode contribuir para a melhoria da qualidade da água e para o paisagismo urbano.

4.1 Objetivos de aprendizagem

Ao final deste capítulo, o estudante deverá ser capaz de:

- diferenciar bacias de detenção e de retenção;
- explicar por que o armazenamento temporário reduz o pico de vazão;
- identificar os principais componentes físicos de uma bacia de controle;
- estimar o volume necessário de armazenamento a partir de um hidrograma simplificado;

- dimensionar, em nível preliminar, um dispositivo de saída por orifício ou vertedor;
- verificar critérios mínimos de segurança, operação e manutenção.

4.2 Função das bacias no sistema de drenagem

As bacias de detenção e retenção são usadas quando não basta ampliar a rede coletora ou aprofundar canais. Elas são especialmente úteis em quatro situações principais:

- quando a vazão de pico excede a capacidade da rede existente;
- quando o lançamento a jusante precisa ser limitado para não agravar cheias;
- quando a bacia contribui com grande volume concentrado após a urbanização;
- quando se deseja integrar drenagem, paisagem e qualidade ambiental.

Do ponto de vista hidrológico, a bacia atua por meio de **armazenamento** e **descarga controlada**. Durante a chuva, o volume de entrada é maior que o volume de saída; o excesso fica temporariamente acumulado. Após a passagem do pico, o armazenamento esvazia gradualmente.

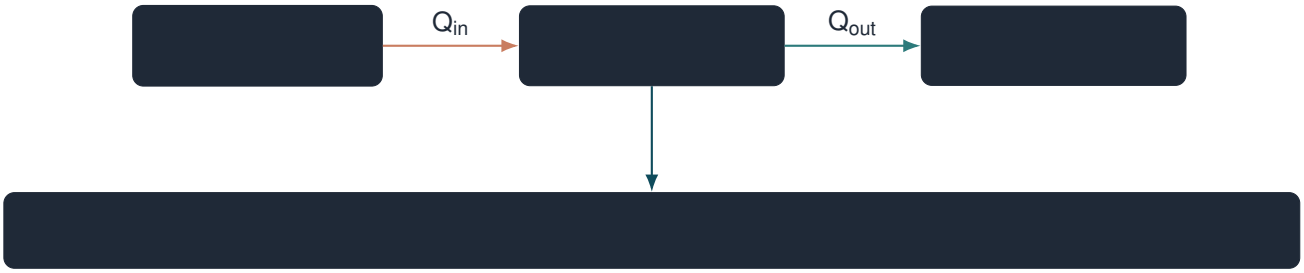

Figura 4.1: Princípio hidráulico de uma bacia de detenção ou retenção.

A Figura 4.1 resume a lógica fundamental: a entrada instantânea da chuva é reduzida para uma saída compatível com a capacidade do sistema receptor.

4.3 Detenção, retenção e infiltração: diferenças importantes

Esses três conceitos são próximos, mas não equivalentes.

Na drenagem urbana brasileira, o termo “retenção” é muitas vezes usado para estruturas com lâmina permanente ou com forte contribuição paisagística. Já a detenção é mais associada ao amortecimento hidrológico propriamente dito. Em ambos os casos, o objetivo é controlar a vazão de descarga e não apenas acumular água de forma passiva.

4.4 Princípio de dimensionamento hidrológico

O dimensionamento de uma bacia de controle parte da relação entre a vazão afluente, a vazão efluente e o volume armazenado. Em forma contínua, o princípio de continuidade é:

Tabela 4.1: Diferença entre bacia de detenção, bacia de retenção e solução de infiltração.

Tipo	Funcionamento	Vantagens	Cuidados
Detenção	Armazena a água apenas durante o evento e libera o volume gradualmente após a chuva	Reduz o pico de vazão e a sobrecarga da rede	Exige verificação de esvaziamento, segurança e limpeza
Retenção	Mantém um espelho d'água permanente e regula excedentes por um dispositivo de saída	Pode melhorar a paisagem, a qualidade da água e o conforto ambiental	Requer controle sanitário, estabilidade de taludes e manutenção contínua
Infiltração	Direciona o volume para o solo, favorecendo percolação e recarga	Diminui escoamento superficial e ajuda na recarga subterrânea	Depende fortemente da permeabilidade do solo e da qualidade da água infiltrada

$$\frac{dS}{dt} = Q_{\text{in}}(t) - Q_{\text{out}}(t)$$

em que S representa o armazenamento na bacia.

Integrando no tempo:

$$S(t) = \int_0^t \Big(Q_{\text{in}}(\tau) - Q_{\text{out}}(\tau)\Big)\, d\tau$$

A capacidade mínima de armazenamento é dada pelo maior valor acumulado dessa diferença ao longo do evento:

$$V_{\text{req}} = \max_t \left[\int_0^t \Big(Q_{\text{in}}(\tau) - Q_{\text{out}}(\tau)\Big)\, d\tau\right]$$

Em termos discretos, para intervalos de tempo iguais, pode-se usar uma aproximação por soma acumulada:

$$S_k = S_{k-1} + \Big(Q_{\text{in},k} - Q_{\text{out},k}\Big)\Delta t$$

em que S_k é o armazenamento ao final do intervalo k e Δt é o passo de cálculo.

Essa é a base de qualquer rotina de reservação: determinar quanto entra, quanto pode sair e quanto precisa ficar temporariamente armazenado.

4.4.1 Vazão admissível de saída

A vazão de saída não é escolhida arbitrariamente. Ela deve ser compatível com a capacidade da rede, do canal ou do corpo receptor a jusante. Em termos práticos, a vazão controlada costuma atender a pelo menos um dos seguintes critérios:

- não ultrapassar a capacidade hidráulica do sistema receptor;
- não aumentar a vazão de pico em relação à condição pré-urbanização;
- limitar a contribuição de uma nova ocupação urbana para o sistema existente;
- respeitar metas definidas em plano diretor de drenagem.

Assim, a seleção de Q_{out} é uma decisão técnica e de planejamento, não apenas um cálculo hidráulico isolado.

4.5 Componentes físicos de uma bacia de controle

Uma bacia de detenção ou retenção bem projetada normalmente inclui os seguintes elementos:

Tabela 4.2: Elementos físicos mais usuais em bacias de detenção e retenção.

Elemento	Função
Bacia ou volume útil	Armazena temporariamente o excedente de água pluvial
Dispositivo de entrada	Recebe e distribui a vazão afluente, reduzindo energia e erosão
Dispositivo de saída	Controla a liberação do volume armazenado
Vertedor de emergência	Protege a estrutura em eventos acima da condição de projeto
Freeboard	Margem vertical de segurança entre o nível máximo da água e o coroamento
Bacia de sedimentação preliminar	Retém sólidos mais grosseiros antes da área principal
Taludes e bermas	Garantem estabilidade geométrica e segurança estrutural
Dreno de fundo	Permite esvaziamento, inspeção e manutenção
Proteção contra erosão	Evita arraste de solo e degradação das margens

Definição – Freeboard

Margem vertical de segurança entre o nível máximo operacional da água e a cota do coroamento da estrutura.

4.5.1 Dispositivo de saída

O dispositivo de saída é a peça mais sensível do projeto. Ele pode ser um orifício, um vertedor, uma combinação de ambos ou um sistema em múltiplos estágios. O objetivo é fazer a descarga crescer de forma controlada com o aumento do nível d'água.

Para um orifício submerso, a vazão pode ser estimada por:

$$Q = C_d A \sqrt{2gh}$$

em que:

- Q é a vazão de saída em m³/s;

- C_d é o coeficiente de descarga;
- A é a área da abertura em m^2;
- g é a aceleração da gravidade;
- h é a carga hidráulica sobre o centro da abertura.

Para um vertedor simples, pode-se usar a forma:

$$Q = C_w L h^{3/2}$$

em que L é o comprimento do vertedor. A escolha entre orifício e vertedor depende do intervalo de níveis operacionais, da meta de vazão e da geometria disponível.

Tabela 4.3: Dispositivos usuais de saída e uso típico.

Dispositivo	Uso predominante	Observação técnica
Orifício	Controle de vazões frequentes e medianas	Requer proteção contra obstrução e boa acessibilidade
Vertedor	Condições de maior nível e descarga de emergência	Útil como elemento complementar de segurança
Sistema multistágio	Combinação de diferentes faixas de operação	Solução mais robusta para projetos urbanos

4.5.2 Segurança e operação

Bacias urbanas exigem cuidados específicos:

- **estabilidade geotécnica:** taludes devem ser seguros e resistentes à saturação;
- **segurança de pessoas:** em áreas públicas, é necessário reduzir risco de quedas e afogamento;
- **controle de erosão:** entradas e saídas precisam de dissipação de energia;
- **acessibilidade para manutenção:** equipes devem conseguir operar a estrutura;
- **controle de sedimentos e lixo:** o acúmulo compromete a capacidade útil;
- **drenagem do volume remanescente:** o esvaziamento deve ocorrer em prazo compatível com o objetivo do sistema e com a operação local.

Em bacias de detenção, o período de esvaziamento deve ser suficiente para evitar novo enchimento imediato, mas não tão longo a ponto de comprometer operação e manutenção. Em bacias de retenção, os aspectos de qualidade da água, vegetação, fauna urbana e riscos sanitários também precisam ser considerados.

4.5.3 Bacia de sedimentação preliminar

Definição – Bacia de sedimentação preliminar

Compartimento inicial destinado a reduzir a entrada de sólidos grosseiros e sedimentos na área principal de armazenamento, facilitando a manutenção e preservando o volume útil.

Sempre que possível, o projeto deve reservar uma parcela inicial do volume para sedimentação. Esse detalhe reduz obstruções, protege o dispositivo de saída e simplifica a limpeza rotineira.

4.6 Critérios de localização

A seleção do local influencia diretamente o custo, o desempenho e a segurança da obra. Os critérios mais importantes são:

- proximidade de áreas com grande geração de escoamento;
- disponibilidade de área livre ou subutilizada;
- cota adequada para receber vazão por gravidade;
- ausência de conflitos com edificações, redes enterradas e faixas de utilidade;
- condição geotécnica compatível com a escavação e o aterro;
- possibilidade de integração com parques, praças e áreas verdes;
- facilidade de manutenção e acesso operacional.

Bacias de controle podem ser implantadas em parques lineares, áreas públicas, fundos de vale, terrenos institucionais, canteiros centrais alargados ou glebas destinadas a uso coletivo. O importante é que o reservatório se encaixe na lógica da drenagem e do uso do solo, em vez de competir com ele.

4.7 Procedimento de dimensionamento

Uma sequência didática e tecnicamente consistente para o projeto de uma bacia de detenção ou retenção é:

1. delimitar a área contribuinte e obter a vazão afluente;
2. definir a vazão admissível de saída;
3. construir ou adotar o hidrograma de entrada;
4. calcular o volume acumulado por diferença entre entrada e saída;
5. adotar um fator de segurança para incertezas e sedimentação;

6. escolher a geometria preliminar da bacia;
7. dimensionar o dispositivo de saída;
8. verificar o vertedor de emergência e o freeboard;
9. analisar estabilidade, manutenção, paisagismo e segurança pública.

O passo mais importante é o cálculo do volume máximo acumulado. Sem ele, qualquer geometria proposta corre o risco de não armazenar o excesso real da chuva de projeto.

4.8 Exemplo completo de dimensionamento

Considere uma bacia urbana de contribuição localizada a montante de um parque público. A análise hidrológica indicou uma descarga potencial elevada, e a gestão local decidiu limitar a vazão de saída a 1,0 m³/s. Foi adotado um hidrograma simplificado, com intervalos de 1 h, conforme a Tabela 4.4.

Tabela 4.4: Hidrograma simplificado utilizado no exemplo de dimensionamento.

Intervalo (h)	Q_{in} **médio**	Q_{out}	**Volume líquido**	**Armazenamento acumulado**
0–1	0,8 m³/s	0,8 m³/s	0 m³	0 m³
1–2	1,6 m³/s	1,0 m³/s	2160 m³	2160 m³
2–3	2,4 m³/s	1,0 m³/s	5040 m³	7200 m³
3–4	3,0 m³/s	1,0 m³/s	7200 m³	14 400 m³
4–5	2,2 m³/s	1,0 m³/s	4320 m³	18 720 m³
5–6	1,4 m³/s	1,0 m³/s	1440 m³	20 160 m³
6–7	0,9 m³/s	1,0 m³/s	–360 m³	19 800 m³

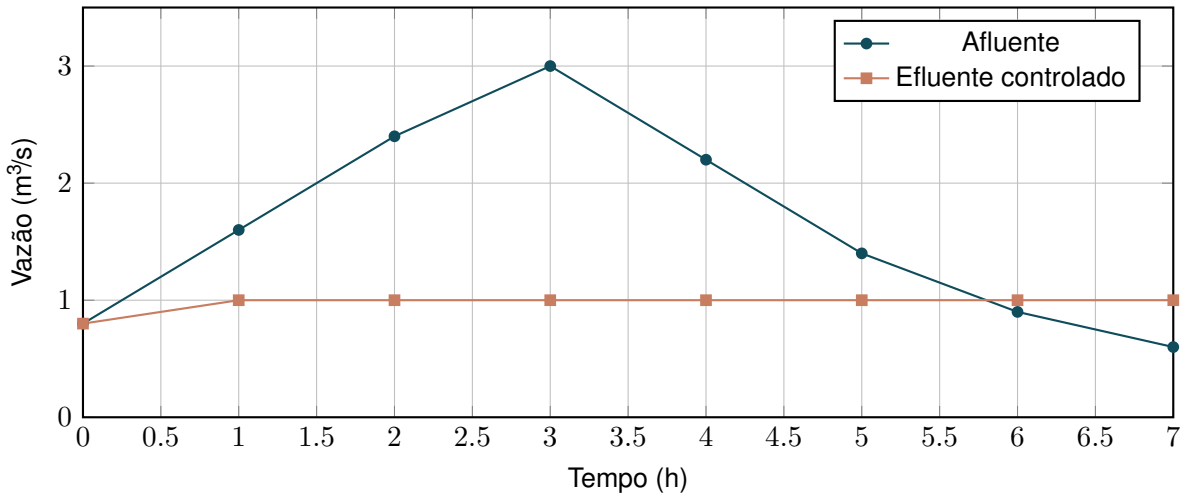

Figura 4.2: Hidrograma simplificado de entrada e descarga controlada adotado no exemplo.

1. Volume necessário de armazenamento

O maior valor acumulado da diferença entre entrada e saída é:

$$V_{\text{req}} = 20\,160\ \text{m}^3$$

Esse é o volume mínimo teórico necessário para conter o evento de projeto sem ultrapassar a vazão admissível.

2. Margem de segurança

Em projetos reais, recomenda-se considerar reserva adicional para sedimentação, incertezas hidrológicas e eventuais perdas de eficiência. Admitindo um fator de segurança de 10 %:

$$V_{\text{proj}} = 1.10 \times 20160 = 22\,176\ \text{m}^3$$

Arredondando, adota-se:

$$V_{\text{proj}} \approx 22\,200\ \text{m}^3$$

3. Geometria preliminar

Se a profundidade útil de armazenamento for de 2,2 m, a área média necessária é:

$$A_{\text{m}} = \frac{V_{\text{proj}}}{h} = \frac{22176}{2.2} \approx 10\,080\ \text{m}^2$$

Assim, pode-se propor uma área de espelho d'água ou área útil aproximada de 10 100 m^2, considerando taludes, bermas e uma zona de sedimentação preliminar.

4. Dimensionamento da saída

Suponha um orifício submerso com descarga controlada para a vazão de 1,0 m^3/s, adotando carga hidráulica de 1,5 m e coeficiente de descarga $C_d = 0{,}62$.

A área da abertura é:

$$A = \frac{Q}{C_d\sqrt{2gh}}$$

$$A = \frac{1.0}{0.62\sqrt{2 \times 9.81 \times 1.5}} \approx 0{,}298\ \text{m}^2$$

O diâmetro equivalente é:

$$D = \sqrt{\frac{4A}{\pi}} = \sqrt{\frac{4 \times 0.298}{\pi}} \approx 0{,}615\ \text{m}$$

Logo, o diâmetro equivalente preliminar é de aproximadamente 615 mm. Em projeto executivo, essa abertura deve ser compatibilizada com peças comerciais, operação em diferentes cotas e eventual necessidade de ajuste fino da vazão.

5. Interpretação do resultado

O resultado mostra um ponto importante de projeto: uma abertura única de grande porte pode ser tecnicamente inconveniente, sobretudo em áreas urbanas com risco de entupimento, necessidade de controle por faixas de vazão e exigência de manutenção simples. Por essa razão, em obras reais, costuma-se preferir um **sistema de saída em estágios**, com um dispositivo principal de pequeno porte, outro para vazões intermediárias e um vertedor de emergência para eventos acima da condição de projeto.

6. Verificações complementares

Além do volume e da descarga, o projeto deve conferir:

- se o vertedor de emergência está dimensionado para eventos acima da chuva de projeto;
- se o freeboard é suficiente para proteger o coroamento;
- se o acesso de manutenção é viável;
- se a estabilidade dos taludes é compatível com o solo local;
- se a estrutura de entrada reduz erosão e arraste de sedimentos;
- se a drenagem do volume remanescente ocorre no prazo operacional previsto.

Esse conjunto de verificações é tão importante quanto o cálculo hidráulico. Uma bacia que armazena corretamente, mas não pode ser mantida com segurança, não é uma solução completa.

4.9 Erros frequentes em projetos

- confundir volume de armazenamento com área superficial da bacia;
- escolher a vazão de saída sem considerar a capacidade do sistema a jusante;
- dimensionar apenas o corpo principal e esquecer o vertedor de emergência;
- ignorar o efeito de sedimentos no volume útil ao longo do tempo;
- adotar profundidades excessivas sem avaliar segurança de usuários;
- não prever acesso de manutenção e limpeza;
- tratar retenção e detenção como se fossem a mesma solução;
- desprezar a influência da topografia e do traçado urbano no custo da obra.

4.10 Resumo do capítulo

Resumo do capítulo

Bacias de detenção e retenção são estruturas de controle de vazões que armazenam temporariamente o excesso de água pluvial e liberam a descarga de forma controlada.
A detenção é, em geral, temporária e seca entre eventos; a retenção costuma manter um volume permanente de água.
O dimensionamento hidrológico baseia-se na diferença entre vazão afluente e vazão efluente, sendo o volume máximo acumulado o parâmetro central do projeto.
A estrutura deve incluir entrada, saída, vertedor de emergência, freeboard, proteção contra erosão, drenagem de fundo e condições seguras de operação e manutenção.
No exemplo desenvolvido, a bacia precisou armazenar cerca de 20 160 m^3, valor que, com margem de segurança, resultou em um volume de projeto de aproximadamente 22 200 m^3.
No próximo capítulo, a lógica do controle será ampliada para soluções distribuídas e mais integradas ao espaço urbano, como jardins de chuva, biovaletas e pavimentos permeáveis.

4.11 Exercícios

Exercício F1

Explique a diferença entre bacia de detenção e bacia de retenção.

Exercício F2

Por que uma bacia de controle reduz o pico de vazão a jusante?

Exercício F3

Cite pelo menos quatro componentes físicos essenciais de uma bacia de detenção ou retenção.

Exercício M1

Com base no hidrograma do exemplo, determine o volume mínimo de armazenamento necessário para o evento de projeto.

Exercício M2

Adotando um fator de segurança de 10 %, calcule o volume de projeto e estime a área média necessária para uma profundidade útil de 2,2 m.

Exercício M3

Para uma vazão controlada de 1,0 m^3/s, carga hidráulica de 1,5 m e coeficiente de descarga $C_d = 0{,}62$, calcule a área equivalente do orifício e o diâmetro correspondente.

Exercício D1

Uma prefeitura dispõe de um terreno público de 1,2 ha em uma área com alagamentos frequentes. Proponha, em linhas gerais, se o melhor uso hidrológico seria uma bacia de detenção, uma bacia de retenção ou uma solução combinada. Justifique a resposta considerando topografia, operação, segurança e manutenção.

Exercício D2

Elabore um roteiro completo de projeto para uma bacia de controle em bairro urbano consolidado. Inclua: levantamento de dados, definição da vazão de saída, cálculo do volume, escolha geométrica, estrutura de saída, drenagem de fundo, segurança pública e plano de manutenção.

4.12 Gabarito comentado

Gabarito comentado

F1. A bacia de detenção armazena a água apenas durante o evento e libera a vazão gradualmente, geralmente ficando seca entre chuvas. A bacia de retenção, por sua vez, mantém um volume permanente de água e regula os excedentes por meio de descarga controlada. Em geral, a retenção possui maior integração paisagística e pode contribuir para a qualidade da água.

F2. Porque o armazenamento temporário retém parte do volume que chegaria simultaneamente ao sistema a jusante. Ao reduzir a vazão de saída para um valor admissível, a bacia espalha a descarga no tempo e diminui o pico. O efeito hidráulico não é eliminar a água, mas reorganizar sua chegada.

F3. Entre os componentes essenciais estão: volume útil de armazenamento, dispositivo de entrada, dispositivo de saída, vertedor de emergência, freeboard, drenagem de fundo, taludes e proteção contra erosão. Quatro deles já são suficientes para caracterizar um projeto básico funcional.

M1. Pelo hidrograma do exemplo, o maior armazenamento acumulado é de 20 160 m^3. Portanto, esse é o volume mínimo teórico necessário para conter o evento com vazão de saída de 1,0 m^3/s.

M2. Com fator de segurança de 10 %:

$$V_{\text{proj}} = 1.10 \times 20160 = 22\,176\ \text{m}^3$$

Arredondando, $V_{\text{proj}} \approx 22\,200$ m^3.

Para profundidade útil de 2,2 m:

$$A_{\text{m}} = \frac{22176}{2.2} \approx 10\,080\ \text{m}^2$$

Logo, a área média necessária é da ordem de 10 100 m^2, podendo ser adotada uma área útil de projeto levemente superior para acomodar taludes e dispositivos internos.

M3. A área do orifício é:

$$A = \frac{1.0}{0.62\sqrt{2 \times 9.81 \times 1.5}} \approx 0{,}298\,\text{m}^2$$

O diâmetro equivalente é:

$$D = \sqrt{\frac{4 \times 0.298}{\pi}} \approx 0{,}615\,\text{m}$$

Portanto, o orifício equivalente tem área próxima de 0,30 m^2 e diâmetro de aproximadamente 615 mm. Em projeto executivo, deve-se compatibilizar esse valor com peças comerciais, operação em diferentes cotas e eventual necessidade de ajuste fino da vazão.

D1. Em um terreno de 1,2 ha, a decisão depende de vários fatores. Se a prioridade for reduzir o pico e a área puder permanecer seca na maior parte do tempo, uma bacia de detenção é geralmente mais simples e segura. Se houver interesse paisagístico e disponibilidade para manutenção constante, uma bacia de retenção pode ser adequada. Em muitos casos, a solução combinada é a mais eficiente: um volume permanente menor, com capacidade adicional de detenção. A escolha final deve considerar a topografia, a proximidade de áreas habitadas, a segurança de crianças e pedestres, o acesso para limpeza e a compatibilidade com o uso do solo adjacente.

D2. Um roteiro completo inclui: delimitação da bacia contribuinte; levantamento topográfico; definição da chuva de projeto e da vazão afluente; escolha da vazão de saída admissível; obtenção do hidrograma; cálculo do volume de armazenamento; concepção da geometria; dimensionamento do dispositivo de saída; previsão de vertedor de emergência; análise de estabilidade geotécnica; avaliação de acessibilidade; e plano de operação e manutenção. Um bom projeto também deve prever inspeção após eventos extremos e remoção periódica de sedimentos.

4.13 Conexão com o próximo capítulo

Conexão com o próximo capítulo

Neste capítulo, o controle de cheia foi tratado por meio de bacias de detenção e retenção, que armazenam e liberam a água de forma regulada. No próximo capítulo, a lógica do controle será ainda mais distribuída e integrada ao ambiente urbano, por meio de jardins de chuva, biovaletas e pavimentos permeáveis. Essas soluções atuam na fonte, reduzem o escoamento superficial e aproximam o projeto de drenagem de uma abordagem sustentável e multifuncional.

Capítulo 5

Técnicas de drenagem sustentável e Soluções Baseadas na Natureza (SBN)

A drenagem urbana contemporânea não se limita a captar e transportar a água da chuva o mais rapidamente possível para jusante. Essa lógica, embora útil em certos contextos, frequentemente apenas transfere o problema hidrológico para outras áreas da cidade. As abordagens mais avançadas buscam reduzir a geração de escoamento na fonte, retardar o fluxo, aumentar a infiltração, melhorar a qualidade da água e integrar a infraestrutura ao espaço urbano. É nesse contexto que surgem a drenagem sustentável e as Soluções Baseadas na Natureza (SBN) (Tucci, 2008; Pompeo, 2000; Botelho, 2011; Canholi, 2014).

As SBN não são ornamentos paisagísticos adicionados ao projeto depois de pronto. Elas são, antes de tudo, dispositivos hidrológicos e ecológicos que atuam na escala do lote, da rua, da quadra e da microbacia. Jardins de chuva, biovaletas, pavimentos permeáveis, trincheiras de infiltração, telhados verdes e canteiros pluviais permitem que a cidade se aproxime do comportamento hidrológico de uma bacia mais natural, com mais armazenamento local, mais evapotranspiração, mais infiltração e menor pico de vazão.

Definição – Drenagem sustentável

Conjunto de estratégias de projeto, implantação e manutenção que buscam controlar a água pluvial com menor impacto hidrológico e ambiental, privilegiando a retenção na fonte, a infiltração, o retardamento do escoamento e a integração com o uso urbano do solo.

Definição – Soluções Baseadas na Natureza

Intervenções inspiradas e apoiadas em processos naturais, capazes de fornecer serviços ecossistêmicos, reduzir riscos hidrológicos e gerar co-benefícios ambientais, sociais e paisagísticos em áreas urbanas.

5.1 Objetivos de aprendizagem

Ao final deste capítulo, o estudante deverá ser capaz de:

- explicar a diferença entre drenagem convencional e drenagem sustentável;
- descrever o papel das Soluções Baseadas na Natureza no controle de cheias urbanas;

- reconhecer as principais técnicas de controle na fonte aplicáveis a lotes e vias;
- selecionar a solução mais adequada conforme solo, declividade, uso do terreno e manutenção disponível;
- realizar pré-dimensionamento simples de jardim de chuva, biovaleta, pavimento permeável e telhado verde;
- identificar limitações técnicas, riscos de falha e cuidados operacionais das SBN.

5.2 Da lógica de transporte à lógica de controle na fonte

A drenagem convencional foi historicamente orientada por uma lógica de rápida remoção da água. O objetivo principal era conduzir o excedente pluvial para fora da área urbana por meio de sarjetas, galerias, canais e lançamentos em corpos receptores. Esse modelo continua útil em muitos trechos da cidade, mas mostra limites claros em áreas densamente ocupadas, onde o aumento da impermeabilização torna a rede insuficiente ou financeiramente onerosa para expansão contínua.

A drenagem sustentável propõe uma mudança de paradigma. Em vez de concentrar toda a resposta no tubo ou no canal, ela distribui o controle ao longo do sistema. A água passa a ser tratada em múltiplas escalas:

- **na fonte,** com redução do escoamento gerado por cada superfície;
- **na parcela,** com dispositivos de infiltração e armazenamento;
- **na rua,** com elementos verdes de retenção e condução;
- **na bacia,** com integração entre microdrenagem, reservação e macrodrenagem.

Essa abordagem reduz a pressão sobre a rede principal, melhora a resiliência do sistema e permite benefícios adicionais, como sombreamento, conforto térmico, aumento da biodiversidade urbana e melhoria visual da paisagem.

Figura 5.1: Da lógica de transporte rápido para a lógica de controle distribuído na fonte.

A Figura 5.1 sintetiza a principal mudança de paradigma: a água deixa de ser apenas conduzida e passa a ser gerida em múltiplos pontos do sistema.

5.3 Princípios de projeto das SBN

Embora existam várias tecnologias específicas, todas as SBN de drenagem compartilham alguns princípios comuns.

Tabela 5.1: Princípios fundamentais das Soluções Baseadas na Natureza aplicadas à drenagem urbana.

Princípio	**Significado prático**
Controle na fonte	Reduzir a água pluvial antes que ela se torne excesso concentrado na rede
Retenção temporária	Armazenar volume por um intervalo suficiente para reduzir o pico de vazão
Infiltração seletiva	Permitir a entrada no solo quando a qualidade da água e o solo local forem adequados
Evapotranspiração	Incorporar vegetação para devolver parte da água à atmosfera e melhorar o microclima
Redundância hidráulica	Criar múltiplos caminhos seguros para a água, inclusive por extravasor
Pré-tratamento	Remover sedimentos e detritos antes da chegada ao dispositivo principal
Manutenção acessível	Garantir que a solução possa ser inspecionada, limpa e reparada com frequência razoável
Integração urbana	Associar a função hidráulica a uso paisagístico, ambiental e social

Do ponto de vista hidrológico, essas soluções reduzem o escoamento superficial por ao menos três mecanismos:

- aumento do armazenamento temporário;
- aumento da infiltração e da recarga local, quando permitido;
- aumento do tempo de resposta da microbacia.

Do ponto de vista urbano, acrescentam ainda benefícios como redução da temperatura superficial, melhoria da caminhabilidade, ampliação de áreas verdes e melhoria da qualidade de vida.

5.4 Principais técnicas de drenagem sustentável

As técnicas de drenagem sustentável podem ser organizadas em grupos. Neste capítulo, o foco recai sobre as soluções mais usuais em projetos urbanos de pequena e média escala: jardins de chuva, biovaletas, pavimentos permeáveis e telhados verdes. Também serão mencionadas trincheiras de infiltração e canteiros pluviais, que frequentemente funcionam como complementos.

5.4.1 Jardins de chuva

Definição – Jardim de chuva

Depressão vegetada projetada para receber, armazenar temporariamente e infiltrar a água da chuva proveniente de áreas impermeáveis adjacentes, com ou sem drenagem subsuperficial.

O jardim de chuva é uma das soluções mais versáteis das SBN. Ele pode ser implantado em quintais, canteiros, praças, estacionamentos e margens de vias, desde que o solo e o nível freático sejam compatíveis. Sua função principal é receber o escoamento de telhados, calçadas ou pequenas áreas pavimentadas e reduzi-lo por armazenamento e infiltração.

Um jardim de chuva normalmente possui:

- área de contribuição impermeável;
- faixa de entrada ou dispositivo de captação;
- camada superficial vegetada e cobertura morta;
- solo de biorretenção ou substrato filtrante;
- eventual dreno de fundo;
- extravasor seguro para eventos mais intensos.

O desempenho hidráulico depende da profundidade útil de armazenamento, da porosidade do substrato, da infiltração do solo subjacente e da área disponível para esvaziamento entre chuvas.

5.4.2 Biovaletas

Definição – Biovaleta

Canal ou vala vegetada, geralmente com seção trapezoidal ou suavemente rebaixada, destinada a transportar água pluvial com velocidade reduzida, promovendo infiltração, retenção de sedimentos e melhoria da qualidade da água.

A biovaleta funciona, ao mesmo tempo, como conduto e como unidade de tratamento. É especialmente útil ao longo de ruas, estacionamentos, canteiros centrais e faixas laterais de vias. Sua principal vantagem é combinar transporte controlado com retenção local de água e sedimentos.

Em comparação com uma sarjeta convencional, a biovaleta:

- reduz a velocidade do escoamento;
- aumenta o tempo de residência da água;
- melhora a remoção de sólidos e contaminantes associados;

- suaviza a paisagem urbana;
- pode servir como elemento linear de conexão entre dispositivos.

5.4.3 Pavimentos permeáveis

Definição – Pavimento permeável

Sistema de revestimento superficial projetado para permitir a passagem de parte da água pluvial para camadas inferiores, onde ela pode ser armazenada temporariamente, infiltrada ou drenada de forma controlada.

Os pavimentos permeáveis podem ser executados com blocos intertravados com juntas abertas, concreto permeável, asfalto poroso ou sistemas modulares específicos. Em todos os casos, a lógica é semelhante: a água atravessa a superfície e é temporariamente armazenada em uma camada granular de base ou sub-base, com posterior infiltração ou drenagem.

Esse tipo de solução é muito adequado para:

- calçadas de baixo tráfego;
- estacionamentos;
- áreas de circulação leve;
- pátios institucionais;
- vias locais com controle de carga e manutenção adequados.

A principal limitação dos pavimentos permeáveis é a perda de desempenho quando há entupimento por finos, poeira, sedimentos e matéria orgânica. Assim, sua durabilidade depende de projeto, instalação e manutenção cuidadosos.

5.4.4 Telhados verdes

Definição – Telhado verde

Sistema de cobertura vegetada implantado sobre lajes ou coberturas, capaz de reter parte da chuva, retardar o escoamento e contribuir para o conforto térmico e a melhoria do microclima.

Os telhados verdes reduzem o volume e o pico de vazão gerado pelas coberturas, além de trazerem benefícios térmicos, estéticos e ecológicos. Em geral, compõem-se de impermeabilização, camada de drenagem, substrato e vegetação. Sua contribuição hidráulica depende do tipo de cobertura, da espessura do substrato e da frequência das chuvas.

5.4.5 Trincheiras de infiltração e canteiros pluviais

As trincheiras de infiltração são valas preenchidas com material granular, às vezes dotadas de geotêxtil e dreno, cuja função principal é receber água, armazenar temporariamente e permitir

percolação ao solo. Os canteiros pluviais atuam de forma muito semelhante aos jardins de chuva, mas com ênfase urbana e ornamental maior.

Essas soluções são úteis quando o espaço é limitado, mas a cidade ainda dispõe de pequenas faixas livres, canteiros e recuos capazes de receber volumes moderados.

5.4.6 Comparação entre técnicas

Tabela 5.2: Comparação entre técnicas usuais de drenagem sustentável.

Técnica	Função predominante	Melhor aplicação	Limitações comuns
Jardim de chuva	Armazenar, infiltrar e tratar o escoamento superficial	Lotes residenciais, praças, recuos e áreas ajardinadas	Necessita solo compatível, manutenção da vegetação e controle de extravasamento
Biovaleta	Conduzir água com baixa velocidade, retendo sedimentos	Laterais de vias, estacionamentos, corredores verdes e canteiros centrais	Sensível a assoreamento e a altas declividades
Pavimento permeável	Captar e armazenar água em camadas inferiores	Calçadas, estacionamentos e áreas de circulação leve	Entupimento por finos, exigência de manutenção e controle de cargas
Trincheira de infiltração	Armazenar e infiltrar em faixa estreita	Faixas laterais e áreas com restrição de espaço	Depende muito da permeabilidade do solo e do nível freático
Telhado verde	Reter parte da chuva na cobertura e retardar o escoamento	Edificações com capacidade estrutural adequada	Custo inicial, peso adicional e necessidade de manutenção vegetada
Canteiro pluvial	Integrar captação e paisagismo urbano	Áreas públicas e institucionais	Requer desenho paisagístico e manutenção contínua

5.5 Critérios de seleção do local

Nem toda solução serve para qualquer sítio. A seleção correta depende de condições hidrológicas, geotécnicas, urbanísticas e operacionais.

De forma geral, algumas recomendações práticas são particularmente importantes:

- evitar infiltração direta em locais com contaminação conhecida do solo;
- prever extravasor em qualquer solução, mesmo quando a intenção principal for infiltrar;
- verificar se o sistema esvazia em tempo compatível com o uso urbano;

Tabela 5.3: Critérios preliminares para escolha de técnicas de drenagem sustentável.

Critério	Observação técnica
Permeabilidade do solo	Solos muito argilosos tendem a exigir dreno de fundo ou adoção preferencial de retenção e não de infiltração pura
Nível freático	Nível d'água muito alto reduz a capacidade de infiltração e aumenta riscos de saturação
Declividade do terreno	Declividades elevadas favorecem erosão, demandando terraceamento, contenção ou biovaletas mais curtas
Qualidade da água afluente	Áreas com maior carga de sedimentos e contaminantes exigem pré-tratamento e inspeção
Espaço disponível	Algumas técnicas precisam de área horizontal; outras podem ser lineares ou subterrâneas
Carga de tráfego	Pavimentos permeáveis devem ser compatíveis com o tipo e a intensidade do tráfego
Capacidade estrutural	Telhados verdes exigem verificação da resistência da laje ou cobertura
Acessibilidade de manutenção	A solução deve permitir limpeza, reposição de vegetação, remoção de sedimentos e inspeção periódica
Proteção de fundações e redes	Deve haver compatibilidade com edificações, subsolos, tubulações e estruturas adjacentes

- considerar a manutenção como parte integrante do projeto, e não como etapa posterior opcional;
- adotar pré-tratamento quando houver risco de acúmulo de sedimentos, folhas e lixo;
- compatibilizar o paisagismo com o objetivo hidráulico, sem comprometer a função principal.

5.6 Pré-dimensionamento hidrológico e hidráulico

O projeto preliminar de uma SBN começa pela quantificação do volume a ser manejado. Em termos simples, o volume de escoamento superficial pode ser estimado por:

$$V = 10\,C\,P\,A$$

em que:

- V é o volume em m^3;
- C é o coeficiente de escoamento;
- P é a chuva de projeto em mm;
- A é a área contribuinte em ha.

Esse volume pode ser distribuído entre diferentes técnicas. Em vez de concentrar tudo em uma única estrutura, é muitas vezes preferível dividir o controle entre pavimentos permeáveis, jardins de chuva, biovaletas e telhados verdes.

5.6.1 Jardim de chuva: área necessária

Para um jardim de chuva, a capacidade útil preliminar pode ser representada por:

$$V_u = A_j \, d_u$$

em que:

- V_u é o volume útil de armazenamento;
- A_j é a área do jardim;
- d_u é a profundidade útil equivalente de armazenamento.

Logo, a área necessária é:

$$A_j = \frac{V_u}{d_u}$$

Em projeto preliminar, d_u costuma ser escolhido com base na profundidade de empoçamento e na capacidade de armazenamento do substrato, de modo compatível com a vegetação e a segurança do uso. O valor deve sempre ser ajustado às condições locais.

5.6.2 Tempo de esvaziamento

Uma forma simples de verificar a viabilidade hidráulica é estimar o tempo de esvaziamento:

$$t_d = \frac{V_u}{k_s A_{\text{inf}}}$$

em que:

- t_d é o tempo de drenagem;
- k_s é a condutividade hidráulica saturada do solo ou do substrato;
- A_{inf} é a área infiltrante disponível.

Em termos práticos, a solução deve ser capaz de esvaziar entre eventos de chuva, evitando saturação prolongada. Se a água permanece acumulada por tempo excessivo, a eficiência hidráulica e a segurança operacional diminuem.

5.6.3 Biovaleta: verificação hidráulica

Uma biovaleta pode ser analisada, em primeira aproximação, como um canal trapezoidal. Para uma seção com largura de fundo b, profundidade y e taludes $z : 1$, a área molhada é:

$$A = by + zy^2$$

e o perímetro molhado é:

$$P = b + 2y\sqrt{1 + z^2}$$

O raio hidráulico é:

$$R = \frac{A}{P}$$

e a vazão pode ser estimada pela equação de Manning:

$$Q = \frac{1}{n} A R^{2/3} S^{1/2}$$

em que n é a rugosidade e S é a declividade longitudinal.

5.6.4 Pavimento permeável: armazenamento em base granular

Para pavimentos permeáveis, o volume de armazenamento temporário na base granular pode ser estimado por:

$$V_p = A_p \, h_r \, n_v$$

em que:

- V_p é o volume armazenado;
- A_p é a área do pavimento;
- h_r é a espessura da camada reservatório;
- n_v é o índice de vazios da camada granular.

Essa formulação é muito útil em pré-dimensionamento, pois permite verificar rapidamente se a área de pavimento permeável disponível é suficiente para armazenar o volume gerado na área atendida.

5.6.5 Telhado verde: retenção simplificada

O desempenho hidráulico de um telhado verde pode ser expressado, em nível simplificado, por:

$$V_t = A_t \, d_e$$

em que:

- V_t é o volume retido ou temporariamente armazenado;

- A_t é a área da cobertura;
- d_e é a profundidade equivalente de retenção do sistema.

Embora esse valor varie muito com o tipo de vegetação, espessura do substrato e umidade antecedente, ele ajuda a comparar cenários de forma didática.

5.7 Exemplo integrado de projeto em lote urbano

Considere um lote urbano residencial com 600 m^2 de área total, dividido da seguinte forma:

- 220 m^2 de cobertura de telhado, com $C = 0{,}90$;
- 150 m^2 de acesso e garagem, com $C = 0{,}80$;
- 230 m^2 de jardim e solo vegetado, com $C = 0{,}25$.

Adote chuva de projeto de 30 mm.

1. Cálculo do volume total de escoamento

O coeficiente ponderado é:

$$C_m = \frac{220 \times 0.90 + 150 \times 0.80 + 230 \times 0.25}{600}$$

$$C_m = \frac{198 + 120 + 57.5}{600} = 0{,}6258$$

Como a área total corresponde a 0,06 ha, o volume de escoamento é:

$$V = 10 \times 0.6258 \times 30 \times 0.06$$

$$V \approx 11{,}26\,\text{m}^3$$

Logo, o lote produz aproximadamente 11,26 m^3 de escoamento para o evento adotado.

2. Pavimento permeável na garagem

Suponha que 80 m^2 da garagem sejam executados com pavimento permeável, com camada reservatório de 0,20 m e índice de vazios $n_v = 0{,}35$.

$$V_p = 80 \times 0.20 \times 0.35$$

$$V_p = 5{,}60\,\text{m}^3$$

3. Jardim de chuva no quintal

Para complementar o sistema, adote um jardim de chuva com 32 m^2 e profundidade útil de 0,20 m.

$$V_j = 32 \times 0.20 = 6{,}40\,\mathrm{m}^3$$

4. Telhado verde parcial

Considere 120 m^2 de telhado verde com retenção equivalente média de 0,015 m.

$$V_t = 120 \times 0.015 = 1{,}80\,\mathrm{m}^3$$

5. Verificação do balanço

A capacidade total aproximada fica:

$$V_{\text{total}} = V_p + V_j + V_t = 5.60 + 6.40 + 1.80 = 13{,}80\,\mathrm{m}^3$$

Como $V_{\text{total}} > V$, o arranjo proposto é suficiente, em primeira aproximação, para manejar o evento de projeto. Ainda assim, o sistema deve incluir extravasor para eventos mais severos e deve ser confirmado por análise do solo e do detalhamento construtivo.

6. Verificação de esvaziamento do jardim

Admitindo condutividade hidráulica saturada do solo de 15 mm/h para o jardim de chuva, a capacidade de infiltração é:

$$q = 0.015 \times 32 = 0{,}48\,\mathrm{m}^3/\mathrm{h}$$

O tempo de esvaziamento estimado é:

$$t_d = \frac{6.40}{0.48} \approx 13{,}3\,\mathrm{h}$$

Esse valor é tecnicamente aceitável em muitos contextos urbanos, pois permite a drenagem entre eventos de chuva e evita saturação prolongada.

7. Interpretação do arranjo

O exemplo mostra que soluções distribuídas podem substituir, em parte, a necessidade de ampliar rapidamente a rede de drenagem convencional. Em vez de concentrar o controle em uma única estrutura de grande porte, o lote passa a reter parte da água no pavimento, parte no jardim, parte no telhado e parte na vegetação, diminuindo o pico enviado à rua.

5.8 Operação, manutenção e falhas comuns

Como qualquer infraestrutura urbana, as SBN dependem de operação e manutenção. A maior parte das falhas não decorre da ideia em si, mas da perda gradual de desempenho por sedimentação, compactação, obstrução ou ausência de manejo.

- **Jardins de chuva:** podem perder capacidade por compactação do solo, colmatação superficial, excesso de matéria orgânica ou falha da vegetação.
- **Biovaletas:** tendem a assorear se não houver pré-tratamento e limpeza periódica.
- **Pavimentos permeáveis:** perdem desempenho com poeira, areia, finos e tráfego inadequado.
- **Trincheiras de infiltração:** podem saturar ou colmatar se a água não for pré-tratada.
- **Telhados verdes:** exigem inspeção da cobertura, irrigação em períodos secos e controle de espécies vegetais.

As medidas de manutenção mais importantes incluem:

- inspeção após eventos intensos;
- remoção de sedimentos e resíduos sólidos;
- substituição ou renovação de cobertura morta;
- replantio de espécies vegetais quando necessário;
- varrição ou aspiração de pavimentos permeáveis;
- checagem do extravasor e das condições de drenagem de fundo.

A existência de um plano de manutenção é tão importante quanto o dimensionamento hidráulico. Sem isso, a solução perde eficiência e pode se transformar em um problema de funcionamento.

5.9 Erros frequentes em projetos

- tratar SBN como decoração sem função hidráulica;
- aplicar infiltração em solos ou locais incompatíveis;
- não prever extravasor ou caminho seguro de excedente;
- ignorar a necessidade de pré-tratamento;
- subestimar a colmatação dos pavimentos permeáveis;
- projetar jardins de chuva muito profundos sem considerar segurança e drenagem;

- escolher biovaletas em declives excessivos sem controle de erosão;
- esquecer que a manutenção é parte do desempenho do sistema;
- ignorar a capacidade estrutural necessária para telhados verdes.

5.10 Resumo do capítulo

Resumo do capítulo

A drenagem sustentável desloca o foco do transporte rápido da água para o controle distribuído na fonte, com retenção temporária, infiltração, evapotranspiração e integração urbana.

As Soluções Baseadas na Natureza proporcionam benefícios hidrológicos, ecológicos, paisagísticos e térmicos, além de reduzir o pico de vazão e a pressão sobre a rede convencional.

Jardins de chuva, biovaletas, pavimentos permeáveis e telhados verdes são técnicas centrais para lotes, ruas e áreas de uso urbano leve.

A escolha da técnica depende de solo, nível freático, declividade, carga de tráfego, espaço disponível, capacidade estrutural e manutenção.

O pré-dimensionamento pode ser feito com base no volume de escoamento, na área útil de armazenamento, no tempo de esvaziamento e na capacidade de infiltração ou retenção estrutural.

No exemplo do lote residencial, o uso combinado de pavimento permeável, jardim de chuva e telhado verde foi suficiente para manejar o volume estimado de 11,26 m^3.

No próximo capítulo, a drenagem urbana será tratada em escala de planejamento e gestão, com o Plano Diretor de Drenagem Urbana, o mapeamento de áreas de risco e os sistemas de alerta para inundação.

5.11 Exercícios

Exercício F1

Defina drenagem sustentável e explique por que ela é diferente da drenagem convencional baseada apenas em canalização e transporte.

Exercício F2

Explique a função hidrológica de um jardim de chuva e de uma biovaleta.

Exercício F3

Cite duas vantagens e duas limitações dos pavimentos permeáveis.

Exercício F4

Explique a contribuição hidráulica de um telhado verde em um sistema urbano de drenagem.

Exercício M1

Para o lote do exemplo, com área total de 600 m^2 e coeficiente ponderado $C_m = 0{,}6258$, calcule o volume de escoamento gerado por uma chuva de 30 mm.

Exercício M2

Se o jardim de chuva do exemplo tiver 32 m^2 e profundidade útil de 0,20 m, determine seu volume de armazenamento. Em seguida, compare com o volume de escoamento total calculado no exercício M1.

Exercício M3

Para o pavimento permeável do exemplo, com área de 80 m^2, camada reservatório de 0,20 m e índice de vazios $n_v = 0{,}35$, calcule o volume armazenável.

Exercício M4

Admitindo condutividade hidráulica saturada de 15 mm/h para o solo do jardim de chuva do exemplo, determine a vazão de infiltração e o tempo estimado de esvaziamento para um volume de 6,40 m^3.

Exercício D1

Proponha um pacote integrado de SBN para uma escola de ensino fundamental localizada em bairro urbano adensado. Considere telhado, pátio, acesso de veículos, segurança de crianças, manutenção e aproveitamento paisagístico.

Exercício D2

Uma área urbana possui solo argiloso, lençol freático relativamente alto e grande produção de sedimentos nas vias adjacentes. Discuta quais SBN são mais adequadas, quais devem ser evitadas e quais medidas de pré-tratamento são indispensáveis.

5.12 Gabarito comentado

Gabarito comentado

F1. Drenagem sustentável é o conjunto de estratégias que busca controlar a água da chuva com retenção na fonte, infiltração, retardamento e integração ao ambiente urbano. Ela difere da drenagem convencional porque não depende apenas de capturar e transportar rapidamente a água; ela procura reduzir o escoamento gerado e distribuir o controle em múltiplos pontos do sistema.

F2. O jardim de chuva armazena e infiltra água em uma depressão vegetada, reduzindo volume e pico de escoamento. A biovaleta conduz a água de maneira lenta e vegetada, ao mesmo tempo em que retém sedimentos e melhora a qualidade da água. Ambos atuam na escala da rua e da parcela, com forte componente paisagístico e hidráulico.

F3. Vantagens: redução do escoamento superficial e armazenamento temporário de água; conforto térmico e integração urbana. Limitações: colmatação por finos e necessidade de manutenção; restrições de carga e sensibilidade ao tráfego intenso. Outros pontos válidos incluem custo inicial e dependência de limpeza periódica.

F4. O telhado verde retém parte da chuva na cobertura, reduzindo o volume de escoamento direto e atrasando sua chegada à rede. Além do efeito hidráulico, contribui para redução da temperatura superficial, melhora do microclima e aumento da área vegetada em ambiente urbano.

M1. O volume é:

$$V = 10 \times 0.6258 \times 30 \times 0.06$$

$$V \approx 11{,}26\,\mathrm{m}^3$$

O lote gera aproximadamente 11,26 m^3 de escoamento para a chuva adotada.

M2. O volume do jardim é:

$$V_j = 32 \times 0.20 = 6{,}40\,\mathrm{m}^3$$

Comparando com 11,26 m^3, o jardim sozinho não absorveria todo o volume. Ele cobriria cerca de 57 % da demanda, devendo ser complementado por outra solução, como pavimento permeável, telhado verde ou trincheira de infiltração.

M3. O volume armazenável no pavimento permeável é:

$$V_p = 80 \times 0.20 \times 0.35 = 5{,}60\,\mathrm{m}^3$$

Esse valor representa o armazenamento temporário da camada granular, sem considerar eventual infiltração para o subleito ou drenagem por subdreno.

M4. A vazão de infiltração é:

$$q = 0.015 \times 32 = 0{,}48\,\mathrm{m}^3/\mathrm{h}$$

O tempo de esvaziamento é:

$$t_d = \frac{6.40}{0.48} \approx 13{,}3\,\mathrm{h}$$

Esse tempo é, em geral, compatível com uma solução de biorretenção, desde que a drenagem ocorra entre eventos e que o solo não apresente saturação prolongada.

D1. Em uma escola, o ideal costuma ser combinar soluções de baixa profundidade e alta segurança: pavimento permeável em áreas de circulação leve, jardim de chuva em canteiros afastados da movimentação intensa e biovaletas em perímetros ou faixas laterais. É importante evitar lâminas profundas em locais de circulação infantil, prever extravasamento seguro e garantir manutenção simples. A solução deve ser pedagógica, segura e visualmente integrada ao espaço escolar.

D2. Em solo argiloso e com lençol freático alto, a infiltração pura tende a ter desempenho limitado e maior risco de saturação. Nesse caso, podem ser mais adequados jardins de chuva com drenagem de fundo, biovaletas com extravasor, canteiros pluviais e pavimentos permeáveis com subdreno, desde que haja manutenção. Devem ser evitadas trincheiras profundas de infiltração sem controle. O pré-tratamento é indispensável: caixas de areia, faixas vegetadas, retenção de grossos e limpeza periódica das entradas são medidas essenciais para evitar colmatação.

5.13 Conexão com o próximo capítulo

Conexão com o próximo capítulo

Este capítulo apresentou a drenagem sustentável como uma mudança de paradigma: da remoção rápida da água para o controle distribuído na fonte, com apoio de processos naturais e múltiplos benefícios urbanos. No próximo capítulo, essa visão será incorporada ao planejamento público por meio do Plano Diretor de Drenagem Urbana, do mapeamento de áreas de risco e dos sistemas de alerta para inundações. Assim, o livro avançará da solução local para a gestão integrada em escala de cidade.

Capítulo 6

Plano Diretor de Drenagem Urbana, mapeamento de áreas de risco e alertas de inundação

Até aqui, o livro percorreu a lógica completa da drenagem urbana em escala de projeto: compreendeu-se o comportamento hidrológico da cidade, quantificou-se a vazão de pico, dimensionaram-se sarjetas, bocas-de-lobo, coletores, reservatórios e técnicas de drenagem sustentável. Falta agora o passo que transforma soluções isoladas em política pública consistente: o planejamento sistêmico.

O **Plano Diretor de Drenagem Urbana** é o instrumento que organiza diagnósticos, prioridades, intervenções, responsabilidades, prazos e mecanismos de monitoramento. Ele conecta engenharia, uso do solo, defesa civil, saneamento, meio ambiente e gestão de riscos. Sem esse elo, as obras tendem a ser reativas, fragmentadas e pouco duráveis (Tucci, 2008; Canholi, 2014; Brasil, 2013).

Este capítulo fecha a parte central do livro com uma abordagem sistêmica. O foco é mostrar como mapear áreas de risco, hierarquizar ações e estruturar sistemas de alerta para inundação de forma tecnicamente sólida e operacionalmente viável.

Definição – Plano Diretor de Drenagem Urbana

Instrumento técnico e gerencial que orienta o diagnóstico, o planejamento, a priorização, a implantação, a operação e a revisão das ações de drenagem urbana em uma bacia ou município, articulando controle de cheias, uso do solo, risco hidrológico e manutenção da infraestrutura.

6.1 Objetivos de aprendizagem

Ao final deste capítulo, o estudante deverá ser capaz de:

- explicar a finalidade de um Plano Diretor de Drenagem Urbana;
- reconhecer as etapas de elaboração de um PDDU;
- diferenciar perigo, exposição, vulnerabilidade e risco em inundação urbana;

- estruturar um mapeamento de áreas críticas e áreas de risco;
- propor um sistema básico de alerta e resposta para eventos de chuva intensa;
- hierarquizar intervenções estruturais e não estruturais;
- definir indicadores de acompanhamento e revisão do plano.

6.2 Por que a drenagem precisa de planejamento diretor

A drenagem urbana não pode ser tratada apenas como um conjunto de obras pontuais. A ampliação isolada de galerias, canais ou bacias de detenção pode aliviar um ponto e agravar outro se não houver visão de bacia. Além disso, a cidade muda rapidamente: novos loteamentos surgem, áreas impermeáveis aumentam, fundos de vale são ocupados, canais são assoreados e a rede envelhece.

O Plano Diretor de Drenagem Urbana existe justamente para evitar respostas improvisadas. Ele permite:

- identificar as causas estruturais dos alagamentos;
- definir prioridades com base em risco e criticidade;
- orientar investimentos por etapas;
- integrar drenagem com saneamento, mobilidade e uso do solo;
- reduzir danos recorrentes com medidas de prevenção e não apenas de remediação;
- estabelecer critérios claros para manutenção e operação;
- vincular obras, regulamentos e monitoramento a metas mensuráveis.

Definição – Drenagem urbana como sistema

Conjunto integrado de elementos naturais, físicos, operacionais e institucionais que controlam a produção, a condução, o armazenamento e o lançamento das águas pluviais em áreas urbanas.

A drenagem só funciona de forma robusta quando é entendida como sistema. Isso inclui desde o telhado e a calha até a planície de inundação, desde o cadastro das galerias até os protocolos de evacuação em eventos extremos.

6.3 Princípios orientadores de um PDDU

Um plano diretor bem elaborado deve observar alguns princípios fundamentais.

Esses princípios evitam uma visão excessivamente centrada na obra física. Em drenagem urbana, o desempenho de longo prazo depende igualmente da governança, da manutenção e da capacidade de responder a eventos extremos.

Tabela 6.1: Princípios técnicos e institucionais de um Plano Diretor de Drenagem Urbana.

Princípio	Aplicação prática
Abordagem por bacia hidrográfica	O planejamento deve considerar a dinâmica da drenagem na unidade de contribuição e não apenas limites administrativos
Prevenção antes da correção	Priorizar ações que evitem a geração do problema em vez de apenas reagir aos danos
Hierarquização de risco	Direcionar recursos primeiro às áreas com maior frequência, maior impacto e maior vulnerabilidade
Integração institucional	Articular prefeitura, defesa civil, limpeza urbana, saneamento, obras e planejamento territorial
Manutenção como parte do sistema	Prever operação e conservação contínuas como condição de desempenho
Flexibilidade e atualização	Ajustar o plano à expansão urbana, à mudança climática e ao monitoramento de campo
Soluções múltiplas e complementares	Combinar obras convencionais, SBN, medidas operacionais e instrumentos de uso do solo
Transparência e participação	Incorporar informação pública, comunicação de risco e participação social

6.4 Etapas de elaboração do PDDU

Um PDDU consistente costuma ser desenvolvido em etapas encadeadas. A Figura 6.1 resume esse processo.

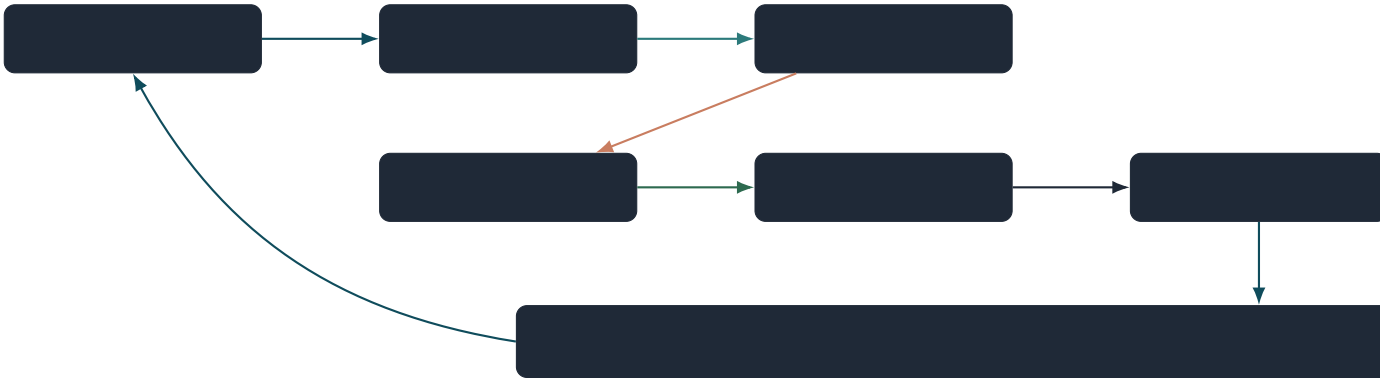

Figura 6.1: Ciclo básico de elaboração, implantação e revisão de um Plano Diretor de Drenagem Urbana.

O ciclo da Figura 6.1 mostra que o plano não termina no relatório. Ele precisa ser implantado, acompanhado e atualizado. Um plano sem monitoramento tende a se tornar obsoleto diante da própria dinâmica urbana.

6.4.1 1. Diagnóstico

O diagnóstico identifica como a drenagem funciona hoje, onde falha e por quê. Essa etapa reúne dados físicos, operacionais, territoriais e sociais.

Os principais componentes do diagnóstico são:

- delimitação das bacias e sub-bacias;
- topografia e declividades;
- uso e ocupação do solo;
- taxas de impermeabilização;
- cadastro da rede existente;
- pontos de alagamento e recorrência;
- histórico de eventos extremos;
- condicionantes geotécnicas e hidrológicas;
- áreas ambientalmente sensíveis;
- vulnerabilidade social e presença de equipamentos críticos.

6.4.2 2. Prognóstico

O prognóstico responde à pergunta: o que acontecerá se nada for feito? Nessa fase, são simulados cenários de crescimento urbano, aumento de impermeabilização, expansão da rede, clima futuro e ocupação de áreas hoje pouco adensadas.

Essa etapa é essencial porque o problema de drenagem não é estático. Um bairro que hoje ainda é funcional pode tornar-se crítico após novas construções, redução de permeabilidade e obstrução progressiva da rede.

6.4.3 3. Alternativas

Com base no diagnóstico e no prognóstico, são comparadas alternativas de solução. Elas podem incluir:

- ampliação de galerias e canais;
- implantação de reservatórios de detenção;
- soluções baseadas na natureza;
- reconfiguração de sarjetas e bocas-de-lobo;
- recuperação de fundos de vale;
- restrição de ocupação em áreas inundáveis;
- programas de manutenção intensiva;
- melhorias em limpeza urbana e controle de resíduos;
- sistemas de alerta e proteção civil.

A melhor alternativa nem sempre é a mais barata no curto prazo. É aquela que apresenta melhor relação entre risco reduzido, custo total, manutenção e benefício social.

6.4.4 4. Priorização

Nem toda intervenção pode ser executada ao mesmo tempo. O plano precisa ordenar prioridades por critérios como:

- número de pessoas afetadas;
- frequência dos eventos;
- severidade dos danos;
- custo de implantação;
- facilidade de execução;
- prazo de maturação do benefício;
- sinergia com outras obras urbanas;
- possibilidade de redução de risco com ações imediatas.

6.4.5 5. Implementação

A implementação converte o plano em programas, projetos e obras. Aqui é importante estabelecer responsabilidades, fontes de financiamento, cronograma, licenciamento, etapas de contratação e compatibilização com demais intervenções urbanas.

6.4.6 6. Monitoramento e revisão

A etapa final é o monitoramento. Sem indicadores, não há como saber se o plano está funcionando. Sem revisão, não há como incorporar mudanças no território e no clima.

6.5 Dados necessários para um bom plano

Um PDDU bem estruturado depende de bases de dados confiáveis. A Tabela 6.2 resume os principais grupos de informação.

6.5.1 Cadastro técnico e campo

Não basta trabalhar com mapas. O cadastro em campo é indispensável para verificar:

- obstruções reais;
- ligações clandestinas;
- deformações e recalques;
- bocas-de-lobo assoreadas;

Tabela 6.2: Principais dados utilizados na elaboração de um PDDU.

Grupo de dados	**Exemplos**	**Uso no plano**
Topografia e relevo	MDT, curvas de nível, seções, declividades, fundos de vale	Delimitação de bacias, caminhos preferenciais de escoamento e pontos baixos
Hidrologia e chuva	Séries pluviométricas, curvas IDF, eventos históricos, vazões observadas	Cálculo de vazões de projeto e análise de recorrência
Rede de drenagem	Galerias, canais, bocas-de-lobo, poços de visita, extravasores	Verificação de capacidade, obstrução e continuidade hidráulica
Uso do solo	Telhados, pavimentos, lotes, áreas verdes, glebas vazias	Estimativa de impermeabilização e geração de escoamento
Solo e geotecnia	Permeabilidade, lençol freático, erosão, estabilidade	Avaliação de infiltração, reservação e segurança estrutural
Histórico de ocorrências	Registros de alagamento, danos, reclamações, ocorrências da defesa civil	Identificação de pontos críticos e recorrência de problemas
Vulnerabilidade social	População exposta, renda, idade, mobilidade reduzida, moradia precária	Priorização de áreas de maior risco humano
Infraestrutura crítica	Escolas, hospitais, vias arteriais, estações de bombeamento, abrigo de emergência	Definição de criticidade e resposta prioritária

- descargas inadequadas;
- erosões de entrada e saída;
- pontos de refluxo e retorno;
- incompatibilidades entre projeto e execução.

Muitas falhas de drenagem aparecem apenas depois de uma vistoria detalhada. Por isso, o plano precisa combinar base cartográfica, modelagem e inspeção local.

6.6 Mapeamento de áreas de risco

Um dos produtos mais importantes do PDDU é o mapeamento de áreas de risco. É importante distinguir três conceitos:

Definição – Perigo

Probabilidade de ocorrência de um fenômeno capaz de produzir danos, como chuva intensa, cheia, transbordamento ou enxurrada.

Definição – Exposição

Presença de pessoas, edificações, infraestrutura, bens ou atividades em área sujeita ao fenômeno perigoso.

Definição – Vulnerabilidade

Grau de suscetibilidade de pessoas ou sistemas a sofrer danos quando expostos ao perigo.

Definição – Risco

Combinação entre perigo, exposição e vulnerabilidade. Em forma conceitual, pode ser representado por:

$$R = H \times E \times V$$

em que H representa o perigo, E a exposição e V a vulnerabilidade.

O risco não é apenas hidráulico. Duas áreas com a mesma lâmina d'água podem apresentar riscos muito diferentes se uma delas possuir escola, hospital, população idosa ou moradias mais frágeis.

6.6.1 Camadas cartográficas do risco

O mapeamento de áreas de risco costuma integrar camadas temáticas distintas.

6.6.2 Classificação simplificada de risco

Em um plano preliminar, pode-se organizar o risco em três classes operacionais:

Tabela 6.3: Camadas usuais de um mapa de risco de inundação urbana.

Camada	**Finalidade**
Modelo digital do terreno	Identificar depressões, talvegues, linhas de fluxo e áreas de acúmulo
Uso e cobertura do solo	Localizar superfícies impermeáveis, áreas verdes e ocupações sensíveis
Rede de drenagem	Verificar continuidade hidráulica, gargalos e pontos de extravasamento
Histórico de alagamentos	Confirmar recorrência espacial e temporal dos eventos
População vulnerável	Priorizar áreas com maior suscetibilidade humana ao dano
Infraestrutura crítica	Proteger serviços essenciais e rotas de evacuação
Imagem de campo e vistorias	Validar a interpretação cartográfica e reduzir erro de leitura

Tabela 6.4: Classificação simplificada de risco para priorização preliminar.

Classe	**Descrição**	**Resposta típica**
Baixo	Baixa frequência, danos limitados, boa capacidade de resposta local	Monitoramento e manutenção rotineira
Médio	Ocorrências intermitentes, danos moderados, necessidade de intervenção pontual	Melhorias de microdrenagem, limpeza e sinalização
Alto	Alta recorrência, danos expressivos ou população exposta de forma crítica	Obras prioritárias, alerta, restrição de uso e ações estruturais e não estruturais

Se for desejável maior refinamento, o plano pode usar escalas numéricas de 1 a 5 para perigo, exposição e vulnerabilidade, com posterior soma, média ponderada ou matriz de priorização. O importante é que o método escolhido seja transparente e repetível.

6.6.3 Exemplo de índice de triagem

Suponha três subáreas com notas de 1 a 5:

$$I_R = \frac{H + E + V}{3}$$

Essa expressão não substitui uma modelagem hidrológica completa, mas ajuda a ordenar prioridades quando o objetivo é triagem inicial.

6.7 Sistema de alerta de inundação

O mapeamento de risco é apenas uma parte da proteção. Em locais sujeitos a eventos recorrentes, o plano deve incluir um sistema de alerta e resposta. O objetivo é reduzir danos antes que a cheia atinja seu ponto máximo.

6.7.1 Componentes do sistema de alerta

Um sistema básico de alerta costuma envolver:

- pluviômetros automáticos ou semiautomáticos;
- sensores de nível em canais, córregos ou estruturas de retenção;
- limiares de atenção, alerta e emergência;
- comunicação rápida com defesa civil e equipes operacionais;
- protocolo de fechamento de vias e remoção de pessoas;
- canais de comunicação com a população;
- base de dados para registro de ocorrência e revisão do sistema.

6.7.2 Níveis operacionais

Os níveis operacionais devem ser definidos localmente, com base em séries históricas, respostas hidrológicas e vulnerabilidade da área.

Em áreas com forte recorrência de inundação, o protocolo deve ser simples, rápido e conhecido antes do evento. O alerta que chega tarde perde valor operacional.

6.7.3 Comunicação de risco

A comunicação com a população deve ser clara, objetiva e padronizada. Ela precisa responder a perguntas simples:

- onde o risco é maior;

Tabela 6.5: Exemplo didático de níveis operacionais para um sistema de alerta.

Nível	Condição típica	Ação esperada
Atenção	Chuva intensa em desenvolvimento ou elevação inicial de nível	Intensificar monitoramento e preparar equipes
Alerta	Probabilidade elevada de transbordamento, alagamento ou enxurrada	Comunicar setores críticos, reforçar vigilância e sinalizar áreas sensíveis
Emergência	Superação de limiar de segurança ou início de extravasamento relevante	Acionar evacuação, fechamento viário e resposta de proteção civil

- qual o nível atual de alerta;
- o que a população deve fazer;
- quais vias devem ser evitadas;
- onde procurar abrigo ou apoio;
- quem acionar em caso de necessidade.

A comunicação de risco não substitui a obra, mas reduz o impacto humano de eventos inevitáveis. Em muitos casos, ela é a diferença entre um evento danoso e um evento catastrófico.

6.8 Medidas estruturais e não estruturais

Um PDDU bem equilibrado combina diferentes tipos de intervenção.

Tabela 6.6: Comparação entre medidas estruturais e não estruturais em drenagem urbana.

Tipo	Exemplos	Função principal
Estruturais	Bacias de detenção, reservatórios, ampliação de galerias, correção de sarjetas, SBN, renaturalização de canais	Modificar fisicamente o comportamento da água
Não estruturais	Zoneamento, restrição de ocupação, manutenção, educação ambiental, alerta, fiscalização, cadastro e operação	Reduzir exposição, ordenar o uso do solo e melhorar a resposta ao risco

Em geral, o melhor PDDU não é o mais cheio de obras, mas o mais coerente com o território. Alguns problemas exigem infraestrutura pesada. Outros são melhor resolvidos por manutenção, controle urbanístico e alerta.

6.9 Hierarquização de intervenções

A priorização é uma etapa estratégica. Uma forma didática de hierarquização é considerar quatro perguntas:

1. O problema causa risco à vida ou apenas incômodo operacional?
2. O problema ocorre com alta frequência ou apenas em eventos extremos?
3. A solução é local, de custo moderado, ou exige grande obra?
4. A intervenção traz benefício imediato ou depende de longo prazo?

A partir dessas respostas, podem ser definidos horizontes de ação:

Tabela 6.7: Horizontes típicos de intervenção em um PDDU.

Horizonte	Tipo de ação	Exemplos
Imediato	Redução de risco operacional já existente	Limpeza, desobstrução, sinalização, revisão de alerta, inspeção de pontos críticos
Curto prazo	Correções localizadas e intervenções simples	Novas bocas-de-lobo, ajustes de sarjeta, microreservatórios, pequeno reforço de rede
Médio prazo	Reconfiguração de trechos e integração com uso do solo	Bacias de detenção, jardins de chuva, biovaletas, recuperação de áreas públicas
Longo prazo	Reestruturação da bacia urbana e ordenamento territorial	Renaturalização de fundos de vale, restrição de ocupação, obras integradas, reassentamento em áreas extremamente críticas

6.10 Exemplo de estruturação de um PDDU simplificado

Considere um município fictício com três setores críticos:

- **Setor A:** área central antiga, alta impermeabilização, rede subdimensionada e muitas reclamações de alagamento.
- **Setor B:** bairro recente com ocupação em fundo de vale e canal retificado.
- **Setor C:** área periférica com encostas urbanizadas, enxurradas e arraste de sedimentos.

A priorização preliminar pode ser organizada da seguinte forma.

Esse exemplo mostra que a mesma cidade pode exigir respostas completamente distintas em cada setor. Um PDDU eficaz não aplica uma solução única para problemas diferentes.

Tabela 6.8: Exemplo simplificado de priorização de ações em um PDDU fictício.

Setor	Problema dominante	Ação prioritária	Justificativa
A	Alagamento recorrente em vias centrais	Limpeza intensiva, ajuste de microdrenagem, reforço de captação e reservação localizada	Alta exposição de pessoas e comércio, além de falhas de capacidade na drenagem existente
B	Ocupação em área naturalmente inundável	Controle de uso do solo, alerta, revisão de ocupação e obras de amortecimento	Reduzir exposição e evitar aprofundamento do risco em área vulnerável
C	Enxurradas e erosão em encostas	Biovaletas, contenção, revegetação, disciplinamento de águas de montante e alerta local	Reduzir velocidade do escoamento e prevenir arraste de sedimentos

6.11 Indicadores de desempenho e revisão

Um plano diretor precisa ser acompanhado por indicadores. Sem eles, a avaliação fica subjetiva. A Tabela 6.9 apresenta exemplos úteis.

Tabela 6.9: Indicadores de acompanhamento de um Plano Diretor de Drenagem Urbana.

Indicador	O que avalia
Número de pontos de alagamento recorrente	Verifica se o problema está sendo reduzido ao longo do tempo
Duração média do alagamento	Mede a eficiência operacional da drenagem após a chuva
Percentual de dispositivos limpos e operantes	Mostra a qualidade da manutenção
Frequência de acionamento de alerta	Indica a sensibilidade do sistema e a necessidade de revisão de limiares
Tempo de resposta da defesa civil	Avalia a prontidão institucional
Área atendida por SBN	Mensura a adoção de controle na fonte e retenção distribuída
Número de ocorrências com danos materiais	Indica o efeito real das medidas implementadas

Um indicador simples de disponibilidade operacional da rede pode ser escrito como:

$$A_o = \frac{N_f}{N_t} \times 100$$

em que N_f é o número de dispositivos funcionais e N_t é o número total inspecionado.

Esse tipo de métrica ajuda a transformar a manutenção em objetivo mensurável e não em atividade secundária.

6.12 Erros frequentes em planos de drenagem

- fazer o diagnóstico apenas por gabinete, sem vistoria de campo;
- tratar o mapa de alagamento como se fosse mapa de risco sem considerar exposição e vulnerabilidade;
- propor apenas obras grandes e ignorar manutenção;
- não integrar drenagem com uso do solo e defesa civil;
- elaborar um plano sem cronograma, responsabilidades e indicadores;
- ignorar a recorrência histórica dos pontos críticos;
- subestimar a importância do alerta e da comunicação de risco;
- desconsiderar que o plano precisa ser revisado periodicamente.

6.13 Resumo do capítulo

Resumo do capítulo

O Plano Diretor de Drenagem Urbana é o instrumento que organiza o diagnóstico, o prognóstico, a priorização, a implantação e o monitoramento das ações de drenagem em escala de bacia ou município.

Um bom PDDU é baseado em princípios como abordagem por bacia, prevenção, integração institucional, manutenção e atualização periódica.

O mapeamento de áreas de risco deve distinguir perigo, exposição, vulnerabilidade e risco, combinando dados físicos, sociais e operacionais.

Sistemas de alerta são fundamentais para reduzir danos quando eventos intensos ultrapassam a capacidade de resposta da infraestrutura.

Medidas estruturais e não estruturais devem ser combinadas conforme a natureza do problema e a criticidade do território.

Indicadores de desempenho permitem verificar se o plano está de fato reduzindo alagamentos, melhorando a operação e aumentando a resiliência urbana.

Com este capítulo, o livro fecha a base conceitual e operacional da drenagem urbana, preparando o leitor para integrar projeto, gestão e prevenção em uma abordagem aplicada ao saneamento ambiental.

6.14 Exercícios

Exercício F1

Defina Plano Diretor de Drenagem Urbana e explique por que ele é necessário em cidades em processo de expansão.

Exercício F2

Diferencie perigo, exposição, vulnerabilidade e risco em uma área sujeita a inundação.

Exercício F3

Explique por que um sistema de alerta é parte essencial do planejamento de drenagem e não apenas uma medida acessória.

Exercício M1

Considere as seguintes notas de triagem para uma subárea urbana: perigo $H = 5$, exposição $E = 4$, vulnerabilidade $V = 3$. Calcule o índice simples de risco:

$$I_R = \frac{H + E + V}{3}$$

e classifique o resultado em uma escala didática de 1 a 5.

Exercício M2

Preencha, de forma conceitual, uma sequência lógica de elaboração de PDDU com as etapas: diagnóstico, prognóstico, alternativas, priorização, implementação e monitoramento. Explique a função de cada etapa.

Exercício M3

Escolha três camadas cartográficas indispensáveis para um mapa de risco de inundação urbana e explique a utilidade de cada uma.

Exercício M4

Uma cidade apresenta 48 dispositivos de drenagem inspecionados, dos quais 39 estão funcionais. Calcule o indicador de disponibilidade operacional:

$$A_o = \frac{N_f}{N_t} \times 100$$

Exercício D1

Proponha uma estrutura mínima de Plano Diretor de Drenagem Urbana para um município de médio porte. Inclua, no mínimo, os capítulos ou blocos de conteúdo, os dados necessários e os produtos finais esperados.

Exercício D2

Imagine um bairro com alagamentos frequentes, ocupação em fundo de vale, população vulnerável e rede antiga. Estruture uma proposta de ação em três horizontes: imediato, curto prazo e longo prazo. Justifique a ordem de prioridade adotada.

6.15 Gabarito comentado

Gabarito comentado

F1. O PDDU é o instrumento técnico e gerencial que organiza o diagnóstico, o planejamento, a priorização, a implantação e a revisão das ações de drenagem em uma bacia ou município. Ele é necessário porque a cidade muda ao longo do tempo, a rede envelhece, novas áreas são impermeabilizadas e os problemas de drenagem se deslocam. Sem planejamento diretor, as obras tendem a ser reativas e fragmentadas.

F2. Perigo é a probabilidade de ocorrência do fenômeno capaz de causar dano, como chuva intensa ou cheia. Exposição é a presença de pessoas, edificações ou infraestrutura na área sujeita ao fenômeno. Vulnerabilidade é o grau de suscetibilidade ao dano quando exposto. Risco é a combinação entre perigo, exposição e vulnerabilidade. Assim, uma área com alta chuva prevista, mas sem ocupação, pode ter perigo elevado e risco baixo; já uma área com ocupação sensível pode ter risco alto mesmo com chuvas moderadas.

F3. O alerta é essencial porque muitos eventos extremos ultrapassam a capacidade imediata da rede e da resposta de campo. Um sistema de alerta reduz o tempo entre a previsão e a ação, permitindo fechamento de vias, evacuação, comunicação com a população e mobilização de equipes. Ele não substitui a obra, mas reduz danos quando a obra sozinha não basta.

M1. O índice simples é:

$$I_R = \frac{5+4+3}{3} = \frac{12}{3} = 4$$

Em uma escala de 1 a 5, isso corresponde a risco alto. A interpretação é coerente: perigo elevado, exposição relevante e vulnerabilidade moderada a alta produzem prioridade de intervenção.

M2. Uma sequência lógica é:

- **Diagnóstico:** identificar onde estão os problemas, por que ocorrem e qual a capacidade atual da rede.
- **Prognóstico:** simular o que acontecerá com o crescimento urbano e com a manutenção da situação atual.
- **Alternativas:** listar obras, SBN, medidas operacionais e regulatórias capazes de mitigar os problemas.
- **Priorização:** escolher o que deve ser feito primeiro, com base em risco, custo e criticidade.

- **Implementação:** transformar as decisões em projetos, obras e rotinas.
- **Monitoramento:** acompanhar indicadores para verificar se o plano está funcionando.

Cada etapa prepara a seguinte e reduz o risco de decisões isoladas.

M3. Três camadas indispensáveis são: modelo digital do terreno, porque mostra depressões, talvegues e áreas de acúmulo; uso e cobertura do solo, porque permite estimar impermeabilização e ocupações sensíveis; e histórico de alagamentos, porque confirma onde os eventos se repetem. Outras camadas importantes incluem rede de drenagem, população vulnerável e infraestrutura crítica.

M4. O indicador de disponibilidade operacional é:

$$A_o = \frac{39}{48} \times 100$$

$$A_o = 81.25$$

Logo, a disponibilidade operacional é de 81,25 %. O valor é bom, mas ainda indica que quase um quinto dos dispositivos inspecionados não está funcional, o que pode comprometer o desempenho em eventos intensos.

D1. Uma estrutura mínima de PDDU deve incluir: caracterização do município e da bacia; diagnóstico físico e operacional; análise de eventos históricos; mapeamento de risco; prognóstico de crescimento; avaliação de alternativas; programa de intervenções; plano de manutenção; sistema de alerta; indicadores de monitoramento; cronograma e responsabilidades. Os dados necessários incluem topografia, chuva, rede existente, uso do solo, solo, vulnerabilidade social e ocorrências históricas. Os produtos finais esperados são mapas, lista de intervenções prioritárias, plano de ação, cronograma e sistema de acompanhamento.

D2. Em um bairro com fundo de vale, população vulnerável e rede antiga, a prioridade imediata deve ser reduzir risco operacional: limpeza, desobstrução, sinalização e ajuste de alerta. Em curto prazo, devem entrar correções pontuais, como novas bocas-de-lobo, melhoria da microdrenagem e pequenas retenções. No longo prazo, são necessárias ações estruturais e territoriais, como reservatórios, requalificação do fundo de vale, SBN, restrições de ocupação e, se indispensável, reassentamento em áreas de risco muito alto. A ordem de prioridade se justifica pela necessidade de proteger vidas primeiro e atacar as causas estruturais em seguida.

6.16 Conexão com o próximo capítulo

Conexão com o próximo capítulo

Este capítulo concluiu a dimensão de planejamento e gestão da drenagem urbana, mostrando como diagnosticar, mapear risco, priorizar obras e estruturar alertas. Com isso, o livro fecha sua progressão principal: do problema hidrológico ao projeto e, depois, ao planejamento público. O próximo passo é a elaboração de um capítulo integrador com estudo de caso completo, reunindo o método racional, a microdrenagem, as bacias de controle, as SBN e o PDDU em um único projeto aplicado.

Capítulo 7

Projeto integrador de uma microbacia urbana

Este capítulo encerra a trajetória didática do livro com uma síntese aplicada. A proposta é transformar os conceitos desenvolvidos ao longo das etapas anteriores em um projeto coerente, tecnicamente defensável e pedagogicamente útil. Em drenagem urbana, nenhum elemento funciona isoladamente: a chuva de projeto depende do diagnóstico hidrológico, a microdrenagem depende da topografia, a bacia de detenção depende da vazão admissível, as Soluções Baseadas na Natureza dependem do uso do solo e o Plano Diretor de Drenagem Urbana depende de governança, operação e monitoramento (Tucci, 2008; Botelho, 2011; Pompeo, 2000; Canholi, 2014; Brasil, 2013).

Definição – Projeto integrador

Exercício de síntese que reúne diagnóstico, hidrologia, microdrenagem, reservação, Soluções Baseadas na Natureza, planejamento e operação em um único caso aplicado.

A seguir, o livro adota uma microbacia fictícia, porém realista, chamada **Microbacia do Córrego Novo Horizonte**. O objetivo é mostrar como os resultados parciais dos capítulos anteriores podem ser reunidos em uma solução única, consistente e passível de execução em etapas.

7.1 Objetivos de aprendizagem

Ao final deste capítulo, o estudante deverá ser capaz de:

- integrar hidrologia, microdrenagem, reservação, SBN e gestão em um caso único;
- estruturar um diagnóstico sintético de uma microbacia urbana com problemas recorrentes de inundação;
- dimensionar preliminarmente um trecho representativo de coletor pluvial;
- interpretar a função de uma bacia de detenção como reguladora de pico;
- propor um pacote distribuído de SBN como reforço da drenagem convencional;
- organizar a implantação por fases, com manutenção e monitoramento;

- hierarquizar intervenções segundo risco, exposição e viabilidade técnica.

7.2 Caso-base da microbacia urbana

A Microbacia do Córrego Novo Horizonte possui 52 ha e apresenta crescimento por adensamento, aumento de impermeabilização e recorrência de alagamentos em uma avenida principal e no fundo de vale. O uso do solo foi simplificado em cinco setores, conforme a Tabela 7.1.

Tabela 7.1: Caracterização simplificada da Microbacia do Córrego Novo Horizonte.

Setor	**Uso predominante**	**Área**	**Coeficiente C**
A	Residencial denso	18 ha	0,70
B	Residencial de baixa densidade	12 ha	0,45
C	Comercial e estacionamentos	6 ha	0,85
D	Parque e áreas verdes	8 ha	0,20
E	Vias e equipamentos públicos	8 ha	0,90

A microbacia apresenta declividade média moderada, pontos baixos ao longo da avenida principal e concentração de fluxo no fundo de vale. Há uma escola, um pequeno polo comercial, áreas residenciais consolidadas e um parque linear com potencial para amortecimento hidráulico. O sistema de drenagem existente foi implantado em etapas e não acompanha a taxa atual de impermeabilização.

7.3 Fluxo integrador do projeto

A Figura 7.1 resume o encadeamento lógico do projeto integrado.

O fluxograma deixa claro que o projeto não depende de uma única obra. Ele exige coordenação entre diagnóstico, hidrologia, microdrenagem, reservação, SBN e gestão pública.

7.4 Síntese técnica do diagnóstico

A leitura integrada da microbacia mostra quatro problemas centrais:

- aumento do escoamento superficial pela impermeabilização;
- concentração de vazões em pontos baixos da avenida principal;
- sobrecarga da rede pluvial em eventos intensos;
- exposição de pedestres, comércio e escola a alagamentos recorrentes.



Figura 7.1: Sequência integradora de projeto adotada para a microbacia caso-base.

Esses sintomas indicam que a solução deve combinar ações de curto, médio e longo prazo. A microdrenagem corrige o transporte local; a bacia de detenção reduz o pico a jusante; as SBN atenuam a geração de escoamento na fonte; e o PDDU organiza a implantação e o monitoramento.

7.5 Dimensionamento integrado

7.5.1 Vazão de projeto da microbacia

O coeficiente médio ponderado de escoamento é:

$$C_m = \frac{18 \times 0.70 + 12 \times 0.45 + 6 \times 0.85 + 8 \times 0.20 + 8 \times 0.90}{52}$$

$$C_m = \frac{12.60 + 5.40 + 5.10 + 1.60 + 7.20}{52} = \frac{31.90}{52} = 0{,}6135$$

Adotando intensidade de chuva de 100 mm/h, a vazão de pico pelo método racional é:

$$Q = 0.278 \times 0.6135 \times 100 \times 0.52$$

$$Q \approx 8{,}87\ \mathrm{m^3/s}$$

A vazão de projeto da microbacia é, portanto, de aproximadamente 8,87 m^3/s.

7.5.2 Trecho representativo da microdrenagem

Para o trecho crítico da avenida principal, considere 1,8 ha de área contribuinte, coeficiente $C = 0{,}72$ e a mesma intensidade de projeto de 100 mm/h. A vazão local é:

$$Q_{\text{local}} = 0.278 \times 0.72 \times 100 \times 0.018$$

$$Q_{\text{local}} \approx 0{,}360\ \text{m}^3/\text{s}$$

Adotando um coletor pluvial circular de concreto com $n = 0{,}013$, declividade $S = 0{,}006$ e diâmetro de 0,60 m, a capacidade hidráulica em regime cheio é:

$$Q = \frac{1}{n} A R^{2/3} S^{1/2}$$

com

$$A = \frac{\pi D^2}{4} \quad \text{e} \quad R = \frac{D}{4}$$

Substituindo $D = 0{,}60$ m:

$$A = \frac{\pi \times 0.60^2}{4} \approx 0{,}283\ \text{m}^2$$

$$R = \frac{0.60}{4} = 0{,}15\ \text{m}$$

$$Q = \frac{1}{0.013} \times 0.283 \times 0.15^{2/3} \times 0.006^{1/2}$$

$$Q \approx 0{,}47\ \text{m}^3/\text{s}$$

Logo, um coletor de 600 mm atende, em primeira aproximação, à vazão local de 0,360 m³/s com margem operacional.

7.5.3 Reservação para amortecimento de pico

Como a vazão da microbacia é superior à capacidade admissível do sistema a jusante, a solução inclui uma bacia de detenção localizada no parque linear. Como valor consolidado de projeto, adota-se um volume útil de:

$$V_{\text{det}} = 22\,200\ \text{m}^3$$

Se a profundidade útil for de 2,2 m, a área média necessária é:

$$A_{\text{det}} = \frac{22200}{2.2} = 10\,090{,}9\ \text{m}^2$$

ou, arredondando:

$$A_{\text{det}} \approx 10\,091\ \text{m}^2$$

A interpretação técnica é direta: a bacia deve ocupar cerca de um hectare de área útil, com geometria compatível com taludes, berma de segurança, drenagem de fundo e extravasor de emergência.

7.5.4 Soluções Baseadas na Natureza

Além da bacia principal, a microbacia recebe um pacote distribuído de SBN para reduzir a primeira onda de escoamento, melhorar a qualidade da água e aumentar a resiliência cotidiana da drenagem. O pacote proposto é resumido na Tabela 7.2.

Tabela 7.2: Pacote distribuído de SBN para a microbacia caso-base.

Medida	**Quantidade**	**Hipótese de cálculo**	**Volume equivalente**
Jardins de chuva	25 unidades	20 m^2 cada, profundidade útil de 0,20 m	100 m^3
Biovaletas	1000 m lineares	Seção média de armazenamento equivalente de 0,15 m^2 por metro	150 m^3
Pavimentos permeáveis	10 000 m^2	Base granular de 0,18 m com índice de vazios 0,35	630 m^3
Telhado verde	1000 m^2	Retenção equivalente média de 0,02 m	20 m^3
Total	—	—	900 m^3

O conjunto de SBN acrescenta cerca de 900 m^3 de retenção distribuída. Em termos equivalentes, esse pacote reduz o coeficiente de escoamento médio em aproximadamente 0,017, reforçando a primeira resposta do sistema sem substituir a bacia principal.

7.6 Plano de implantação por fases

A implementação deve ser organizada em etapas para compatibilizar custo, operação, licenciamento e aceitação social.

A lógica de implantação não é apenas técnica; ela é também administrativa. A etapa imediata protege pessoas e reduz danos recorrentes, enquanto as etapas seguintes atacam a causa estrutural do problema.

7.7 Operação, manutenção e monitoramento

Como qualquer infraestrutura urbana, o sistema integrado depende de manutenção. A Tabela 7.4 organiza uma rotina mínima.

Tabela 7.3: Fases de implantação do projeto integrado.

Horizonte	Ações principais	Objetivo
Imediato	Limpeza de bocas-de-lobo, retirada de resíduos, sinalização dos pontos críticos e revisão do protocolo de alerta	Reduzir o risco operacional já existente
Curto prazo	Reforço de microdrenagem na avenida principal, ajustes de sarjetas e implantação inicial de jardins de chuva e pavimentos permeáveis	Melhorar a resposta local e reduzir a geração de escoamento na fonte
Médio prazo	Construção da bacia de detenção, integração com o parque linear e implementação do sistema de saída em estágios	Amortecer o pico de vazão e proteger o sistema a jusante
Longo prazo	Revisão do uso do solo, consolidação do monitoramento, expansão das SBN e atualização periódica do PDDU	Sustentar a resiliência hidráulica e institucional

Tabela 7.4: Rotina mínima de operação e manutenção do sistema integrado.

Elemento	Frequência sugerida	Atividade
Bocas-de-lobo e sarjetas	Semanal e após chuva intensa	Remoção de resíduos, sedimentos e verificação de obstruções
Coletores e poços de visita	Trimestral e após eventos críticos	Inspeção, limpeza e checagem de refluxo ou assoreamento
Jardins de chuva e biovaletas	Mensal e por campanha sazonal	Reposição de vegetação, retirada de lixo e verificação de erosão
Pavimentos permeáveis	Mensal ou bimestral	Varrição mecânica, aspiração e controle de colmatação superficial
Bacia de detenção	Após eventos e periodicamente	Inspeção de taludes, drenagem de fundo, sedimentação e dispositivos de saída
Sistema de alerta	Mensal	Teste de sensores, comunicação e protocolo de emergência

Os indicadores de desempenho permitem verificar se o sistema realmente está funcionando. A Tabela 7.5 propõe métricas simples e objetivas.

Tabela 7.5: Indicadores de desempenho para o projeto integrado.

Indicador	**Meta sugerida**
Pontos de alagamento recorrente	Redução progressiva até a eliminação dos pontos de maior frequência
Disponibilidade operacional dos dispositivos	Superior a 90 % dos elementos críticos
Tempo de esvaziamento da bacia de detenção	Inferior a 24 h em regime normal
Cobertura de alerta em áreas críticas	100 % dos setores de maior risco
Área atendida por SBN	Ampliação contínua com prioridade às áreas institucionais e de maior contribuição superficial

7.8 Resultados técnicos consolidados

A Tabela 7.6 reúne os principais resultados do caso-base.

Tabela 7.6: Resultados finais do projeto integrador da microbacia.

Item	**Resultado**
Área total da microbacia	52 ha
Coeficiente médio ponderado	0,6135
Vazão de pico	8,87 m^3/s
Vazão local de referência	0,360 m^3/s
Coletor representativo	600 mm
Volume útil da bacia de detenção	22 200 m^3
Área útil estimada da bacia	10 091 m^2
Volume equivalente das SBN distribuídas	900 m^3
Redução equivalente no coeficiente médio	0,017

A solução integrada mostra que a drenagem urbana eficiente raramente depende de uma única obra. O sistema mais robusto combina microdrenagem confiável, reservação para amortecer picos, SBN para controle na fonte, monitoramento e alerta, além de gestão territorial por meio de PDDU.

7.9 Resumo do capítulo

Resumo do capítulo

Este capítulo apresentou um projeto integrador completo para uma microbacia urbana fictícia, articulando hidrologia, microdrenagem, reservação, SBN, operação e planejamento.
A Microbacia do Córrego Novo Horizonte possui 52 ha, coeficiente médio ponderado 0,6135 e vazão de pico estimada em 8,87 m^3/s.
Um trecho representativo da avenida principal pode ser atendido por um coletor de 600 mm, com capacidade hidráulica superior à vazão local de 0,360 m^3/s.
A bacia de detenção consolidada requer 22 200 m^3 de volume útil, com área aproximada de 10 091 m^2 para profundidade útil de 2,2 m.
O pacote de SBN distribuídas adiciona cerca de 900 m^3 de retenção e reforça o controle na fonte, sem substituir a bacia principal.
A implantação deve ser faseada, com prioridade para limpeza, alerta, correções locais, reservação e revisão do uso do solo.
O projeto só se completa com operação, manutenção, monitoramento e revisão contínua, em consonância com um Plano Diretor de Drenagem Urbana.

7.10 Exercícios

Exercício F1

Explique por que, em drenagem urbana, um projeto integrador é mais eficaz do que a simples soma de obras isoladas.

Exercício F2

Justifique por que a bacia de detenção, o coletor pluvial e as SBN são soluções complementares no caso-base.

Exercício F3

Explique por que um sistema multistágio de saída pode ser mais adequado do que um único orifício de grande porte em uma bacia de detenção urbana.

Exercício M1

Calcule o coeficiente médio ponderado da Microbacia do Córrego Novo Horizonte, a partir dos dados da Tabela 7.1.

Exercício M2

Usando $C_m = 0{,}6135$, $i = 100\,\mathrm{mm/h}$ e $A = 0{,}52\,\mathrm{km}^2$, determine a vazão de pico da microbacia pelo método racional.

Exercício M3

Com base no volume útil consolidado da bacia de detenção, estime a área média necessária para uma profundidade útil de 2,2 m.

Exercício D1

Proponha um plano de implantação em três fases para o caso-base, distinguindo medidas imediatas, de curto prazo e de médio a longo prazo. Indique a finalidade principal de cada fase.

Exercício D2

Construa uma matriz de priorização para os três setores mais críticos do caso-base, usando como critérios perigo, exposição, vulnerabilidade e viabilidade técnica. Apresente a ordem de prioridade e justifique sua decisão.

7.11 Gabarito comentado

Gabarito comentado

F1. Um projeto integrador é mais eficaz porque articula todas as escalas do problema: superfície, rede, reservação, uso do solo e gestão. Obras isoladas podem aliviar um ponto e agravar outro. Já um projeto integrado distribui a função entre os componentes certos, reduz o risco de transferência do problema a jusante e melhora a eficiência global do sistema.

F2. O coletor pluvial conduz a vazão local com segurança; a bacia de detenção reduz o pico de descarga da microbacia como um todo; e as SBN reduzem a geração de escoamento na fonte e melhoram a qualidade da água. Como atuam em escalas diferentes, as três soluções se complementam naturalmente.

F3. Um único orifício muito grande tende a ser sensível a entupimento, a problemas operacionais e a variações de nível. Além disso, dificulta a modulação da descarga em diferentes regimes de chuva. Um sistema multistágio oferece maior controle, melhor operação e mais segurança em eventos frequentes e extremos.

M1. O coeficiente médio ponderado é:

$$C_m = \frac{18 \times 0.70 + 12 \times 0.45 + 6 \times 0.85 + 8 \times 0.20 + 8 \times 0.90}{52}$$

$$C_m = \frac{31.90}{52} = 0{,}6135$$

Logo, $C_m \approx 0{,}61$.

M2. Aplicando o método racional:

$$Q = 0.278 \times 0.6135 \times 100 \times 0.52$$

$$Q \approx 8{,}87\ \mathrm{m^3/s}$$

A vazão de pico é aproximadamente 8,87 m³/s. Esse é o valor de referência para a microbacia.

M3. A área da bacia de detenção é:

$$A_{\text{det}} = \frac{22200}{2.2} = 10\,090{,}9\ \text{m}^2$$

Arredondando, $A_{\text{det}} \approx 10\,091\ \text{m}^2$. Esse resultado é coerente com uma bacia de controle com cerca de um hectare de área útil.

D1. Uma proposta consistente pode ser:

- **Fase imediata:** limpeza de bocas-de-lobo, remoção de resíduos, sinalização dos pontos críticos e revisão do protocolo de alerta.
- **Fase de curto prazo:** reforço da microdrenagem na avenida principal, ajustes de sarjetas e implantação inicial de jardins de chuva e pavimentos permeáveis.
- **Fase de médio e longo prazo:** construção da bacia de detenção, integração com o parque linear, implementação de sistema de saída em estágios e revisão do uso do solo.

A lógica é proteger pessoas e reduzir danos recorrentes primeiro, para depois atacar a causa estrutural do problema.

D2. A matriz de priorização deve apontar como prioritário o setor da avenida principal, pois ele reúne perigo elevado, exposição intensa e falha operacional imediata. Em seguida, o fundo de vale e o parque linear devem receber atenção por concentrar volumes e ter forte potencial de amortecimento por reservação. O setor institucional e escolar é prioritário pela vulnerabilidade das pessoas e pelo uso diário intenso. A viabilidade técnica também deve ser considerada: medidas imediatas costumam ser mais simples, enquanto a bacia de detenção exige projeto e execução mais robustos. A ordem final, em geral, tende a ser: avenida principal, fundo de vale e, depois, setor institucional, sem perder de vista que todos os setores precisam ser tratados em conjunto.

7.12 Conexão com os apêndices

Conexão com o próximo capítulo

Este capítulo mostra como o conteúdo do livro pode ser convertido em um projeto integrado de drenagem urbana, com números, prioridades, fases e critérios de manutenção. Nos apêndices, esse caso é desdobrado em fórmulas de apoio, checklists de inspeção, modelos de memorial de cálculo e glossário técnico, reforçando a transição entre o aprendizado didático e a prática profissional.

Capítulo A

Fórmulas, unidades e relações de apoio

Este apêndice reúne as expressões matemáticas, conversões de unidade e relações operacionais mais usadas ao longo do livro. O objetivo é servir como referência rápida para estudo, revisão e resolução de exercícios. As equações aqui apresentadas não substituem o julgamento técnico nem as normas locais, mas organizam a base mínima para o trabalho em drenagem urbana.

A.1 Equações fundamentais

A.1.1 Método racional

A expressão clássica do método racional é:

$$Q = 0.278\, C\, i\, A$$

em que:

- Q é a vazão de pico em m³/s;
- C é o coeficiente de escoamento superficial, adimensional;
- i é a intensidade de chuva em mm/h;
- A é a área da bacia em km².

Quando a área é expressa em hectares, a forma equivalente é:

$$Q = 0.00278\, C\, i\, A$$

com A em ha.

A.1.2 Coeficiente médio ponderado

Para bacias com usos do solo distintos:

$$C_m = \frac{\sum C_j A_j}{\sum A_j}$$

em que C_j é o coeficiente de cada subárea e A_j a respectiva área.

A.1.3 Volume de escoamento superficial

Uma estimativa simplificada do volume gerado por uma chuva de projeto é:

$$V = 10\,C\,P\,A$$

em que:

- V é o volume em m^3;
- P é a altura de chuva em mm;
- A é a área em ha.

A.1.4 Equação da continuidade em reservação

Para bacias de detenção e retenção:

$$\frac{dS}{dt} = Q_{\text{in}}(t) - Q_{\text{out}}(t)$$

onde S representa o armazenamento no tempo.
A forma integrada é:

$$S(t) = \int_0^t \Big(Q_{\text{in}}(\tau) - Q_{\text{out}}(\tau)\Big)\, d\tau$$

O armazenamento máximo requerido é dado por:

$$V_{\text{req}} = \max_t \left[\int_0^t \Big(Q_{\text{in}}(\tau) - Q_{\text{out}}(\tau)\Big)\, d\tau\right]$$

A.1.5 Manning

Para escoamento em canal aberto ou conduto em regime simplificado:

$$Q = \frac{1}{n} A R^{2/3} S^{1/2}$$

em que:

- n é o coeficiente de rugosidade de Manning;
- A é a área molhada;
- R é o raio hidráulico;
- S é a declividade hidráulica.

Para tubo circular escoando cheio:

$$A = \frac{\pi D^2}{4}$$

$$R = \frac{D}{4}$$

e, portanto,

$$Q = \frac{1}{n}\frac{\pi D^2}{4}\left(\frac{D}{4}\right)^{2/3} S^{1/2}$$

A.1.6 Orifício

Para vazão por orifício submerso:

$$Q = C_d A\sqrt{2gh}$$

em que:

- C_d é o coeficiente de descarga;
- A é a área da abertura;
- g é a aceleração da gravidade;
- h é a carga hidráulica.

A.1.7 Vertedor

Para vertedor simples:

$$Q = C_w L h^{3/2}$$

em que:

- C_w é o coeficiente do vertedor;
- L é o comprimento útil;
- h é a carga hidráulica sobre a soleira.

A.1.8 Tempo de esvaziamento em soluções de infiltração

Uma estimativa preliminar pode ser feita por:

$$t_d = \frac{V_u}{k_s A_{\text{inf}}}$$

em que:

- t_d é o tempo de drenagem;
- V_u é o volume útil armazenado;
- k_s é a condutividade hidráulica saturada;

- A_{inf} é a área infiltrante efetiva.

A.2 Conversões de unidade mais úteis

Tabela A.1: Conversões usuais em drenagem urbana.

Relação	Equivalência
1 ha	10 000 m^2
1 km^2	100 ha
1 mm de chuva em 1 ha	10 m^3
1 L/s	0,001 m^3/s
1 m^3/s	1000 L/s
1 h	3600 s
1 min	60 s

A.3 Sequência de cálculo recomendada

1. Delimitar a bacia e identificar subáreas homogêneas.
2. Estimar o coeficiente médio ponderado de escoamento.
3. Obter a chuva de projeto a partir da curva IDF local.
4. Definir o tempo de concentração e a duração crítica.
5. Calcular a vazão de pico por método racional, quando aplicável.
6. Verificar microdrenagem, reservação e necessidade de SBN.
7. Ajustar a descarga admissível com base na capacidade a jusante.
8. Estimar volume de armazenamento e dimensionar dispositivos de saída.
9. Conferir manutenção, segurança e extravasamento de emergência.

A.4 Faixas indicativas de coeficiente de escoamento

A.5 Observações de uso

As relações reunidas neste apêndice são adequadas para pré-dimensionamento, verificação preliminar e exercícios didáticos. Em projeto executivo, devem ser confrontadas com:

- dados pluviométricos locais;
- características reais do solo;
- topografia detalhada;

Tabela A.2: Faixas indicativas de coeficiente de escoamento para apoio preliminar.

Tipo de superfície	**Faixa indicativa de C**
Telhados, lajes e superfícies praticamente impermeáveis	0.80 a 0.95
Asfalto e concreto contínuos	0.75 a 0.95
Áreas pavimentadas com juntas e recuos	0.60 a 0.85
Residencial adensado com uso misto	0.45 a 0.70
Residencial de baixa densidade	0.30 a 0.50
Áreas verdes urbanas e parques	0.05 a 0.25
Solo exposto ou compactado	0.20 a 0.40

- critérios de norma e manual aplicável;
- restrições de manutenção e operação;
- segurança hidráulica e urbana.

Capítulo B

Checklist de inspeção e diagnóstico de campo

A qualidade de um projeto de drenagem depende diretamente da qualidade do diagnóstico de campo. Muitas falhas não aparecem em gabinete, mas tornam-se evidentes durante a vistoria: boca-de-lobo obstruída, sarjeta deformada, ponto baixo ignorado, ligação irregular, sedimento acumulado, erosão em descarga e ocupação inadequada de áreas naturalmente inundáveis.

Este apêndice apresenta um roteiro de inspeção prática que pode ser utilizado em levantamento preliminar, vistoria técnica ou campanha de monitoramento.

B.1 Checklist geral da bacia

- Delimitação correta da bacia e dos pontos de contribuição.
- Identificação do exutório principal e de possíveis rotas alternativas.
- Reconhecimento de pontos baixos, depressões e linhas de fluxo preferencial.
- Verificação da presença de áreas de várzea, fundos de vale e margens ocupadas.
- Registro de ocupações sensíveis: escolas, hospitais, abrigos, vias arteriais e comércio.
- Avaliação visual da taxa de impermeabilização.
- Identificação de áreas verdes, canteiros, jardins e superfícies permeáveis.
- Observação de sinais de alagamento recorrente, depósitos de lama e marcas de nível.

B.2 Checklist da microdrenagem

- Sarjetas com declividade contínua e sem contra-caídas.
- Meio-fio íntegro e sem descontinuidades problemáticas.
- Bocas-de-lobo posicionadas em locais hidráulicos coerentes.
- Grelhas sem deformações, entupimentos ou acúmulo de resíduos.
- Poços de visita acessíveis, identificáveis e sem extravasamento.

- Coletores sem afundamento aparente, abatimento ou sinais de refluxo.
- Descargas protegidas contra erosão e sem lançamento irregular.
- Conexões laterais sem sinais de improvisação ou ligação clandestina.

B.3 Checklist de reservação e controle de cheias

- Área disponível para detenção ou retenção.
- Cota de entrada compatível com a drenagem por gravidade.
- Volume útil plausível para a bacia proposta.
- Presença de vertedor de emergência.
- Existência de drenagem de fundo ou estrutura de esvaziamento.
- Taludes estáveis e com proteção contra erosão.
- Acesso para limpeza, inspeção e remoção de sedimentos.
- Compatibilidade com uso público, segurança e sinalização.

B.4 Checklist de Soluções Baseadas na Natureza

- Solo compatível com infiltração ou presença de dreno de fundo.
- Espaço suficiente para o desenvolvimento da vegetação.
- Entrada de água protegida contra sedimentos grosseiros.
- Extravasor seguro para chuvas acima da condição de projeto.
- Vegetação adaptada ao regime local de umidade.
- Ausência de risco estrutural a fundações, taludes ou redes enterradas.
- Plano de manutenção definido e viável.
- Compatibilidade com a circulação de pessoas e veículos.

B.5 Checklist de risco e vulnerabilidade

- População exposta em áreas de alagamento ou enxurrada.
- Presença de crianças, idosos, pessoas com mobilidade reduzida ou baixa autonomia.
- Edificações críticas sujeitas a perda funcional.
- Rotas de fuga e acessos de emergência.

- Histórico de ocorrências com danos materiais ou interrupção de serviços.
- Nível de percepção comunitária do risco.
- Existência de comunicação prévia e sistema de alerta.

B.6 Modelo de ficha de vistoria

A seguir, um modelo simples de campos que pode ser adaptado a formulário impresso ou digital.

Tabela B.1: Modelo básico de ficha de vistoria de drenagem urbana.

Campo	Informação a registrar
Data e hora da vistoria	Preenchimento obrigatório
Responsável técnico	Nome, cargo e contato
Localização	Rua, trecho, coordenadas e referência local
Tipo de ocorrência	Alagamento, enxurrada, refluxo, erosão, obstrução ou outro
Condição visual da drenagem	Boa, regular, ruim ou crítica
Obstruções observadas	Lixo, folhas, sedimentos, vegetação, entulho, deformações
Pontos baixos e marcas de água	Registrar cotas, extensão e profundidade aparente
Fotografias	Anexar imagens representativas
Ação imediata recomendada	Limpeza, sinalização, reparo, monitoramento ou outra
Observações complementares	Campo livre para descrição técnica

B.7 Critérios de priorização em campo

Quando o tempo de vistoria é limitado, recomenda-se priorizar:

1. locais com risco à vida;
2. pontos com frequência elevada de alagamento;
3. áreas com infraestrutura crítica;
4. trechos com grande concentração de água e sedimentos;
5. locais com falha visível de dispositivos essenciais;
6. setores com forte vulnerabilidade social.

B.8 Uso do checklist

Este roteiro pode ser usado em:

- inspeção pós-chuva;
- diagnóstico preliminar de bairro;
- elaboração de Plano Diretor de Drenagem Urbana;
- acompanhamento de obras;
- avaliação de desempenho de SBN;
- atualização cadastral da rede existente.

Capítulo C

Modelo de memorial de cálculo e relatório técnico

Este apêndice apresenta uma estrutura de referência para a elaboração de um memorial de cálculo de drenagem urbana ou de um relatório técnico de projeto. O objetivo é oferecer um roteiro claro, completo e facilmente adaptável a trabalhos acadêmicos, projetos de graduação, estudos preliminares e relatórios profissionais.

C.1 Estrutura mínima do documento

1. Identificação do empreendimento ou da área de estudo.
2. Objetivo do projeto.
3. Caracterização da área e da bacia contribuinte.
4. Dados de precipitação e critérios de projeto.
5. Estimativa da vazão de pico.
6. Dimensionamento da microdrenagem.
7. Dimensionamento de bacias de detenção ou retenção, se aplicável.
8. Avaliação de Soluções Baseadas na Natureza.
9. Verificação de segurança, manutenção e operação.
10. Conclusões e recomendações.

C.2 Modelo de capa interna

C.3 Roteiro de conteúdo técnico

C.3.1 Caracterização da área

Descrever:

- localização e limites;

Tabela C.1: Campos recomendados para a identificação do projeto.

Campo	Conteúdo
Título do projeto	Exemplo: Drenagem pluvial da Microbacia do Córrego Novo Horizonte
Localização	Município, bairro, estado
Contratante ou disciplina	Instituição, curso ou órgão responsável
Responsável técnico	Nome do autor ou equipe
Data	Mês e ano
Versão	Preliminar, executivo, revisão ou relatório final

- topografia e declividades;
- uso e ocupação do solo;
- histórico de alagamentos e danos;
- solo, permeabilidade e nível freático;
- rede de drenagem existente;
- áreas sensíveis e infraestrutura crítica.

C.3.2 Critérios hidrológicos

Registrar:

- curva IDF adotada;
- período de retorno;
- tempo de concentração;
- coeficiente de escoamento;
- método de estimativa da vazão;
- hipóteses e limitações do cálculo.

C.3.3 Dimensionamento hidráulico

Apresentar:

- vazões por trecho e por sub-bacia;
- sarjetas, bocas-de-lobo e coletores;
- dispositivos de reservação;
- verificação de velocidades e declividades;
- elementos de dissipação e proteção contra erosão.

C.3.4 Soluções complementares

Indicar:

- jardins de chuva;
- biovaletas;
- pavimentos permeáveis;
- trincheiras de infiltração;
- medidas de manutenção e operação;
- adequação ao Plano Diretor de Drenagem Urbana.

C.4 Modelo de conclusão

A conclusão deve responder objetivamente:

- o que foi dimensionado;
- qual problema foi enfrentado;
- qual solução foi escolhida;
- quais limitações ainda permanecem;
- quais medidas complementares são recomendadas.

C.5 Modelo de quadro-síntese

Tabela C.2: Quadro-síntese para fechamento do relatório.

Item	Síntese
Problema principal	Excesso de escoamento e alagamentos recorrentes
Estratégia de controle	Microdrenagem, reservação, SBN e gestão operacional
Critério de projeto	Vazão admissível compatível com o sistema a jusante
Ponto de atenção	Manutenção e obstrução dos dispositivos
Resultado esperado	Redução do pico, mitigação de danos e maior resiliência urbana

C.6 Sugestão de organização visual

Para relatórios formais, recomenda-se:

- títulos claros e numerados;
- tabelas padronizadas;

- figuras com legenda objetiva;
- unidades sempre explícitas;
- hipóteses destacadas;
- conclusões separadas de cálculos;
- anexos e apêndices para dados extensos.

Capítulo D

Glossário técnico essencial

Este glossário reúne conceitos centrais do livro em linguagem sintética, útil para revisão, consulta rápida e uniformização terminológica.

Tabela D.1: Glossário técnico essencial de drenagem urbana.

Termo	Definição resumida
Alagamento	Acúmulo de água em ruas, calçadas ou baixadas por falha de drenagem local, sem necessidade de transbordamento de curso d'água.
Bacia de detenção	Estrutura de armazenamento temporário que libera a água de forma controlada após a chuva.
Bacia de retenção	Estrutura com volume permanente de água e descarga regulada.
Biovaleta	Canal vegetado para condução lenta, retenção de sedimentos e melhoria da qualidade da água.
Chuva de projeto	Evento pluviométrico representativo usado no dimensionamento de obras de drenagem.
Coeficiente de escoamento	Fração da chuva que se converte em escoamento superficial.
Coletores pluviais	Condutos subterrâneos que transportam a água captada pela microdrenagem.
Drenagem sustentável	Conjunto de estratégias que reduz escoamento, melhora infiltração e integra a água ao espaço urbano.
Enchente	Elevação do nível de um corpo d'água com transbordamento sobre áreas adjacentes.
Enxurrada	Escoamento superficial rápido e concentrado, com alta energia e potencial de dano.
Exposição	Presença de pessoas, bens ou infraestrutura em área sujeita ao perigo.

Termo	Definição resumida
Impermeabilização	Redução da infiltração do solo por pavimentação, compactação ou cobertura artificial.
Microdrenagem	Sistema de captação e transporte em escala de rua e quadra.
Método racional	Método simplificado para estimar vazão de pico em pequenas bacias urbanas.
PDDU	Instrumento de planejamento que organiza diagnóstico, prioridades, obras e monitoramento da drenagem urbana.
Período de retorno	Medida estatística de frequência média de ocorrência de eventos de determinada magnitude.
Perigo	Probabilidade de ocorrência de um fenômeno capaz de causar danos.
Risco	Combinação entre perigo, exposição e vulnerabilidade.
Sarjeta	Faixa da via que conduz o escoamento superficial até a captação.
SBN	Soluções Baseadas na Natureza, inspiradas em processos naturais e voltadas a serviços ecossistêmicos e redução de risco.
Tempo de concentração	Tempo necessário para a água do ponto mais distante da bacia alcançar o exutório.
Vazão de pico	Máximo valor instantâneo ou quase instantâneo da vazão gerada por um evento de chuva.
Vulnerabilidade	Grau de suscetibilidade a danos quando um sistema ou população está exposto ao perigo.

D.1 Como usar este glossário

O glossário pode ser consultado de três maneiras:

- como revisão conceitual antes de exercícios;
- como apoio para relatórios e memoriais de cálculo;
- como referência de uniformização de termos em aula ou em projeto.

D.2 Encerramento dos apêndices

Os apêndices reúnem fórmulas, checklists, modelos e definições que sustentam o conteúdo principal do livro. Em conjunto, eles formam uma base de consulta prática para o estudo, para a elaboração de exercícios e para a construção de projetos de drenagem urbana com rigor técnico e clareza pedagógica.

Referências Bibliográficas

BOTELHO, M. H. C. *Águas de Chuva: Engenharia das Águas Pluviais nas Cidades*. 3. ed. São Paulo: Edgard Blücher, 2011.

BRASIL. *Plano Nacional de Saneamento Básico (PLANSAB)*. Brasília: MCidades, 2013.

CANHOLI, A. P. *Drenagem Urbana e Controle de Enchentes*. 2. ed. São Paulo: Oficina de Textos, 2014.

POMPÊO, C. A. *Drenagem Urbana Sustentável*. Florianópolis: UFSC, 2000.

TUCCI, C. E. M. *Águas Urbanas*. Estudos Avançados, São Paulo: USP, 2008.