CURSO DE SANEAMENTO AMBIENTAL

Sistema de Esgotamento Sanitário

Concepção, projeto, operação e manutenção de sistemas de coleta, transporte e afastamento de esgotos domésticos e industriais

TRANSPORTE | COLETA | OPERAÇÃO | MANUTENÇÃO

Livro modular • exercícios comentados • foco em concepção, projeto e operação

Material didático para o curso de Saneamento Ambiental

Sumário

I Bases de projeto 1

1 Geração de esgoto e vazões de projeto 2

1.1 Objetivos de aprendizagem 2

1.2 Conceitos fundamentais 2

1.3 Composição das vazões de projeto 4

1.4 Parâmetros usuais em estudos preliminares 7

1.5 Metodologia de estimativa 7

1.6 Exemplo resolvido 9

1.7 Resumo do capítulo 10

1.8 Exercícios 10

1.9 Gabarito comentado 12

1.10 Conexão com o próximo capítulo 14

2 Redes coletoras gravitárias: traçado, materiais e dimensionamento 15

2.1 Objetivos de aprendizagem 15

2.2 O papel dos coletores na hierarquia do sistema 15

2.3 Traçado da rede coletora 16

2.4 Critérios hidráulicos para dimensionamento 18

2.5 Procedimento prático de dimensionamento 21

2.6 Seleção de materiais 22

2.7 Exemplo resolvido 23

2.8 Resumo do capítulo 25

2.9 Exercícios 26

2.10 Gabarito comentado 27

2.11 Conexão com o próximo capítulo 29

3 Poços de visita, caixas de inspeção, ramais prediais e ligações à rede 30

3.1 Objetivos de aprendizagem 30

3.2 Função dos elementos de interface no sistema de esgoto 30

3.3 Poços de visita . . . 31
3.4 Caixas de inspeção . . . 33
3.5 Ramal predial e ligação predial . . . 34
3.6 Redes coletoras secundárias e organização da quadra . . . 36
3.7 Critérios de inspeção, manutenção e durabilidade . . . 37
3.8 Exemplo resolvido . . . 38
3.9 Resumo do capítulo . . . 39
3.10 Exercícios . . . 39
3.11 Gabarito comentado . . . 40
3.12 Conexão com o próximo capítulo . . . 42

II Soluções especiais de coleta e disposição . . . 43

4 Sistemas condominiais de esgoto, tanques sépticos e disposição de efluentes 44
4.1 Objetivos de aprendizagem . . . 44
4.2 Panorama das soluções de esgotamento em pequena escala . . . 45
4.3 Sistemas condominiais de esgoto . . . 45
4.4 Tanques sépticos . . . 49
4.5 Disposição e tratamento complementar dos efluentes . . . 51
4.6 Metodologia de dimensionamento didático . . . 53
4.7 Boas práticas de projeto e operação . . . 55
4.8 Exemplo resolvido . . . 56
4.9 Resumo do capítulo . . . 57
4.10 Exercícios . . . 58
4.11 Gabarito comentado . . . 59
4.12 Conexão com o próximo capítulo . . . 60

5 Estações elevatórias de esgoto bruto . . . 61
5.1 Objetivos de aprendizagem . . . 61
5.2 Função das estações elevatórias no sistema . . . 62
5.3 Configuração típica de uma elevatória . . . 63
5.4 Fundamentos hidráulicos do recalque . . . 65
5.5 Seleção de bombas . . . 67
5.6 Concepção civil, sanitária e operacional . . . 68
5.7 Manutenção e operação . . . 70
5.8 Exemplo resolvido . . . 71
5.9 Resumo do capítulo . . . 73

5.10 Exercícios . . . 73
5.11 Gabarito comentado . . . 74
5.12 Conexão com o próximo capítulo . . . 76

6 Emissários terrestres e subaquáticos . . . 77
6.1 Objetivos de aprendizagem . . . 77
6.2 Conceito e função dos emissários . . . 78
6.3 Tipos de emissário . . . 79
6.4 Fundamentos hidráulicos do transporte em emissários . . . 79
6.5 Materiais usuais em emissários . . . 82
6.6 Critérios de projeto . . . 83
6.7 Emissário subaquático: aspectos específicos . . . 84
6.8 Aspectos ambientais e de licenciamento . . . 86
6.9 Exemplo resolvido . . . 87
6.10 Resumo do capítulo . . . 89
6.11 Exercícios . . . 90
6.12 Gabarito comentado . . . 91
6.13 Conexão com o próximo capítulo . . . 93

III Operação, manutenção e reabilitação . . . 94

7 Operação, manutenção e reabilitação de redes de esgoto . . . 95
7.1 Objetivos de aprendizagem . . . 95
7.2 Operação, manutenção e reabilitação: diferenças essenciais . . . 96
7.3 Desempenho de redes de esgoto ao longo do tempo . . . 97
7.4 Principais problemas operacionais . . . 98
7.5 Rotinas de inspeção . . . 100
7.6 Limpeza e desobstrução . . . 102
7.7 Controle de infiltração e contribuições indevidas . . . 103
7.8 Segurança em operação e manutenção . . . 103
7.9 Reabilitação de redes degradadas . . . 104
7.10 Gestão operacional integrada . . . 106
7.11 Exemplo resolvido . . . 107
7.12 Resumo do capítulo . . . 108
7.13 Exercícios . . . 108
7.14 Gabarito comentado . . . 109
7.15 Encerramento e conexão final . . . 111

A Síntese de fórmulas e unidades de referência . . . 112
A.1 Objetivo do apêndice . . . 112
A.2 Unidades mais usuais . . . 112
A.3 Relações fundamentais . . . 112
A.4 Leituras rápidas de interpretação . . . 114

B Parâmetros de referência para estudos preliminares . . . 116
B.1 Finalidade do apêndice . . . 116
B.2 Parâmetros usuais de geração de esgoto . . . 116
B.3 Parâmetros hidráulicos e materiais . . . 117
B.4 Parâmetros operacionais de referência . . . 117
B.5 Quadro de leitura técnica rápida . . . 117

C Checklist de concepção e projeto . . . 119
C.1 Uso do checklist . . . 119
C.2 Levantamento inicial . . . 119
C.3 Definição da vazão . . . 119
C.4 Rede coletora . . . 120
C.5 Interface predial . . . 120
C.6 Soluções especiais . . . 120
C.7 Operação futura . . . 121

D Checklist de operação, manutenção e reabilitação . . . 122
D.1 Objetivo . . . 122
D.2 Rotina de operação . . . 122
D.3 Rotina de manutenção preventiva . . . 122
D.4 Rotina de inspeção . . . 123
D.5 Sinais de alerta . . . 123
D.6 Critérios para reabilitação . . . 123
D.7 Estratégias possíveis . . . 124
D.8 Roteiro mínimo de resposta a ocorrência . . . 124

E Quadro de normas e referências de apoio . . . 125
E.1 Uso deste quadro . . . 125
E.2 Síntese de aplicação . . . 125
E.3 Leituras recomendadas por tema . . . 125

Bibliografia . . . 127

Parte I

Bases de projeto

Capítulo 1

Geração de esgoto e vazões de projeto

1.1 Objetivos de aprendizagem

Ao final deste capítulo, o leitor deverá ser capaz de:

- diferenciar consumo de água, contribuição per capita e vazão de esgoto;
- interpretar o coeficiente de retorno e os principais fatores que alteram a geração de esgoto;
- estimar vazões médias, máximas diárias e máximas horárias para fins de projeto;
- considerar infiltração, contribuições parasitárias e lançamentos industriais na composição da vazão;
- organizar os dados de entrada necessários para o dimensionamento hidráulico dos coletores.

Observação — Posição deste capítulo na lógica do livro

Este é o capítulo de base quantitativa do livro. Todo o dimensionamento posterior de coletores, poços de visita, elevatórias e emissários depende das vazões estabelecidas aqui. Em outras palavras, uma estimativa frágil de geração de esgoto compromete toda a cadeia de projeto.

1.2 Conceitos fundamentais

1.2.1 Consumo de água e geração de esgoto

Nem toda água consumida por uma população retorna à rede coletora. Uma parcela é perdida por evaporação, lavagem de áreas externas, irrigação, incorporação em produtos, umidade em resíduos sólidos ou outros usos não lançados ao sistema de esgoto. Por isso, o consumo de água e a geração de esgoto não são grandezas idênticas.

A literatura clássica de saneamento destaca que a estimativa de vazões deve ser feita com critério local, com base em consumo observado, hábitos de uso, abastecimento disponível e

características urbanas da área atendida [1, 2]. A NBR 9649 também reforça que o projeto de redes coletoras deve adotar parâmetros coerentes com a realidade da bacia contribuinte [3].

Definição — Contribuição per capita

É o volume médio diário de esgoto gerado por cada habitante atendido, normalmente expresso em litros por habitante por dia. Representa a parcela da água consumida que efetivamente alcança a rede coletora.

Definição — Coeficiente de retorno

É a razão entre a contribuição per capita de esgoto e o consumo per capita de água. Em termos simples, indica qual fração da água consumida retorna ao sistema de esgoto.

A relação básica pode ser escrita como:

$$q_{\text{esgoto}} = C_r \, q_{\text{agua}}$$

em que:

- q_{esgoto} é a contribuição per capita de esgoto;
- C_r é o coeficiente de retorno;
- q_{agua} é o consumo per capita de água.

Atenção — Interpretação correta do coeficiente de retorno

O coeficiente de retorno não é um valor universal. Ele depende do perfil da ocupação, da renda, da presença de jardins, do hábito de lavagem de áreas externas, da existência de atividades comerciais e até da regularidade do abastecimento de água. Em áreas residenciais consolidadas, valores próximos de 0,8 são frequentemente adotados em estudos preliminares, mas o projetista deve sempre confrontar o valor com dados locais.

1.2.2 Fatores que influenciam a geração de esgoto

A vazão gerada em uma bacia urbana varia com diversos fatores:

- **densidade populacional**: áreas adensadas tendem a apresentar maior uniformidade de contribuição;
- **tipo de uso e ocupação do solo**: zonas exclusivamente residenciais, mistas ou industriais apresentam comportamentos distintos;
- **regularidade do abastecimento**: sistemas intermitentes alteram fortemente o perfil diário de vazão;
- **nível de perdas internas e usos não sanitários**: irrigação, lavagem de calçadas e limpeza podem reduzir a parcela retornada à rede;

- **hábitos culturais e padrão de consumo**: variam entre regiões e classes sociais;
- **presença de atividades econômicas**: comércio, serviços e indústrias modificam o regime de geração.

1.2.3 Esgoto doméstico, comercial e industrial

Para fins de projeto de redes coletoras, costuma-se considerar:

- **esgoto doméstico**: proveniente de residências e atividades sanitárias humanas;
- **esgoto comercial e institucional**: originado em escolas, escritórios, restaurantes, hotéis e similares;
- **esgoto industrial**: efluente decorrente de processos produtivos, que pode exigir análise específica, equalização ou pré-tratamento.

Observação — Contribuição industrial

Quando a área atendida possui atividades industriais, não basta somar uma vazão média genérica. É necessário avaliar a continuidade do processo, a variação horária, a existência de reuso interno, os volumes de lavagem e a eventual necessidade de pré-tratamento antes do lançamento na rede pública. Em muitos casos, a contribuição industrial é menos regular que a doméstica e deve ser tratada como componente próprio do sistema.

1.3 Composição das vazões de projeto

1.3.1 Vazão média

A vazão média de esgoto corresponde à soma das contribuições médias de todas as fontes relevantes na bacia.

$$Q_{\text{med}} = Q_{\text{dom,med}} + Q_{\text{ind,med}} + Q_{\text{inf}}$$

em que:

- $Q_{\text{dom,med}}$ é a vazão média doméstica;
- $Q_{\text{ind,med}}$ é a vazão média industrial ou não doméstica;
- Q_{inf} é a vazão média de infiltração e contribuições parasitárias.

Para a parcela doméstica, adota-se:

$$Q_{\text{dom,med}} = \frac{P\,q\,C_r}{86400}$$

na qual:

- P é a população atendida de projeto;
- q é o consumo per capita de água, em litros por habitante por dia;
- C_r é o coeficiente de retorno;
- 86400 é o número de segundos em um dia.

Atenção — Conversão de unidades

Se q estiver em litros por habitante por dia, o resultado de $Q_{\text{dom,med}}$ será obtido em litros por segundo. Um erro recorrente em cálculos automáticos é esquecer a divisão por 86400. Esse descuido gera vazões centenas de vezes maiores do que o real.

1.3.2 Vazão máxima diária e vazão máxima horária

O regime de esgoto não é constante ao longo do dia. Há períodos de pico associados a horários de banho, preparo de refeições, limpeza e uso de sanitários. Por isso, utiliza-se o conceito de coeficientes de variação.

Definição — Coeficiente de máxima diária

É o fator que relaciona a vazão média diária com a maior vazão diária provável do sistema.

Definição — Coeficiente de máxima horária

É o fator que relaciona a vazão média ou a vazão máxima diária com a maior vazão horária provável do sistema.

Uma formulação didática e amplamente usada em estudos preliminares é:

$$Q_{\text{max,dia}} = K_1 \, Q_{\text{med}}$$

$$Q_{\text{max,h}} = K_2 \, Q_{\text{max,dia}}$$

ou, de forma equivalente,

$$Q_{\text{max,h}} = K_1 \, K_2 \, Q_{\text{med}}$$

em que K_1 e K_2 são coeficientes de pico adotados conforme a realidade da bacia, a população atendida e os critérios do prestador de serviço.

Observação — Uso dos coeficientes de pico

Quanto menor a população, maior tende a ser a irregularidade relativa do consumo e da geração de esgoto. Portanto, trechos com pequenas populações podem apresentar picos

mais elevados em relação à média. Em redes extensas, os picos tendem a se suavizar pela própria mistura das contribuições.

1.3.3 Infiltração e contribuições parasitárias

Mesmo em sistemas bem executados, pode haver entrada de água externa para a rede, principalmente por juntas defeituosas, tubulações deterioradas, poços de visita com falhas, caixas de inspeção mal vedadas e ligações irregulares.

Definição — Infiltração

É a entrada indevida de água subterrânea na rede coletora de esgoto, em geral associada ao lençol freático e às condições de estanqueidade do sistema.

Definição — Contribuições parasitárias

São lançamentos indevidos de água na rede de esgoto, como águas de drenagem, águas pluviais conectadas irregularmente, descargas de limpeza e outras entradas não sanitárias.

De modo simplificado, a infiltração pode ser modelada por:

$$Q_{\text{inf}} = q_\ell \, L + q_a \, A$$

em que:

- q_ℓ é um coeficiente de infiltração por unidade de comprimento de rede;
- L é o comprimento da rede;
- q_a é um coeficiente por unidade de área drenada, quando aplicável;
- A é a área correspondente.

Na prática, a forma de representar a infiltração depende do método adotado pelo projeto, da disponibilidade de dados locais e das exigências do prestador. O importante é nunca desprezar esse componente em áreas com lençol freático alto, solos permeáveis ou redes antigas [5].

1.3.4 Relação entre vazões médias e de pico

A sequência lógica do dimensionamento costuma seguir esta ordem:

1. estimar a vazão média doméstica;
2. somar vazões industriais ou institucionais conhecidas;
3. incluir infiltração e contribuições parasitárias;
4. aplicar fatores de pico para obter vazões máximas;

5. adotar a vazão de projeto conforme o trecho e o critério hidráulico.

Figura 1.1: Encadeamento conceitual da estimativa de geração de esgoto.

1.4 Parâmetros usuais em estudos preliminares

A Tabela 1.1 reúne valores de referência frequentemente utilizados em estudos preliminares. Eles não substituem dados locais, mas ajudam a formar uma primeira aproximação de projeto.

Tabela 1.1: Parâmetros usuais para estimativa de geração de esgoto

Parâmetro	Faixa típica	Unidade	Observação
Consumo per capita de água q	100 L/d a 250 L/d	L/hab.d	Depende do porte urbano, clima e padrão de uso
Coeficiente de retorno C_r	0,6 a 0,9	adimensional	Valores próximos de 0,8 são comuns em estudos preliminares
Coeficiente de máxima diária K_1	1,1 a 1,5	adimensional	Aumenta a vazão média para a condição crítica diária
Coeficiente de máxima horária K_2	1,2 a 2,5	adimensional	Varia com população e regularidade do abastecimento
Infiltração Q_{inf}	conforme estudo local	L/s	Pode ser expressa por comprimento, área ou vazão global

Observação — Critério de prudência

As faixas da Tabela 1.1 são referências didáticas e não devem ser interpretadas como valores normativos universais. Quando houver dados de consumo medido, medições de vazão na rede, cadastro hidráulico confiável ou exigências da concessionária, esses dados devem prevalecer.

1.5 Metodologia de estimativa

Uma metodologia segura para estimar vazões de esgoto em um estudo de projeto é a seguinte:

Passo 1: definir a população de projeto

A população atendida deve corresponder ao horizonte de projeto do sistema ou do trecho em análise. O número de habitantes deve refletir ocupação realista, não apenas a população atual.

Passo 2: adotar o consumo per capita

Escolhe-se um valor de consumo per capita representativo da localidade. Em áreas com fornecimento contínuo e nível de renda mais elevado, os consumos tendem a ser maiores. Em áreas com abastecimento intermitente, o consumo pode oscilar de forma significativa.

Passo 3: definir o coeficiente de retorno

O coeficiente de retorno é selecionado conforme a natureza da ocupação e a presença de usos não sanitários. Quando houver dúvida, é mais seguro adotar valor conservador e justificar a escolha.

Passo 4: incluir contribuições não domésticas

Se existirem escolas, hospitais, restaurantes, instalações comerciais ou industriais, a vazão correspondente deve ser incorporada ao balanço.

Passo 5: estimar infiltração

A infiltração deve ser considerada com base em dados da concessionária, estado da rede, nível freático e características do solo.

Passo 6: aplicar fatores de pico

Por fim, aplicam-se os coeficientes de máxima diária e horária para obter a vazão de projeto mais crítica para o trecho.

Atenção — Erro conceitual frequente

Não se deve aplicar coeficientes de pico duas vezes. Primeiro, calcula-se a vazão média. Depois, uma única vez, aplicam-se os fatores de variação definidos pelo critério do projeto. Repetir a amplificação em cascata produz superdimensionamento e distorce todo o sistema.

1.6 Exemplo resolvido

Exemplo — Estimativa de vazões para um setor urbano

Considere um setor urbano com as seguintes características:

- população de projeto: $P = 18\,000$ habitantes;
- consumo per capita de água: $q =$ 180 L/hab.d;
- coeficiente de retorno: $C_r = 0{,}80$;
- contribuição industrial média: $Q_{\text{ind,med}} = 4\,\text{L/s}$;
- infiltração média: $Q_{\text{inf}} = 2{,}5\,\text{L/s}$;
- coeficiente de máxima diária: $K_1 = 1{,}20$;
- coeficiente de máxima horária: $K_2 = 1{,}50$.

1. Vazão média doméstica

$$Q_{\text{dom,med}} = \frac{P\,q\,C_r}{86400}$$

Substituindo os valores:

$$Q_{\text{dom,med}} = \frac{18\,000 \times 180 \times 0{,}80}{86400}$$

$$Q_{\text{dom,med}} = 30\,\text{L/s}$$

2. Vazão média total

$$Q_{\text{med}} = Q_{\text{dom,med}} + Q_{\text{ind,med}} + Q_{\text{inf}}$$

$$Q_{\text{med}} = 30 + 4 + 2{,}5$$

$$Q_{\text{med}} = 36{,}5\,\text{L/s}$$

3. Vazão máxima diária

$$Q_{\text{max,dia}} = K_1\,Q_{\text{med}}$$

$$Q_{\text{max,dia}} = 1{,}20 \times 36{,}5$$

$$Q_{\text{max,dia}} = 43{,}8\,\text{L/s}$$

4. Vazão máxima horária

$$Q_{\text{max,h}} = K_2\,Q_{\text{max,dia}}$$

$$Q_{\text{max,h}} = 1{,}50 \times 43{,}8$$

$$Q_{\text{max,h}} = 65{,}7\,\text{L/s}$$

Resultado final

Para esse setor, a vazão média de esgoto é de 36,5 L/s e a vazão máxima horária é de 65,7 L/s. Em um trecho crítico de coletor, esse último valor tende a ser o mais relevante para a verificação hidráulica preliminar.

1.7 Resumo do capítulo

Resumo — Ideias centrais

- A geração de esgoto depende do consumo de água, do coeficiente de retorno e das características da ocupação.
- A contribuição per capita é uma grandeza média de referência, não um valor fixo e universal.
- A vazão média deve incluir parcelas domésticas, industriais e infiltração.
- A vazão de projeto para trechos críticos costuma ser obtida pela aplicação de coeficientes de máxima diária e horária.
- Infiltração e contribuições parasitárias podem alterar de modo significativo a vazão noturna e a vazão média do sistema.
- Dados locais, cadastro confiável e critérios da concessionária são sempre preferíveis a valores genéricos.

1.8 Exercícios

1.8.1 Exercícios F

1. Defina contribuição per capita e explique por que ela é menor, em geral, do que o consumo per capita de água.

2. Cite três fatores que podem reduzir o coeficiente de retorno de uma área urbana.

3. Por que a vazão máxima horária é mais importante do que a vazão média no dimensionamento de muitos trechos de rede?

1.8.2 Exercícios M

1. Uma localidade possui $P = 12\,000$ habitantes, consumo per capita de $q =$ 150 L/hab.d, coeficiente de retorno $C_r = 0{,}75$, infiltração média $Q_{\text{inf}} = 1{,}5\,\text{L/s}$, $K_1 = 1{,}20$ e $K_2 = 1{,}40$. Calcule $Q_{\text{dom,med}}$, Q_{med}, $Q_{\text{max,dia}}$ e $Q_{\text{max,h}}$.

2. Um bairro com $2\,500$ habitantes apresenta consumo per capita de $q =$ 170 L/hab.d e coeficiente de retorno $C_r = 0{,}80$. Sabendo que a infiltração média é de 0,7 L/s e que há uma contribuição institucional média de 0,5 L/s, estime a vazão média total.

3. Um sistema possui 6 km de rede principal e 2 km de rede secundária. Adotando coeficientes de infiltração de 0,25 L/(s km) para a rede principal e 0,15 L/(s km) para a rede secundária, determine a infiltração total.

1.8.3 Exercícios D

1. Em uma área urbana mista, a população de projeto é de $20\,000$ habitantes. O consumo per capita é de $q =$ 160 L/hab.d, o coeficiente de retorno é $C_r = 0{,}78$, a contribuição industrial média é de 6 L/s, a infiltração média é de 4 L/s, $K_1 = 1{,}15$ e $K_2 = 1{,}45$. Calcule a vazão média, a vazão máxima diária e a vazão máxima horária.

2. Compare dois setores urbanos:

   - Setor A: $P = 10\,000$, $q =$ 140 L/hab.d, $C_r = 0{,}85$, $Q_{\text{inf}} = 1{,}2\,\text{L/s}$, $K_1 = 1{,}20$, $K_2 = 1{,}50$;
   - Setor B: $P = 6\,000$, $q =$ 190 L/hab.d, $C_r = 0{,}70$, $Q_{\text{inf}} = 0{,}8\,\text{L/s}$, $K_1 = 1{,}15$, $K_2 = 1{,}40$.

   Determine qual setor apresenta maior vazão máxima horária.

3. Explique como a presença de infiltração elevada e de ligações clandestinas pode alterar o projeto de um sistema coletor e indique duas medidas de projeto e duas medidas de operação para reduzir esse problema.

1.9 Gabarito comentado

Gabarito comentado — Respostas comentadas

Exercícios F

1. **Resposta esperada:** contribuição per capita é o volume médio de esgoto gerado por habitante por dia. Ela é menor do que o consumo de água porque parte da água consumida não retorna à rede, seja por evaporação, irrigação, incorporação em produtos ou outros usos não sanitários. A resposta deve mencionar a relação com o coeficiente de retorno.

2. **Resposta esperada:** três fatores possíveis são: irrigação de jardins e lavagem externa; perdas e usos não lançados à rede; abastecimento intermitente; presença de atividades comerciais; hábitos de consumo local; climas quentes e secos. Qualquer trio coerente com a lógica do coeficiente de retorno é aceitável.

3. **Resposta esperada:** porque os picos horários representam a condição mais crítica de solicitação hidráulica em vários trechos da rede. A vazão média pode ser insuficiente para revelar sobrecarga em horários de maior concentração de uso; por isso, o projeto deve considerar o pico e não apenas a média.

Exercícios M

1. **Cálculo:**

$$Q_{\text{dom,med}} = \frac{12\,000 \times 150 \times 0{,}75}{86400} = 15{,}625\ \text{L/s}$$

$$Q_{\text{med}} = 15{,}625 + 1{,}5 = 17{,}125\ \text{L/s}$$

$$Q_{\text{max,dia}} = 1{,}20 \times 17{,}125 = 20{,}55\ \text{L/s}$$

$$Q_{\text{max,h}} = 1{,}40 \times 20{,}55 = 28{,}77\ \text{L/s}$$

Resposta final: $Q_{\text{dom,med}} = 15{,}625\ \text{L/s}$, $Q_{\text{med}} = 17{,}125\ \text{L/s}$, $Q_{\text{max,dia}} = 20{,}55\ \text{L/s}$ e $Q_{\text{max,h}} = 28{,}77\ \text{L/s}$.

2. **Cálculo:**

$$Q_{\text{dom,med}} = \frac{2\,500 \times 170 \times 0{,}80}{86400} = 3{,}935\ \text{L/s}$$

$$Q_{\text{med}} = 3{,}935 + 0{,}7 + 0{,}5 = 5{,}135\,\text{L/s}$$

Resposta final: a vazão média total é de aproximadamente 5,14 L/s.

3. **Cálculo:**

$$Q_{\text{inf}} = 6 \times 0{,}25 + 2 \times 0{,}15$$

$$Q_{\text{inf}} = 1{,}5 + 0{,}3 = 1{,}8\,\text{L/s}$$

Resposta final: a infiltração total é de 1,8 L/s.

Exercícios D

1. **Cálculo:**

$$Q_{\text{dom,med}} = \frac{20\,000 \times 160 \times 0{,}78}{86400} = 28{,}889\,\text{L/s}$$

$$Q_{\text{med}} = 28{,}889 + 6 + 4 = 38{,}889\,\text{L/s}$$

$$Q_{\text{max,dia}} = 1{,}15 \times 38{,}889 = 44{,}722\,\text{L/s}$$

$$Q_{\text{max,h}} = 1{,}45 \times 44{,}722 = 64{,}842\,\text{L/s}$$

Resposta final: $Q_{\text{med}} \approx 38{,}9\,\text{L/s}$, $Q_{\text{max,dia}} \approx 44{,}7\,\text{L/s}$ e $Q_{\text{max,h}} \approx 64{,}8\,\text{L/s}$.

2. **Cálculo do setor A:**

$$Q_{\text{dom,med,A}} = \frac{10\,000 \times 140 \times 0{,}85}{86400} = 13{,}773\,\text{L/s}$$

$$Q_{\text{med,A}} = 13{,}773 + 1{,}2 = 14{,}973\,\text{L/s}$$

$$Q_{\text{max,h,A}} = 1{,}50 \times 1{,}20 \times 14{,}973 = 26{,}951\,\text{L/s}$$

Cálculo do setor B:

$$Q_{\text{dom,med,B}} = \frac{6\,000 \times 190 \times 0{,}70}{86400} = 9{,}236\ \text{L/s}$$

$$Q_{\text{med,B}} = 9{,}236 + 0{,}8 = 10{,}036\ \text{L/s}$$

$$Q_{\text{max,h,B}} = 1{,}40 \times 1{,}15 \times 10{,}036 = 16{,}451\ \text{L/s}$$

Resposta final: o setor A apresenta maior vazão máxima horária, com aproximadamente 26,95 L/s, contra 16,45 L/s no setor B. Apesar de o setor B ter maior consumo per capita, o conjunto população $\times$ coeficiente de retorno $\times$ fatores de pico resulta em vazão crítica inferior.

3. **Resposta esperada:** infiltração elevada e ligações clandestinas aumentam a vazão transportada, podem sobrecarregar trechos em tempo seco, reduzir a margem hidráulica, provocar extravasamentos e elevar custos operacionais. Entre as medidas de projeto, devem ser citadas: seleção adequada de materiais e juntas; detalhamento de poços de visita e caixas com boa estanqueidade; setorização e controle do comprimento de rede; previsão de inspeção e manutenção. Entre as medidas operacionais, podem ser citadas: inspeções regulares com CFTV ou testes de fumaça; controle e correção de ligações indevidas; limpeza programada; campanhas de fiscalização e educação sanitária. A resposta deve evidenciar que o problema não é apenas hidráulico, mas também construtivo e de gestão.

1.10 Conexão com o próximo capítulo

Observação — Ponte para o Capítulo 2

As vazões estimadas neste capítulo serão a base para o dimensionamento dos coletores gravitários. No próximo capítulo, essas vazões serão combinadas com critérios de declividade, velocidade de autolimpeza, diâmetro mínimo, materiais e restrições construtivas para transformar a estimativa de geração em uma rede funcional e economicamente viável.

Capítulo 2

Redes coletoras gravitárias: traçado, materiais e dimensionamento

2.1 Objetivos de aprendizagem

Ao final deste capítulo, o leitor deverá ser capaz de:

- compreender a função dos coletores na hierarquia de um sistema de esgotamento sanitário;
- definir critérios de traçado para redes gravitárias em áreas urbanas;
- dimensionar, em nível preliminar e executivo, trechos de coletor com base na vazão de projeto;
- aplicar a equação de Manning ao escoamento em condutos livres e interpretar suas limitações;
- selecionar materiais adequados para coletores em função de desempenho hidráulico, durabilidade e ambiente de instalação;
- reconhecer os principais critérios de projeto associados à NBR 9649 [3].

Observação — Relação com o capítulo anterior

No capítulo anterior, a vazão de esgoto foi estimada a partir da população, do consumo per capita, dos coeficientes de retorno e das parcelas não domésticas. Aqui, essa vazão passa a ser convertida em uma rede física, por gravidade, com diâmetro, declividade, material e traçado coerentes.

2.2 O papel dos coletores na hierarquia do sistema

Em um sistema público de esgotamento sanitário, a rede não é homogênea. Ela se organiza em níveis funcionais, cada qual com uma responsabilidade hidráulica e operacional distinta.

Tabela 2.1: Hierarquia simplificada de condução do esgoto em sistemas gravitários

Elemento	Função principal	Observação de projeto
Coletor secundário	Recebe contribuições locais de trechos menores e conduz o esgoto até trechos de maior porte.	É o componente mais próximo da ocupação urbana e, em geral, o mais sensível a interferências de traçado e manutenção.
Coletor-tronco	Recebe vazões de vários coletores secundários e conduz o fluxo em direção ao interceptor, à elevatória ou ao emissário.	Exige maior atenção à acumulação de vazões e ao crescimento progressivo do diâmetro.
Interceptor	Intercepta descargas ao longo de uma faixa urbana ou marginal de corpo d'água e conduz o esgoto para tratamento.	Normalmente é um elemento de maior porte e com implicações topográficas e ambientais relevantes.

Definição — Coletor de esgoto

É a tubulação pública destinada a receber e conduzir esgoto sanitário por gravidade, transportando as contribuições de trechos menores até componentes de maior capacidade, como coletores-tronco, elevatórias, interceptores ou emissários.

Observação — Coletor não é ligação predial

O coletor público não deve ser confundido com a ligação predial nem com o ramal interno do imóvel. Esses elementos pertencem a uma escala distinta e serão tratados no próximo capítulo. Aqui, o foco é a rede pública propriamente dita.

2.3 Traçado da rede coletora

2.3.1 Princípios gerais de implantação

O traçado de uma rede coletora gravitária deve buscar o melhor compromisso entre eficiência hidráulica, facilidade construtiva, custo de implantação e confiabilidade operacional. Em termos práticos, o projeto deve procurar:

- aproveitar a declividade natural do terreno;
- reduzir ao mínimo as profundidades excessivas de vala;
- diminuir o número de mudanças bruscas de direção;
- facilitar acesso para inspeção e manutenção;
- evitar áreas de difícil escavação ou com interferências intensas;
- compatibilizar a rede com vias públicas, outros serviços e estruturas urbanas;
- assegurar continuidade hidráulica sem trechos mortos ou pontos de acúmulo indevido [1, 5].

Atenção — Regra de ouro do traçado

A rede coletora deve seguir a lógica da gravidade, e não forçar o terreno a se adaptar à tubulação. Quando o traçado ignora a topografia, o resultado costuma ser profundidade excessiva, maior custo de escavação, maior risco de recalque e pior desempenho de manutenção.

2.3.2 Critérios urbanísticos e topográficos

Na prática, o traçado é definido a partir de um conjunto de condicionantes:

- **topografia**: a rede deve acompanhar preferencialmente as linhas de menor cota das quadras e vias;
- **traçado viário**: em geral, a implantação sob o eixo da rua facilita a padronização de servidões e o acesso à manutenção;
- **drenagem e interferências**: galerias pluviais, adutoras, redes elétricas, gás e telecomunicações podem impor desvios;
- **ocupação do solo**: áreas densas, industriais ou institucionais podem exigir trechos de maior capacidade;
- **restrições ambientais**: travessias de cursos d'água, áreas alagáveis e encostas pedem análise específica;
- **expansão futura**: o traçado deve permitir ampliação coerente com o crescimento da bacia contribuinte.

2.3.3 Estratégia de traçado em planta e em perfil

Em um projeto bem concebido, o traçado deve ser estudado em dois planos complementares:

- **em planta**: define-se o caminho horizontal da tubulação, a sequência dos trechos e os pontos de coleta;
- **em perfil**: define-se a declividade, a profundidade e a compatibilização com o relevo e com os demais serviços enterrados.

A figura a seguir ilustra, de forma simplificada, a hierarquia de condução em um setor urbano.

2.3.4 Evitar traçados problemáticos

Alguns traçados parecem economicamente vantajosos no curto prazo, mas geram problemas no ciclo de vida do sistema. Devem ser evitados, sempre que possível:

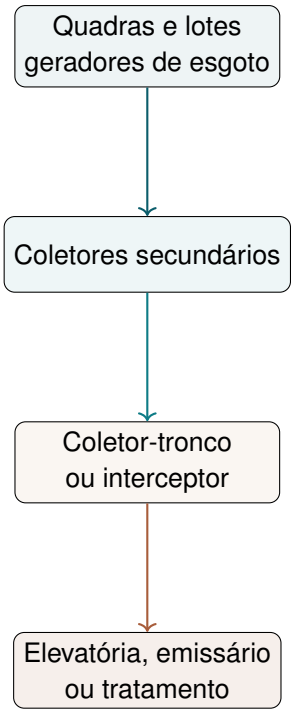

Figura 2.1: Fluxo conceitual de condução em um sistema gravitário.

- longos trechos com grandes profundidades sem justificativa técnica;
- muitas mudanças de direção em curtas distâncias;
- troncos que atravessam propriedades privadas sem servidão adequada;
- passagens sob estruturas com difícil acesso para manutenção;
- soluções que dependem de extrapolações hidráulicas sem dados confiáveis.

2.4 Critérios hidráulicos para dimensionamento

2.4.1 Premissa fundamental

O dimensionamento de um coletor parte da vazão de projeto do trecho, obtida pela soma das contribuições a montante. Em cada ponto da rede, a vazão tende a crescer conforme novos usuários e novas áreas se conectam. Assim, o projetista deve trabalhar por trechos e não por uma vazão única para toda a cidade.

Observação — Acúmulo progressivo de vazões

A vazão no trecho mais a montante pode ser pequena, mas o somatório de vários trechos gera, a jusante, uma demanda consideravelmente maior. Esse acúmulo exige revisão contínua do diâmetro, da declividade e da capacidade de transporte ao longo da rede.

2.4.2 Equação de Manning

Para escoamentos livres em condutos, a relação hidráulica clássica é dada pela equação de Manning:

$$Q = \frac{1}{n} A\, R^{2/3}\, S^{1/2}$$

em que:

- Q é a vazão;
- n é o coeficiente de rugosidade de Manning;
- A é a área molhada;
- R é o raio hidráulico, isto é, $R = A/P$;
- P é o perímetro molhado;
- S é a declividade da linha de energia, que, em regime uniforme, pode ser aproximada pela declividade do fundo do tubo.

Para uma tubulação circular em escoamento a seção cheia:

$$A = \frac{\pi D^2}{4} \qquad \text{e} \qquad R = \frac{D}{4}$$

Substituindo na equação de Manning, obtém-se:

$$Q = \frac{\pi}{4^{5/3}} \frac{1}{n} D^{8/3}\, S^{1/2}$$

Essa forma é muito útil no pré-dimensionamento porque evidencia três efeitos importantes:

- a capacidade cresce fortemente com o diâmetro;
- a capacidade aumenta com a declividade;
- a capacidade melhora quando a rugosidade é menor.

2.4.3 Escoamento parcialmente cheio

Em redes sanitárias, o coletor normalmente opera em regime parcialmente cheio. Isso é desejável por vários motivos:

- favorece a aeração do escoamento;
- permite absorver variações de vazão ao longo do dia;
- reduz a probabilidade de pressurização indevida;
- cria margem operacional para picos não previstos.

Para a verificação mais rigorosa em seção parcialmente cheia, podem ser usadas tabelas, ábacos ou softwares que relacionam:

$$\frac{Q}{Q_{\text{cheio}}}, \qquad \frac{V}{V_{\text{cheio}}}, \qquad \frac{y}{D}$$

onde y/D é a relação entre lâmina escoada e diâmetro da tubulação.

Atenção — Uso correto da fórmula de Manning

A equação de Manning é adequada para verificar a capacidade hidráulica, mas não substitui o julgamento de projeto. Em redes sanitárias, o projetista deve considerar a condição parcial de escoamento, a autolimpeza, a durabilidade do material e a compatibilidade com a operação futura [3, 1].

2.4.4 Velocidade, autolimpeza e limitação de desgaste

O desempenho hidráulico do coletor não depende apenas da vazão. A velocidade média também importa, pois ela interfere na deposição de sólidos e na abrasão do material.

Em termos didáticos, o projeto deve buscar:

- velocidade suficiente para evitar deposição de sólidos sedimentáveis;
- velocidade não excessiva, para não provocar desgaste ou danos em materiais sensíveis;
- estabilidade do escoamento ao longo da rede;
- compatibilidade entre declividade disponível e vazão transportada.

Observação — Autolimpeza

A ideia de autolimpeza refere-se à capacidade do escoamento de transportar os sólidos sem formação persistente de depósitos. Em esgoto sanitário, esse critério é especialmente importante em trechos com pequena vazão noturna, baixa declividade ou material com rugosidade mais elevada.

2.4.5 Parâmetros práticos de projeto

Embora os valores exatos dependam da concessionária, do solo e do porte do sistema, alguns parâmetros são comumente adotados como referência preliminar:

Observação — Valores de referência

Os números da Tabela 2.2 são faixas típicas de engenharia e não substituem o caderno de encargos da concessionária nem o projeto executivo com especificação de fabricante.

Tabela 2.2: Parâmetros hidráulicos e de seleção usados como referência preliminar

Grandeza	Faixa típica	Unidade	Comentário
Diâmetro nominal mínimo	100 mm	mm	Valor usual para redes coletoras públicas em projetos urbanos, sujeito a diretriz local.
Rugosidade de PVC ou PEAD	0,009 a 0,011	–	Tubos lisos, com bom desempenho hidráulico.
Rugosidade de concreto	0,011 a 0,013	–	Dependente da qualidade interna e de eventual revestimento.
Rugosidade de cerâmica vitrificada	0,010 a 0,013	–	Boa resistência química, mas uso menos frequente em redes modernas.
Rugosidade de PRFV	0,009 a 0,011	–	Bom compromisso entre leveza, resistência química e desempenho hidráulico.

2.5 Procedimento prático de dimensionamento

Um roteiro seguro para o dimensionamento de um coletor gravitário é o seguinte:

1. **definir o trecho**: identificar início, fim e área contribuinte;
2. **calcular a vazão de projeto**: usar o resultado obtido no capítulo anterior, acumulando contribuições locais e a montante;
3. **estudar o traçado**: verificar a faixa viária, as interferências e a declividade disponível;
4. **escolher o material**: considerar resistência química, rigidez, facilidade de assentamento e custo;
5. **assumir uma declividade preliminar**: compatível com o relevo e com a profundidade admissível;
6. **dimensionar o diâmetro**: usar a equação de Manning, inicialmente em aproximação conservadora;
7. **verificar a condição parcial**: conferir a faixa de operação real do tubo;
8. **avaliar velocidades**: garantir autolimpeza e evitar erosão;
9. **ajustar o projeto**: se necessário, alterar diâmetro, declividade ou material;
10. **documentar a solução**: registrar memória de cálculo e justificativas.

2.6 Seleção de materiais

A escolha do material da tubulação é uma decisão central no projeto. Não existe um material universalmente superior; existe o material mais adequado ao contexto.

2.6.1 Critérios de seleção

Os critérios mais relevantes são:

- **desempenho hidráulico**: menor rugosidade significa menor perda de capacidade;
- **resistência química**: o esgoto pode gerar ambientes com sulfeto de hidrogênio e corrosão ácida;
- **resistência estrutural**: cargas de solo e tráfego devem ser suportadas com segurança;
- **estanqueidade**: juntas e conexões devem minimizar infiltração e exfiltração;
- **facilidade construtiva**: transporte, corte, assentamento e inspeção devem ser viáveis;
- **durabilidade**: a vida útil esperada deve ser compatível com o investimento;
- **compatibilidade com o ambiente**: solos agressivos, lençol freático e áreas alagáveis pedem atenção especial.

2.6.2 Materiais usuais

Observação — Corrosão por sulfetos

Em sistemas com baixa ventilação, presença de tempo de detenção elevado ou trechos sujeitos à septicidade, o sulfeto de hidrogênio pode gerar corrosão interna severa, sobretudo em materiais cimentícios sem proteção. Em tais casos, o material e o revestimento interno tornam-se decisivos para a vida útil do sistema.

2.6.3 Compatibilização entre material e declividade

A escolha do material não deve ser feita isoladamente. Um tubo com baixa rugosidade permite, em geral, maior capacidade para a mesma declividade. Por outro lado, materiais muito lisos não eliminam a necessidade de uma declividade mínima funcional.

Em síntese:

- materiais mais lisos favorecem capacidade hidráulica;
- materiais mais robustos podem ser necessários em trechos profundos ou sujeitos a cargas elevadas;
- materiais com melhor resistência química são desejáveis em ambientes agressivos;

Tabela 2.3: Materiais usuais em coletores de esgoto: características e aplicações

Material	Vantagens	Limitações	Aplicação típica
PVC rígido	Baixa rugosidade, leveza, boa estanqueidade, fácil assentamento	Sensível a temperaturas elevadas e a danos por compactação inadequada	Redes urbanas de pequeno e médio porte
PEAD	Flexibilidade, soldagem por termofusão, bom desempenho em travessias e métodos não destrutivos	Exige controle rigoroso de instalação e especificação correta de juntas e ancoragens	Trechos especiais, travessias, áreas agressivas e obras com restrição de vala
PRFV	Boa resistência química, leveza e desempenho hidráulico favorável	Custo e especificação mais dependentes de projeto e fabricante	Coletores e interceptores com demandas especiais
Concreto	Boa resistência estrutural e uso em grandes diâmetros	Pode sofrer corrosão por sulfetos se não houver proteção adequada	Interceptores, troncos e grandes coletores
Cerâmica vitrificada	Excelente resistência química e boa durabilidade	Menor disponibilidade comercial em alguns mercados	Situações específicas ou redes antigas

- o custo inicial não deve ser avaliado sem considerar a manutenção e a durabilidade.

2.7 Exemplo resolvido

Exemplo — Pré-dimensionamento de um coletor público

Considere um trecho de coletor com vazão máxima horária de projeto igual a 65,7 L/s, obtida no capítulo anterior. Adote:

- declividade do trecho: $S = 0{,}005$ ou 0,5 %;
- coeficiente de Manning para o material: $n = 0{,}011$;
- regime de escoamento para verificação preliminar: seção cheia, de forma conservadora.

1. Fórmula de projeto para seção cheia

$$Q = \frac{\pi}{4^{5/3}} \frac{1}{n} D^{8/3} S^{1/2}$$

Isolando o diâmetro:

$$D = \left(\frac{4^{5/3}\, n\, Q}{\pi\, S^{1/2}} \right)^{3/8}$$

2. Substituição numérica

Como $Q = 0{,}065\,7\ \mathrm{m^3/s}$, $n = 0{,}011$ e $S = 0{,}005$:

$$D = \left(\frac{4^{5/3} \times 0{,}011 \times 0{,}0657}{\pi \times \sqrt{0{,}005}} \right)^{3/8}$$

$$D \approx 0{,}264\ \mathrm{m}$$

3. Escolha do diâmetro nominal

Adota-se o diâmetro comercial imediatamente superior:

$$D_N = 300\ \mathrm{mm}$$

4. Verificação da capacidade hidráulica do diâmetro escolhido

Para $D = 0{,}30\ \mathrm{m}$, a área cheia é:

$$A = \frac{\pi D^2}{4} = \frac{\pi \times 0{,}30^2}{4} \approx 0{,}070\,7\ \mathrm{m^2}$$

O raio hidráulico em seção cheia é:

$$R = \frac{D}{4} = 0{,}075\ \mathrm{m}$$

Pela equação de Manning:

$$Q = \frac{1}{0{,}011} \times 0{,}0707 \times 0{,}075^{2/3} \times 0{,}005^{1/2}$$

$$Q \approx 0{,}080\,8\ \mathrm{m^3/s}$$

ou:

$$Q \approx 80{,}8\ \mathrm{L/s}$$

5. Interpretação

A capacidade estimada do tubo de 300 mm supera a vazão máxima horária de projeto, que é de 65,7 L/s. Portanto, o diâmetro é tecnicamente aceitável para o pré-dimensionamento. Em projeto executivo, ainda seria necessário verificar a condição parcial de escoamento, as profundidades, as interferências e a compatibilidade com os trechos adjacentes.

6. Observação complementar

Se se tentasse usar um diâmetro menor, por exemplo 250 mm, a capacidade ficaria significativamente mais baixa e possivelmente insuficiente para o trecho. Isso ilustra o efeito muito forte do diâmetro sobre a vazão transportável.

2.7.1 Capacidades comparativas para a mesma declividade

A tabela a seguir mostra, para fins didáticos, a capacidade aproximada de alguns diâmetros comerciais na mesma declividade e com o mesmo coeficiente de rugosidade do exemplo.

Tabela 2.4: Capacidade aproximada em seção cheia para $S = 0{,}005$ e $n = 0{,}011$

Diâmetro nominal	Capacidade aproximada	Velocidade média	Comentário
200 mm	27 L/s	0,86 m/s	Insuficiente para a vazão do exemplo.
250 mm	49 L/s	1,01 m/s	Ainda abaixo da vazão máxima horária do exemplo.
300 mm	81 L/s	1,14 m/s	Atende com margem hidráulica.

2.8 Resumo do capítulo

Resumo — Ideias centrais

- Os coletores são o núcleo da rede pública de esgoto em regime gravitário.
- Um traçado eficiente acompanha a topografia, reduz interferências e facilita manutenção.
- A vazão do trecho cresce progressivamente ao longo da rede e deve ser verificada por segmentos.
- A equação de Manning é a base da verificação hidráulica, mas deve ser interpretada em conjunto com o escoamento parcialmente cheio.
- A autolimpeza é um critério essencial para a operação estável do coletor.
- O material deve ser escolhido pela combinação entre rugosidade, resistência química, resistência estrutural, estanqueidade e durabilidade.
- PVC, PEAD, PRFV, concreto e cerâmica vitrificada têm perfis de uso distintos e não são intercambiáveis sem análise técnica.

2.9 Exercícios

2.9.1 Exercícios F

1. Explique a diferença entre coletor secundário, coletor-tronco e interceptor.

2. Por que um traçado que segue a topografia costuma ser mais econômico e confiável do que um traçado que ignora o relevo?

3. Cite quatro critérios que devem orientar a escolha do material de uma tubulação coletora.

2.9.2 Exercícios M

1. Um trecho de rede deve transportar 32 L/s. Adotando $n = 0{,}011$ e $S = 0{,}004$, estime o diâmetro necessário em seção cheia pela equação de Manning e escolha um diâmetro nominal comercial.

2. Verifique a capacidade aproximada de um tubo de 250 mm com $n = 0{,}011$ e $S = 0{,}004$. Compare com a vazão do item anterior.

3. Compare, para um mesmo diâmetro de 300 mm e declividade de 0,4 %, a diferença de capacidade entre um tubo de PVC com $n = 0{,}011$ e um tubo de concreto com $n = 0{,}013$.

2.9.3 Exercícios D

1. Um setor urbano possui três trechos consecutivos de coletor. Os trechos recebem, respectivamente, vazões máximas horárias de 12 L/s, 18 L/s e 24 L/s adicionais ao longo do percurso. Adote $S = 0{,}005$ e $n = 0{,}011$. Determine a vazão de projeto em cada trecho, escolha diâmetros nominais adequados e justifique a evolução dos diâmetros.

2. Uma rua apresenta declividade natural muito baixa, o que limitaria o escoamento gravitário. Discuta, do ponto de vista de concepção, quais alternativas podem ser estudadas antes de decidir por uma solução elevatória.

3. Em um projeto preliminar, o coletor de jusante foi subdimensionado e passou a operar com sobrecarga frequente. Explique quais consequências hidráulicas, operacionais e sanitárias isso pode provocar e proponha medidas corretivas.

2.10 Gabarito comentado

Gabarito comentado — Respostas comentadas

Exercícios F

1. **Resposta esperada:** o coletor secundário recebe contribuições locais; o coletor-tronco agrega vazões de vários coletores secundários; o interceptor conduz grandes volumes ao longo de uma faixa da cidade, em geral rumo ao tratamento. A resposta deve mostrar a lógica de hierarquia crescente de vazão e responsabilidade.

2. **Resposta esperada:** porque o traçado que acompanha o relevo reduz a necessidade de grandes escavações, diminui profundidades excessivas, reduz interferências e melhora a confiabilidade hidráulica. Quando o traçado ignora a topografia, aumentam custo, risco de conflito com outras redes e complexidade de manutenção.

3. **Resposta esperada:** pelo menos quatro entre: rugosidade hidráulica, resistência química, resistência estrutural, estanqueidade, custo, facilidade construtiva, durabilidade, compatibilidade com o solo e com a profundidade de assentamento.

Exercícios M

1. **Cálculo do diâmetro:**

   Pela equação de Manning em seção cheia,

$$D = \left(\frac{4^{5/3}\, n\, Q}{\pi\, S^{1/2}} \right)^{3/8}$$

   Substituindo $Q = 0{,}032\,\mathrm{m^3/s}$, $n = 0{,}011$ e $S = 0{,}004$:

$$D \approx 0{,}226\,\mathrm{m}$$

   Resposta final: o diâmetro calculado é da ordem de 225 mm; como diâmetro comercial, adota-se usualmente 250 mm.

2. **Cálculo da capacidade do tubo de 250 mm:**

$$A = \frac{\pi \times 0{,}25^2}{4} \approx 0{,}049\,1\,\mathrm{m^2}$$

$$R = \frac{0{,}25}{4} = 0{,}062\,5\,\mathrm{m}$$

$$Q = \frac{1}{0{,}011} \times 0{,}0491 \times 0{,}0625^{2/3} \times 0{,}004^{1/2}$$

$$Q \approx 0{,}034\,1\ \mathrm{m^3/s}$$

ou:

$$Q \approx 34{,}1\ \mathrm{L/s}$$

Resposta final: a capacidade é ligeiramente superior à vazão solicitada de 32 L/s, portanto o tubo de 250 mm é aceitável no pré-dimensionamento.

3. **Comparação de materiais:**

   Para o mesmo diâmetro e a mesma declividade, a capacidade é inversamente proporcional a n. Assim,

$$\frac{Q_{\text{PVC}}}{Q_{\text{concreto}}} = \frac{0{,}013}{0{,}011} \approx 1{,}18$$

   Isso significa que o tubo de PVC transporta cerca de 18% mais vazão do que o tubo de concreto nas mesmas condições geométricas.

   Resposta final: a capacidade do PVC é maior; o concreto, por ter rugosidade superior, oferece menor vazão transportável para a mesma declividade.

Exercícios D

1. **Procedimento esperado:** as vazões devem ser acumuladas trecho a trecho.

   - Trecho 1: $Q_1 = 12\ \mathrm{L/s}$
   - Trecho 2: $Q_2 = 12\ \mathrm{L/s} + 18\ \mathrm{L/s} = 30\ \mathrm{L/s}$
   - Trecho 3: $Q_3 = 30\ \mathrm{L/s} + 24\ \mathrm{L/s} = 54\ \mathrm{L/s}$

   Em seguida, cada trecho deve ser verificado pela equação de Manning, com diâmetro crescente conforme a vazão aumenta. Em uma solução típica, o primeiro trecho pode ser atendido por 200 mm ou 250 mm, o segundo por 250 mm ou 300 mm, e o terceiro por 300 mm ou superior, conforme a verificação hidráulica e as restrições locais. O essencial é justificar a progressão dos diâmetros pelo acúmulo de vazão e pela limitação de capacidade.

2. **Resposta esperada:** antes de recorrer a uma elevatória, o projetista deve examinar alternativas como ajuste do traçado, remanejamento do ponto de coleta, alteração de

cota de assentamento, uso de interceptores em outra linha de drenagem, redistribuição de áreas contribuintes ou até reorganização da bacia por setores. A resposta deve mostrar que a elevatória é uma solução de última instância técnica, e não a primeira opção.

3. **Resposta esperada:** um coletor subdimensionado pode provocar redução de margem hidráulica, extravasamentos, retorno de esgoto, aumento de deposição de sólidos, odores, maior frequência de limpeza e risco sanitário. Medidas corretivas incluem redimensionamento do trecho, implantação de paralelo, aumento de declividade quando possível, redução de entradas indevidas, e readequação da setorização da rede. Em casos críticos, pode ser necessária intervenção estrutural e operacional simultânea.

2.11 Conexão com o próximo capítulo

Observação — Ponte para o Capítulo 3

Neste capítulo, a rede foi tratada como um sistema de condução gravitária composto por traçado, declividade, material e diâmetro. No próximo capítulo, a atenção se desloca para os elementos que viabilizam a inspeção, a transição e a interface entre o sistema público e as conexões individuais: poços de visita, caixas de inspeção e ramais prediais. Esses componentes são decisivos para a operação e para a durabilidade da rede.

Capítulo 3

Poços de visita, caixas de inspeção, ramais prediais e ligações à rede

3.1 Objetivos de aprendizagem

Ao final deste capítulo, o leitor deverá ser capaz de:

- distinguir poços de visita, caixas de inspeção, ramais prediais e ligações prediais;
- compreender a função desses elementos na operação e na manutenção do sistema;
- definir critérios básicos para implantação de interfaces entre o lote e a rede pública;
- reconhecer situações em que mudanças de direção, declividade ou diâmetro devem ser acomodadas em poços de visita;
- aplicar critérios práticos para conexão de edificações à rede coletora;
- projetar, em nível preliminar, a transição geométrica entre o imóvel e o coletor público [3, 1, 5].

Observação — Relação com os capítulos anteriores e posteriores

No capítulo anterior, a rede foi tratada como um sistema gravitário composto por traçado, declividade, material e diâmetro. Aqui, o foco recai sobre os pontos de acesso, transição e inspeção que tornam essa rede operável. No próximo capítulo, essa lógica será expandida para a tomada de decisão entre escoamento gravitário e recalque em estações elevatórias.

3.2 Função dos elementos de interface no sistema de esgoto

A rede coletora não é formada apenas por tubulações enterradas. Ela depende de elementos de acesso e transição que permitem:

- inspecionar o interior das tubulações;
- limpar e desobstruir trechos críticos;

- realizar mudanças de direção, declividade ou diâmetro;
- conectar ramais vindos dos imóveis;
- compatibilizar a rede pública com o sistema predial;
- reduzir o custo e a complexidade da manutenção ao longo da vida útil [1, 5].

Definição — Elemento de interface

É qualquer componente que faça a transição física, hidráulica ou operacional entre o sistema predial e a rede pública, ou entre trechos distintos da rede coletora.

Em um sistema bem concebido, os elementos de interface não devem ser vistos como acessórios. Eles são parte integrante da solução hidráulica e operacional.

Atenção — Erro conceitual frequente

É comum tratar poços de visita e caixas de inspeção apenas como peças de acesso. Na prática, eles também têm função hidráulica, construtiva e sanitária. Um elemento mal posicionado pode gerar refluxo, acúmulo de sólidos, entrada de água indevida e dificuldade de manutenção.

3.3 Poços de visita

3.3.1 Definição e finalidade

Definição — Poço de visita

É uma estrutura de acesso à rede coletora, normalmente instalada em pontos estratégicos do sistema, permitindo inspeção, limpeza, ventilação relativa e transição geométrica da tubulação.

Os poços de visita, frequentemente abreviados como PVs, são elementos de maior robustez e mais ampla utilização em redes públicas. Eles cumprem papel central em trechos de maior responsabilidade hidráulica ou em pontos onde a rede sofre alterações de geometria.

3.3.2 Funções principais

Os poços de visita são usados, em geral, para:

- receber contribuições de mais de um trecho;
- permitir mudança de direção da tubulação;
- acomodar alteração de declividade;
- absorver mudança de diâmetro;

- viabilizar acesso para limpeza mecânica;
- oferecer ponto de inspeção visual e operacional;
- servir como referência cadastral para a rede enterrada.

3.3.3 Componentes usuais de um poço de visita

Um PV típico pode conter:

- base de concreto ou peça estrutural equivalente;
- canal de fundo, orientado ao fluxo;
- banquetas laterais com declividade adequada;
- corpo ou câmara de acesso;
- degraus ou meios de acesso, quando previstos;
- tampa de fechamento compatível com a classe de tráfego;
- anel de ajuste e elementos de nivelamento.

A geometria interna do PV deve favorecer a continuidade do escoamento. O canal de fundo precisa conduzir a água sem criar descontinuidades acentuadas, zonas mortas ou acumulação de material sólido.

Observação — Canal de fundo e banquetas

A geometria interna do poço não deve transformar o PV em um ponto de deposição. O fundo canalizado e as banquetas laterais são responsáveis por encaminhar o fluxo principal e reduzir turbulências desnecessárias.

3.3.4 Situações em que o poço de visita é especialmente importante

O uso de PV torna-se particularmente relevante quando há:

- encontro de trechos com contribuições distintas;
- mudanças expressivas de direção;
- mudanças de diâmetro;
- desníveis topográficos que exijam acomodação estrutural;
- necessidade de acesso frequente para limpeza;
- trechos de alta criticidade operacional [3].

3.3.5 Critérios de posicionamento

Em termos de concepção, o PV deve ser posicionado de modo a:

- estar acessível a partir da superfície;
- não conflitar com infraestrutura urbana sensível;
- estar preferencialmente em faixa pública ou local tecnicamente garantido;
- facilitar o acesso de equipamentos de manutenção;
- reduzir a probabilidade de interferências ocultas;
- permitir leitura cadastral clara no projeto e na operação.

Atenção — Mudança de direção sem poço

Mudanças bruscas de direção sem dispositivo de inspeção comprometem a manutenção e podem provocar perda de energia local, deposição de sólidos e dificuldade de desobstrução. Em geral, mudanças significativas de direção devem ser tratadas em poços de visita ou em dispositivos equivalentes, conforme o projeto e a norma aplicável.

3.4 Caixas de inspeção

3.4.1 Definição e uso típico

Definição — Caixa de inspeção

É uma pequena estrutura de acesso à tubulação, geralmente associada a trechos prediais ou a ligações de menor porte, destinada a permitir inspeção, limpeza e conexão entre segmentos de menor extensão.

As caixas de inspeção são normalmente usadas em ambientes mais localizados, sobretudo no interior do lote ou junto à divisa do imóvel. Sua escala é menor do que a de um poço de visita, e sua função é mais ligada à interface predial do que à rede pública principal.

3.4.2 Diferenças entre poço de visita e caixa de inspeção

Observação — Termos variam conforme a concessionária

A nomenclatura pode variar entre municípios e prestadores. Em alguns contextos, certas estruturas de inspeção predial são chamadas de caixas de passagem, caixas de inspeção ou caixas de gordura, conforme a função. Neste livro, o termo caixa de inspeção é reservado para o acesso à tubulação de esgoto sanitário sem tratamento preliminar adicional.

Tabela 3.1: Diferenças funcionais entre poço de visita e caixa de inspeção

Elemento	Função principal	Uso mais comum
Poço de visita	Acesso operacional, inspeção, limpeza e acomodação de mudanças geométricas da rede.	Rede pública coletora, coletores-tronco e pontos de interseção.
Caixa de inspeção	Inspeção e limpeza de trechos curtos, com escala reduzida e aplicação predial ou de ligação.	Lotes, interfaces prediais e trechos de menor porte.

3.4.3 Critérios de uso

As caixas de inspeção são especialmente úteis quando:

- o trecho é curto e de pequena profundidade;
- a inspeção precisa ser simples e econômica;
- o acesso ao trecho não exige a robustez de um PV;
- a interface ocorre dentro do lote ou próxima à divisa;
- a solução busca reduzir custo sem sacrificar manutenibilidade.

3.4.4 Cuidados construtivos

Independentemente da geometria e do material, a caixa de inspeção deve:

- ser acessível;
- ser estanque;
- manter continuidade hidráulica;
- evitar infiltração e exfiltração;
- permitir remoção de obstruções simples;
- ser protegida contra cargas incompatíveis com sua capacidade estrutural.

3.5 Ramal predial e ligação predial

3.5.1 Distinção entre os termos

A terminologia pode variar entre normas locais e concessionárias. Para fins didáticos neste livro:

- **ramal predial**: trecho que conduz o esgoto gerado no imóvel até o ponto de conexão com a rede pública ou até a caixa de inspeção de interface;
- **ligação predial**: trecho final de conexão entre a instalação predial e o coletor público, incluindo a transição hidráulica e construtiva.

Definição — Instalação predial de esgoto

É o conjunto de tubulações e dispositivos localizados no interior do imóvel, responsável por coletar e conduzir os despejos das unidades sanitárias até o ponto de ligação com o sistema público.

3.5.2 Percurso hidráulico típico

De modo simplificado, o fluxo segue esta sequência:

- aparelhos sanitários e pontos de descarga;
- tubulações internas;
- caixa de inspeção ou caixa de passagem, quando prevista;
- ramal predial;
- ligação predial;
- rede coletora pública.

A figura a seguir sintetiza essa interface.

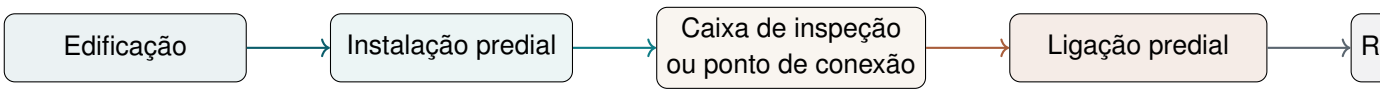

Figura 3.1: Interface típica entre o imóvel e a rede pública de esgoto.

3.5.3 Princípios de projeto para o ramal

O ramal predial deve observar alguns princípios essenciais:

- declividade suficiente para evitar deposição de sólidos;
- percursos tão curtos e diretos quanto possível;
- compatibilidade com a profundidade da rede pública;
- acessibilidade para inspeção e desobstrução;
- separação rigorosa das águas pluviais;
- estanqueidade para evitar infiltrações e retorno de odores.

Atenção — Não misturar esgoto sanitário com drenagem pluvial

A conexão indevida entre esgoto sanitário e águas pluviais é uma das causas mais graves de sobrecarga de rede. Além de aumentar a vazão transportada, essa prática pode provocar extravasamentos, reduzir a eficiência hidráulica e comprometer a operação do sistema.

3.5.4 Conexão com a rede pública

A conexão deve ser executada de modo tecnicamente controlado, respeitando:

- alinhamento e cotas de fundo;
- compatibilidade de diâmetros;
- estanqueidade da união;
- proteção mecânica durante o assentamento;
- acesso para eventual manutenção;
- autorização e padrão da concessionária, quando aplicável.

Observação — Integração com o cadastro da rede

Uma ligação predial bem executada precisa ser registrada no cadastro técnico da rede. Sem isso, a operação futura fica prejudicada, pois a equipe de manutenção perde a referência exata da conexão, da cota e do percurso da ligação.

3.6 Redes coletoras secundárias e organização da quadra

As redes coletoras secundárias fazem a coleta inicial dos esgotos de uma área urbana. Elas geralmente recebem contribuições de vários lotes e as encaminham para coletores de maior porte.

3.6.1 Função urbana

Numa quadra típica, as redes secundárias devem:

- captar os esgotos gerados nos lotes lindeiros;
- conduzir o fluxo até um ponto de concentração;
- organizar a coleta em uma malha coerente;
- reduzir a necessidade de atravessar quadras desnecessariamente;
- facilitar a expansão do sistema em etapas futuras.

3.6.2 Interface entre lote, passeio e via pública

A concepção deve considerar três faixas típicas:

- **lote**: domínio da instalação predial e da caixa de inspeção;
- **passeio**: faixa de transição, onde a ligação pode atravessar ou se aproximar da rede pública;
- **via pública**: local de passagem da rede coletora e dos pontos de inspeção associados.

A coordenação entre essas faixas reduz conflitos com outros serviços subterrâneos e facilita a implantação da rede.

Observação — Projeto em tecido urbano consolidado

Em áreas já urbanizadas, o projetista frequentemente encontra limitações de espaço, interferências enterradas e restrições de escavação. Nesses casos, a organização da ligação predial e da rede secundária passa a ser tão importante quanto a verificação hidráulica.

3.7 Critérios de inspeção, manutenção e durabilidade

3.7.1 Acesso para operação

Um dos objetivos centrais do projeto é garantir que a rede possa ser mantida. Para isso, o posicionamento de PVs e caixas de inspeção deve proporcionar:

- acesso físico para equipamentos de limpeza;
- identificação visual das conexões;
- possibilidade de inspeção em pontos críticos;
- manejo seguro de eventuais obstruções;
- substituição ou reparo de componentes danificados.

3.7.2 Estanqueidade e controle de entradas indevidas

PVs, caixas e ligações devem limitar:

- infiltração de água subterrânea;
- exfiltração de esgoto para o solo;
- entrada de água pluvial;
- conexão irregular entre sistemas distintos.

Atenção — Falha de estanqueidade

Mesmo uma pequena falha em uma conexão predial pode se transformar em grande problema operacional quando repetida em centenas de imóveis. Por isso, o cuidado com a interface predial tem efeito sistêmico.

3.8 Exemplo resolvido

Exemplo — Avaliação de uma ligação predial por gravidade

Considere um imóvel cuja saída da instalação predial está a 0,82 m abaixo do nível do terreno no ponto de saída do lote. A caixa de inspeção será instalada junto à divisa frontal do terreno. O coletor público, localizado no alinhamento da via, está a 1,08 m abaixo do nível do terreno no mesmo ponto. A distância horizontal entre a saída do lote e a conexão com a rede pública é de 16 m.

Deseja-se verificar se a ligação pode ser feita por gravidade, admitindo uma declividade mínima de projeto de 1 % para o ramal predial.

1. Diferença de cota disponível

A profundidade disponível passa de 0,82 m para 1,08 m, logo a diferença vertical é:

$$\Delta h = 1{,}08 - 0{,}82 = 0{,}26\ \text{m}$$

2. Declividade disponível

A declividade média do trecho é:

$$i = \frac{\Delta h}{L} = \frac{0{,}26}{16}$$

$$i = 0{,}01625$$

Em termos percentuais:

$$i = 1{,}625\ \%$$

3. Verificação

Como a declividade disponível é de 1,625 %, superior à declividade mínima admitida de 1 %, a ligação predial pode, em princípio, ser executada por gravidade.

4. Interpretação técnica

A solução é viável, mas ainda depende de verificar:

- a compatibilidade do diâmetro do ramal;
- a posição real da caixa de inspeção;
- a presença de interferências subterrâneas;

- a cota efetiva de entrada no coletor público;
- a padronização exigida pela concessionária.

5. Conclusão
Do ponto de vista geométrico, a conexão é viável por gravidade e atende à declividade mínima indicada.

3.9 Resumo do capítulo

Resumo — Ideias centrais

- Poços de visita e caixas de inspeção não são acessórios: eles integram a lógica hidráulica e operacional da rede.
- PVs são usados preferencialmente em pontos de maior responsabilidade, como mudanças de direção, declividade ou diâmetro, e em interseções da rede.
- Caixas de inspeção são soluções de escala menor, muito úteis em interfaces prediais e trechos curtos.
- O ramal predial e a ligação predial fazem a transição entre o imóvel e a rede pública.
- A separação entre esgoto sanitário e águas pluviais é indispensável.
- A estanqueidade e o acesso para manutenção são critérios tão importantes quanto a geometria hidráulica.
- Um projeto bem elaborado deixa o sistema inspecionável, limpável e cadastralmente identificável.

3.10 Exercícios

3.10.1 Exercícios F

1. Explique a diferença entre poço de visita e caixa de inspeção.
2. Por que mudanças de direção da tubulação devem ser preferencialmente acomodadas em um PV?
3. Cite dois riscos associados à conexão indevida entre a drenagem pluvial e a rede de esgoto.

3.10.2 Exercícios M

1. Um ramal predial tem 12 m de comprimento. Adotando declividade mínima de 1 %, qual é a diferença mínima de cota necessária entre a origem e o ponto de conexão?

2. Em uma ligação predial, a saída da instalação do imóvel está a 0,90 m abaixo do terreno. O coletor público está a 1,05 m abaixo do terreno, e a distância horizontal é de 18 m. Determine a declividade disponível e verifique se ela atende a um critério mínimo de 1 %.

3. Um trecho de rede secundária recebe duas ligações prediais. A primeira está associada a um lote com saída a 0,70 m de profundidade e a segunda, a 0,88 m. O coletor público está a 1,02 m. Discuta, em termos geométricos, qual das duas ligações tende a ser mais crítica para execução por gravidade.

3.10.3 Exercícios D

1. Elabore, em texto técnico, a solução de interface para uma quadra com seis lotes em uma mesma testada urbana. Indique onde você posicionaria caixas de inspeção, ligação predial e pelo menos dois pontos de inspeção da rede pública, justificando a escolha.

2. Em uma área consolidada, a rede apresenta obstruções recorrentes em um trecho localizado entre dois cruzamentos. Proponha um diagnóstico e indique quais características de projeto e operação você investigaria primeiro.

3. Compare duas alternativas para uma ligação predial em área urbana densa: conexão direta à rede pública ou conexão via caixa de inspeção junto à divisa. Indique vantagens, limitações e condições de uso de cada alternativa.

3.11 Gabarito comentado

Gabarito comentado — Respostas comentadas

Exercícios F

1. **Resposta esperada:** o poço de visita é maior, mais robusto e destinado à rede pública, com função de inspeção, limpeza e acomodação de mudanças geométricas. A caixa de inspeção é menor, em geral associada ao lote ou a trechos curtos, com função de acesso e manutenção simplificada. A resposta deve mostrar a diferença de escala e de aplicação.

2. **Resposta esperada:** porque o PV oferece acesso adequado para manutenção, permite inspeção do ponto de inflexão e reduz o risco de deposição ou de dificuldade de limpeza em mudanças abruptas. A transição geométrica em um elemento apropriado melhora a confiabilidade operacional.

3. **Resposta esperada:** dois riscos entre os seguintes: sobrecarga hidráulica da rede de esgoto; extravasamento em períodos de chuva; entrada de sólidos e areia; redução da

capacidade de transporte; aumento de infiltração por juntas sobrecarregadas. Qualquer resposta coerente é aceitável.

Exercícios M

1. **Cálculo:**

$$\Delta h = 12 \times 0{,}01 = 0{,}12\,\text{m}$$

Resposta final: a diferença mínima de cota necessária é de 0,12 m.

2. **Cálculo:**

A diferença vertical disponível é:

$$\Delta h = 1{,}05 - 0{,}90 = 0{,}15\,\text{m}$$

A declividade disponível é:

$$i = \frac{0{,}15}{18} = 0{,}00833$$

Em percentagem:

$$i = 0{,}833\,\%$$

Resposta final: a declividade disponível é de aproximadamente 0,83 %, portanto inferior ao mínimo de 1 %. A ligação por gravidade, nesse arranjo, não atende ao critério mínimo adotado.

3. **Resposta esperada:** a ligação do primeiro lote, com profundidade de 0,70 m, tende a ser menos favorável do que a do segundo, pois oferece menor margem vertical em relação ao coletor público de 1,02 m. Logo, o primeiro caso é mais crítico para execução por gravidade, sobretudo se a distância horizontal for pequena. A resposta deve mostrar que a compatibilidade entre profundidade de saída e cota do coletor é o fator decisivo.

Exercícios D

1. **Resposta esperada:** a solução deve indicar que cada lote deve possuir sua interface predial com caixa de inspeção ou ponto de conexão, enquanto a rede pública deve ter pontos de inspeção em posições estratégicas, preferencialmente antes e depois de mudanças de direção ou em pontos de concentração de contribuições. O texto

deve justificar acesso, manutenção, estanqueidade e compatibilidade geométrica. Não existe uma única solução numérica, mas a resposta deve ser tecnicamente coerente e organizada.

2. **Resposta esperada:** o diagnóstico deve considerar acúmulo de sólidos, declividade insuficiente, conexões indevidas, falha de estanqueidade, ausência de pontos adequados de inspeção, geometria desfavorável e histórico de manutenção. As primeiras ações investigativas incluem inspeção cadastral, verificação de cota e declividade, checagem de PVs e análise de entradas indevidas. A resposta deve propor correção de projeto e de operação.

3. **Resposta esperada:** a conexão direta à rede pública pode ser mais curta e simples, mas costuma ser menos flexível para inspeção e pode dificultar a manutenção. A conexão via caixa de inspeção junto à divisa tende a melhorar o acesso, a gestão da ligação e a desobstrução, embora acrescente um elemento construtivo. Em área densa, a alternativa com caixa de inspeção costuma ser mais robusta operacionalmente, desde que compatível com o padrão local e com a disponibilidade de espaço.

3.12 Conexão com o próximo capítulo

Observação — Ponte para o Capítulo 4

Os elementos de interface tratados neste capítulo resolvem a transição entre o imóvel e a rede pública em regime gravitário. No próximo capítulo, quando a topografia ou a profundidade de assentamento impedirem a continuidade por gravidade, será necessário recorrer a outro arranjo: as estações elevatórias de esgoto bruto, nas quais a energia mecânica substitui a energia potencial do escoamento.

Parte II

Soluções especiais de coleta e disposição

Capítulo 4

Sistemas condominiais de esgoto, tanques sépticos e disposição de efluentes

4.1 Objetivos de aprendizagem

Ao final deste capítulo, o leitor deverá ser capaz de:

- distinguir sistema convencional, sistema condominial e solução descentralizada;
- compreender os princípios de funcionamento e as vantagens do sistema condominial;
- identificar quando um tanque séptico é tecnicamente adequado e quando ele não deve ser usado como solução final;
- reconhecer as exigências gerais das ABNT NBR 7229 e NBR 13969 para projeto, construção e operação [6, 7];
- selecionar, em nível preliminar, a unidade complementar ou o dispositivo de disposição final mais coerente com o contexto local;
- dimensionar, de forma didática, o volume de um tanque séptico e a área de disposição do efluente;
- relacionar o desempenho da solução descentralizada com a operação, a manutenção e o controle sanitário do sistema [5, 4, 2].

Observação — Posição deste capítulo na lógica do livro

Os capítulos anteriores trataram da geração de vazões, da rede coletora e dos elementos de interface predial. Aqui, o foco se desloca para soluções em que a coleta e o tratamento ocorrem de modo mais localizado, com menor dependência de grandes redes públicas. Isso é particularmente relevante em áreas de baixa densidade, ocupações dispersas, periferias

urbanas e situações em que a implantação do sistema convencional é economicamente ou topograficamente inadequada.

4.2 Panorama das soluções de esgotamento em pequena escala

A escolha de uma solução de esgotamento sanitário não deve ser feita por hábito ou preferência estética. Ela depende de fatores como densidade populacional, topografia, disponibilidade de rede pública, custo de implantação, possibilidade de manutenção e sensibilidade ambiental da área.

Em termos didáticos, pode-se organizar as alternativas em três grandes grupos:

- **sistema convencional**: rede pública com coleta em vias, transporte por gravidade ou recalque e encaminhamento a tratamento centralizado;
- **sistema condominial**: solução coletiva simplificada em que um conjunto de unidades atende um grupo de imóveis ou quadra, reduzindo extensão e profundidade das redes internas;
- **solução descentralizada ou local**: tratamento e disposição próximos à fonte geradora, com tanques sépticos, filtros, valas de infiltração, sumidouros ou outras unidades complementares.

Definição — Solução descentralizada

É aquela em que o esgoto é tratado e disposto em escala local, sem dependência imediata de uma rede pública extensa. Pode atender uma única edificação, um conjunto pequeno de moradias ou uma comunidade de baixa densidade.

Atenção — Hierarquia de decisão

Quando existe rede pública disponível e tecnicamente adequada, a conexão ao sistema coletivo costuma ser a solução preferencial. O sistema condominial e o tanque séptico tornam-se particularmente úteis quando a rede convencional é inviável, muito onerosa ou incompatível com a ocupação do território. A decisão deve ser técnica, institucional e ambiental, nunca improvisada.

4.2.1 Comparação entre arranjos usuais

4.3 Sistemas condominiais de esgoto

4.3.1 Conceito e lógica de funcionamento

O sistema condominial surgiu como alternativa para reduzir custo e complexidade de implantação em áreas urbanas, especialmente onde a rede convencional exigiria traçados longos, profundas escavações ou grande interferência na infraestrutura existente [1, 5].

Tabela 4.1: Comparação entre sistema convencional, sistema condominial e solução descentralizada

Sistema	Característica dominante	Vantagens	Limitações
Convencional	Rede pública extensa, com coletores em vias e transporte a tratamento centralizado.	Alta padronização, operação concentrada, integração com a malha urbana consolidada.	Maior custo de implantação em áreas dispersas, necessidade de maior escavação e maior dependência topográfica.
Condominial	Rede simplificada compartilhada por grupo de imóveis ou por quadra, com traçado mais curto e menor profundidade.	Redução de custo, menor volume de escavação, adaptação a áreas consolidadas e periferias.	Requer acordo de uso, gestão compartilhada e manutenção bem organizada.
Descentralizado	Tratamento e disposição próximos ao ponto de geração, com tanque séptico e unidade complementar.	Adequado para áreas isoladas, baixa densidade e locais sem rede pública.	Exige controle sanitário contínuo, manejo de lodo e avaliação cuidadosa do solo e do lençol freático.

A ideia central é simples: em vez de cada imóvel se conectar diretamente a uma rede pública principal em via, um conjunto de lotes compartilha uma rede mais curta, geralmente localizada em faixa de menor conflito, como corredor lateral, servidão, espaço comum ou alinhamento interno da quadra.

Definição — Sistema condominial

É um arranjo de coleta em que um grupo de imóveis utiliza uma rede compartilhada de pequeno porte, normalmente com traçado mais simples e menor profundidade, conduzindo os esgotos até um ponto de entrega ao sistema público, a um interceptor, a uma elevatória ou a uma unidade de tratamento local.

Observação — A essência do sistema condominial

O ganho do sistema condominial não está apenas em usar tubos menores. O ganho principal vem da reorganização espacial da coleta: menos extensão, menor profundidade, menos interferência viária e maior aderência à ocupação real do terreno.

4.3.2 Princípios de concepção

Um sistema condominial bem concebido deve observar os seguintes princípios:

- **simplicidade geométrica**: traçados curtos, poucas inflexões e pontos de acesso bem distribuídos;

- **integração com a ocupação**: uso de espaços disponíveis sem criar conflitos desnecessários;
- **menor profundidade**: redução de escavação e de custo;
- **menor extensão de rede**: menos material, menos juntas e menos pontos potenciais de falha;
- **acesso à manutenção**: pontos de inspeção suficientes para limpeza e desobstrução;
- **responsabilidade compartilhada**: clareza sobre uso, operação e conservação;
- **compatibilidade sanitária**: separação completa das águas pluviais e das águas servidas.

4.3.3 Vantagens operacionais e econômicas

As principais vantagens do sistema condominial são:

- redução do comprimento total de tubulações;
- diminuição da profundidade média das valas;
- menor volume de escavação e recomposição de pavimento;
- possibilidade de atender áreas consolidadas com menor conflito urbano;
- menor custo de implantação por unidade atendida;
- maior flexibilidade em terrenos e quadras de geometria irregular;
- adequação a fases iniciais de urbanização ou expansão gradual.

4.3.4 Limitações e cuidados

Apesar das vantagens, o sistema condominial não é solução automática. Ele exige cuidados específicos:

- acordo institucional sobre uso e manutenção;
- definição clara de servidão ou faixa de passagem;
- controle de ligações indevidas;
- cuidado com raízes, pavimentação e obstruções;
- inspeção e limpeza mais frequentes em certos contextos;
- projeto compatível com a topografia e com o padrão de ocupação;
- integração com o operador local ou com a comunidade assistida.

Atenção — Erro comum em sistemas condominiais

Uma rede condominial mal gerida pode parecer barata na implantação e cara na operação. Se não houver clareza de responsabilidades, o sistema tende a acumular obstruções, ligações clandestinas, perdas de estanqueidade e conflitos entre usuários.

4.3.5 Quando o sistema condominial é mais indicado

O sistema condominial costuma ser especialmente útil em:

- bairros de baixa ou média densidade;
- áreas periféricas com ocupação consolidada;
- conjuntos habitacionais;
- quadras com geometria interna favorável à passagem de uma rede comum;
- locais onde o traçado convencional exigiria grandes profundidades;
- situações em que a rede pública pode ser simplificada sem prejuízo da segurança sanitária.

4.3.6 Quando ele deve ser evitado ou estudado com cautela

A solução condominial exige maior cautela quando há:

- conflitos intensos de propriedade e acesso;
- ocupação muito irregular e sem servidão viável;
- tráfego pesado em áreas de passagem da rede;
- lençol freático alto e solo com baixa estabilidade;
- necessidade de acesso frequente de máquinas de grande porte;
- ausência de apoio institucional para manutenção.

Observação — Aspecto social e institucional

Em sistemas condominiais, a solução técnica só se sustenta se a dimensão social também for cuidadosamente tratada. É necessário orientar usuários, delimitar responsabilidades e estabelecer regras claras para uso, limpeza e manutenção.

4.3.7 Configuração típica

Em um arranjo condominial típico, os esgotos saem dos imóveis, convergem para uma rede simplificada no interior da quadra e seguem até um ponto de entrega que pode ser:

- um coletor público de maior porte;

- um interceptor;
- uma estação elevatória;
- uma unidade de tratamento local.

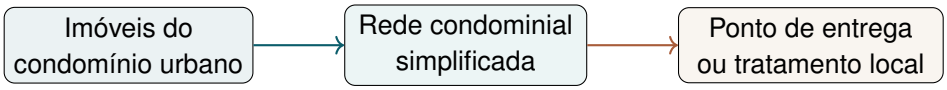

Figura 4.1: Esquema conceitual de um sistema condominial.

4.4 Tanques sépticos

4.4.1 Conceito e função

O tanque séptico, popularmente chamado de fossa séptica, é uma unidade de tratamento primário que recebe esgoto bruto, promove a separação de sólidos sedimentáveis e flutuantes, e inicia a digestão anaeróbia do lodo acumulado [6, 2, 4].

Definição — Tanque séptico

É uma unidade fechada, estanque e de fluxo contínuo ou semicontínuo, destinada à separação de sólidos, retenção de escuma e digestão anaeróbia de parte da matéria orgânica presente no esgoto doméstico.

Observação — Tanque séptico não é tratamento completo

O tanque séptico reduz a carga poluidora, mas não transforma o efluente em água apta para lançamento irrestrito. Em geral, ele deve ser seguido de unidade complementar de tratamento ou de disposição final adequadamente dimensionada.

4.4.2 Processos internos

No interior do tanque séptico ocorrem, em linhas gerais, três processos:

- **sedimentação**: sólidos mais densos se acumulam no fundo, formando lodo;
- **flotação**: materiais leves sobem e compõem a camada de escuma;
- **digestão anaeróbia**: microorganismos degradam parte da matéria orgânica em ambiente sem oxigênio.

Atenção — Gases e ventilação

A degradação anaeróbia produz gases como metano, gás carbônico e sulfeto de hidrogênio. Por isso, o sistema precisa ser estanque, mas não pode ser completamente desprovido de

ventilação apropriada. O projeto deve evitar acumulação perigosa de gases e deve garantir acesso seguro para inspeção e limpeza.

4.4.3 Componentes usuais do tanque séptico

Um tanque séptico usualmente apresenta:

- câmara ou câmaras de sedimentação e digestão;
- entrada e saída cuidadosamente posicionadas;
- dispositivos de retenção de escuma;
- dispositivo de saída com proteção contra arraste de sólidos;
- abertura de inspeção e limpeza;
- tampa de acesso e fechamento estanque.

4.4.4 Desempenho esperado

Do ponto de vista sanitário, o tanque séptico:

- reduz parte da carga orgânica;
- retém uma parcela significativa dos sólidos sedimentáveis;
- produz efluente ainda susceptível a contaminação;
- exige manejo periódico do lodo;
- deve ser visto como etapa inicial de tratamento, e não como solução final por si só.

4.4.5 Condições de uso mais adequadas

Os tanques sépticos são frequentemente adequados para:

- habitações isoladas;
- pequenos núcleos rurais;
- áreas periurbanas sem rede pública;
- empreendimentos de baixa densidade;
- instalações onde a coleta centralizada ainda não existe ou não é viável.

4.4.6 Condições de uso inadequadas ou críticas

O uso de tanque séptico é problemático quando há:

- lençol freático muito raso;
- solo com permeabilidade incompatível com a disposição prevista;
- falta de área disponível para complementação ou infiltração;
- impossibilidade de retirada periódica de lodo;
- ocupação muito densa sem controle de uso;
- risco de contaminação de poços, nascentes ou corpos d'água sensíveis.

Observação — Importância da manutenção

Um tanque séptico mal operado perde rapidamente sua eficiência. A remoção periódica de lodo, a verificação de escuma, a inspeção das entradas e saídas e a manutenção da unidade complementar são parte essencial do desempenho sanitário.

4.5 Disposição e tratamento complementar dos efluentes

4.5.1 Por que é necessário complementar o tanque séptico

Segundo as diretrizes da ABNT NBR 13969, o efluente do tanque séptico deve ser encaminhado a unidade complementar de tratamento ou a sistema de disposição final compatível com o solo, o nível freático e a sensibilidade ambiental da área [7].

Isso significa que o tanque séptico, isoladamente, não resolve a destinação sanitária. Ele apenas inicia o tratamento.

4.5.2 Opções mais usuais

As alternativas mais comuns incluem:

- **sumidouro**: poço ou cava destinada à infiltração do efluente no solo;
- **vala de infiltração**: trincheira rasa e alongada para dispersão controlada no terreno;
- **filtro anaeróbio**: unidade complementar que melhora a remoção de matéria orgânica;
- **leito ou sistema de infiltração distribuída**: conjunto de elementos lineares de infiltração;
- **outras unidades complementares**: conforme o tipo de solo, a disponibilidade de área e a exigência ambiental local.

Definição — Disposição final no solo

É a transferência controlada do efluente tratado ou parcialmente tratado para o solo, de modo que o terreno atue como meio de infiltração, retenção, depuração complementar e proteção sanitária, sempre dentro dos limites permitidos pelo projeto.

4.5.3 Critérios para escolha da disposição

A seleção da unidade complementar deve considerar:

- textura e estrutura do solo;
- capacidade de infiltração;
- profundidade do lençol freático;
- declividade do terreno;
- risco de saturação;
- distância a poços, corpos d'água e áreas sensíveis;
- disponibilidade de área;
- facilidade de inspeção e manutenção;
- exigências sanitárias e ambientais locais.

Atenção — Solo e lençol freático

Um bom tanque séptico não compensa um mau sistema de disposição. Se o solo não infiltra adequadamente ou se o lençol freático está muito próximo da superfície, o problema sanitário permanece ou até se agrava.

4.5.4 Sumidouro

O sumidouro é uma solução simples, geralmente utilizada em situações de baixa carga e solo com capacidade de infiltração compatível. Embora seja atraente pela simplicidade, ele deve ser selecionado com prudência.

- Vantagem: ocupa pouca área.
- Limitação: pode saturar rapidamente em solos inadequados.
- Cuidado: exige solo e nível de água subterrânea favoráveis.

4.5.5 Valas de infiltração

As valas de infiltração distribuem o efluente ao longo de uma extensão maior, reduzindo a carga por unidade de área.

- Vantagem: melhor distribuição do efluente.
- Limitação: requer área linear maior.
- Cuidado: é sensível à colmatação se o efluente não estiver suficientemente estabilizado.

4.5.6 Filtro anaeróbio

O filtro anaeróbio é uma unidade complementar que recebe o efluente do tanque séptico e promove tratamento adicional por meio de meio suporte e atividade biológica aderida.

- Vantagem: melhora o desempenho em relação ao tanque isolado.
- Limitação: requer projeto e operação mais cuidadosos.
- Cuidado: não dispensa o manejo de lodo e a manutenção de acessos.

4.5.7 Critério geral de distribuição de carga

Em forma simplificada, a área de disposição no solo pode ser estimada por:

$$A = \frac{Q_e}{I_{adm}}$$

em que:

- A é a área necessária de infiltração ou disposição, em m^2;
- Q_e é a vazão diária de efluente, em L/d;
- I_{adm} é a taxa admissível de aplicação ao solo, em L/(m^2 d).

Esse critério é didático e auxilia a entender a lógica do dimensionamento. Na prática, a norma, o ensaio de percolação e as condições locais devem prevalecer [7, 5].

4.6 Metodologia de dimensionamento didático

4.6.1 Etapa 1: definir a população ou o número de usuários

O primeiro passo é estimar quantas pessoas utilizarão a unidade. Em ocupações familiares, utiliza-se o número de moradores. Em pequenos condomínios ou agrupamentos, usa-se a população equivalente estimada.

4.6.2 Etapa 2: estimar a contribuição diária

Adota-se uma contribuição per capita compatível com a realidade da ocupação. Em áreas residenciais, essa contribuição pode ser derivada do consumo de água, conforme tratado no capítulo anterior.

$$Q_d = \frac{N\,q}{1000}$$

em que:

- Q_d é a vazão diária de esgoto em m^3/d, ou seu equivalente em litros por dia;
- N é o número de usuários;
- q é a contribuição per capita em L/d.

4.6.3 Etapa 3: calcular o volume hidráulico de retenção

O volume hidráulico básico pode ser estimado por:

$$V_H = Q_d\,T$$

em que T é o tempo de detenção, em dias.

4.6.4 Etapa 4: acrescentar o volume de armazenamento de sólidos

Além do volume hidráulico, é necessário reservar espaço para o acúmulo de lodo e escuma durante o intervalo entre limpezas. Assim, o volume total pode ser expresso por:

$$V_T = V_H + V_S$$

em que:

- V_T é o volume total do tanque;
- V_H é o volume hidráulico;
- V_S é o volume de armazenamento de sólidos.

Observação — Simplificação didática

Neste capítulo, a formulação é apresentada em forma conceitual para fins de projeto introdutório. A aplicação executiva deve seguir as prescrições e tabelas da ABNT NBR 7229, além das orientações do prestador de serviço e das condições reais de operação [6].

4.6.5 Etapa 5: dimensionar a disposição complementar

Com o efluente estimado, calcula-se a área necessária de infiltração ou escolhe-se a unidade complementar mais adequada ao terreno.

- Se o solo for favorável e houver área disponível, valas ou sumidouro podem ser estudados.
- Se o solo exigir maior controle, filtros anaeróbios e sistemas em série podem ser mais adequados.
- Se a água subterrânea estiver muito próxima, a solução no solo pode ser inviável.

4.6.6 Etapa 6: verificar condições sanitárias e de manutenção

O projeto deve confirmar:

- afastamentos sanitários;
- acesso para remoção de lodo;
- facilidade de inspeção;
- proteção contra retorno superficial;
- segurança estrutural da tampa e da câmara;
- continuidade operacional do conjunto.

4.7 Boas práticas de projeto e operação

4.7.1 Boas práticas

- prever acesso simples e seguro para inspeção;
- separar corretamente as entradas de águas pluviais;
- escolher materiais resistentes ao meio agressivo;
- manter estanqueidade nas juntas e conexões;
- orientar o usuário sobre limpeza e uso correto;
- registrar as cotas, o volume e a localização da unidade;
- prever a destinação final do lodo retirado;
- evitar lançar efluente sem critério diretamente em solo inadequado.

4.7.2 Falhas mais comuns

- tanque sem acesso para limpeza;
- colmatação da unidade de disposição;
- infiltração excessiva de águas externas;
- lançamento de lixo, óleo e sólidos grosseiros;
- dimensionamento sem considerar a ocupação real;
- ausência de plano de retirada de lodo;
- distância inadequada de poços, drenagens e áreas sensíveis.

Atenção — Erro crítico

Muitas falhas em sistemas descentralizados não decorrem de um defeito pontual, mas da combinação entre projeto insuficiente, uso inadequado e manutenção inexistente. Por isso, o desempenho depende tanto da engenharia quanto do comportamento do usuário.

4.8 Exemplo resolvido

Exemplo — Tanque séptico para pequeno agrupamento de moradias

Considere três residências com quatro moradores cada, totalizando $N = 12$ usuários. Adote contribuição per capita de $q =$ 100 L/hab.d. Para fins didáticos, considere tempo de detenção hidráulica de $T = 1$ dia e volume de reserva para lodo e escuma de $V_S =$ 800 L. O efluente final será disposto em valas de infiltração com taxa admissível didática de $I_{adm} =$ 50 L/m².d.

1. Vazão diária de esgoto

$$Q_d = N\,q = 12 \times 100$$

$$Q_d = \text{1200 L/d}$$

2. Volume hidráulico

$$V_H = Q_d\,T = 1200 \times 1$$

$$V_H = \text{1200 L}$$

3. Volume total do tanque

$$V_T = V_H + V_S = 1200 + 800$$

$$V_T = 2000 \text{ L}$$

4. Área de disposição complementar

$$A = \frac{Q_d}{I_{adm}} = \frac{1200}{50}$$

$$A = 24 \text{ m}^2$$

5. Interpretação

O tanque séptico, neste exemplo didático, deve ter volume total de aproximadamente 2000 L. A área de infiltração necessária para o efluente é de 24 m². Se cada vala tiver, por exemplo, 12 m de comprimento e 0.5 m de largura útil, cada uma fornece 6 m²; nesse caso, seriam necessárias quatro valas equivalentes ou uma redistribuição geométrica do sistema.

6. Observação técnica

Esse exemplo não substitui o dimensionamento normativo. Ele apenas mostra a lógica da solução: calcular a vazão, reservar o volume de retenção e verificar a capacidade de disposição final em função do solo.

4.9 Resumo do capítulo

Resumo — Ideias centrais

- O sistema condominial reduz extensão, profundidade e custo em áreas em que a rede convencional é pouco eficiente.
- Seu sucesso depende de boa concepção, responsabilidade compartilhada e manutenção organizada.
- O tanque séptico é uma unidade de tratamento primário, não uma solução final isolada.
- Efluentes sépticos exigem disposição ou tratamento complementar em unidade compatível com o solo, o lençol freático e a área disponível.
- Sumidouros, valas de infiltração e filtros anaeróbios são alternativas, cada uma com vantagens e limitações próprias.
- O dimensionamento didático do tanque séptico pode ser visto como soma de volume hidráulico e volume de reserva para lodo e escuma.
- A operação correta, a retirada periódica de lodo e o controle de ligações indevidas são decisivos para a durabilidade sanitária do sistema.

- As normas ABNT NBR 7229 e NBR 13969 devem sempre orientar a solução executiva [6, 7].

4.10 Exercícios

4.10.1 Exercícios F

1. Explique, com suas palavras, a diferença entre sistema condominial e sistema convencional de esgoto.

2. Por que o tanque séptico não pode ser considerado tratamento final do esgoto?

3. Cite três condições que tornam a disposição do efluente no solo tecnicamente mais arriscada.

4.10.2 Exercícios M

1. Um grupo de 16 usuários gera $q = 110$ L/hab.d. Calcule a vazão diária de esgoto.

2. Para o grupo do item anterior, adote $T = 1$ dia e volume de reserva de $V_S = 1\,000$ L. Determine o volume total do tanque séptico.

3. Se o efluente do item anterior for disposto em valas com taxa admissível de 55 L/m².d, determine a área mínima de disposição.

4.10.3 Exercícios D

1. Em uma quadra com oito moradias, discuta a conveniência de um sistema condominial em relação à solução convencional. Aponte vantagens, limitações e exigências de manutenção.

2. Uma localidade periurbana apresenta lençol freático muito próximo da superfície e solo argiloso. Analise a adequação de tanques sépticos com disposição no solo e indique alternativas mais coerentes.

3. Proponha uma solução completa para uma pequena comunidade de 20 moradores sem rede pública, incluindo: coleta local, tratamento primário, tratamento complementar, manutenção e destinação do lodo.

4.11 Gabarito comentado

Gabarito comentado — Respostas comentadas

Exercícios F

1. **Resposta esperada:** o sistema convencional utiliza rede pública mais extensa, em geral implantada em vias e com transporte centralizado; o condominial simplifica o traçado, reduz profundidade e compartilha a rede entre um grupo de imóveis. A resposta deve destacar que o condominial reorganiza a coleta em escala menor e mais econômica.
2. **Resposta esperada:** porque o tanque séptico remove apenas parte da carga orgânica e sólidos sedimentáveis, deixando no efluente contaminantes e matéria orgânica remanescente. Sem unidade complementar ou disposição final adequada, o risco sanitário e ambiental permanece.
3. **Resposta esperada:** três entre as seguintes: lençol freático alto, solo com baixa permeabilidade, ausência de área suficiente, proximidade de poços ou cursos d'água, risco de saturação, clima ou relevo desfavorável, dificuldade de manutenção.

Exercícios M

1. **Cálculo:**

$$Q_d = 16 \times 110 = 1760 \text{ L/d}$$

Resposta final: a vazão diária de esgoto é de 1760 L/d.

2. **Cálculo:**

$$V_H = 1760 \times 1 = 1760 \text{ L}$$

$$V_T = 1760 + 1000 = 2760 \text{ L}$$

Resposta final: o volume total do tanque séptico é de 2760 L.

3. **Cálculo:**

$$A = \frac{1760}{55} \approx 32.0 \text{ m}^2$$

Resposta final: a área mínima de disposição é de aproximadamente 32 m².

Exercícios D

1. **Resposta esperada:** o sistema condominial tende a ser vantajoso se a quadra permitir rede curta, servidão clara e acesso à manutenção. O candidato deve citar redução de custo, menor escavação, adaptação à malha existente e simplificação de traçado. Também deve apontar os riscos de responsabilidade difusa, obstruções, ligações indevidas e necessidade de governança. A resposta correta é aquela que mostra equilíbrio entre benefício técnico e exigência institucional.

2. **Resposta esperada:** tanques sépticos com disposição no solo são pouco adequados quando o lençol freático é raso e o solo é argiloso, pois a infiltração fica comprometida e o risco de contaminação aumenta. O texto deve sugerir alternativas como tratamento complementar mais controlado, unidades elevatórias para encaminhamento a solução coletiva, filtros anaeróbios, sistemas de disposição com maior controle ou outra tecnologia aprovada pelos órgãos locais. O ponto central é reconhecer que a disposição no solo não deve ser forçada em ambiente hidrogeologicamente desfavorável.

3. **Resposta esperada:** a solução pode incluir coleta condominial ou rede simplificada, tanque séptico coletivo ou modular, unidade complementar como filtro anaeróbio e disposição final compatível com o solo, além de plano de limpeza periódica e destinação adequada do lodo. A resposta deve contemplar operação, manutenção, inspeção e gestão. É aceitável que o aluno proponha arranjo em etapas, desde que a lógica sanitária esteja coerente.

4.12 Conexão com o próximo capítulo

Observação — Ponte para o Capítulo 5

Neste capítulo, foram estudadas soluções em que a coleta pode ser simplificada ou o tratamento pode ocorrer próximo à fonte geradora. No próximo capítulo, será tratada a situação em que a gravidade deixa de ser suficiente para conduzir o esgoto até o destino desejado. Nessa condição, entram em cena as estações elevatórias de esgoto bruto, que introduzem energia mecânica ao sistema e exigem outro nível de concepção, operação e segurança.

Capítulo 5

Estações elevatórias de esgoto bruto

5.1 Objetivos de aprendizagem

Ao final deste capítulo, o leitor deverá ser capaz de:

- identificar quando a solução gravitária deixa de ser suficiente para conduzir o esgoto até o destino desejado;
- compreender a função das estações elevatórias de esgoto bruto no sistema de esgotamento sanitário;
- reconhecer os principais componentes civis, hidráulicos, elétricos e operacionais de uma elevatória;
- calcular, em nível introdutório, a altura manométrica total e a potência hidráulica de bombeamento;
- interpretar critérios básicos de seleção de bombas e de arranjos com redundância;
- relacionar o projeto da elevatória com operação, manutenção, segurança e confiabilidade do sistema [1, 5, 4].

Observação — Relação com os capítulos anteriores

Nos capítulos anteriores, o esgoto foi conduzido por gravidade, a partir de sua geração, passando pela rede coletora e pelos elementos de interface predial. Aqui, o foco muda para a situação em que a gravidade não basta: seja por topografia desfavorável, seja por profundidade excessiva, seja por restrições urbanas. Nesses casos, a energia mecânica fornecida por bombas passa a integrar o sistema.

5.2 Função das estações elevatórias no sistema

5.2.1 Por que elevar o esgoto?

A estação elevatória existe para transferir o esgoto bruto de uma cota mais baixa para uma cota mais alta, permitindo que o fluxo continue até o interceptor, o emissário ou a unidade de tratamento. Ela é necessária quando a solução exclusivamente gravitária deixa de ser tecnicamente razoável, economicamente viável ou operacionalmente segura.

Em termos práticos, a elevatória aparece quando:

- a profundidade do coletor a jusante se tornaria excessiva;
- a topografia local impede o escoamento por gravidade;
- há travessias de vales, canais, rodovias ou corpos d'água;
- o sistema precisa vencer longas distâncias com menor profundidade de assentamento;
- a malha urbana consolidada não permite rebaixamentos adicionais;
- o traçado ótimo em planta não coincide com a declividade disponível.

Definição — Estação elevatória de esgoto bruto

É o conjunto de obras civis, mecânicas, elétricas e de automação destinado a receber esgoto bruto, armazená-lo temporariamente e recalcá-lo por meio de bombas até uma cota superior, mantendo a continuidade do sistema de esgotamento sanitário.

Atenção — Solução de oportunidade, não de preferência

A elevatória não é a primeira opção de projeto. Em geral, ela é adotada quando uma solução gravitária mais simples, mais segura ou mais econômica não é possível. Por isso, seu uso deve ser justificado tecnicamente e acompanhado de análise de ciclo de vida, operação e contingências.

5.2.2 Papel sistêmico

A estação elevatória atua como elo entre dois regimes de condução:

- **montante gravitário**: recebe a contribuição dos coletores ou interceptores que chegam por declividade;
- **jusante pressurizado**: empurra o fluxo por uma linha de recalque até novo ponto de descarga.

Assim, ela não substitui a rede coletora; ela complementa a lógica do sistema quando a topografia ou a implantação urbana impõem a necessidade de transpor cotas.

5.3 Configuração típica de uma elevatória

5.3.1 Elementos principais

Uma estação elevatória de esgoto bruto costuma reunir os seguintes componentes:

- poço úmido ou poço de sucção;
- conjunto motobomba, submersível ou em casa de bombas;
- tubulação de sucção, quando aplicável;
- tubulação de recalque;
- válvulas de retenção e de bloqueio;
- quadro elétrico e sistema de comando;
- sensores de nível, alarmes e automação;
- ventilação, acesso e dispositivos de segurança;
- eventual gerador, reserva de energia ou by-pass de emergência.

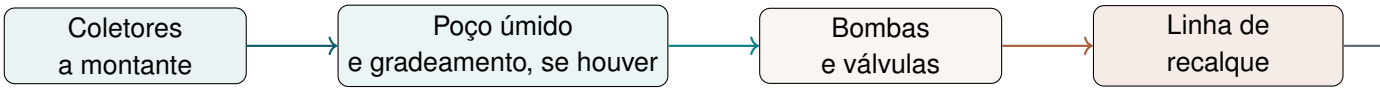

Figura 5.1: Esquema simplificado de uma estação elevatória de esgoto bruto.

5.3.2 Poço úmido

O poço úmido é a câmara onde o esgoto chega antes de ser bombeado. Ele armazena temporariamente o líquido até que o nível acione o comando de partida das bombas.

Seu projeto deve equilibrar três exigências:

- volume suficiente para amortecer variações de chegada;
- volume não excessivo, para evitar tempo de retenção muito alto;
- geometria que reduza deposição de sólidos e facilita limpeza.

Observação — Tempo de retenção e septicidade

Se o esgoto permanecer muito tempo parado no poço úmido, aumentam o risco de degradação anaeróbia, geração de odores, corrosão por sulfeto de hidrogênio e formação de depósitos. Por isso, o volume útil deve ser bem dosado e o tempo de permanência, controlado.

5.3.3 Casa de bombas ou poço seco

Em algumas configurações, as bombas ficam instaladas em um compartimento separado e seco, acessível para inspeção e manutenção. Em outras, especialmente com bombas submersíveis, o conjunto motobomba trabalha imerso e a manutenção é feita por içamento.

- **poço seco**: facilita acesso, mas exige maior obra civil e drenagem interna;
- **poço úmido com bombas submersíveis**: reduz complexidade civil, mas exige bom controle de vedação, guias, içamento e segurança elétrica.

5.3.4 Válvulas e linha de recalque

Na linha de recalque, duas peças são indispensáveis:

- **válvula de retenção**: evita retorno do fluxo quando a bomba para;
- **válvula de bloqueio**: permite isolamento do trecho para manutenção.

A linha de recalque deve suportar as pressões geradas pela bomba, o regime de partidas e paradas, e os efeitos transitórios de operação. Em sistemas mais robustos, devem ser avaliadas também medidas de proteção contra golpe de aríete e dissipação de sobrepressões.

5.3.5 Comando, automação e segurança

Uma elevatória moderna deve contar com:

- comando automático por boias, sensores ou transdutores de nível;
- alternância entre bombas para equalização de desgaste;
- alarme de nível alto;
- indicação de falha elétrica;
- supervisão remota, quando exigida pela operação;
- proteção contra sobrecarga, curto-circuito e falta de fase;
- eventual gerador de emergência, dependendo da criticidade do sistema.

Atenção — Falha de energia

A falta de energia elétrica pode interromper o recalque e provocar extravasamento do poço úmido. Em sistemas críticos, a estação deve prever reserva operacional, redundância de bombas, alarme de falha e, quando necessário, alimentação emergencial.

5.4 Fundamentos hidráulicos do recalque

5.4.1 Altura geométrica e altura manométrica

A energia requerida para elevar o esgoto depende da diferença de cotas entre o ponto de sucção e o ponto de descarga, acrescida das perdas de carga ao longo da tubulação.

A altura geométrica, ou altura estática, pode ser representada por:

$$H_g = z_d - z_s$$

em que:

- H_g é a altura geométrica;
- z_d é a cota do ponto de descarga;
- z_s é a cota do nível líquido de sucção.

A altura manométrica total, que representa a carga que a bomba deve vencer, pode ser escrita como:

$$H_{MT} = H_g + H_f + H_l$$

em que:

- H_{MT} é a altura manométrica total;
- H_f é a perda de carga distribuída;
- H_l é a soma das perdas localizadas.

5.4.2 Perdas de carga

As perdas de carga distribuídas podem ser estimadas por fórmulas clássicas de escoamento em tubulações, como Darcy-Weisbach, enquanto as perdas localizadas decorrem de curvas, conexões, válvulas, entradas e saídas.

Uma forma geral de representação é:

$$H_f = f\,\frac{L}{D}\,\frac{V^2}{2g}$$

$$H_l = \sum K\,\frac{V^2}{2g}$$

em que:

- f é o fator de atrito;
- L é o comprimento da tubulação;

- D é o diâmetro interno;
- V é a velocidade média;
- g é a aceleração da gravidade;
- K é o coeficiente de perda localizada.

Observação — Escolha do método de cálculo

Em projetos didáticos, pode-se trabalhar com valores estimados de perdas ou com a forma clássica de Darcy-Weisbach. Em projeto executivo, o método deve ser compatível com o material da tubulação, as características do esgoto, as recomendações do fabricante e o critério do projetista.

5.4.3 Curva do sistema e curva da bomba

Toda estação elevatória funciona na interseção entre a curva da bomba e a curva do sistema.

- **curva da bomba**: relaciona vazão e altura manométrica fornecidas pelo equipamento;
- **curva do sistema**: expressa a altura requerida em função da vazão, incluindo carga estática e perdas.

O ponto de operação real é o ponto em que as duas curvas se encontram. Esse ponto determina a vazão efetiva de trabalho da estação.

Definição — Ponto de operação

É a condição de equilíbrio entre o que a bomba fornece e o que o sistema exige. O ponto de operação define a vazão e a altura manométrica efetivamente atendidas.

Atenção — Erro de projeto comum

Selecionar a bomba apenas pela vazão nominal, sem avaliar a curva do sistema, é um erro grave. O equipamento pode funcionar fora da faixa ideal, consumir mais energia, cavitar ou apresentar baixo rendimento.

5.4.4 Potência hidráulica e potência elétrica

A potência hidráulica necessária para elevar um fluido é dada por:

$$P_h = \rho g Q H_{MT}$$

em que:

- P_h é a potência hidráulica;
- ρ é a massa específica do fluido;

- Q é a vazão;
- H_{MT} é a altura manométrica total.

A potência elétrica requerida no eixo ou no motor pode ser estimada por:

$$P_e = \frac{P_h}{\eta}$$

em que η é o rendimento global do conjunto.

5.5 Seleção de bombas

5.5.1 Tipos mais usuais

Para esgoto bruto, a bomba deve ser compatível com sólidos, fibras e eventuais partículas em suspensão. Entre as soluções mais usuais, destacam-se:

- **bombas submersíveis não entupíveis**: muito utilizadas em estações compactas, com instalação simplificada e boa adaptação ao esgoto bruto;
- **bombas centrífugas em poço seco**: adequadas a estações de maior porte, com acesso mais fácil à manutenção;
- **bombas com rotor vortex ou passagem livre**: úteis quando se deseja reduzir risco de obstrução;
- **bombas especiais com maceração**: aplicáveis em casos específicos, mas exigem análise cuidadosa, pois podem alterar o regime de sólidos e a operação a jusante.

5.5.2 Critérios de escolha

A seleção deve considerar:

- vazão de projeto;
- altura manométrica total;
- natureza do esgoto bruto;
- passagem de sólidos;
- rendimento do equipamento;
- confiabilidade e disponibilidade de peças;
- facilidade de manutenção;
- número admissível de partidas por hora;

- redundância necessária.

Observação — Redundância

Em muitas estações, adota-se pelo menos uma bomba reserva ou arranjo com duas unidades, para que uma falha não paralise completamente o sistema. A redundância é uma medida de confiabilidade, não um luxo.

5.5.3 Arranjos de operação

Os arranjos mais comuns são:

- **1 + 1**: uma bomba operando e uma reserva;
- **2 + 1**: duas bombas em operação e uma reserva, em estações maiores;
- **múltiplas unidades**: usadas quando a vazão varia muito ao longo do dia ou em grandes sistemas.

5.5.4 Velocidade na linha de recalque

A velocidade na tubulação de recalque deve ser suficiente para evitar deposição, mas não tão alta a ponto de gerar perdas excessivas. Em recalques de esgoto, a seleção do diâmetro deve equilibrar:

- risco de sedimentação em baixa velocidade;
- custo energético em alta velocidade;
- faixa de operação da bomba;
- robustez contra transientes.

5.6 Concepção civil, sanitária e operacional

5.6.1 Volume útil do poço úmido

O poço úmido precisa armazenar o esgoto entre partidas sucessivas. O volume útil depende da vazão afluente, do intervalo entre acionamentos e da estratégia de operação.

Em uma forma didática simplificada, o volume útil entre dois níveis de acionamento pode ser estimado por:

$$V_u = Q_a \, \Delta t$$

em que:

- V_u é o volume útil entre partida e parada;

- Q_a é a vazão afluente considerada;
- Δt é o intervalo desejado entre eventos de acionamento.

Observação — Muitas partidas são indesejáveis

Se o volume útil for pequeno demais, a bomba liga e desliga com muita frequência, o que aumenta desgaste mecânico e elétrico. Se for grande demais, o esgoto permanece retido por tempo excessivo. O dimensionamento deve equilibrar esses extremos.

5.6.2 Ventilação e controle de odores

O esgoto bruto pode liberar gases agressivos e odorantes. Por isso, a estação deve prever ventilação adequada e, quando necessário, controle de odores.

Os principais riscos são:

- corrosão por sulfeto de hidrogênio;
- desconforto odorífero;
- risco ocupacional para manutenção;
- degradação de componentes metálicos e de concreto.

5.6.3 Segurança de acesso

Toda estação elevatória deve ser tratada como ambiente de risco. São fundamentais:

- tampa e acesso adequados;
- sinalização;
- procedimentos de entrada em espaço confinado, quando aplicável;
- bloqueio elétrico para manutenção;
- ventilação e teste de atmosfera interna;
- equipamentos de proteção individual e coletiva.

Atenção — Espaço confinado

Poços úmidos e câmaras de válvulas podem se comportar como espaços confinados. A entrada sem avaliação atmosférica, ventilação e autorização formal pode ser fatal. Segurança do trabalho é parte integrante do projeto e da operação.

5.6.4 By-pass e contingência

Em situações críticas, pode ser necessário prever by-pass ou transferência provisória de fluxo para manutenção da estação. Essa solução deve ser cuidadosamente planejada para evitar lançamento indevido e para manter a segurança sanitária.

5.7 Manutenção e operação

5.7.1 Rotinas essenciais

Uma estação elevatória exige rotina de inspeção e manutenção com periodicidade definida. Entre as práticas mais relevantes, destacam-se:

- verificação de níveis e sensores;
- limpeza do poço úmido;
- inspeção de válvulas e registros;
- teste de partida e alternância das bombas;
- checagem elétrica e de automação;
- inspeção de ruídos, vibração e aquecimento;
- verificação de odores, corrosão e vazamentos;
- registro de ocorrências e falhas.

5.7.2 Principais problemas operacionais

Os problemas mais frequentes em elevatórias incluem:

- obstrução por sólidos, panos e detritos;
- falha de sensor de nível;
- válvula de retenção defeituosa;
- bomba com rendimento abaixo do esperado;
- sobrecarga elétrica;
- perda de estanqueidade;
- extravasamento por falta de energia ou falha de comando;
- corrosão acelerada do concreto e de peças metálicas.

Observação — Operação é parte do projeto

Uma estação elevatória bem projetada, mas mal operada, rapidamente se torna um ponto crítico do sistema. Por isso, o projeto deve ser pensado desde o início com a lógica da manutenção, da supervisão e da resposta a falhas.

5.8 Exemplo resolvido

Exemplo — Dimensionamento preliminar de uma estação elevatória

Considere uma estação elevatória destinada a recalcar esgoto bruto com vazão máxima horária de projeto igual a 24 L/s.
Adote os seguintes dados:

- cota do nível líquido de sucção: $z_s = 98{,}2$ m;
- cota do ponto de descarga: $z_d = 107{,}4$ m;
- perdas distribuídas na linha de recalque: $H_f = 3{,}8$ m;
- perdas localizadas: $H_l = 1{,}2$ m;
- rendimento global do conjunto: $\eta = 0.68$;
- massa específica do esgoto: $\rho = 1\,000\,\mathrm{kg/m^3}$.

1. Altura geométrica

$$H_g = z_d - z_s = 107{,}4 - 98{,}2$$

$$H_g = 9{,}2\,\mathrm{m}$$

2. Altura manométrica total

$$H_{MT} = H_g + H_f + H_l$$

$$H_{MT} = 9{,}2 + 3{,}8 + 1{,}2$$

$$H_{MT} = 14{,}2\,\mathrm{m}$$

3. Potência hidráulica

Convertendo a vazão para $\mathrm{m^3/s}$:

$$Q = 24\,\mathrm{L/s} = 0{,}024\,\mathrm{m^3/s}$$

Então:

$$P_h = \rho g Q H_{MT}$$

$$P_h = 1000 \times 9{,}81 \times 0{,}024 \times 14{,}2$$

$$P_h \approx 3{,}34\,\text{kW}$$

4. Potência elétrica estimada

$$P_e = \frac{P_h}{\eta}$$

$$P_e = \frac{3{,}34}{0{,}68}$$

$$P_e \approx 4{,}91\,\text{kW}$$

5. Seleção preliminar do motor

Como é usual adotar margem de segurança e disponibilidade comercial, a solução preliminar mais coerente seria selecionar motor de potência nominal imediatamente superior, por exemplo 5,5 kW ou 7,5 kW, conforme a curva real da bomba, a reserva de desempenho e o padrão de mercado.

6. Interpretação

O exemplo mostra que a bomba precisa vencer não apenas a diferença de cotas, mas também as perdas na linha de recalque. A seleção final depende da curva da bomba, do diâmetro efetivo da tubulação, do regime de operação e da redundância prevista.

5.8.1 Exemplo complementar: volume útil do poço

Se o projeto limitar o intervalo entre partidas a 5 min e a vazão afluente de referência for 18 L/s, o volume útil entre ligações sucessivas pode ser estimado por:

$$V_u = Q_a\,\Delta t$$

$$V_u = 0{,}018 \times 300$$

$$V_u = 5{,}4\,\text{m}^3$$

Esse valor representa uma ordem de grandeza para o volume útil entre níveis de acionamento, devendo ser compatibilizado com a geometria real do poço, a estratégia de alternância das bombas e o número admissível de partidas por hora.

5.9 Resumo do capítulo

Resumo — Ideias centrais

- A estação elevatória é usada quando o escoamento gravitário deixa de ser viável ou racional.
- Seu conjunto básico inclui poço úmido, bombas, válvulas, linha de recalque, comando e segurança.
- A altura manométrica total combina altura geométrica, perdas distribuídas e perdas localizadas.
- O ponto de operação resulta da interação entre a curva da bomba e a curva do sistema.
- Bombas para esgoto bruto devem ser compatíveis com sólidos e com o regime de operação sanitária.
- Redundância, automação, ventilação e segurança ocupacional são partes essenciais do projeto.
- O poço úmido não deve reter esgoto por tempo excessivo, sob pena de septicidade, odores e corrosão.
- A manutenção e a confiabilidade operacional são tão importantes quanto o dimensionamento hidráulico.

5.10 Exercícios

5.10.1 Exercícios F

1. Explique por que a elevatória não deve ser vista como a solução preferencial de um sistema de esgotamento sanitário.
2. Qual a função da válvula de retenção na linha de recalque?
3. Por que o tempo de retenção do esgoto no poço úmido deve ser limitado?

5.10.2 Exercícios M

1. Uma elevatória apresenta altura geométrica de 11 m, perdas distribuídas de 4 m e perdas localizadas de 1,5 m. Determine a altura manométrica total.

2. Para a situação do item anterior, com vazão de 20 L/s e rendimento global de 70%, estime a potência elétrica requerida.
3. Se o projeto limitar o intervalo entre partidas a 4 min e a vazão afluente for de 16 L/s, estime o volume útil entre níveis de acionamento.

5.10.3 Exercícios D

1. Em uma área urbana consolidada, a solução gravitária exigiria uma vala muito profunda em um trecho de 140 m. Discuta os fatores que justificariam a adoção de uma elevatória em vez de aprofundar ainda mais a rede.
2. Proponha um arranjo mínimo confiável para uma elevatória de bairro, indicando os componentes indispensáveis de operação, redundância e segurança.
3. Uma estação elevatória apresenta extravasamentos frequentes em dias de chuva, embora receba esgoto bruto. Analise possíveis causas e proponha medidas de projeto, operação e controle que poderiam mitigar o problema.

5.11 Gabarito comentado

Gabarito comentado — Respostas comentadas

Exercícios F

1. **Resposta esperada:** porque a elevatória introduz complexidade mecânica, elétrica e operacional ao sistema. Embora seja necessária em certas condições, ela adiciona dependência de energia, manutenção, redundância e segurança. A preferência continua sendo a gravidade quando possível.
2. **Resposta esperada:** impedir o retorno do fluxo para a bomba quando ela desliga, evitando refluxo, sobrecarga do equipamento, golpes de pressão e perda de rendimento operacional.
3. **Resposta esperada:** porque retenção excessiva favorece septicidade, odor, corrosão por sulfeto de hidrogênio, deposição de sólidos e degradação da qualidade operacional do sistema.

Exercícios M

1. **Cálculo:**

$$H_{MT} = 11 + 4 + 1{,}5 = 16{,}5\,\text{m}$$

Resposta final: a altura manométrica total é de 16,5 m.

2. **Cálculo:**

   Convertendo a vazão:

$$Q = 20\,\mathrm{L/s} = 0{,}020\,\mathrm{m^3/s}$$

   Potência hidráulica:

$$P_h = 1000 \times 9{,}81 \times 0{,}020 \times 16{,}5$$

$$P_h \approx 3{,}24\,\mathrm{kW}$$

   Potência elétrica:

$$P_e = \frac{3{,}24}{0{,}70} \approx 4{,}63\,\mathrm{kW}$$

   Resposta final: a potência elétrica requerida é de aproximadamente 4,63 kW, devendo-se adotar potência comercial superior com margem de segurança.

3. **Cálculo:**

$$V_u = 0{,}016 \times 240$$

$$V_u = 3{,}84\,\mathrm{m^3}$$

   Resposta final: o volume útil entre níveis de acionamento é de 3,84 $\mathrm{m^3}$.

Exercícios D

1. **Resposta esperada:** a adoção de elevatória é justificável quando a profundidade do coletor se torna excessiva, quando o custo de escavação cresce de forma desproporcional, quando há interferências urbanas ou quando o traçado gravitário implicaria grande risco construtivo e operacional. A resposta deve mencionar comparação entre solução gravitária profunda e recalque, incluindo custo de implantação, manutenção, segurança e confiabilidade.

2. **Resposta esperada:** um arranjo mínimo confiável deve incluir poço úmido, pelo menos duas bombas ou uma bomba de reserva, válvula de retenção, válvula de bloqueio,

comando automático por nível, alarme de nível alto, quadro elétrico protegido, ventilação e acesso seguro. Em sistemas mais críticos, deve-se prever energia de emergência e telemetria.

3. **Resposta esperada:** as causas prováveis incluem entrada indevida de águas pluviais, sensores mal calibrados, volume de espera insuficiente, linha de recalque subdimensionada, válvula defeituosa e falha de energia. As medidas podem envolver inspeção e correção de ligações clandestinas, revisão do volume do poço úmido, adequação da bomba e da linha de recalque, melhoria do comando, previsão de reserva operacional e reforço da drenagem separativa. A resposta correta é a que conecta hidráulica, operação e controle de contribuições indevidas.

5.12 Conexão com o próximo capítulo

Observação — Ponte para o Capítulo 6

A estação elevatória permite vencer desníveis e manter a continuidade do sistema quando a gravidade não basta. No próximo capítulo, essa energia introduzida mecanicamente será aplicada para conduzir o esgoto por longas distâncias, em superfícies terrestres ou sob corpos d'água, por meio de emissários. Ali, a atenção se desloca para o transporte em regime pressurizado, a proteção ambiental e as condições de lançamento.

Capítulo 6

Emissários terrestres e subaquáticos

6.1 Objetivos de aprendizagem

Ao final deste capítulo, o leitor deverá ser capaz de:

- distinguir emissário, coletor-tronco e interceptor em um sistema de esgotamento sanitário;
- compreender a função dos emissários no afastamento final de esgotos ou efluentes tratados;
- reconhecer as diferenças entre emissários terrestres e subaquáticos;
- dimensionar, em nível preliminar, um trecho pressurizado com base em vazão, velocidade e perdas de carga;
- interpretar critérios de materiais, pressão admissível, ancoragem, proteção e estanqueidade;
- relacionar o projeto do emissário com a proteção ambiental e com o licenciamento da obra [1, 4, 5].

Observação — Relação com o capítulo anterior

No capítulo anterior, a estação elevatória foi apresentada como o elemento que fornece energia ao sistema quando a gravidade deixa de ser suficiente. Aqui, essa energia é aplicada ao afastamento de longas distâncias por meio de emissários, que conduzem o esgoto ou o efluente em regime pressurizado até o ponto de descarga ou lançamento.

6.2 Conceito e função dos emissários

6.2.1 Definição

Definição — Emissário

É uma tubulação destinada a conduzir esgoto bruto, efluente tratado ou fluxo equivalente até um ponto de descarga, lançamento ou transferência, em geral sem receber contribuições intermediárias ao longo do percurso.

A essência do emissário é o afastamento. Diferentemente de um coletor, ele não organiza a coleta em rede ramificada. Diferentemente de um interceptor, ele normalmente não recebe ligações sucessivas ao longo do traçado. Sua função é transportar o fluxo já reunido até o destino técnico definido pelo sistema [1].

Definição — Interceptor

É uma tubulação de maior porte que intercepta contribuições de vários coletores e as conduz para tratamento, recalque ou afastamento final.

Observação — Diferença funcional

O interceptor recolhe vazões ao longo do caminho. O emissário, em regra, não. Isso é importante porque o emissário é concebido para condução principal e não para a coleta distribuída típica das redes urbanas.

6.2.2 Papel no sistema de saneamento

Os emissários aparecem quando o sistema já cumpriu uma etapa de reunião de vazões e precisa agora vencer distância, relevo, obstáculos urbanos ou exigências ambientais específicas. Eles podem conduzir:

- esgoto bruto, em casos especiais e com forte controle;
- efluente tratado proveniente de estação de tratamento;
- efluente encaminhado a corpo receptor em condição controlada;
- fluxo de transferência entre unidades do próprio sistema.

Em termos de concepção, o emissário costuma ser a última etapa hidráulica antes do lançamento, transferência ou destino final. Por isso, seu projeto deve ser muito cuidadoso em relação a pressão, material, confiabilidade e riscos ambientais [5, 4].

6.3 Tipos de emissário

6.3.1 Emissário terrestre

O emissário terrestre é assentado em solo, em geral enterrado, e transporta o fluxo por via pressurizada ou com regime hidráulico controlado até o ponto de destino. Pode atravessar:

- áreas urbanas;
- faixas de domínio;
- áreas rurais;
- regiões periurbanas;
- travessias terrestres extensas antes do lançamento final.

Seu traçado costuma ser escolhido para reduzir interferências e manter a segurança estrutural e operacional. Quando enterrado, requer análise de cobertura, proteção mecânica e compatibilidade com cargas externas.

6.3.2 Emissário subaquático

O emissário subaquático é instalado em corpo hídrico, normalmente em trecho final de lançamento. Sua função é conduzir o efluente para um ponto submerso adequado, favorecendo diluição e dispersão no receptor.

- Pode ser instalado em rios, lagos, reservatórios, estuários ou mar.
- Em geral, possui trecho difusor ou terminal de lançamento.
- Exige estudo rigoroso de correntes, profundidade, batimetria e sensibilidade ambiental.

Atenção — Lançamento subaquático não é solução simplificada

A instalação subaquática não dispensa estudo ambiental. Ao contrário, ela pede análise mais sofisticada do meio receptor, da dispersão inicial e da eventual formação de zona de mistura. A concepção do difusor e o posicionamento do emissário são decisivos para a eficiência do lançamento.

6.3.3 Comparação entre emissário terrestre e subaquático

6.4 Fundamentos hidráulicos do transporte em emissários

6.4.1 Escoamento pressurizado

Os emissários normalmente operam em regime pressurizado. A vazão é dada por:

Tabela 6.1: Comparação entre emissário terrestre e emissário subaquático

Característica	Emissário terrestre	Emissário subaquático	Observação
Meio de instalação	Solo, vala, travessia terrestre ou faixa de domínio	Corpo hídrico, leito submerso ou região costeira	O meio influencia diretamente as cargas e as proteções necessárias
Destino típico	Transferência entre unidades ou chegada a ponto de lançamento	Lançamento final em corpo receptor	O subaquático exige maior atenção ao meio ambiental
Proteções especiais	Cobertura, encamisamento, travessias e ancoragem local	Lastreamento, ancoragem, difusores e proteção contra flutuabilidade	A flutuabilidade é crítica em dutos submersos
Manutenção	Mais acessível em trechos terrestres	Mais complexa, com necessidade de mergulho ou inspeção especializada	O custo de operação tende a ser maior no subaquático

$$Q = AV$$

em que:

- Q é a vazão;
- A é a área interna da tubulação;
- V é a velocidade média.

A velocidade é um parâmetro central do projeto. Velocidades muito baixas favorecem deposição de sólidos. Velocidades muito altas aumentam perdas de carga, consumo de energia e, em certos materiais, desgaste.

Observação — Faixa de velocidade de referência

Em muitos projetos de saneamento, busca-se trabalhar com velocidades aproximadamente intermediárias, suficientes para minimizar sedimentação e sem impor perdas excessivas. A faixa exata depende do material, da qualidade do efluente e das diretrizes do prestador.

6.4.2 Perdas de carga

As perdas de carga em emissários são fundamentais no cálculo da altura que a bomba ou o sistema deve vencer. De forma geral:

$$H_{MT} = H_g + H_f + H_l$$

em que:

- H_g é a altura geométrica;
- H_f é a perda de carga distribuída;
- H_l é a soma das perdas localizadas.

Para o trecho principal, pode-se empregar a fórmula de Darcy-Weisbach:

$$H_f = f\,\frac{L}{D}\,\frac{V^2}{2g}$$

e, para elementos singulares:

$$H_l = \sum K\,\frac{V^2}{2g}$$

em que:

- f é o fator de atrito;
- L é o comprimento do trecho;
- D é o diâmetro interno;
- V é a velocidade;
- g é a aceleração da gravidade;
- K são coeficientes de perdas localizadas.

Atenção — Projeto por curva completa

Em emissários longos, o projetista não deve olhar apenas para a vazão. A combinação entre comprimento, material, diâmetro, cotas e conexões define a perda total. Além disso, deve-se prever margem para condições transitórias, como partidas e paradas, que podem elevar a pressão momentânea.

6.4.3 Pressão admissível e classe do tubo

Como o emissário pode operar sob pressão, o tubo deve resistir:

- à pressão estática;
- às perdas e à sobrepressão de operação;
- aos efeitos transitórios;
- às cargas externas do terreno ou da água, quando enterrado ou submerso.

A classe de pressão do material deve ser escolhida com margem de segurança. Em emissários pressurizados, essa decisão deve considerar a maior pressão esperada ao longo da vida útil, e não apenas a pressão média de operação.

6.4.4 Transientes hidráulicos

Em longos recalques e emissários, o desligamento súbito de bombas ou o fechamento de válvulas pode gerar sobrepressões transitórias, popularmente associadas ao golpe de aríete. Por isso, devem ser analisados:

- velocidade de propagação da onda de pressão;
- tempo de fechamento de válvulas;
- presença de ventosas ou válvulas de alívio;
- possibilidade de retorno do fluxo;
- seleção de bomba compatível com regime transitório.

Observação — Importância do transitório

Uma linha que opera bem em regime permanente pode falhar no instante de parada. Em emissários longos, o regime transitório não é detalhe: ele faz parte do núcleo do dimensionamento.

6.5 Materiais usuais em emissários

A escolha do material depende do tipo de emissário, da pressão, do solo, da possibilidade de submersão e do custo total de implantação e manutenção.

Tabela 6.2: Materiais usuais em emissários e suas características

Material	Vantagens	Limitações	Aplicação típica
PEAD	Flexibilidade, soldagem por termofusão, boa resistência química e boa adaptação a travessias	Exige controle rigoroso de execução e avaliação da pressão classe	Emissários terrestres e subaquáticos, sobretudo em traçados longos e instalações especiais
PRFV	Leveza, boa resistência química e bom desempenho hidráulico	Projeto e especificação mais dependentes do fabricante	Emissários de grande porte e soluções especiais
Aço	Elevada resistência mecânica e boa resposta em grandes pressões	Necessita proteção anticorrosiva e controle rigoroso de juntas	Travessias, trechos especiais e obras com exigência estrutural elevada
Ferro dúctil	Boa resistência estrutural e disponibilidade comercial	Requer proteção externa e interna adequada em ambientes agressivos	Trechos pressurizados com cargas externas significativas
Concreto protendido	Adequado a grandes diâmetros e esforços relevantes	Peso elevado e cuidados com estanqueidade e agressividade química	Emissários de grande porte e algumas travessias terrestres

Observação — Material e meio receptor

Em emissários subaquáticos, a resistência à corrosão, a segurança de juntas e o controle da flutuabilidade tornam-se ainda mais importantes. Em muitas aplicações, PEAD e aço com proteção adequada apresentam bom desempenho, desde que o projeto de lastreamento e ancoragem seja coerente com o ambiente.

6.6 Critérios de projeto

6.6.1 Traçado e implantação

O traçado do emissário deve buscar:

- menor extensão possível compatível com o relevo;
- menor interferência com outros serviços e propriedades;
- segurança estrutural;
- facilidade de inspeção, quando terrestre;
- menor impacto ambiental, quando subaquático;
- compatibilidade com a obra civil e com a operação do sistema.

6.6.2 Diâmetro e velocidade

Um bom emissário deve evitar tanto a sedimentação quanto o excesso de perdas. Para isso, a combinação entre diâmetro e velocidade deve ser equilibrada.

- Diâmetro muito pequeno: velocidade alta, maior perda de carga, maior pressão e maior sensibilidade a transientes.
- Diâmetro muito grande: velocidade baixa, risco de deposição e operação ineficiente.

Atenção — Critério essencial

Não basta verificar que a vazão passa. É preciso verificar se a vazão passa com velocidade adequada, pressão admissível, perda de carga aceitável e segurança operacional.

6.6.3 Ancoragem e proteção mecânica

Trechos enterrados ou submersos podem exigir:

- lastreamento contra flutuabilidade;
- blocos de ancoragem em curvas e mudanças de direção;
- envelopamento ou proteção externa;

- travessias protegidas;
- encamisamento em passagens críticas;
- cobertura mínima de solo, quando aplicável.

6.6.4 Ventosas e dispositivos de ar

Em linhas longas, é necessário estudar a presença de ar aprisionado, vácuo e interferência no enchimento ou esvaziamento da tubulação. Dispositivos de admissão e expulsão de ar podem ser importantes para:

- evitar colunas de ar;
- reduzir sobrepressões ou depressões;
- melhorar a partida e a operação;
- proteger a tubulação contra colapso local.

6.6.5 Conexão com a elevatória ou estação de tratamento

O ponto de entrada do emissário deve ser compatível com a saída da elevatória ou da estação anterior. A transição entre unidade de bombeamento e emissário deve incluir:

- válvulas adequadas;
- câmaras de inspeção ou de transição;
- controle de pressão;
- acesso para manutenção;
- possibilidade de isolamento do trecho.

6.7 Emissário subaquático: aspectos específicos

6.7.1 Ponto de lançamento

O ponto de lançamento subaquático deve ser escolhido com base em:

- profundidade disponível;
- correntes e hidrodinâmica local;
- distância a áreas sensíveis;
- proteção de praias, margens, captações e ecossistemas;

- condições de mistura e dispersão;
- restrições de navegação, pesca ou uso recreativo.

Observação — A lógica do lançamento

Em um emissário subaquático, não basta conduzir até a água. É preciso definir onde e como o fluxo se mistura com o meio receptor. O projeto deve buscar um ponto e uma geometria que reduzam o impacto local e favoreçam a dispersão inicial.

6.7.2 Difusores

O difusor é o trecho terminal que distribui o efluente em múltiplas saídas ou em uma seção projetada para aumentar a mistura com o corpo hídrico. Sua função é melhorar a diluição inicial, reduzindo concentração localizada.

Os difusores podem ser úteis quando:

- há exigência de melhor distribuição do efluente;
- a sensibilidade ambiental do receptor é elevada;
- o corpo hídrico tem baixa capacidade de mistura natural em certos trechos;
- a qualidade do efluente e o ponto de lançamento exigem maior controle.

6.7.3 Lastreamento e estabilidade

Emissários subaquáticos precisam evitar flutuação. Por isso, podem ser necessários:

- anéis ou pesos de concreto;
- lastros integrais;
- suportes ou fixações no leito;
- valas de assentamento subaquático;
- sistemas de ancoragem adequados à corrente e ao fundo.

6.7.4 Inspeção e manutenção subaquática

A manutenção de emissários subaquáticos é mais complexa que a de terrestres. Em geral, requer:

- inspeções por mergulho ou ROV, quando disponível;
- monitoramento de vazão e pressão;
- controle de vazamentos e integridade estrutural;

- acompanhamento de movimentação de sedimentos;
- análise periódica da condição do difusor e dos pontos de ancoragem.

Atenção — Custos de manutenção

Se o projeto subaquático não considerar manutenção desde o início, o custo do ciclo de vida pode crescer muito. A solução mais barata na implantação pode não ser a mais racional ao longo dos anos de operação.

6.8 Aspectos ambientais e de licenciamento

6.8.1 Proteção do corpo receptor

Emissários se relacionam diretamente com a qualidade ambiental do meio receptor. O projeto deve considerar:

- capacidade de assimilação do corpo hídrico;
- sensibilidade ecológica local;
- uso múltiplo da água;
- presença de captações;
- proteção de balneabilidade, vida aquática e usos econômicos;
- compatibilidade com as condicionantes de licenciamento.

6.8.2 Zoneamento de influência

O lançamento deve ser analisado em termos de:

- zona de mistura inicial;
- dispersão secundária;
- alcance do pluma;
- interferência em margens, fundo e superfície;
- eventual recirculação por correntes.

6.8.3 Risco ambiental

Os principais riscos associados a emissários são:

- lançamento em local inadequado;
- retorno do efluente por efeito de corrente ou maré;

- degradação de habitats aquáticos;
- vazamentos em trechos enterrados ou submersos;
- perda de estanqueidade e contaminação local;
- ruptura estrutural por esforços não previstos.

Observação — Licenciamento

A concepção de um emissário, sobretudo subaquático, deve dialogar com os estudos ambientais, a autorização de implantação e os parâmetros de operação definidos pelos órgãos competentes. O projeto hidráulico isolado não é suficiente.

6.9 Exemplo resolvido

Exemplo — Pré-dimensionamento de um emissário terrestre pressurizado

Considere um emissário terrestre que deve transportar vazão de projeto igual a 80 L/s, com comprimento de 1 800 m. Adote os seguintes dados:

- desnível geométrico entre a origem e o destino: $H_g = 16$ m;
- perdas localizadas estimadas: $H_l = 2{,}2$ m;
- fator de atrito de Darcy: $f = 0{,}020$;
- tubulação em PEAD com diâmetro interno preliminar de 315 mm.

1. Verificação da velocidade

Convertendo a vazão para $\mathrm{m^3/s}$:

$$Q = 80\,\mathrm{L/s} = 0{,}08\,\mathrm{m^3/s}$$

Área interna do tubo:

$$A = \frac{\pi D^2}{4} = \frac{\pi \times 0{,}315^2}{4}$$

$$A \approx 0{,}077\,9\,\mathrm{m^2}$$

Velocidade média:

$$V = \frac{Q}{A} = \frac{0{,}08}{0{,}0779}$$

$$V \approx 1{,}03\,\mathrm{m/s}$$

A velocidade é adequada para transporte de esgoto ou efluente em linha pressurizada, porque tende a evitar deposição e não é excessivamente alta.

2. Perda de carga distribuída

Pela fórmula de Darcy-Weisbach:

$$H_f = f\,\frac{L}{D}\,\frac{V^2}{2g}$$

Substituindo:

$$H_f = 0{,}020 \times \frac{1800}{0{,}315} \times \frac{1{,}03^2}{2 \times 9{,}81}$$

$$H_f \approx 6{,}18\,\text{m}$$

3. Altura manométrica total

$$H_{MT} = H_g + H_f + H_l$$

$$H_{MT} = 16 + 6{,}18 + 2{,}2$$

$$H_{MT} \approx 24{,}38\,\text{m}$$

4. Pressão equivalente

A pressão equivalente é aproximadamente:

$$p \approx \rho g H_{MT}$$

Para interpretação prática, isso corresponde a cerca de:

$$24{,}38\,\text{m.c.a.} \approx 2{,}44\,\text{bar}$$

5. Interpretação do resultado

O diâmetro de 315 mm fornece velocidade satisfatória e uma altura manométrica total moderada. Ainda assim, a seleção final deve verificar:

- pressão admissível do material;
- sobrepressões transitórias;
- necessidade de ventosas e dispositivos de proteção;
- condições de assentamento e ancoragem;
- compatibilidade com a estação elevatória a montante.

6. Conclusão

Como pré-dimensionamento, a solução é tecnicamente plausível. Na etapa executiva, o projeto deveria ser refinado com análise de transientes, detalhamento de juntas, classe de pressão e condições de instalação.

6.9.1 Exemplo complementar: emissário subaquático

Em uma situação de lançamento subaquático, a análise não se limita à hidráulica interna da tubulação. Além da vazão e da pressão, o projetista precisa estudar:

- profundidade do trecho de lançamento;
- direção dominante das correntes;
- existência de sedimentos móveis;
- proteção contra flutuação;
- distância de áreas sensíveis;
- geometria do difusor;
- possibilidade de inspeção futura.

Esse tipo de avaliação é indispensável para que o emissário cumpra sua função sem transferir o problema para o meio receptor.

6.10 Resumo do capítulo

Resumo — Ideias centrais

- O emissário é uma tubulação de afastamento, geralmente sem contribuições intermediárias.
- Emissários terrestres são implantados em solo; emissários subaquáticos terminam em corpo hídrico.
- O projeto deve considerar velocidade, perda de carga, pressão admissível e transientes hidráulicos.
- A escolha do material depende de resistência mecânica, resistência química, estanqueidade, flutuabilidade e custo de ciclo de vida.
- Trechos subaquáticos exigem lastreamento, ancoragem, difusão e inspeção especializada.
- O projeto de emissários está diretamente ligado à proteção ambiental e ao licenciamento.
- O ponto de lançamento no meio receptor é tão importante quanto a tubulação em si.

- O desempenho operacional depende de dimensionamento, montagem, proteção e manutenção.

6.11 Exercícios

6.11.1 Exercícios F

1. Explique a diferença entre emissário e interceptor.

2. Por que emissários longos exigem análise de transientes hidráulicos?

3. Cite três cuidados específicos no projeto de um emissário subaquático.

6.11.2 Exercícios M

1. Um emissário deve transportar 60 L/s. Se a velocidade de projeto desejada é 1,0 m/s, estime o diâmetro interno necessário.

2. Para o mesmo emissário do item anterior, com comprimento de 1 200 m, desnível geométrico de 10 m, perdas localizadas de 1,8 m, fator de atrito $f = 0{,}022$ e diâmetro interno adotado de 280 mm, calcule a altura manométrica total.

3. Considerando o resultado do item anterior, estime a pressão equivalente em metros de coluna d'água e interprete o nível de solicitação da tubulação.

6.11.3 Exercícios D

1. Uma cidade litorânea pretende lançar efluente tratado por emissário subaquático. Discuta os fatores que devem ser avaliados antes da definição do ponto de lançamento.

2. Compare os materiais PEAD, aço e ferro dúctil para uso em emissário pressurizado, destacando vantagens, limitações e situações de aplicação.

3. Um emissário terrestre mostrou vibração e variações de pressão após partidas e paradas da bomba. Proponha um diagnóstico técnico inicial e indique medidas corretivas de projeto e operação.

6.12 Gabarito comentado

Gabarito comentado — Respostas comentadas

Exercícios F

1. **Resposta esperada:** o interceptor coleta vazões ao longo do percurso e conduz para tratamento ou afastamento; o emissário, em geral, não recebe contribuições intermediárias e faz o transporte final até o ponto de descarga. A diferença principal é funcional e de papel na malha de esgoto.

2. **Resposta esperada:** porque paradas bruscas, fechamento de válvulas e variações rápidas de vazão podem gerar sobrepressões e depressões significativas, capazes de danificar a tubulação, deslocar juntas ou comprometer o funcionamento da linha.

3. **Resposta esperada:** três entre: estudo de correntes e batimetria; lastreamento e ancoragem; concepção do difusor; proteção contra flutuabilidade; avaliação da sensibilidade ambiental; inspeção e manutenção especializada; distância de áreas sensíveis.

Exercícios M

1. **Cálculo:**

$$A = \frac{Q}{V} = \frac{0{,}060}{1{,}0} = 0{,}06\,\text{m}^2$$

$$D = \sqrt{\frac{4A}{\pi}} = \sqrt{\frac{4 \times 0{,}06}{\pi}}$$

$$D \approx 0{,}276\,\text{m}$$

Resposta final: o diâmetro interno necessário é de aproximadamente 276 mm; comercialmente, uma solução próxima seria 280 mm ou 315 mm, conforme disponibilidade e verificação de perdas.

2. **Cálculo:**

Para $D = 0{,}28$ m:

$$V = \frac{0{,}060}{\pi \times 0{,}28^2/4}$$

$$V \approx 0{,}98\,\text{m/s}$$

Agora, a perda distribuída:

$$H_f = 0{,}022 \times \frac{1200}{0{,}28} \times \frac{0{,}98^2}{2 \times 9{,}81}$$

$$H_f \approx 2{,}33\,\text{m}$$

Altura manométrica total:

$$H_{MT} = 10 + 2{,}33 + 1{,}8$$

$$H_{MT} \approx 14{,}13\,\text{m}$$

Resposta final: a altura manométrica total é aproximadamente 14,1 m.

3. **Resposta esperada:** a pressão equivalente é cerca de 14,1 m de coluna d'água, ou aproximadamente 1,4 bar. Trata-se de uma solicitação moderada, mas o projetista ainda deve verificar transientes, resistência das juntas e margem de segurança da classe do tubo.

Exercícios D

1. **Resposta esperada:** devem ser avaliados profundidade local, correntes, batimetria, sedimentos, sensibilidade ecológica, distância a praias, captações e áreas de uso recreativo, além da geometria do difusor e da facilidade de manutenção. O ponto de lançamento deve favorecer mistura inicial e minimizar impactos localizados.

2. **Resposta esperada:** PEAD oferece flexibilidade, soldagem confiável e boa resistência química, sendo muito usado em travessias e subaquáticos. O aço oferece grande resistência mecânica, mas requer proteção anticorrosiva rigorosa. O ferro dúctil combina robustez e disponibilidade, porém também exige proteção contra corrosão e análise cuidadosa de juntas. A resposta correta é a que relaciona material com contexto de instalação e pressão.

3. **Resposta esperada:** o diagnóstico inicial deve investigar golpe de aríete, ar aprisionado, válvulas defeituosas, variação abrupta de operação, diâmetro inadequado e ausência de dispositivos de proteção. Medidas corretivas podem incluir ventosas, válvula de alívio, ajuste da rampa de partida e parada da bomba, revisão da classe de pressão, aumento de diâmetro ou reconfiguração da linha.

6.13 Conexão com o próximo capítulo

Observação — Ponte para o Capítulo 7

Os emissários fecham o ciclo de afastamento do esgoto, seja por terra, seja sob a água, e mostram como o sistema depende de materiais, pressão, proteção e desempenho ambiental. No próximo capítulo, o foco passa para a rotina do sistema já implantado: operação, manutenção, limpeza, inspeção, reabilitação e controle de anomalias. É ali que a qualidade do projeto se revela, na prática, ao longo do tempo.

Parte III

Operação, manutenção e reabilitação

Capítulo 7

Operação, manutenção e reabilitação de redes de esgoto

7.1 Objetivos de aprendizagem

Ao final deste capítulo, o leitor deverá ser capaz de:

- compreender a diferença entre projetar, operar, manter e reabilitar uma rede de esgoto;
- identificar os principais modos de falha em redes coletoras e seus componentes associados;
- reconhecer rotinas de inspeção, limpeza, desobstrução e controle operacional;
- interpretar causas de infiltração, contribuições indevidas, deposição de sólidos, corrosão e extravasamentos;
- relacionar segurança em espaços confinados com a operação de poços de visita, caixas e elevatórias;
- selecionar, em nível preliminar, estratégias de reabilitação para redes degradadas [1, 5, 4].

Observação — Papel deste capítulo no livro

Este é o capítulo de fechamento técnico do percurso. Depois de compreender a geração de esgoto, o traçado da rede, os elementos de interface, as soluções descentralizadas, as estações elevatórias e os emissários, o leitor precisa agora enxergar o sistema ao longo do tempo. Uma rede de esgoto não termina quando é construída: ela começa a existir de fato quando passa a ser operada, mantida e monitorada.

7.2 Operação, manutenção e reabilitação: diferenças essenciais

7.2.1 Operação

Operação é o conjunto de ações contínuas que mantém o sistema funcionando conforme o projeto e dentro dos limites de segurança e desempenho esperados. Em redes de esgoto, isso inclui acompanhar vazões, níveis, odores, extravasamentos, obstruções, funcionamento de elevatórias e integridade dos elementos de acesso.

Definição — Operação

É o conjunto de práticas de funcionamento cotidiano e controle funcional de um sistema de esgotamento sanitário, visando assegurar continuidade, segurança, eficiência hidráulica e proteção sanitária.

7.2.2 Manutenção

Manutenção é o conjunto de intervenções planejadas ou corretivas destinadas a preservar ou restabelecer a condição de funcionamento dos componentes do sistema.

Definição — Manutenção

É a ação técnica que busca conservar, corrigir ou recuperar a capacidade de desempenho de componentes da rede, reduzindo falhas, obstruções, vazamentos e perdas de eficiência.

7.2.3 Reabilitação

Reabilitação é a intervenção mais ampla, normalmente aplicada quando a rede apresenta deterioração estrutural, hidráulica ou sanitária significativa. Pode envolver reparos localizados, substituição de trechos, técnicas não destrutivas, reforço estrutural ou reorganização funcional da rede.

Definição — Reabilitação

É o conjunto de obras e técnicas destinadas a recuperar parcial ou totalmente a capacidade operacional, estrutural e sanitária de uma rede de esgoto degradada.

Atenção — Erro de percepção comum

Operação, manutenção e reabilitação não são sinônimos. Operar é manter o sistema em funcionamento; manter é intervir para preservar ou corrigir; reabilitar é recuperar uma rede já comprometida. Misturar esses conceitos leva a planos de gestão confusos e decisões ineficientes.

7.3 Desempenho de redes de esgoto ao longo do tempo

7.3.1 Por que as redes se degradam

Uma rede coletora sofre envelhecimento natural e também agressões externas. Entre as causas mais comuns de degradação estão:

- abrasão por sólidos transportados;
- corrosão química, especialmente em ambientes com sulfeto de hidrogênio;
- infiltração de água subterrânea;
- entrada de águas pluviais por conexões indevidas;
- movimentações do solo e recalques diferenciais;
- cargas excessivas de tráfego;
- defeitos construtivos;
- obstruções por gordura, areia, panos, raízes ou detritos;
- falhas de inspeção e de manutenção preventiva [1, 5].

7.3.2 Indicadores de desempenho

Para avaliar uma rede, o operador ou gestor pode acompanhar indicadores como:

- número de obstruções por quilômetro por ano;
- frequência de extravasamentos;
- volume de infiltração estimado;
- número de chamados operacionais;
- tempo médio de resposta;
- trechos com maior recorrência de falhas;
- custo de manutenção por extensão de rede;
- reincidência de intervenções no mesmo ponto.

Observação — Gestão orientada por dados

Uma boa operação não se apoia apenas em reação a falhas. Ela depende de registro, análise de tendências e priorização. Sem dados históricos, o sistema vira uma sucessão de emergências sem aprendizado institucional.

7.4 Principais problemas operacionais

7.4.1 Obstruções e deposição de sólidos

A obstrução é um dos problemas mais frequentes em redes de esgoto. Ela pode ser provocada por:

- baixa velocidade de escoamento;
- declividade insuficiente;
- depósitos de gordura;
- areia e material inerte;
- descarte inadequado de sólidos pelo usuário;
- raízes intrusas;
- deformações ou descontinuidades na tubulação.

Atenção — Velocidade baixa

Quando a velocidade do escoamento fica abaixo do necessário para arrastar partículas sedimentáveis, o coletor passa a acumular material. A consequência é gradual: primeiro surgem depósitos, depois redução de seção útil, aumento de perda de carga e, por fim, obstrução ou extravasamento.

7.4.2 Infiltração e contribuições indevidas

A infiltração de água subterrânea e as contribuições indevidas de águas pluviais aumentam a vazão transportada sem benefício sanitário. Isso pode:

- sobrecarregar tubulações e elevatórias;
- elevar o volume a tratar;
- gerar extravasamentos em tempo de chuva;
- mascarar problemas de estanqueidade;
- aumentar custo de energia e operação.

7.4.3 Corrosão e agressividade química

A corrosão é especialmente importante em trechos com baixa ventilação, tempo de detenção elevado e presença de material orgânico em decomposição. O sulfeto de hidrogênio pode ser oxidado e produzir ácido sulfúrico em superfícies internas, atacando concretos e metais.

Observação — Ambiente agressivo

Trechos sujeitos a septicidade, poços mal ventilados, coletores com baixo fluxo e câmaras pouco ventiladas são mais propensos à geração de gases corrosivos. O problema é químico, mas também hidráulico e operacional.

7.4.4 Raízes e interferência vegetal

A intrusão de raízes ocorre quando a vegetação encontra pontos de umidade, juntas defeituosas ou fissuras. As raízes podem:

- ampliar rachaduras;
- reduzir a seção útil;
- reter sólidos;
- dificultar a limpeza mecânica;
- provocar recidiva de obstruções.

7.4.5 Recalques e danos estruturais

Movimentações do solo, cargas excessivas ou assentamentos inadequados podem provocar:

- deslocamento de tubos;
- fissuras;
- inversão de declividade em trechos curtos;
- deformações permanentes;
- rupturas em juntas;
- infiltração e exfiltração.

7.4.6 Extravasamentos

Extravasamentos são eventos críticos do ponto de vista sanitário e ambiental. Podem decorrer de:

- obstruções;
- chuvas intensas e ligações indevidas;
- falhas de elevatórias;
- colapso estrutural;

- subdimensionamento original;
- operações inadequadas.

Atenção — Extravasamento não é apenas desconforto

Um extravasamento representa risco sanitário, ambiental e reputacional. Ele pode contaminar solo, águas superficiais, galerias pluviais e áreas de circulação pública. Em gestão de saneamento, extravasamento é evento prioritário de resposta.

7.5 Rotinas de inspeção

7.5.1 Inspeção visual

A inspeção visual é o primeiro nível de verificação operacional. Envolve observação de:

- presença de vazamentos;
- odores anormais;
- sinais de refluxo;
- tampas quebradas ou mal assentadas;
- afundamentos no pavimento;
- umidade recorrente em pontos específicos;
- marcas de transbordamento.

7.5.2 Inspeção cadastral

A rede deve ser acompanhada por cadastro técnico atualizado, contendo:

- posição dos poços de visita;
- cotas de fundo;
- diâmetros;
- materiais;
- profundidades;
- pontos de conexão;
- intervenções realizadas;
- histórico de falhas.

Observação — Cadastro técnico e memória operacional

Sem cadastro confiável, o operador não consegue localizar problemas com precisão nem priorizar a manutenção. Um bom banco de dados da rede é um ativo operacional, não um detalhe administrativo.

7.5.3 Inspeção por câmera

A inspeção por circuito fechado de TV, ou inspeção interna por câmera, permite avaliar o interior da tubulação sem escavação. É útil para identificar:

- fissuras;
- deslocamentos;
- infiltração;
- intrusão de raízes;
- depósitos;
- deformações;
- conexões irregulares;
- corrosão interna.

Atenção — Escolha do método de inspeção

Nem todo trecho exige câmera, mas trechos críticos, históricos de falha ou de grande importância operacional justificam inspeção mais sofisticada. A escolha deve equilibrar custo, urgência e criticidade.

7.5.4 Ensaios complementares

Dependendo do problema, podem ser usados:

- testes de fumaça;
- testes de corante;
- ensaios de estanqueidade;
- monitoramento de nível e vazão;
- acompanhamento de extravasamentos em chuva;
- verificação de odores e gases.

7.6 Limpeza e desobstrução

7.6.1 Métodos usuais

As principais técnicas de limpeza de redes de esgoto são:

- **hidrojateamento**: uso de jato de água pressurizada para remover depósitos;
- **desobstrução mecânica**: emprego de cabos, hastes ou equipamentos de corte;
- **aspiração**: remoção de material solto ou sedimentado;
- **limpeza preventiva programada**: intervenção periódica para evitar formação de obstruções.

Observação — Limpeza não resolve causa estrutural

Limpar um trecho obstruído é necessário, mas não suficiente, se a causa raiz continuar presente. Declividade inadequada, entrada de areia, defeito estrutural ou ligações indevidas exigem correção permanente.

7.6.2 Hidrojateamento

O hidrojateamento é muito eficiente para remover:

- gordura;
- areia leve;
- biofilme;
- incrustações superficiais;
- resíduos aderidos.

Entretanto, seu uso exige cuidado em trechos muito frágeis ou com juntas comprometidas.

7.6.3 Programação de limpeza

A programação deve ser baseada em criticidade, histórico e comportamento hidráulico. Em geral, merecem limpeza mais frequente:

- trechos com baixa declividade;
- pontos de mudança de direção;
- regiões com depósitos recorrentes;
- áreas com gordura elevada;
- redes antigas;
- trechos sujeitos a areia ou intrusão vegetal.

7.7 Controle de infiltração e contribuições indevidas

7.7.1 Como identificar o problema

A identificação pode vir de:

- aumento de vazão em tempo chuvoso;
- elevação de nível em poços de visita;
- entrada de água clara em inspeções;
- vazões noturnas anormalmente altas;
- recorrência em certos bairros ou trechos;
- correspondência com lençol freático ou redes pluviais próximas.

7.7.2 Medidas de controle

As medidas incluem:

- reparo de juntas e conexões;
- selagem de poços de visita;
- eliminação de ligações pluviais indevidas;
- revisão de tampas e tampões;
- reabilitação de trechos fissurados;
- fiscalização e orientação aos usuários;
- setorização e monitoramento hidráulico.

Atenção — Contribuição indevida é perda sistêmica

Quando águas pluviais entram na rede de esgoto, todo o sistema paga a conta: a estação elevatória trabalha mais, o emissário carrega mais volume, o tratamento recebe carga diluída e a rede sofre com picos desnecessários.

7.8 Segurança em operação e manutenção

7.8.1 Espaços confinados

Poços de visita, caixas e certas câmaras podem se comportar como espaços confinados. Os riscos mais importantes são:

- deficiência de oxigênio;

- presença de gases tóxicos;
- atmosfera explosiva;
- afogamento;
- soterramento;
- queda;
- contato com agentes biológicos.

7.8.2 Princípios básicos de segurança

A entrada em espaços confinados deve observar:

- avaliação prévia da atmosfera;
- ventilação adequada;
- bloqueio e sinalização da área;
- uso de EPI e EPC;
- equipe treinada;
- plano de resgate;
- autorização formal, quando aplicável.

Observação — Segurança é requisito de projeto

Não basta treinar a equipe depois. O projeto precisa facilitar o acesso seguro, prever ventilação, dimensionar tampas e passagens e reduzir a necessidade de entrada frequente em locais de alto risco.

7.9 Reabilitação de redes degradadas

7.9.1 Quando reabilitar

A reabilitação deve ser considerada quando a rede apresenta:

- obstruções recorrentes;
- infiltração elevada;
- falhas estruturais;
- recalques e deformações;
- intrusão de raízes persistente;

- insuficiência hidráulica;
- custo de manutenção crescente;
- risco sanitário elevado.

7.9.2 Estratégias de reabilitação

As principais estratégias são:

- **reparo localizado**: correção pontual de falhas ou juntas;
- **substituição de trecho**: remoção e instalação de novo segmento;
- **reforma interna**: recuperação do interior da tubulação;
- **revestimento ou relining**: inserção de nova camada estrutural ou estanque;
- **reabilitação sem vala**: métodos não destrutivos para reduzir escavação;
- **reconfiguração funcional**: alteração de traçado, setorização ou pontos de coleta.

Definição — Reabilitação sem vala

É o conjunto de técnicas aplicadas para recuperar ou substituir tubulações com mínima abertura de vala, reduzindo impacto urbano, tempo de obra e interferências na superfície.

7.9.3 Escolha da estratégia

A escolha depende de:

- tipo e extensão do dano;
- profundidade da rede;
- interferências urbanas;
- custo comparativo;
- urgência de restabelecimento;
- disponibilidade de acesso;
- vida útil desejada após intervenção.

Atenção — Reabilitação não é remendo aleatório

A intervenção deve resolver a causa do problema. Se a rede falha por recalque, infiltração ou geometria inadequada, um reparo superficial pode ter efeito temporário apenas. A reabilitação boa é aquela que combina solução local e correção da causa raiz.

7.9.4 Técnicas comuns

Entre as técnicas mais usuais estão:

- relining com tubos flexíveis ou estruturados;
- inserção de nova tubulação interna;
- cura localizada de juntas;
- selagem de infiltrações;
- rompimento e substituição dirigida em trechos específicos;
- reconstrução de poços de visita;
- melhoria de acessos e pontos de inspeção.

7.10 Gestão operacional integrada

7.10.1 Planejamento preventivo

Uma rede bem gerida deve ter plano preventivo com:

- cronograma de inspeção;
- limpeza programada;
- priorização de trechos críticos;
- acompanhamento de histórico de falhas;
- revisão de cadastro;
- plano de resposta a extravasamentos;
- comunicação com a população;
- integração com a operação de elevatórias e tratamento.

7.10.2 Resposta a ocorrências

Quando surge uma falha, a resposta deve seguir uma lógica clara:

1. identificar o local e a gravidade;
2. isolar o risco sanitário, quando necessário;
3. diagnosticar a causa provável;
4. executar a correção emergencial;

5. registrar a ocorrência;
6. propor medida definitiva;
7. atualizar o cadastro e o plano de manutenção.

Observação — Ciclo de aprendizado

Toda ocorrência operacional deve gerar aprendizado. Se um problema acontece repetidamente, o sistema de gestão não está aprendendo, apenas apagando incêndios.

7.11 Exemplo resolvido

Exemplo — Diagnóstico e priorização de um trecho crítico

Considere um trecho de rede coletora que apresenta os seguintes sintomas ao longo de um semestre:

- três obstruções no mesmo intervalo;
- extravasamento em dias de chuva forte;
- presença recorrente de areia no poço de visita a jusante;
- odor intenso em tempo seco;
- aumento de vazão noturna sem correspondente crescimento populacional.

1. Diagnóstico preliminar

Os sinais sugerem a coexistência de pelo menos três problemas:

- entrada de água pluvial ou contribuição indevida;
- deposição de areia e material sedimentável;
- possível problema de estanqueidade ou de declividade local.

2. Hipóteses técnicas prioritárias

As hipóteses mais prováveis são:

- ligações pluviais irregulares ou infiltração forte;
- ponto de baixa velocidade ou contra-declividade;
- falha em poço de visita ou junta;
- ausência de limpeza programada suficiente.

3. Ações de curto prazo

- limpeza por hidrojateamento;
- inspeção por câmera;

- verificação cadastral da cota e da declividade;
- teste de fumaça ou corante para identificar ligações indevidas;
- revisão do poço de visita com areia acumulada.

4. Ações de médio prazo

- selagem de juntas ou reparo do trecho;
- correção de conexões irregulares;
- reabilitação do poço de visita;
- eventual substituição do segmento com inversão de declividade.

5. Conclusão

O caso não se resolve apenas com limpeza. A recorrência indica causa estrutural e hidráulica associada, exigindo diagnóstico completo e intervenção permanente.

7.12 Resumo do capítulo

Resumo — Ideias centrais

- Operação, manutenção e reabilitação são fases distintas do ciclo de vida da rede.
- As redes se degradam por ação hidráulica, química, estrutural e operacional.
- Os principais problemas incluem obstrução, infiltração, corrosão, raízes, recalques e extravasamentos.
- A inspeção pode ser visual, cadastral, por câmera ou por ensaios complementares.
- A limpeza deve ser programada e orientada por criticidade e histórico.
- A segurança em espaços confinados é requisito obrigatório de operação.
- Reabilitar significa recuperar desempenho, não apenas executar um reparo pontual.
- Gestão eficiente depende de cadastro, monitoramento, resposta rápida e aprendizado institucional.

7.13 Exercícios

7.13.1 Exercícios F

1. Diferencie operação, manutenção e reabilitação de redes de esgoto.
2. Cite quatro causas comuns de obstrução em coletores.

3. Por que a segurança em poços de visita é um tema central na operação de redes?

7.13.2 Exercícios M

1. Uma rede apresenta 8 obstruções em um ano ao longo de 4 km. Calcule a taxa de obstruções por quilômetro por ano.

2. Um trecho de rede recebe limpeza preventiva a cada 6 meses. Discuta, em termos operacionais, quando essa frequência poderia ser aumentada.

3. Em uma inspeção, verificou-se que um trecho sofre extravasamento sempre em dias chuvosos. Quais testes você executaria primeiro para distinguir entre infiltração e conexão pluvial indevida?

7.13.3 Exercícios D

1. Elabore um plano básico de manutenção preventiva para uma rede coletora urbana com trechos antigos, poços de visita frequentes e histórico de obstruções.

2. Uma cidade decide reabilitar um trecho de 600 m com alta infiltração e várias juntas defeituosas. Discuta os critérios para escolher entre reparo localizado, substituição de trecho e reabilitação sem vala.

3. Proponha um roteiro de resposta a extravasamento em via pública, desde a identificação do problema até o registro da solução definitiva.

7.14 Gabarito comentado

Gabarito comentado — Respostas comentadas

Exercícios F

1. **Resposta esperada:** operação é o funcionamento cotidiano e controle do sistema; manutenção é a ação técnica para conservar ou recuperar a capacidade de funcionamento; reabilitação é a intervenção mais profunda para recuperar redes degradadas. A resposta deve diferenciar nível, finalidade e extensão das intervenções.

2. **Resposta esperada:** entre as causas comuns estão baixa velocidade, declividade insuficiente, gordura, areia, raízes, descarte inadequado de sólidos e defeitos construtivos. O aluno não precisa listar todas, mas deve demonstrar compreensão da origem multifatorial.

3. **Resposta esperada:** porque poços de visita são espaços potencialmente confinados, com risco de gases tóxicos, deficiência de oxigênio, queda, afogamento e contaminação biológica. A operação segura depende de procedimentos e equipamentos específicos.

Exercícios M

1. **Cálculo:**

$$\frac{8}{4} = 2$$

Resposta final: a taxa é de 2 obstruções por quilômetro por ano.

2. **Resposta esperada:** a frequência deve ser aumentada quando houver histórico recorrente de obstruções, trechos com baixa declividade, presença de gordura, raízes, areia ou quando a limpeza semestral deixar depósitos residuais. Em áreas críticas, a periodicidade pode ser trimestral ou até menor, conforme a recorrência observada.

3. **Resposta esperada:** os primeiros testes podem incluir inspeção visual em período seco e chuvoso, fumaça, corante, medição de vazão noturna, verificação de infiltração em poços e comparação do comportamento hidráulico entre tempo seco e tempo chuvoso. A resposta deve diferenciar entrada por chuva externa e contribuição permanente por infiltração.

Exercícios D

1. **Resposta esperada:** o plano deve incluir priorização dos trechos antigos, limpeza programada de poços de visita, inspeções periódicas por câmera nos pontos críticos, controle de gordura, monitoramento de extravasamentos, atualização cadastral e resposta rápida a chamados. O aluno deve mostrar organização preventiva e não apenas corretiva.

2. **Resposta esperada:** o reparo localizado é indicado quando os defeitos são pontuais e restritos. A substituição de trecho é preferível quando os danos são extensos ou estruturais. A reabilitação sem vala torna-se atrativa quando há dificuldade de abertura de vala, interferência urbana intensa ou necessidade de reduzir impacto e tempo de obra. A resposta deve comparar custo, extensão do dano, profundidade e interferências.

3. **Resposta esperada:** o roteiro deve prever: identificação e isolamento do trecho; contenção sanitária; limpeza emergencial; diagnóstico por inspeção e cadastro; definição da causa; correção provisória; solução definitiva; teste pós-intervenção; registro técnico

e atualização do histórico. A resposta correta demonstra visão operacional e sanitária integrada.

7.15 Encerramento e conexão final

Observação — Síntese final do livro

Com este capítulo, fecha-se a trajetória técnica do livro: geração de esgoto, concepção de coletores, interfaces prediais, soluções condominiais e descentralizadas, estações elevatórias, emissários e, por fim, operação, manutenção e reabilitação. A lógica fundamental do saneamento aparece com clareza: um sistema só é bom quando consegue ser concebido, construído, operado e mantido de forma coerente ao longo do tempo.

Observação — Conexão com apêndices e uso prático

Se houver apêndices no projeto editorial, este é o ponto natural de transição para tabelas auxiliares, quadros de referência, sínteses normativas ou formulários de apoio. Caso não haja apêndices, o livro se encerra aqui com a bibliografia e com a base necessária para estudo, projeto e prática profissional em sistemas de esgotamento sanitário.

Apêndice A

Síntese de fórmulas e unidades de referência

A.1 Objetivo do apêndice

Este apêndice reúne, em forma compacta, as relações matemáticas e unidades mais úteis ao longo do livro. Ele não substitui a análise de projeto nem as prescrições normativas, mas funciona como apoio rápido para revisão, cálculo preliminar e conferência de consistência.

Observação — Uso didático

A intenção aqui não é criar uma tabela desconectada do texto, mas consolidar o encadeamento conceitual desenvolvido ao longo dos capítulos. A leitura deste apêndice faz mais sentido quando o leitor já percorreu os capítulos principais e deseja rever a estrutura geral do sistema.

A.2 Unidades mais usuais

A.3 Relações fundamentais

A.3.1 Geração de esgoto

$$Q_{\text{dom,med}} = \frac{P\,q\,C_r}{86400}$$

em que:

- P é a população de projeto;
- q é o consumo per capita de água;
- C_r é o coeficiente de retorno;
- 86400 é o número de segundos em um dia.

Tabela A.1: Unidades e grandezas recorrentes no livro

Grandeza	Unidade usual	Observação
População de projeto	hab	Base para estimativa de vazão doméstica.
Contribuição per capita	L/d	Volume diário por habitante.
Vazão	L/s ou m^3/s	Usar a unidade coerente com a etapa de cálculo.
Comprimento	m ou km	Atenção à coerência com as perdas de carga e cotas.
Diâmetro	mm ou m	Converter antes de aplicar fórmulas hidráulicas.
Declividade	adimensional, % ou m/m	Devem ser cuidadosamente convertidas.
Altura manométrica	m de coluna de água	Interpretação hidráulica direta.
Potência	W ou kW	A seleção comercial costuma usar potência nominal superior.

A vazão média total pode ser escrita por:

$$Q_{\text{med}} = Q_{\text{dom,med}} + Q_{\text{ind,med}} + Q_{\text{inf}}$$

A.3.2 Vazões de pico

$$Q_{\text{max,dia}} = K_1\, Q_{\text{med}}$$

$$Q_{\text{max,h}} = K_2\, Q_{\text{max,dia}}$$

ou, de forma equivalente,

$$Q_{\text{max,h}} = K_1\, K_2\, Q_{\text{med}}$$

A.3.3 Equação de Manning

$$Q = \frac{1}{n}\, A\, R^{2/3}\, S^{1/2}$$

com:

$$A = \frac{\pi D^2}{4} \qquad \text{e} \qquad R = \frac{D}{4}$$

para seção circular cheia.

A.3.4 Altura manométrica total

$$H_{MT} = H_g + H_f + H_l$$

com:

$$H_f = f\,\frac{L}{D}\,\frac{V^2}{2g}$$

e

$$H_l = \sum K\,\frac{V^2}{2g}$$

A.3.5 Potência hidráulica

$$P_h = \rho g Q H_{MT}$$

e a potência elétrica estimada:

$$P_e = \frac{P_h}{\eta}$$

A.3.6 Velocidade em tubulação

$$Q = AV$$

A.3.7 Área de disposição no solo

$$A = \frac{Q_e}{I_{adm}}$$

A.4 Leituras rápidas de interpretação

- Se a vazão cresce, a rede tende a exigir maior diâmetro ou maior capacidade de recalque.
- Se a declividade aumenta, a capacidade hidráulica também aumenta, mas o projeto deve verificar velocidade e erosão.
- Se o coeficiente de rugosidade aumenta, a capacidade do conduto diminui.
- Se a perda de carga aumenta, a potência de bombeamento também cresce.
- Se a infiltração aumenta, o sistema passa a transportar água indesejada, com impacto em custo e operação.

Atenção — Coerência dimensional

A maior parte dos erros em projetos preliminares não ocorre na fórmula, mas na unidade. Sempre verifique se a vazão está em m^3/s ou L/s, se o diâmetro está em metros e se a declividade é adimensional antes da substituição numérica.

Apêndice B

Parâmetros de referência para estudos preliminares

B.1 Finalidade do apêndice

Este apêndice apresenta faixas de referência utilizadas com frequência em estudos de concepção e pré-dimensionamento. Os valores não substituem dados locais, requisitos da concessionária nem as normas aplicáveis. Eles servem para organizar o raciocínio técnico e apoiar exercícios, exemplos e revisões rápidas.

Observação — Critério editorial

Em saneamento, valores típicos são úteis, mas nunca universais. O bom projeto não copia parâmetros sem contexto; ele escolhe valores compatíveis com a realidade local, com justificativa técnica e documentação consistente.

B.2 Parâmetros usuais de geração de esgoto

Tabela B.1: Parâmetros de geração de esgoto usados em estudos preliminares

Parâmetro	Faixa típica	Unidade	Comentário
Consumo per capita de água	100 L/d a 250 L/d	L/hab.d	Varia com clima, abastecimento e padrão de uso.
Coeficiente de retorno	0,6 a 0,9	–	Geralmente inferior a 1.
Coeficiente de máxima diária K_1	1,1 a 1,5	–	Depende da população e da regularidade do consumo.
Coeficiente de máxima horária K_2	1,2 a 2,5	–	Em pequenas populações, tende a ser mais elevado.
Infiltração média	conforme estudo local	L/s	Pode ser expressa por trecho, rede ou área.

B.3 Parâmetros hidráulicos e materiais

Tabela B.2: Faixas usuais de rugosidade e observações de uso

Material	Rugosidade de Manning n	Observação	Uso típico
PVC rígido	0,009 a 0,011	Tubo liso, bom desempenho hidráulico.	Redes urbanas de pequeno e médio porte.
PEAD	0,009 a 0,011	Leve, flexível e adequado a travessias.	Redes especiais, emissários e recalques.
PRFV	0,009 a 0,011	Boa resistência química.	Coletores e emissários de maior porte.
Concreto	0,011 a 0,013	Rugosidade maior e atenção à corrosão.	Grandes coletores e interceptores.
Cerâmica vitrificada	0,010 a 0,013	Boa resistência química.	Situações específicas e redes com exigências particulares.

B.4 Parâmetros operacionais de referência

Tabela B.3: Faixas indicativas para operação e manutenção

Parâmetro	Faixa indicativa	Unidade	Comentário
Velocidade de escoamento em rede	dependente do trecho	m/s	Deve evitar deposição e erosão.
Intervalo entre limpezas preventivas	de acordo com criticidade	meses	A frequência deve vir do histórico operacional.
Número de partidas de elevatória	conforme equipamento	h^{-1}	Deve respeitar a faixa recomendada do fabricante.
Volume útil de poço úmido	ajustado à vazão e operação	m^3	Deve evitar partidas excessivas e retenção prolongada.

B.5 Quadro de leitura técnica rápida

- **Se a rede obstrui com frequência**, verifique declividade, velocidade, ligações indevidas e necessidade de limpeza preventiva.
- **Se a vazão em tempo chuvoso cresce muito**, suspeite de infiltração e de contribuições pluviais indevidas.

- **Se a elevatória falha com frequência**, revise sensores, redundância, válvulas, energia e volume útil.
- **Se o emissário opera com pressão excessiva**, reavalie diâmetro, perdas de carga e transientes.
- **Se o sistema descentralizado perde eficiência**, revise lodo, disposição final e manutenção do tanque séptico.

Atenção — Parâmetros não são substitutos da norma

Valores de referência ajudam a começar. A decisão final deve sempre ser compatibilizada com a norma aplicável, o prestador de serviço, a topografia local, o tipo de solo, o cadastro existente e os dados reais de campo.

Apêndice C

Checklist de concepção e projeto

C.1 Uso do checklist

O objetivo deste apêndice é oferecer uma sequência de verificação para concepção e projeto de sistemas de esgotamento sanitário. Ele é particularmente útil em estudos preliminares, anteprojetos e revisões de consistência.

Observação — Método de conferência

O checklist não substitui a memória de cálculo. Ele serve para reduzir omissões, organizar a leitura e padronizar a checagem técnica antes da emissão do projeto.

C.2 Levantamento inicial

- Há dados topográficos confiáveis?
- A ocupação atual e futura foi estimada?
- Existe cadastro de infraestrutura enterrada?
- Há informações sobre lençol freático, solo e interferências?
- O sistema será convencional, condominial, descentralizado ou misto?
- A área possui exigências ambientais específicas?

C.3 Definição da vazão

- A população de projeto foi definida de forma coerente?
- O consumo per capita adotado tem justificativa?
- O coeficiente de retorno está documentado?

- Há vazões não domésticas identificadas?
- A infiltração foi considerada?
- Foram definidos coeficientes de pico compatíveis com a realidade local?

C.4 Rede coletora

- O traçado acompanha a topografia de forma racional?
- As declividades são compatíveis com a autolimpeza?
- Os diâmetros crescem progressivamente ao longo da rede?
- Os materiais foram escolhidos conforme ambiente e desempenho?
- Há pontos de inspeção em mudanças de direção, declividade ou diâmetro?
- A rede evita conflitos com drenagem, água, gás, energia e telecomunicações?

C.5 Interface predial

- Há distinção clara entre instalação predial, ramal e ligação?
- O imóvel pode se conectar por gravidade?
- A caixa de inspeção, se prevista, está em local acessível?
- A rede pública está compatível com a cota de saída do lote?
- Foram evitadas ligações cruzadas com águas pluviais?

C.6 Soluções especiais

- A solução condominial foi justificada tecnicamente?
- A necessidade de tanque séptico foi avaliada com critério?
- A disposição final no solo é compatível com a hidrogeologia local?
- A elevatória é realmente necessária ou existe alternativa gravitária?
- O emissário foi verificado quanto à pressão, perdas e transientes?

C.7 Operação futura

- Há acessibilidade para limpeza e inspeção?
- O cadastro técnico foi previsto?
- A estratégia de manutenção está definida?
- Foram consideradas redundância e contingência onde necessárias?
- Existe plano de resposta a extravasamentos e falhas?
- A solução é operável pela equipe disponível?

Atenção — Projeto bom é projeto operável

Uma solução tecnicamente bonita, mas impossível de manter, não é boa engenharia. O projeto deve nascer já pensando em acesso, limpeza, segurança, reposição e resposta a falhas.

Apêndice D

Checklist de operação, manutenção e reabilitação

D.1 Objetivo

Este apêndice organiza um roteiro prático para operação e manutenção de redes de esgoto, além de apoiar decisões iniciais de reabilitação.

Observação — Princípio de gestão

O sistema não deve ser administrado apenas por emergência. Operação eficiente se apoia em programação, registro e priorização. Isso vale tanto para redes simples quanto para sistemas com elevatórias e emissários.

D.2 Rotina de operação

- monitorar queixas e chamados;
- acompanhar níveis em PVs e elevatórias;
- verificar odores, refluxos e extravasamentos;
- observar variações incomuns de vazão;
- registrar chuva, falhas e ocorrências;
- atualizar o cadastro sempre que houver intervenção.

D.3 Rotina de manutenção preventiva

- limpar trechos críticos em periodicidade definida;
- inspecionar poços de visita e caixas;

- verificar tampas, anéis e selagens;
- testar bombas e sensores em elevatórias;
- avaliar pontos com histórico de obstrução;
- controlar areia, gordura e detritos;
- acompanhar trechos sujeitos a raízes e recalques;
- revisar áreas com contribuição indevida.

D.4 Rotina de inspeção

- inspeção visual de superfície;
- inspeção de acessos e tampas;
- inspeção interna com câmera nos pontos críticos;
- testes de fumaça ou corante quando houver suspeita de ligação indevida;
- acompanhamento de vazões noturnas e em chuva;
- verificação de estanqueidade em trechos suspeitos.

D.5 Sinais de alerta

- obstruções repetidas;
- extravasamento em tempo de chuva;
- odor persistente em trecho específico;
- recalque frequente em elevatória;
- presença de areia em excesso;
- afundamento do pavimento;
- vazão noturna acima do esperado;
- corrosão acelerada ou degradação estrutural.

D.6 Critérios para reabilitação

- o problema é pontual ou recorrente?

- existe causa estrutural ou apenas operacional?
- a rede ainda tem capacidade hidráulica suficiente?
- o custo de manutenção já se aproxima do custo de recuperação?
- a intervenção precisa ser rápida para reduzir risco sanitário?
- há restrição urbana para abertura de vala?

D.7 Estratégias possíveis

- reparo localizado;
- substituição de trecho;
- selagem de juntas;
- relining ou reabilitação sem vala;
- reconstrução de PVs e caixas;
- reconfiguração do traçado;
- reforço operacional com alteração de limpeza e inspeção.

Atenção — Causa raiz

Reabilitar sem entender a origem do problema pode apenas deslocar a falha no tempo. O diagnóstico deve vir antes da intervenção e a intervenção deve atacar a causa raiz.

D.8 Roteiro mínimo de resposta a ocorrência

1. Identificar e localizar a ocorrência.
2. Proteger o entorno e reduzir risco sanitário.
3. Diagnosticar a causa provável.
4. Executar a correção emergencial.
5. Registrar a intervenção.
6. Atualizar o histórico da rede.
7. Planejar a solução definitiva.

Apêndice E

Quadro de normas e referências de apoio

E.1 Uso deste quadro

Este quadro tem finalidade puramente orientativa. Ele resume o papel das referências normativas e bibliográficas mais recorrentes no conteúdo do livro. Não substitui a consulta integral às normas e aos documentos originais.

Observação — Boa prática

Antes de fechar um projeto, a leitura deve ser cruzada entre norma, memorial descritivo, especificação da concessionária e dados de campo. Nenhum desses elementos, isoladamente, resolve o problema inteiro.

E.2 Síntese de aplicação

E.3 Leituras recomendadas por tema

- **Geração de vazões**: Tsutiya e Alem Sobrinho; Jordão e Pessôa.
- **Redes coletoras**: ABNT NBR 9649; Tsutiya e Alem Sobrinho.
- **Soluções descentralizadas**: ABNT NBR 7229; ABNT NBR 13969; FUNASA.
- **Visão geral de saneamento**: Nuvolari; FUNASA.

Atenção — Consulta integral

Quadros sintéticos são úteis, mas não têm a mesma autoridade do texto original das normas e dos documentos técnicos. Sempre que o projeto exigir precisão normativa, a consulta deve ser feita ao documento completo e vigente.

Tabela E.1: Referências de apoio e sua aplicação geral no livro

Referência	Tema principal	Aplicação no livro
ABNT NBR 9649	Projeto de redes coletoras de esgoto sanitário	Base para traçado, dimensionamento e critérios de rede coletora.
ABNT NBR 7229	Tanques sépticos	Base para concepção de unidades sépticas e tratamento primário local.
ABNT NBR 13969	Unidades complementares e disposição final de efluentes	Base para tratamento complementar e disposição no solo.
TSUTIYA; ALEM SOBRINHO	Coleta e transporte de esgoto sanitário	Referência central para redes, colectores e afastamento.
JORDÃO; PESSÔA	Tratamento de esgotos domésticos	Apoio para visão integrada entre coleta e tratamento.
FUNASA	Manual de saneamento	Suporte prático para soluções sanitárias e condições de campo.
NUVOLARI	Esgoto sanitário	Consolidação conceitual e tecnológica do tema.

Referências Bibliográficas

[1] TSUTIYA, M. T.; ALEM SOBRINHO, P. (ed.). *Coleta e Transporte de Esgoto Sanitário*. 3. ed. São Paulo: POLI/USP, 2011.

[2] JORDÃO, E. P.; PESSÔA, C. A. *Tratamento de Esgotos Domésticos*. 7. ed. Rio de Janeiro: SEGRAC, 2014.

[3] ABNT. *NBR 9649: Projetos de Redes Coletoras de Esgoto Sanitário*. Rio de Janeiro: ABNT, 1986.

[4] NUVOLARI, A. (coord.). *Esgoto Sanitário*. São Paulo: Edgard Blücher, 2003.

[5] FUNASA. *Manual de Saneamento*. 4. ed. Brasília: FUNASA, 2015.

[6] ABNT. *NBR 7229: Projeto, construção e operação de sistemas de tanques sépticos*. Rio de Janeiro: ABNT.

[7] ABNT. *NBR 13969: Tanques sépticos – unidades de tratamento complementar e disposição final dos efluentes líquidos – projeto, construção e operação*. Rio de Janeiro: ABNT.